Bulletin d'estimation du risque d'avalanche

(valable en dehors des pistes balisées et ouvertes)

MASSIF : Mercantour

Rédigé le dimanche 22 mars 2026 à 16h

Estimation des risques pour le : LUNDI 23 MARS

NOMBREUSES PETITES PLAQUES DANS LA NEIGE FRAICHE VENTÉE - QUELQUES DÉPARTS AU SOLEIL

3

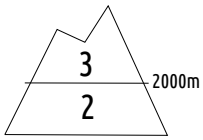

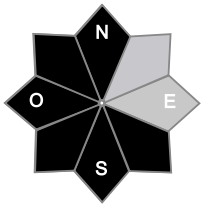

Au-dessus de 2000m indice de risque marqué, plus bas indice limité.

Départs spontanés : départs superficiels de neige fraiche s'humidifiant au soleil

Déclenchements provoqués : nombreuses petites plaques sensibles en altitude dans la neige fraîche ventée, notamment vers les crêtes.

Indices de risque : 5 très fort - 4 fort - 3 marqué - 2 limité - 1 faible -- En noir : les pentes les plus dangereuses

Stabilité du manteau neigeux

Situation avalancheuse typique : neige ventée neige humide

Déclenchements provoqués : nombreuses plaques superficielles dans la neige fraiches en lien avec le transport de neige par le vent de nord-est, possibles en toutes orientations, mais plus fréquentes dans un large versant nord-ouest à sud-est au-dessus de 2000 m. Plaques très faciles à déclencher au passage d'un skieur, présentes plutôt aux abords des crêtes et générant des avalanches de petite taille, rarement moyenne (taille 1 à 2).
En versant nord au-dessus de 2200 m environ, des départs un peu plus volumineux sont possibles au passage d'un skieur par déstabilisation d'une plaque plus ancienne et épaisse, restant généralement de taille moyenne (taille 2).

Départs spontanés : peu probable au levé du jour, puis départs superficiels de neige fraiche s'humidifiant au soleil, devenant fréquents au fil de la journée. Avalanches de petite taille, rarement moyenne (taille 1 à 2).

Qualité de la neige

Enneigement excédentaire dans la Roya, proche des normales sur le reste du massif.
Données observées : 170 cm à la Nivôse de Millefonts à 2430 m, 120 cm à Isola 2000 à 1912 m.

Enneigement skiable : vers 1400 m en ubacs, 1700/1800 m en adrets peu pentus.

État de la neige en surface : on retrouve le matin 10 à 15 cm de neige fraiche, travaillée par le vent de nord-est proche des crêtes, et s'humidifiant au soleil en journée. Elle repose en général sur un fond dure/regelé, excepté en ubacs au-dessus de 2000/2200 m environ, où la couche de neige légère peut être plus importante dans les combes abritées du vent.

Aperçu météo pour le lundi 23 mars

nuit	matin	après-midi	soir

Temps sec et ensoleillé le matin, quelques cumulus se développent l'après-midi.

Pluie-Neige				
Iso 0 °C	1 500 m	1 700 m	2 000 m	2 000 m
Vent 2000 m	↓ 30 km/h	↓ 20 km/h	↓ 25 km/h	↓ 25 km/h
Vent 3000 m	↙ 40 km/h	↙ 30 km/h	↓ 35 km/h	↓ 40 km/h

Épaisseur de neige hors-piste

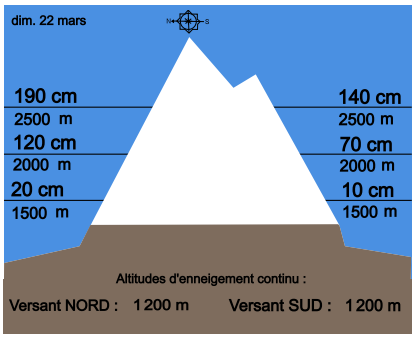

Précipitations à 1800 m

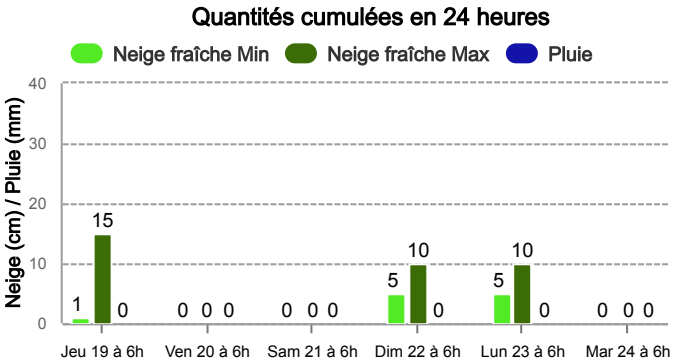

Tendance du mardi 24 mars

2

Indice de risque limité

Stabilisation rapide des plaques dans la neige fraîche au soleil, elles persistent un peu plus longtemps en versants ombragés.

Pour consulter la vigilance en cours, veuillez vous rendre sur le site https://vigilance.meteofrance.fr/fr

Météo-France - 73 avenue de Paris, 94165 Saint-Mandé cedex - Contact : contact@meteo.fr

Rédigé par Météo-France avec la contribution des observateurs du réseau nivo-météorologiques. Partenariat : ANMSM (Maires de Stations de Montagne), DSF (Domaines Skiables de France), ADSP (Directeurs de Pistes et de la Sécurité des Stations de Sports d'Hiver) et autres acteurs de la montagne.

Bulletin neige & avalanches par téléphone au 0 892 68 10 20 Service 0,35 € / min + prix appel

RÉPUBLIQUE FRANÇAISE
Liberté Égalité Fraternité

METEO FRANCE
À VOS CÔTÉS, DANS UN CLIMAT QUI CHANGE

Bulletin d'estimation du risque d'avalanche

(valable en dehors des pistes balisées et ouvertes)

MASSIF : Mercantour

Rédigé le dimanche 22 mars 2026 à 16h

Conditions nivo-météo des 7 derniers jours

	lun. 16/03				mar. 17/03				mer. 18/03				jeu. 19/03				ven. 20/03				sam. 21/03				dim. 22/03			
	03h	09h	15h	21h	03h	09h	15h	21h	03h	09h	15h	21h	03h	09h	15h	21h	03h	09h	15h	21h	03h	09h	15h	21h	03h	09h	15h	21h
Météo																												
Vent (km/h)	45	40	35	30	20	15	20	20	20	65	90	95	80	60	50	35	25	20	15	15	15	15	20	10	15	20	35	45
à 3000m																												
Vent (km/h)	35	30	25	15	15	15	15	15	15	45	65	70	70	50	35	30	20	20	15	10	5	10	15	5	5	10	25	30
à 2000m																												

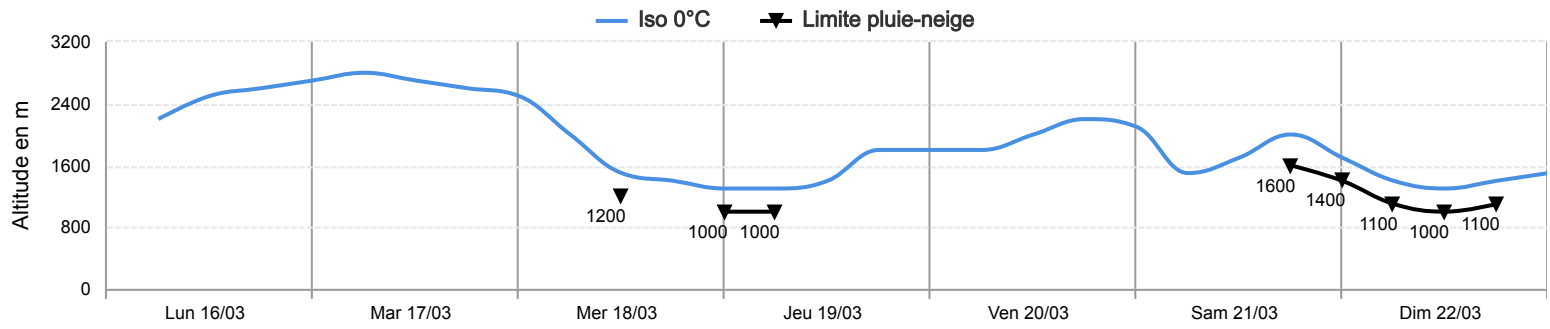

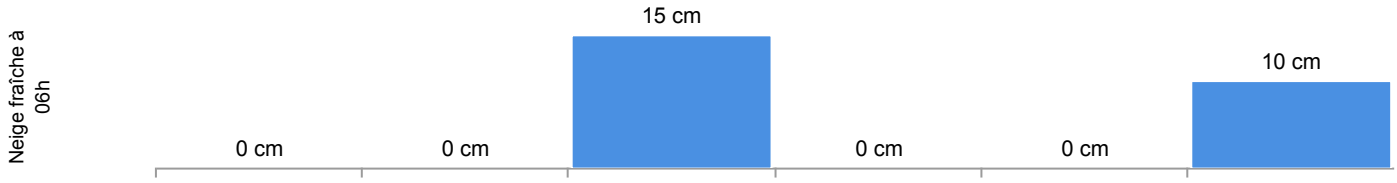

Risque d'avalanche	lun. 16/03	mar. 17/03	mer. 18/03	jeu. 19/03	ven. 20/03	sam. 21/03	dim. 22/03
	3	3	3	3	2	2	3

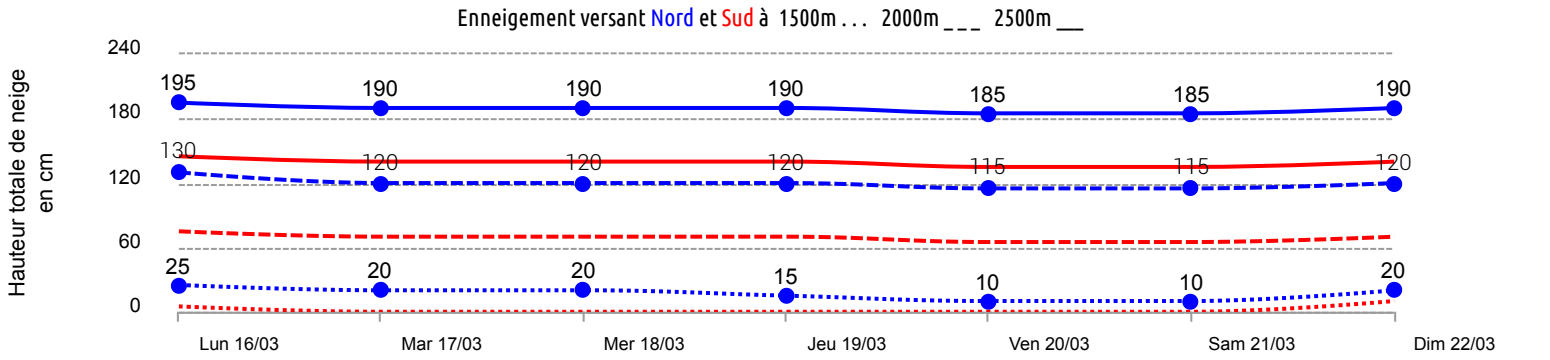

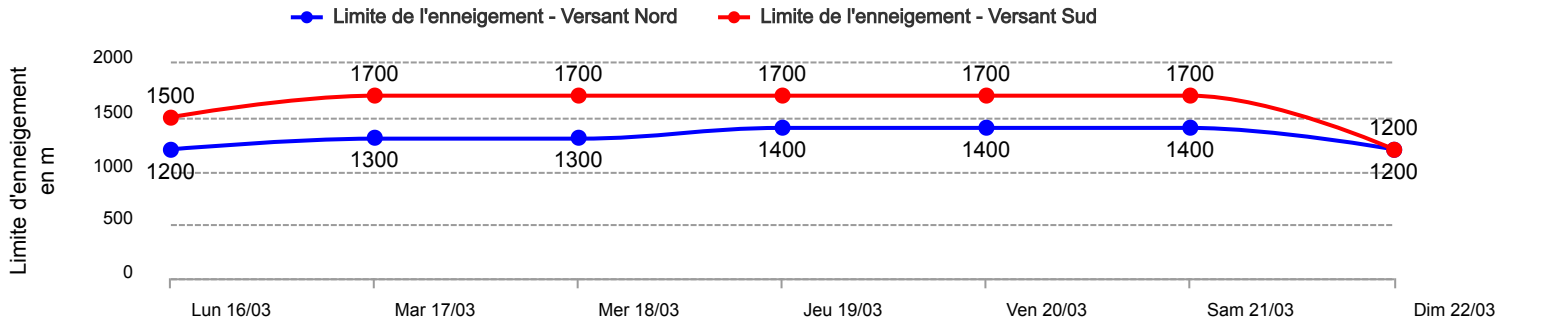

Pour consulter la vigilance en cours, veuillez vous rendre sur le site https://vigilance.meteofrance.fr/fr

Météo-France - 73 avenue de Paris, 94165 Saint-Mandé cedex - Contact : contact@meteo.fr

Rédigé par Météo-France avec la contribution des observateurs du réseau nivo-météorologiques. Partenariat : ANMSM (Maires de Stations de Montagne), DSF (Domaines Skiables de France), ADSP (Directeurs de Pistes et de la Sécurité des Stations de Sports d'Hiver) et autres acteurs de la montagne.

Bulletin neige & avalanches par téléphone au
0 892 68 10 20 Service 0,35 € / min + prix appel