Bulletin d'estimation du risque d'avalanche

(valable en dehors des pistes balisées et ouvertes)

MASSIF : Mont-Blanc

Rédigé le dimanche 22 mars 2026 à 16h

Estimation des risques pour le : LUNDI 23 MARS

NOMBREUSES PLAQUES À VENT EN HAUTE MONTAGNE, INSTABILITÉS ENCORE PRÉSENTES DANS LA NEIGE RÉCENTE PLUS BAS

3

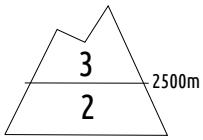

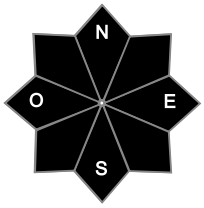

Au-dessus de 2500m indice de risque marqué, plus bas indice limité.

Départs spontanés : Départ en plaque à cause du transport de neige par le vent

Déclenchements provoqués : Nombreuses plaques à vent avec la rotation du vent de Sud-Ouest en vent de Nord-Est

Indices de risque : 5 très fort - 4 fort - 3 marqué - 2 limité - 1 faible -- En noir : les pentes les plus dangereuses

Stabilité du manteau neigeux

Situation avalancheuse typique : neige fraîche neige ventée

Déclenchements provoqués :

* Au-dessus de 2500 m : nombreuses plaques à vent formées sous le vent de SO/SE dimanche, de nouvelles plaques se forment sous le vent de NE lundi en journée. Elles sont d'aspect friable, voir dur plus en altitude, facilement déclenchables au passage d'un skieur. On les retrouve au voisinage des crêtes. Taille 1 à 2 (petite à moyenne).

Observables : accumulation de neige, vaguelettes, fissures sous les skis.

* Quelques instabilités dans la neige fraiche entre 2000 et 2500 m sont encore présentes. Elles sont plus nombreuses sous le vent de SO et SE, les plaques sont facilement déclenchables par un skieur. Taille 1 à 2 (petite à moyenne).
* Dans les adrets d'altitude et en ubacs au-dessus de 2100 m, une couche fragile persistante est encore enfouie, mais ne semble pas vraiment déclenchable par un skieur. Toutefois, par une forte surcharge (avalanche en cascade, chutes de corniches, chutes de séracs), elle pourrait être sollicitée et engendrer une avalanche de taille 2 à 3 (moyenne à grande).

Départs spontanés :

* Départs dans la neige récente à cause du vent de NE en journée. Taille 1 à 2.
* Sous 2000 m, quelques coulées de neige humide dans les versants ensoleillés au fil du réchauffement (secteur sans vent). Taille 1.
* Peu probable, plaques de fond, en tous versants, à toute heure du jour et de la nuit, dans les pentes lisses et raides (zones herbeuses, dalles, vires). Taille 1 à 2.

Qualité de la neige

Enneigement :

L'enneigement passe d'inexistant à relativement bon une fois la limite d'enneigement atteinte.

On peut chausser les skis vers 1200/1300 m en nord et 1400/1500 m en sud.

Grosses corniches présentes.

Qualité de la neige ce lundi :

* 5/10 cm de neige récente, ventée près des crêtes. Elle s'humidifie en surface dans les versants ensoleillés et reste froide à l'ombre. Elle repose sur un fond dur : croute en versant S/E/O et sur de la neige froide souvent cartonnée en Nord (ou de la vielle poudre dans les secteurs abrités en altitude).
* Plus haut en altitude, neige récente plus souvent travaillée par le vent. Dans les couloirs/secteurs encaissés, la neige reste légère. Plus on monte en altitude, plus la neige est dure.

Aperçu météo pour le lundi 23 mars

nuit	matin	après-midi	soir

Belles éclaircies, des nuages sur le relief en journée. Légère remontée de l'isotherme 0°C. Vent de nord-est.

Pluie-Neige				
Iso 0 °C	1 600 m	1 800 m	2 200 m	2 000 m
Vent 2000 m	20 km/h	30 km/h	25 km/h	20 km/h
Vent 4000 m	30 km/h	45 km/h	40 km/h	40 km/h

Épaisseur de neige hors-piste

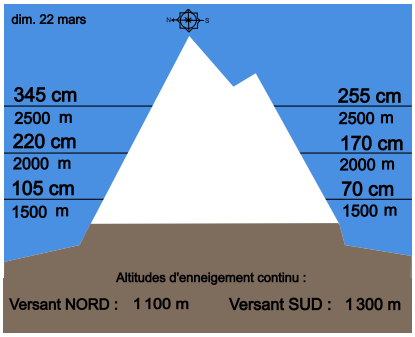

Précipitations à 1800 m

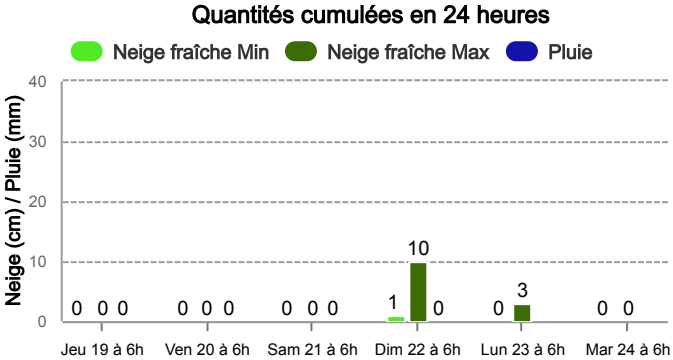

Tendance du mardi 24 mars

3 **Indice de risque marqué**

Les plaques formées sous le vent de nord-est sont encore bien présentes en altitude.

Pour consulter la vigilance en cours, veuillez vous rendre sur le site https://vigilance.meteofrance.fr/fr

Météo-France - 73 avenue de Paris, 94165 Saint-Mandé cedex - Contact : contact@meteo.fr

Rédigé par Météo-France avec la contribution des observateurs du réseau nivo-météorologiques. Partenariat : ANMSM (Maires de Stations de Montagne), DSF (Domaines Skiables de France), ADSP (Directeurs de Pistes et de la Sécurité des Stations de Sports d'Hiver) et autres acteurs de la montagne.

Bulletin neige & avalanches par téléphone au

0 892 68 10 20 Service 0,35 € / min + prix appel

RÉPUBLIQUE FRANÇAISE
Liberté Égalité Fraternité

METEO FRANCE
À VOS CÔTÉS, DANS UN CLIMAT QUI CHANGE

Bulletin d'estimation du risque d'avalanche

(valable en dehors des pistes balisées et ouvertes)

MASSIF : Mont-Blanc

Rédigé le dimanche 22 mars 2026 à 16h

Conditions nivo-météo des 7 derniers jours

	lun. 16/03				mar. 17/03				mer. 18/03				jeu. 19/03				ven. 20/03				sam. 21/03				dim. 22/03			
	03h	09h	15h	21h	03h	09h	15h	21h	03h	09h	15h	21h	03h	09h	15h	21h	03h	09h	15h	21h	03h	09h	15h	21h	03h	09h	15h	21h
Météo																												
Vent (km/h)	70	80	60	70	65	65	70	70	80	100	100	80	60	50	50	60	40	30	20	15	20	25	30	30	30	40	50	30
à 4000m																												
Vent (km/h)	10	20	15	20	20	20	25	20	15	40	80	40	20	30	10	20	5	5	15	10	10	10	10	10	15	25	30	20
à 2000m																												

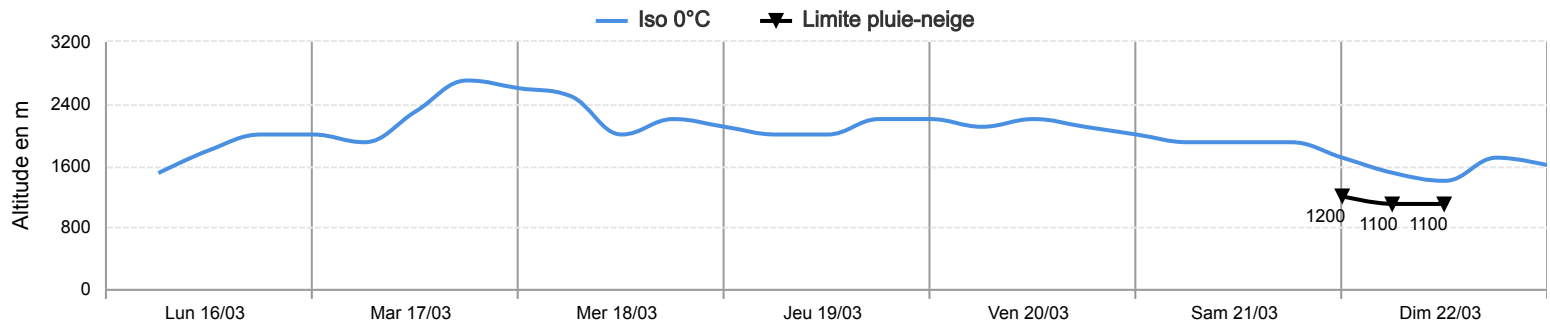

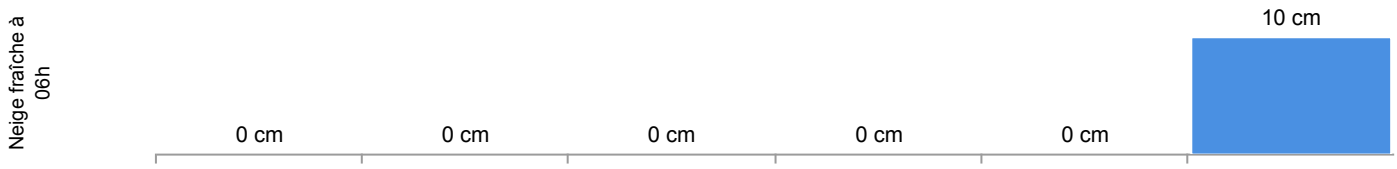

Risque d'avalanche	lun. 16/03	mar. 17/03	mer. 18/03	jeu. 19/03	ven. 20/03	sam. 21/03	dim. 22/03
	3	3	3	3	2	2	2

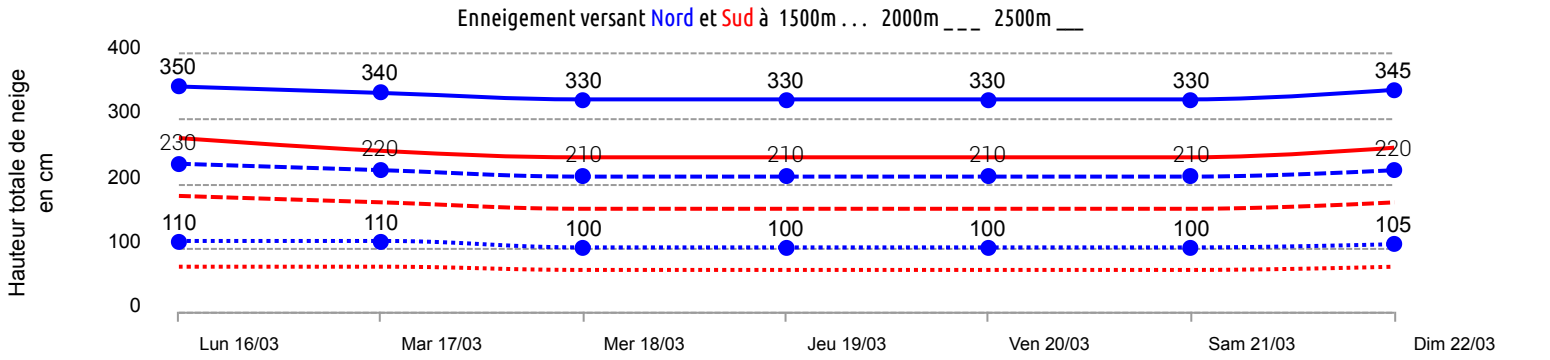

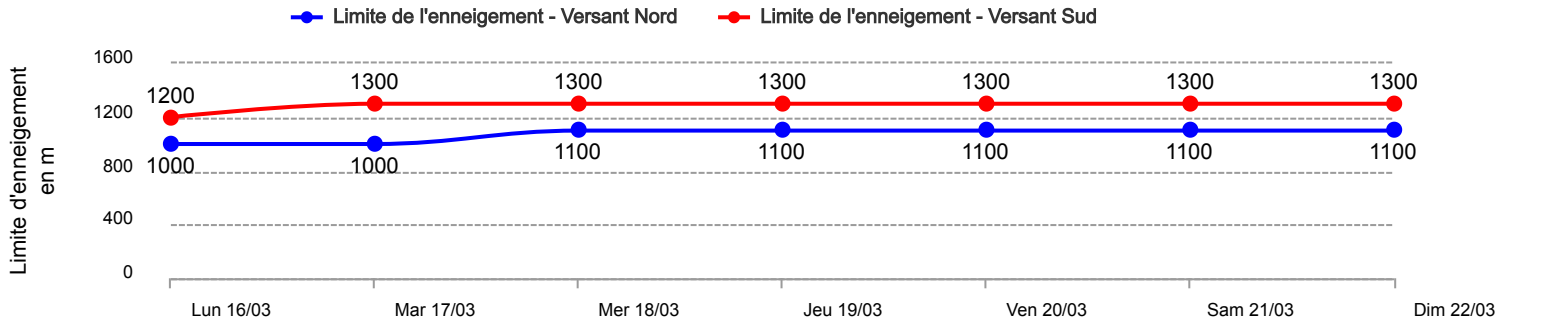

Pour consulter la vigilance en cours, veuillez vous rendre sur le site https://vigilance.meteofrance.fr/fr

Météo-France - 73 avenue de Paris, 94165 Saint-Mandé cedex - Contact : contact@meteo.fr

Rédigé par Météo-France avec la contribution des observateurs du réseau nivo-météorologiques. Partenariat : ANMSM (Maires de Stations de Montagne), DSF (Domaines Skiables de France), ADSP (Directeurs de Pistes et de la Sécurité des Stations de Sports d'Hiver) et autres acteurs de la montagne.

Bulletin neige & avalanches par téléphone au

0 892 68 10 20 Service 0,35 € / min + prix appel