Bulletin d'estimation du risque d'avalanche

(valable en dehors des pistes balisées et ouvertes)

MASSIF : Queyras

Rédigé le dimanche 22 mars 2026 à 16h

Estimation des risques pour le : LUNDI 23 MARS

PLAQUES EN PLACE LOCALEMENT ÉPAISSES DANS LA NEIGE RÉCENTE, UN PEU D'ACTIVITÉ NATURELLE AU SOLEIL

3

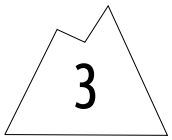

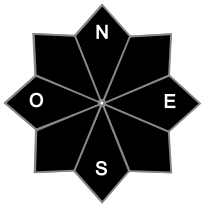

Indice de risque marqué.

Départs spontanés : départs ponctuels en neige humide au soleil. Taille 1 à 2.

Déclenchements provoqués : plaques à vent en place dans la neige récente, parfois épaisses

Indices de risque : 5 très fort - 4 fort - 3 marqué - 2 limité - 1 faible -- En noir : les pentes les plus dangereuses

Stabilité du manteau neigeux

Situation avalancheuse typique : neige fraîche neige ventée

Déclenchements provoqués : plaques en place dans la neige fraîche tombée ce dimanche et entretenues par une petite Lombarde qui transporte la neige récente jusqu'à lundi matin. Présentes dans toutes les orientations, ce plaques localement épaisses restent facilement déclenchables. Elles peuvent générer des avalanches de taille moyenne (taille 2) en général, voire grande (taille 3) dans un couloir chargé. Dans le secteur de Ceillac où les épaisseurs de fraîche avoisinent 40/50 cm, un départ peut mobiliser un volume de neige plus conséquent.

Départs spontanés : en journée, quelques départs sont attendus avec le soleil et le redoux qui viennent déstabiliser la neige récente. Avalanches de taille petite ou moyenne (taille 1 à 2).

Qualité de la neige

L'enneigement est proche des normales pour une mi-mars.
Hauteurs de neige observées : 160 cm en versant nord du col Izoard à 2300 m, 159 cm au-dessus de St Véran à 2700 m, 113 cm à la Nivôse du Col Agnel à 2630 m, 63 cm à Ristolas à 1670 m.

Limite d'enneigement skiable : au plus bas à 1600 m en ubacs bien protégés ou sur pistes forestières, plutôt 2000 m en adrets.

État de la neige de surface : on retrouve en surface 10/15 cm de neige froide, localement 20/40 cm secteur Ceillac/St Véran/Col Agnel, qui repose sur un manteau neigeux printanier bien dense en sud. En large versant nord au-dessus de 2200/2300 m, elle repose sur une neige plus sèche, travaillée par le vent ou encore d'aspect poudreux.

Aperçu météo pour le lundi 23 mars

nuit	matin	après-midi	soir

Retour du soleil dans une ambiance plus douce : +5°C à 2000 m et -5° à 3000 m.

Pluie-Neige				
Iso 0 °C	1 400 m	1 500 m	2 000 m	2 100 m
Vent 2000 m	20 km/h	15 km/h	20 km/h	10 km/h
Vent 3000 m	25 km/h	20 km/h	20 km/h	15 km/h

Épaisseur de neige hors-piste

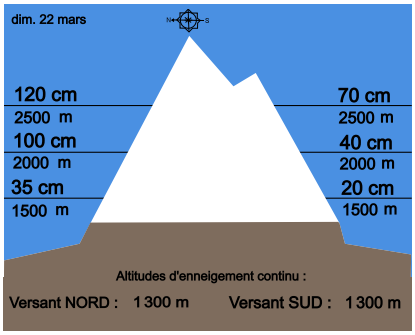

Précipitations à 1800 m

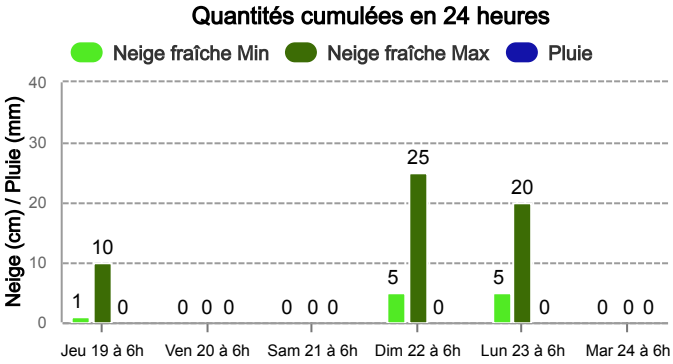

Tendance du mardi 24 mars

2

Indice de risque limité

Passage probable en risque limité. Avec la poursuite d'un temps sec et doux, le manteau neigeux se stabilise progressivement.

Pour consulter la vigilance en cours, veuillez vous rendre sur le site https://vigilance.meteofrance.fr/fr

Météo-France - 73 avenue de Paris, 94165 Saint-Mandé cedex - Contact : contact@meteo.fr

Rédigé par Météo-France avec la contribution des observateurs du réseau nivo-météorologiques. Partenariat : ANMSM (Maires de Stations de Montagne), DSF (Domaines Skiables de France), ADSP (Directeurs de Pistes et de la Sécurité des Stations de Sports d'Hiver) et autres acteurs de la montagne.

Bulletin neige & avalanches par téléphone au
0 892 68 10 20 Service 0,35 € / min + prix appel

RÉPUBLIQUE FRANÇAISE
Liberté Égalité Fraternité

METEO FRANCE
À VOS CÔTÉS, DANS UN CLIMAT QUI CHANGE

Bulletin d'estimation du risque d'avalanche
(valable en dehors des pistes balisées et ouvertes)

MASSIF : Queyras

Rédigé le dimanche 22 mars 2026 à 16h

Conditions nivo-météo des 7 derniers jours

	lun. 16/03				mar. 17/03				mer. 18/03				jeu. 19/03				ven. 20/03				sam. 21/03				dim. 22/03			
	03h	09h	15h	21h	03h	09h	15h	21h	03h	09h	15h	21h	03h	09h	15h	21h	03h	09h	15h	21h	03h	09h	15h	21h	03h	09h	15h	21h
Météo																												
Vent (km/h)	20	30	30	25	25	15	20	15	20	40	70	70	55	35	30	25	20	15	5	10	15	15	15	15	20	30	40	35
à 3000m	↓	↘	↘	↘	↘	↘	↘	↘	↘	←	←	←	←	←	←	←	↙	↙	→	↘	↘	↘	↘	→	→	←	←	←
Vent (km/h)	10	20	30	15	10	10	15	10	10	30	40	30	25	20	20	15	15	10	15	5	5	10	15	10	15	25	30	30
à 2000m	↙	↙	↓	↓	↓	↓	→	↓	↻	↙	↙	←	↙	←	↙	←	←	↖	↑	↓	↗	↗	↗	↑	←	←	↙	↙

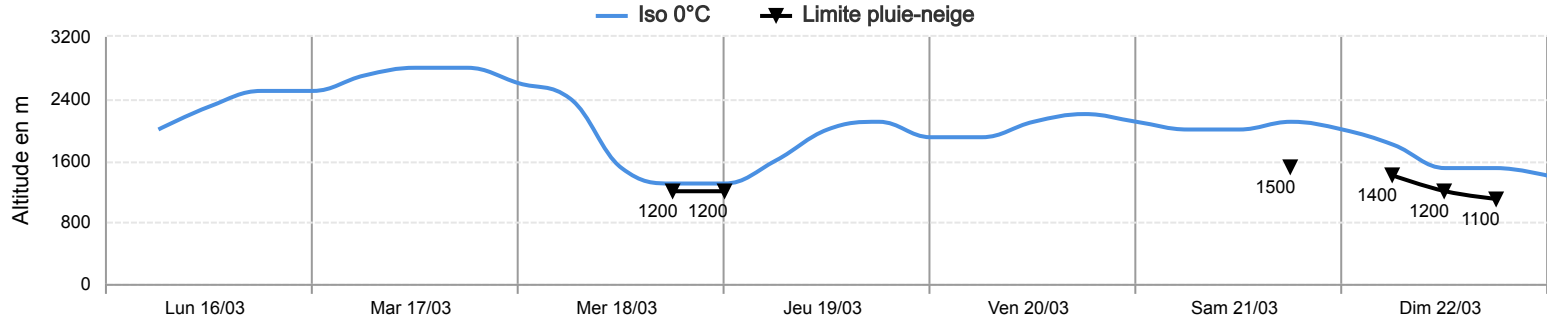

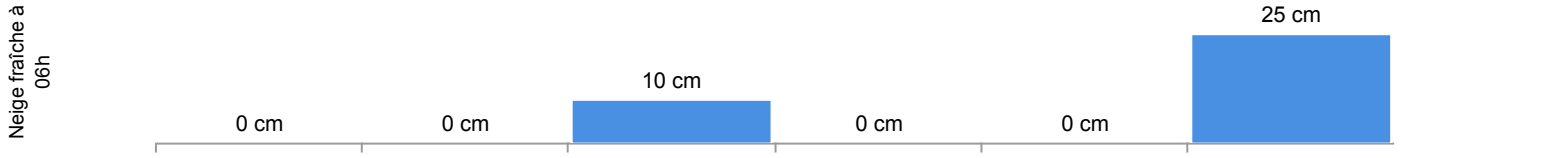

Risque d'avalanche	lun. 16/03	mar. 17/03	mer. 18/03	jeu. 19/03	ven. 20/03	sam. 21/03	dim. 22/03
	3	3	3	3	2	2	3

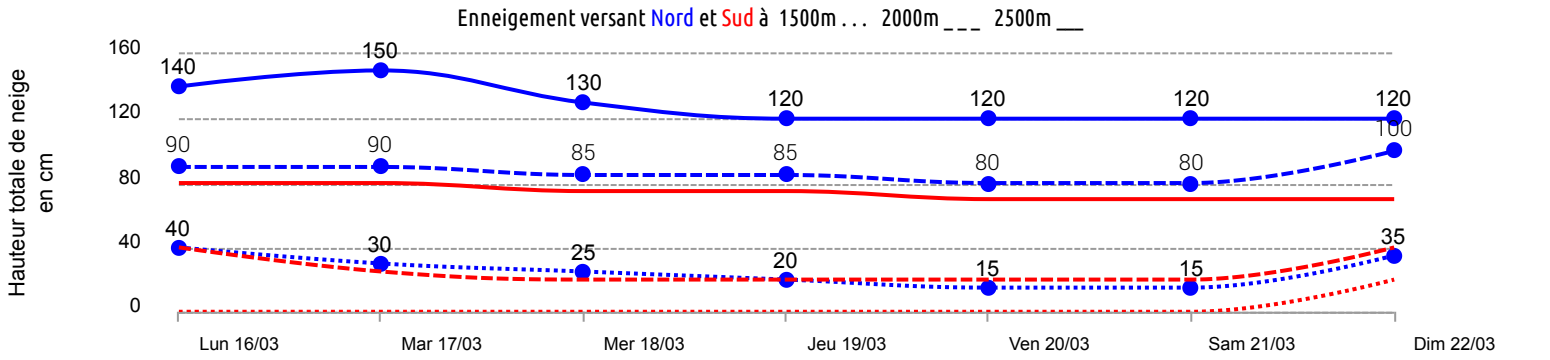

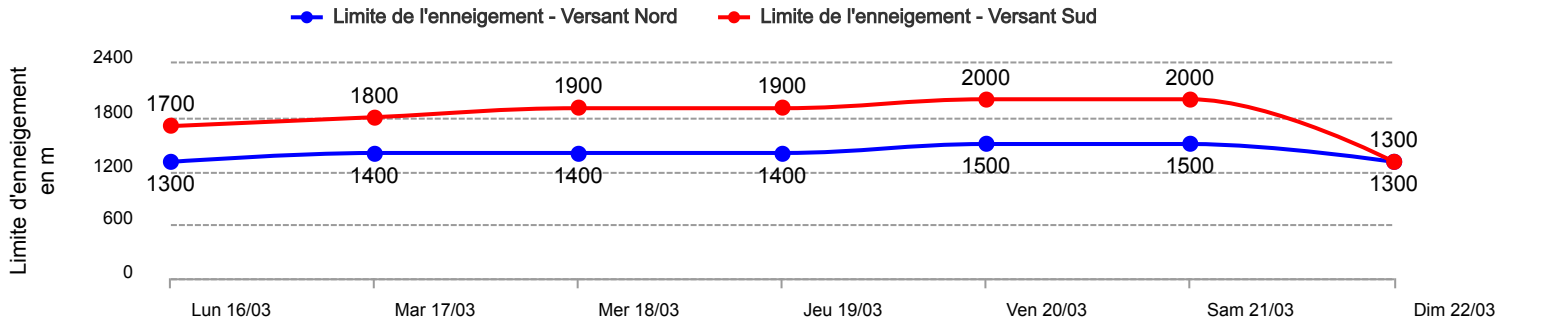

Pour consulter la vigilance en cours, veuillez vous rendre sur le site https://vigilance.meteofrance.fr/fr

Météo-France - 73 avenue de Paris, 94165 Saint-Mandé cedex - Contact : contact@meteo.fr

Rédigé par Météo-France avec la contribution des observateurs du réseau nivo-météorologiques. Partenariat : ANMSM (Maires de Stations de Montagne), DSF (Domaines Skiables de France), ADSP (Directeurs de Pistes et de la Sécurité des Stations de Sports d'Hiver) et autres acteurs de la montagne.

Bulletin neige & avalanches par téléphone au
0 892 68 10 20 Service 0,35 € / min + prix appel