RÉPUBLIQUE FRANÇAISE
*Liberté Égalité Fraternité*

METEO FRANCE
À VOS CÔTÉS, DANS UN CLIMAT QUI CHANGE

# Bulletin d'estimation du risque d'avalanche
## (valable en dehors des pistes balisées et ouvertes)

# MASSIF : Thabor

Rédigé le dimanche 22 mars 2026 à 16h

## Estimation des risques pour le : LUNDI 23 MARS

**PETITES PLAQUES EN PLACE DANS LA NEIGE RÉCENTE, UN PEU D'ACTIVITÉ NATURELLE AU SOLEIL**

2

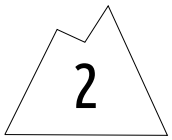


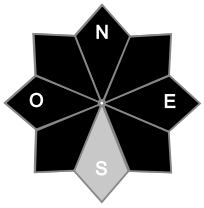


Indice de risque limité.

**Départs spontanés :** départs ponctuels en neige humide au soleil. Taille limitée.

**Déclenchements provoqués :** minces plaques en place dans la neige récente, sensibles en versants froids d'altitude

Indices de risque : 5 très fort - 4 fort - 3 marqué - 2 limité - 1 faible -- En noir : les pentes les plus dangereuses

## Stabilité du manteau neigeux

**Situation avalancheuse typique :** neige ventée

**Déclenchements provoqués** : plaques en place dans la neige fraîche tombée ce dimanche. Plaques souvent peu épaisses mais facilement déclenchables dans un large secteur nord d'altitude supérieure à 2200 m environ. En sud, le soleil détruit rapidement les structures de plaques. Elles peuvent générer des avalanches de taille petite à moyenne (taille 1 à 2) en général.

**Départs spontanés** : en journée, quelques départs sont attendus avec le soleil et le redoux qui viennent déstabiliser la neige récente. Avalanches de petite taille (taille 1).

## Qualité de la neige

**L'enneigement** est proche des normales pour une fin mars.
Hauteurs de neige observées vers 2500 m : 180 cm dans le vallon du Chardonnet, 126 cm à la nivôse des Rochilles, 84 cm à la Nivôse du Galibier.

**Limite d'enneigement skiable** : vers 1400 m en ubacs, 1800/1900 m en adrets pas trop raides.

**État de la neige de surface** : on retrouve en surface 5/15 cm de neige froide, qui repose sur un manteau neigeux printanier bien dense en sud. En large versant nord au-dessus de 2200/2300 m, elle repose sur une neige plus sèche, travaillée par le vent ou encore d'aspect poudreux.

## Aperçu météo pour le lundi 23 mars

| nuit | matin | après-midi | soir |
|---|---|---|---|
| | | | |

Retour du soleil dans une ambiance plus douce : +5°C à 2000 m et -5° à 3000 m.

| Pluie-Neige | | | | |
|---|---|---|---|---|
| Iso 0 °C | 1 300 m | 1 500 m | 2 000 m | 2 100 m |
| Vent 2000 m | ↖ 20 km/h | ↙ 15 km/h | ↘ 20 km/h | ↘ 15 km/h |
| Vent 3000 m | ↖ 30 km/h | ↓ 15 km/h | ↓ 20 km/h | ↘ 20 km/h |

## Épaisseur de neige hors-piste

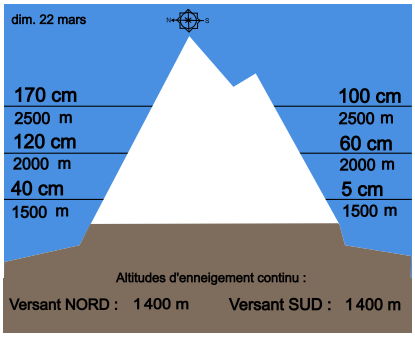


## Précipitations à 1800 m

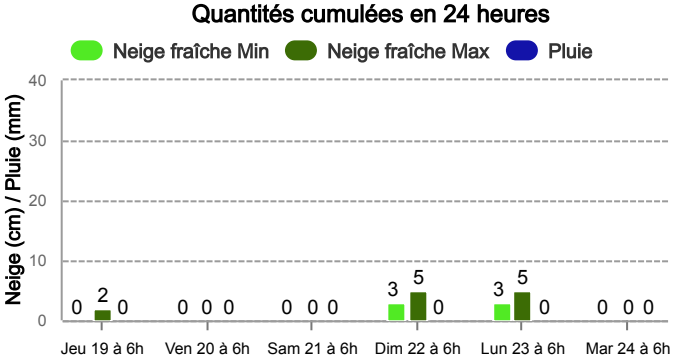


## Tendance du mardi 24 mars

2

**Indice de risque limité**

Maintien d'un risque limité avec la poursuite d'un temps sec et doux. Un peu d'activité naturelle au soleil.

Pour consulter la vigilance en cours, veuillez vous rendre sur le site https://vigilance.meteofrance.fr/fr

Météo-France - 73 avenue de Paris, 94165 Saint-Mandé cedex - Contact : contact@meteo.fr

Rédigé par Météo-France avec la contribution des observateurs du réseau nivo-météorologiques. Partenariat : ANMSM (Maires de Stations de Montagne), DSF (Domaines Skiables de France), ADSP (Directeurs de Pistes et de la Sécurité des Stations de Sports d'Hiver) et autres acteurs de la montagne.

Bulletin neige & avalanches par téléphone au
0 892 68 10 20 Service 0,35 € / min + prix appel

RÉPUBLIQUE FRANÇAISE
*Liberté Égalité Fraternité*

METEO FRANCE
À VOS CÔTÉS, DANS UN CLIMAT QUI CHANGE

# Bulletin d'estimation du risque d'avalanche

## (valable en dehors des pistes balisées et ouvertes)

# MASSIF : Thabor

Rédigé le dimanche 22 mars 2026 à 16h

## Conditions nivo-météo des 7 derniers jours

| | lun. 16/03 | | | | mar. 17/03 | | | | mer. 18/03 | | | | jeu. 19/03 | | | | ven. 20/03 | | | | sam. 21/03 | | | | dim. 22/03 | | | |
|---|---|---|---|---|---|---|---|---|---|---|---|---|---|---|---|---|---|---|---|---|---|---|---|---|---|---|---|---|
| | 03h | 09h | 15h | 21h | 03h | 09h | 15h | 21h | 03h | 09h | 15h | 21h | 03h | 09h | 15h | 21h | 03h | 09h | 15h | 21h | 03h | 09h | 15h | 21h | 03h | 09h | 15h | 21h |
| Météo | | | | | | | | | | | | | | | | | | | | | | | | | | | | |
| Vent (km/h) | 30 | 40 | 50 | 40 | 35 | 20 | 25 | 25 | 40 | 50 | 70 | 65 | 55 | 45 | 30 | 10 | 15 | 15 | 10 | 10 | 15 | 15 | 15 | 20 | 25 | 30 | 35 | 35 |
| à 3000m | | | | | | | | | | | | | | | | | | | | | | | | | | | | |
| Vent (km/h) | 10 | 30 | 40 | 25 | 20 | 15 | 20 | 15 | 20 | 30 | 40 | 20 | 20 | 15 | 15 | 10 | 10 | 5 | 5 | 5 | 5 | 5 | 5 | 5 | 10 | 20 | 25 | 25 |
| à 2000m | | | | | | | | | | | | | | | | | | | | | | | | | | | | |

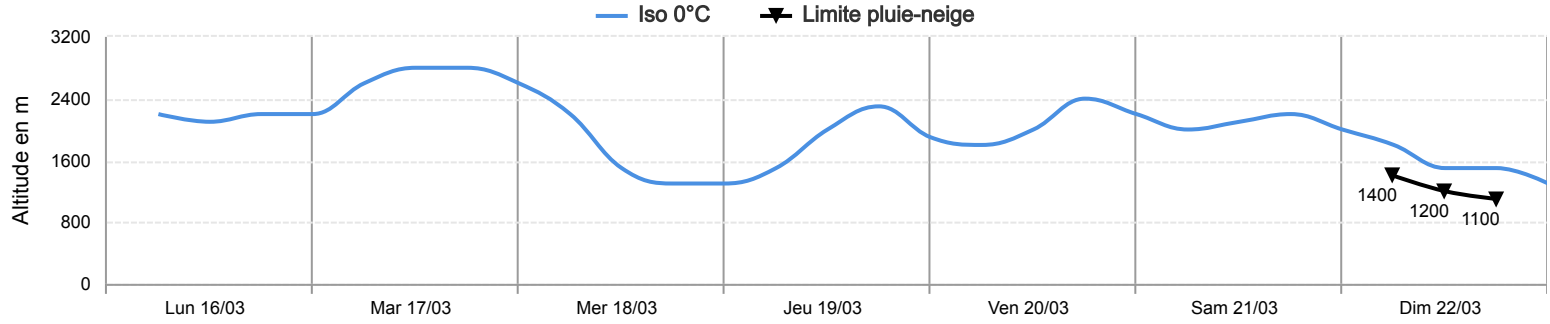


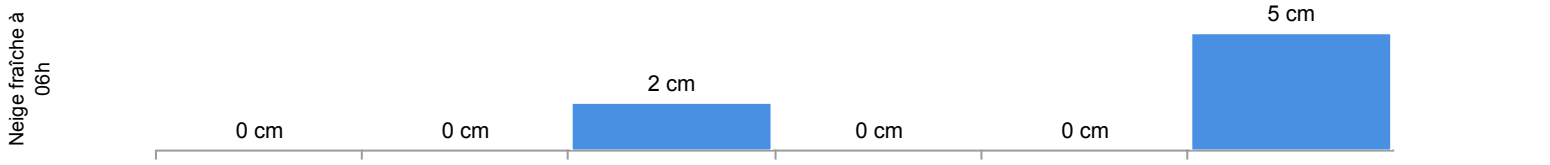


| Risque d'avalanche | lun. 16/03 | mar. 17/03 | mer. 18/03 | jeu. 19/03 | ven. 20/03 | sam. 21/03 | dim. 22/03 |
|---|---|---|---|---|---|---|---|
| | 3 | 3 | 3 | 3 | 2 | 2 | 2 |

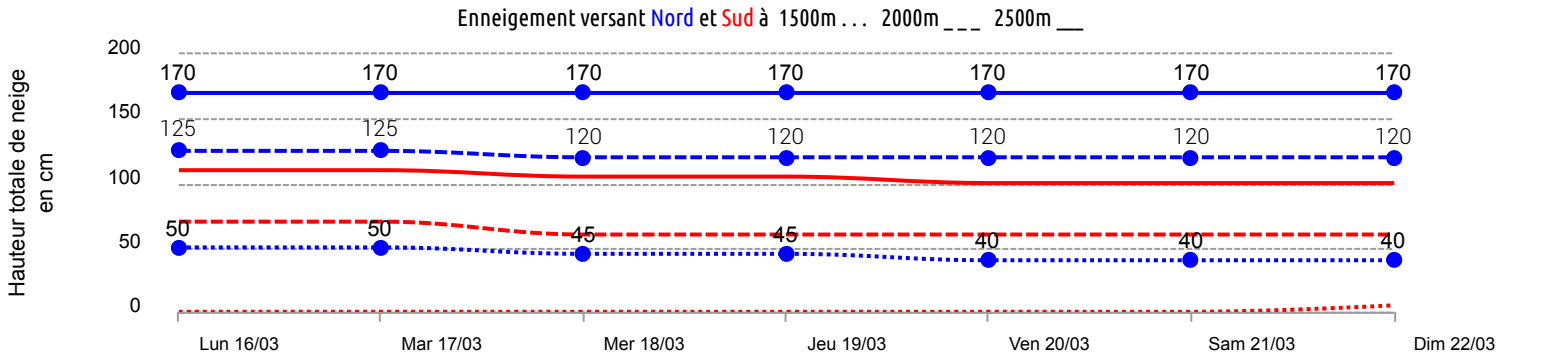


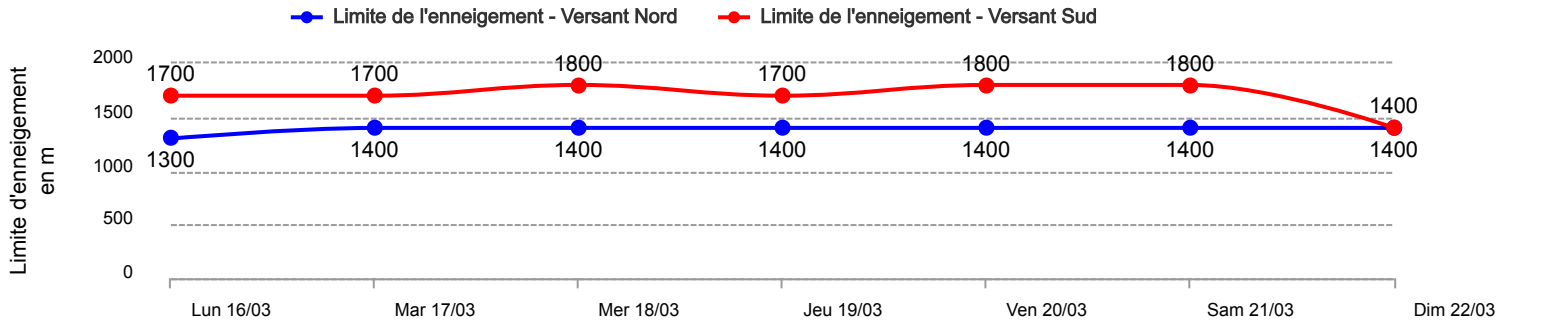


Pour consulter la vigilance en cours, veuillez vous rendre sur le site https://vigilance.meteofrance.fr/fr


**Météo-France - 73 avenue de Paris, 94165 Saint-Mandé cedex - Contact : contact@meteo.fr**



Rédigé par Météo-France avec la contribution des observateurs du réseau nivo-météorologiques. Partenariat : ANMSM (Maires de Stations de Montagne), DSF (Domaines Skiables de France), ADSP (Directeurs de Pistes et de la Sécurité des Stations de Sports d'Hiver) et autres acteurs de la montagne.



Bulletin neige & avalanches par téléphone au
0 892 68 10 20 Service 0,35 € / min + prix appel