GOBIERNO DE ESPAÑA
VICEPRESIDENCIA TERCERA DEL GOBIERNO
MINISTERIO PARA LA TRANSICIÓN ECOLÓGICA Y EL RETO DEMOGRÁFICO

Boletín de información nivológica y de peligro de aludes

Pirineo Navarro y Aragonés

aemet Agencia Estatal de Meteorología

lunes, 23 de marzo de 2026

Pronóstico hasta las 24 horas del martes, día 24 de marzo

(Válido fuera de pistas de esquí balizadas y abiertas)

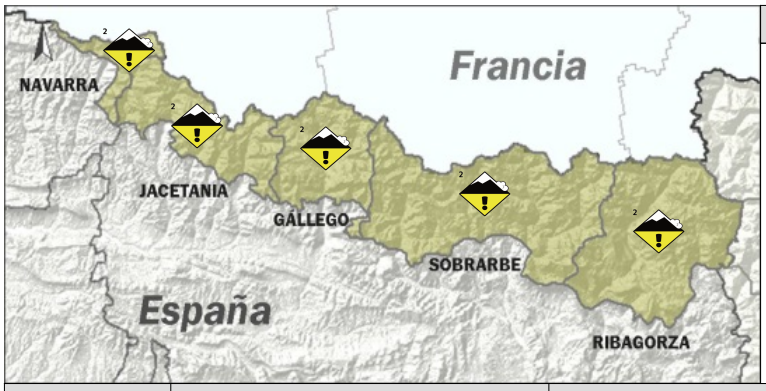

Problemas de aludes

Nieve húmeda

Capas débiles persistentes

Macizo	Peligro	Problemas de aludes, cota, orientación, tamaño	Innivación observada (m)
Navarra	2 Limitado	Nieve húmeda	2026-03-23
Jacetania	2 Limitado	Nieve húmeda Capas débiles persistentes	2026-03-23
Gállego	2 Limitado	Nieve húmeda Capas débiles persistentes	2026-03-23
Sobrarbe	2 Limitado	Nieve húmeda Capas débiles persistentes	2026-03-23

Cota más baja caras N

AEMET. Se autoriza la reproducción de su contenido citando la fuente.

Boletín de información nivológica y de peligro de aludes

Pirineo Navarro y Aragonés

Ribagorza	**Limitado**	**Nieve húmeda** 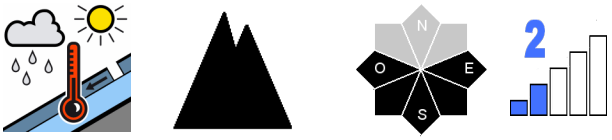 **Capas débiles persistentes** 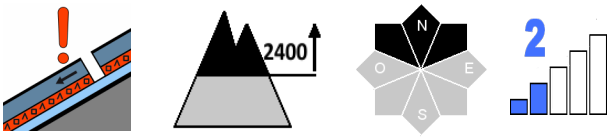	2026-03-23 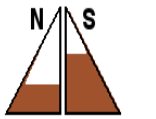 Cota más baja caras N

Estado del manto y observaciones recientes

Continúa el apelmazamiento de la nieve y la mengua progresiva del grosor del manto, con una disminución de entre 1 y 6 cm durante las últimas 24 horas en los diferentes puntos de observación. Pese a ello sigue presentando continuidad desde medianías, aunque con una disimetría entre solanas y umbrías que se va haciendo cada vez más patente. Los espesores rondan los 40 a 140 cm en torno a 1.800 metros y van aumentando conforme ascendemos, de tal manera que pueden superarse en algunas áreas los 180 a 200 cm en cota 2.100.

La nieve se encuentra muy humedecida en zonas medias y bajas así como en solanas de cotas altas, aunque aquí de manera más superficial, y se ve sometida por lo general al ciclo de fusión diurna y rehielo nocturno. En las altas umbrías predomina la nieve más seca, venteada y encostrada, pudiendo existir estratos débiles en el interior del manto localizados a no demasiada profundidad.

Evolución del manto y peligro de aludes para el martes, día 24

Situación de nieve húmeda, y de capas débiles persistentes en cotas altas.

Continuará el régimen de fusión diurna y rehielo nocturno, con formación de costras sobre la superficie del manto que tenderán a mantenerlo estable a primeras horas, aunque esa capa más externa congelada podrá incrementar el peligro de resbalones durante el tránsito. Con el aumento de la insolación a lo largo de la mañana esta costra irá fundiéndose y reblandeciéndose la nieve, lo que aumentará la probabilidad de purgas de nieve húmeda en pendientes con suficiente inclinación, siendo más probables en áreas de solana. En general serán de tamaño pequeño o mediano, sin poder descartase del todo algún deslizamiento basal en laderas herbosas o de roca lisa.

En umbrías de la alta montaña persisten estratos débiles en el interior del manto sobre los cuales puede descansar alguna placa de viento antigua, sobre todo en cercanías de crestas y collados. Estas estructuras podrían romperse fracturarse ante una sobrecarga débil, como es el paso de un esquiador, dando lugar a algún alud de dimensiones medianas, suficiente como para enterrar a una persona.

Predicción meteorológica para el martes, día 24

Poco nuboso o despejado, con velos de nubes altas. Brumas y nieblas matinales en los valles. Temperaturas mínimas sin cambios o en ligero descenso, y máximas en ligero o moderado ascenso. Heladas débiles o localmente moderadas. Vientos flojos de dirección variable, con

AEMET. Se autoriza la reproducción de su contenido citando la fuente.

intervalos de norte moderado en cotas altas.

Datos en la atmósfera libre:

Altitud de la isoterma de 0 ºC: 2.800 m
Altitud de la isoterma de -10 ºC: 4.700 m

Viento a 1500 m: W 10 km/h
Viento a 3000 m: N 20 km/h

Evolución para el miércoles día 25

Nivel de peligro con pocos cambios.

(Información elaborada a partir de los datos recibidos de los refugios de Linza, Lizara, Panticosa, Bachimaña, Góriz, Pineta, Estós, Angel Orús, La Renclusa, Cap de Llauset y Belagua, de las estaciones de esquí de Formigal y Panticosa (lagos), de la estación de esquí de fondo de Llanos del Hospital y de Ordesa Pradera)

Escala europea de peligro de aludes

Débil Limitado Notable Fuerte Muy Fuerte

Problemas de aludes

Nieve reciente Placas de viento Capas débiles persistentes Nieve húmeda Deslizamientos basales Sin problema evidente

Nota1: Se recuerda que, siempre que haya nieve, la ausencia total de peligro no existe. Hay que tener presente que en circunstancias desfavorables, con aludes de tamaño 1 (alud pequeño o colada) y tamaño 2 (alud mediano), se pueden sufrir severos daños personales.

Nota2: Los BPA se elaboran en base a información meteorológica así como al estado del manto nivoso a través de sondeos puntuales. Se advierte a los usuarios de la variabilidad de esta información al extrapolarla a zonas extensas de montaña. Por ello, AEMET no se hace responsable de su uso para la toma de decisiones que conciernen a la seguridad personal, ni de los riesgos físicos o materiales de ellas derivadas.

AEMET. Se autoriza la reproducción de su contenido citando la fuente.