Dienstag 24.03.2026

Veröffentlicht am 23.03.2026 um 17:00

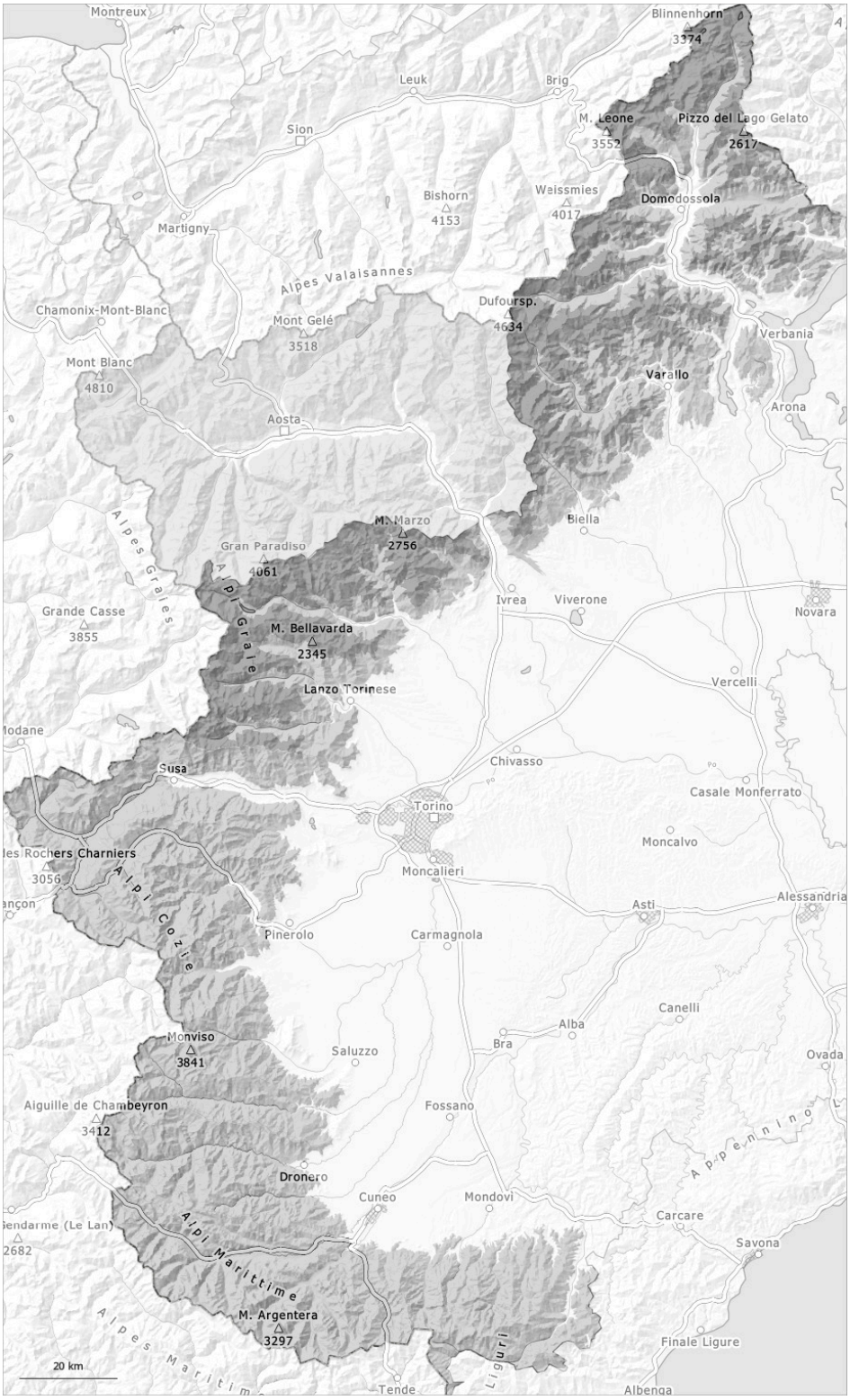

1	2	3	4	5
gering	mäßig	erheblich	groß	sehr groß

Gefahrenstufe 3 - Erheblich

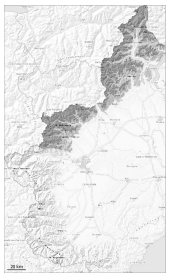

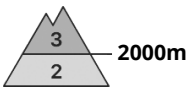

Tendenz: Lawinengefahr bleibt gleich
am Mittwoch, den 25.03.2026

Triebschnee

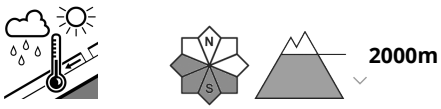

Nassschnee

Triebschnee und Nassschnee sind die Hauptgefahr.

In den letzten drei Tagen fielen oberhalb von rund 1500 m 20 bis 40 cm Schnee, lokal auch mehr. Mit schwachem bis mäßigem Wind entstanden vor allem in Kamm- und Passlagen sowie in der Höhe große Triebschneeansammlungen. Der Neuschnee ist stellenweise schlecht mit dem Altschnee verbunden. Lawinen können v.a. an steilen Schattenhängen im Altschnee anreißen und groß werden. Dies vor allem in mittleren und hohen Lagen.
Mit der tageszeitlichen Erwärmung und der Sonneneinstrahlung sind im Tagesverlauf feuchte und nasse Lawinen möglich, auch große. Dies vor allem an steilen Grashängen in tiefen Lagen sowie an steilen Sonnenhängen in mittleren und hohen Lagen. Touren erfordern eine vorsichtige Routenwahl.

Schneedecke

Gefahrenmuster gm.6: lockerer schnee und wind | gm.10: frühjahrssituation

In den letzten drei Tagen fiel Schnee oberhalb von rund 600 m.
Vor allem mittlere Lagen, steile Sonnenhänge: Der Neuschnee überlagert eine recht günstige Altschneedecke.
Hohe Lagen und Hochgebirge: Der Neuschnee liegt verbreitet auf einer weichen Altschneeoberfläche. Sonne und Wärme führen im Tagesverlauf vor allem in tiefen und mittleren Lagen zu einer zunehmenden Anfeuchtung der Schneedecke.

Gefahrenstufe 2 - Mäßig

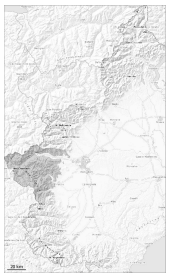

Tendenz: Lawinengefahr bleibt gleich
am Mittwoch, den 25.03.2026

Triebschnee

2200m

Nassschnee

2200m

Trockene Lawinen und feuchte Rutsche im Tagesverlauf sind möglich.

In den letzten drei Tagen fielen oberhalb von rund 1500 m 10 bis 30 cm Schnee, lokal auch mehr. Mit schwachem bis mäßigem Wind entstanden vor allem in Kamm- und Passlagen sowie in der Höhe teils dicke Triebschneeansammlungen. Lawinen können v.a. an steilen Schattenhängen in den verschiedenen Triebschneeschichten anreißen und vereinzelt groß werden. Dies vor allem an Übergängen von wenig zu viel Schnee wie z.B. bei der Einfahrt in Rinnen und Mulden in hohen Lagen und im Hochgebirge. Triebschneeansammlungen können vereinzelt schon von einzelnen Wintersportlern ausgelöst werden. Mit der tageszeitlichen Erwärmung und der Sonneneinstrahlung sind im Tagesverlauf feuchte und nasse Lawinen möglich, vor allem solche mittlerer Größe. Touren erfordern eine vorsichtige Routenwahl.

Schneedecke

Gefahrenmuster gm.6: lockerer schnee und wind

In den letzten drei Tagen fiel Schnee oberhalb von rund 700 m.
Vor allem mittlere Lagen und steile Sonnenhänge: Der Neuschnee überlagert eine recht günstige Altschneedecke.
Hohe Lagen und Hochgebirge: Der Neuschnee liegt teilweise auf einer weichen Altschneeoberfläche. Sonne und Wärme führen im Tagesverlauf vor allem in tiefen und mittleren Lagen zu einer deutlichen Anfeuchtung der Schneedecke.

Gefahrenstufe 2 - Mäßig

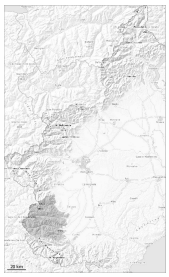

Tendenz: Lawinengefahr bleibt gleich
am Mittwoch, den 25.03.2026

Triebschnee

2100m

Nassschnee

2100m

Trockene Lawinen und feuchte Rutsche im Tagesverlauf sind möglich.

Es fielen oberhalb von rund 1800 m 15 bis 25 cm Schnee. Lawinen können v.a. an steilen Schattenhängen in den verschiedenen Triebschneeschichten anreißen und vereinzelt groß werden. Dies vor allem an Übergängen von wenig zu viel Schnee wie z.B. bei der Einfahrt in Rinnen und Mulden in hohen Lagen und im Hochgebirge. Lawinen können vereinzelt schon von einzelnen Wintersportlern ausgelöst werden. Entlang der Grenze zu Frankreich ist die Situation etwas gefährlicher.
Mit der tageszeitlichen Erwärmung und der Sonneneinstrahlung sind im Tagesverlauf feuchte und nasse Lawinen möglich, vor allem solche mittlerer Größe. Touren erfordern eine vorsichtige Routenwahl.

Schneedecke

Gefahrenmuster gm.6: lockerer schnee und wind

Es fiel Schnee oberhalb von rund 800 m.
Vor allem tiefe und mittlere Lagen, steile Sonnenhänge: Der Neuschnee überlagert eine recht günstige Altschneedecke.
Hohe Lagen und Hochgebirge: Der Neuschnee liegt teilweise auf einer weichen Altschneeoberfläche. Sonne und Wärme führen im Tagesverlauf vor allem in tiefen und mittleren Lagen zu einer zunehmenden Anfeuchtung der Schneedecke.

Gefahrenstufe 2 - Mäßig

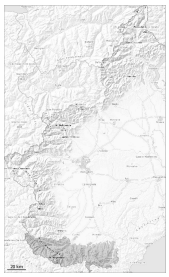

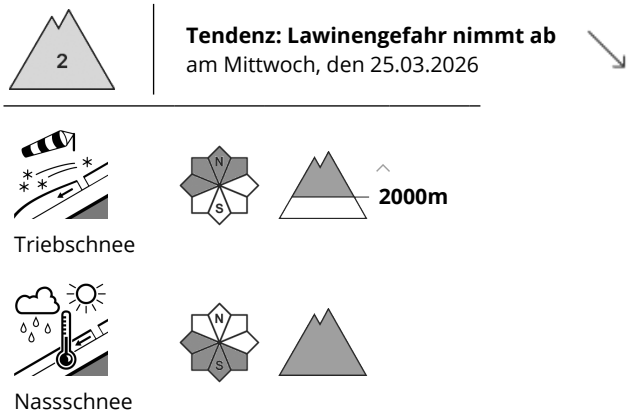

Triebschnee und Nassschnee kritisch beurteilen.

Es fielen oberhalb von rund 1800 m 5 bis 20 cm Schnee. Der wenige Neuschnee vom Wochenende und die vor allem oberhalb von rund 2000 m vorhandenen Triebschneeansammlungen sollten vorsichtig beurteilt werden. Die schon etwas älteren Triebschneeansammlungen können an steilen Schattenhängen in hohen Lagen und im Hochgebirge vor allem mit großer Zusatzbelastung ausgelöst werden. Dies vor allem an Übergängen von wenig zu viel Schnee wie z.B. bei der Einfahrt in Rinnen und Mulden. Mit der tageszeitlichen Erwärmung und der Sonneneinstrahlung sind im Tagesverlauf feuchte und nasse Lawinen möglich, vor allem solche mittlerer Größe.

Schneedecke

Gefahrenmuster gm.6: lockerer schnee und wind

Es fiel Schnee oberhalb von rund 900 m.
Vor allem tiefe und mittlere Lagen, steile Sonnenhänge: Der Neuschnee überlagert eine recht günstige Altschneedecke.
Hohe Lagen und Hochgebirge: Der Neuschnee liegt teilweise auf einer weichen Altschneeoberfläche. V.a. in der Höhe liegen je nach Windeinfluss sehr unterschiedliche Schneehöhen. Sonne und Wärme führen im Tagesverlauf vor allem in tiefen und mittleren Lagen zu einer zunehmenden Anfeuchtung der Schneedecke.

Tendenz

Die Wetterbedingungen führen vor allem in tiefen und mittleren Lagen zu einer zunehmenden Verfestigung der Schneedecke.