Dienstag 24.03.2026

Veröffentlicht am 23.03.2026 um 17:00

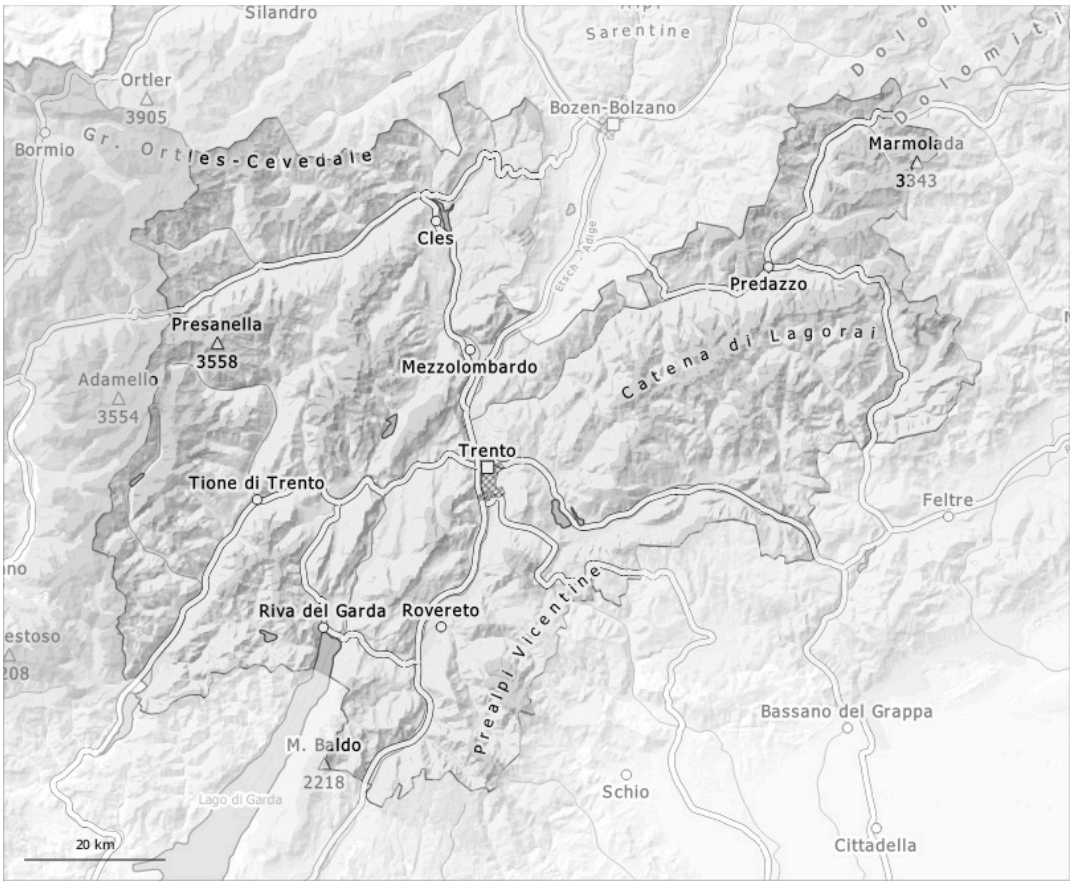

1	2	3	4	5
gering	mäßig	erheblich	groß	sehr groß

Gefahrenstufe 2 - Mäßig

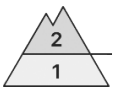

Waldgrenze

Tendenz: Lawinengefahr bleibt gleich
am Mittwoch, den 25.03.2026

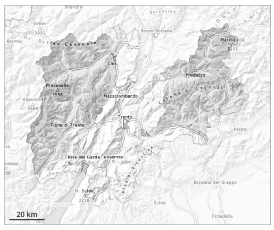

Altschnee

Waldgrenze

Triebschnee

Waldgrenze

Vorsicht vor Triebschnee und schwachem Altschnee.

Schwachen Altschnee vorsichtig beurteilen. Diese Gefahrenstellen liegen vor allem an den Expositionen Nordwest über Nord bis Nordost. Vorsicht vor allem an sehr steilen Schattenhängen oberhalb der Waldgrenze sowie an Übergängen von wenig zu viel Schnee wie z.B. bei der Einfahrt in Rinnen und Mulden. Die Triebschneeansammlungen können vor allem an den Expositionen West über Nord bis Ost oberhalb der Waldgrenze vor allem mit großer Zusatzbelastung ausgelöst werden. Lawinen können auch tiefere Schichten der Schneedecke mitreißen und recht groß werden.
Mit der tageszeitlichen Erwärmung und der Sonneneinstrahlung sind einzelne meist kleine feuchte Lockerschneerutsche möglich. Dies an sehr steilen Hängen an Felswandfüßen.

Schneedecke

Gefahrenmuster gm.1: bodennahe schwachschicht | gm.6: lockerer schnee und wind

Mit teils starkem Wind aus wechselnden Richtungen entstanden in den letzten Tagen teils störanfällige Triebschneeansammlungen. Die frischen und schon etwas älteren Triebschneeansammlungen liegen auf einer ungünstigen Altschneeoberfläche.
Im unteren Teil der Schneedecke sind vor allem an steilen Schattenhängen ausgeprägte Schwachschichten vorhanden. Dies besonders oberhalb von rund 2000 m.

Tendenz

Die Lawinengefahr bleibt bestehen.

Gefahrenstufe 2 - Mäßig

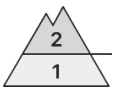

Waldgrenze

Tendenz: Lawinengefahr bleibt gleich
am Mittwoch, den 25.03.2026

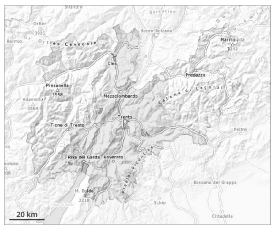

Triebschnee

Waldgrenze

Altschnee

Waldgrenze

Vorsicht vor Triebschnee und schwachem Altschnee.

Schwachen Altschnee vorsichtig beurteilen. Diese Gefahrenstellen liegen vor allem an den Expositionen Nordwest über Nord bis Nordost. Vorsicht vor allem an sehr steilen Schattenhängen oberhalb der Waldgrenze sowie an Übergängen von wenig zu viel Schnee wie z.B. bei der Einfahrt in Rinnen und Mulden. Die Triebschneeansammlungen können vor allem an den Expositionen West über Nord bis Ost oberhalb der Waldgrenze vor allem mit großer Zusatzbelastung ausgelöst werden. Lawinen können auch tiefere Schichten der Schneedecke mitreißen und recht groß werden.
Mit der tageszeitlichen Erwärmung und der Sonneneinstrahlung sind einzelne meist kleine feuchte Lockerschneerutsche möglich. Dies an sehr steilen Hängen an Felswandfüßen.

Schneedecke

Gefahrenmuster gm.1: bodennahe schwachschicht | gm.6: lockerer schnee und wind

Mit teils starkem Wind aus wechselnden Richtungen entstanden in den letzten Tagen teils störanfällige Triebschneeansammlungen. Die frischen und schon etwas älteren Triebschneeansammlungen liegen auf einer ungünstigen Altschneeoberfläche.
Im unteren Teil der Schneedecke sind vor allem an steilen Schattenhängen ausgeprägte Schwachschichten vorhanden. Dies besonders oberhalb von rund 2000 m.

Tendenz

Die Lawinengefahr bleibt bestehen.