Mardi 24.03.2026

Publié 23 03 2026, 17:00

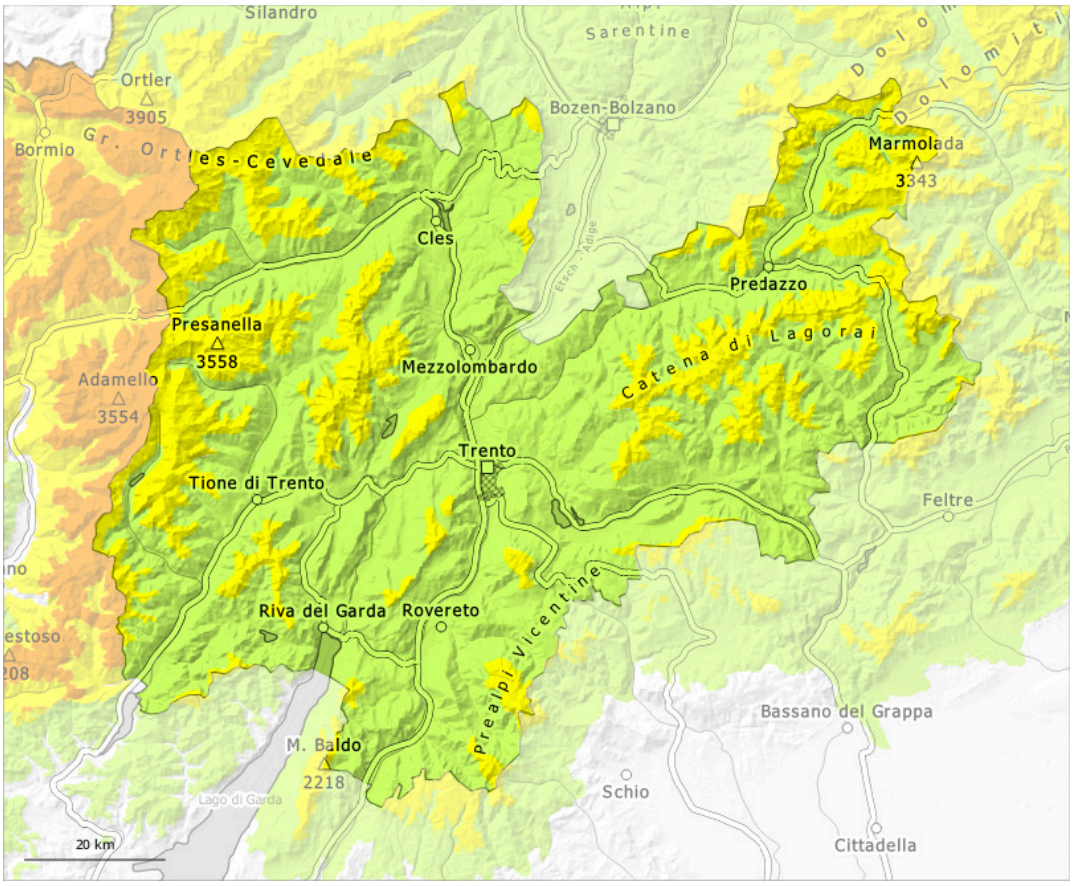

1	2	3	4	5
faible	limité	marqué	fort	très fort

Degré de danger 2 - Limité

Limite de la forêt

Tendance: danger d'avalanche constant
leMercredi 25 03 2026

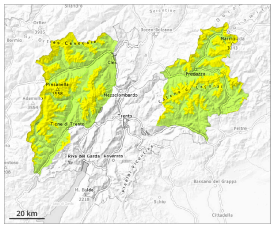

Neige ancienne (Sous-couche fragile persistante)

Limite de la forêt

Neige soufflée (Neige ventée)

Limite de la forêt

Attention à la neige soufflée et neige ancienne fragile.

Neige ancienne fragile à évaluer avec précaution. Ces endroits dangereux se trouvent surtout aux expositions nord-ouest à nord-est en passant par le nord. Prudence surtout sur les pentes très raides à l'ombre au-dessus de la limite de la forêt comme aux transitions entre les endroits peu enneigés et les endroits très enneigés, notamment à l'entrée des combes et des couloirs.
Les accumulations de neige soufflée peuvent être déclenchées surtout avec une surcharge importante surtout sur les pentes exposées à l'ouest à est en passant par le nord au-dessus de la limite de la forêt. Des avalanches peuvent aussi entraîner avec elles les couches profondes du manteau neigeux et atteindre une taille assez importante.
Des coulées de neige meuble humide isolées en général de petite taille sont possibles avec le réchauffement diurne et le rayonnement solaire. Ceci sur les pentes très raides au pied des parois rocheuses.

Manteau neigeux

Modèles de danger md.1: sous-couche fragile persistante | md.6: froid, neige légère et vent

Des accumulations de neige soufflée en partie fragiles se sont formées avec le vent de direction variable partiellement fort dans les derniers jours. Les accumulations récentes et déjà plus anciennes de neige soufflée reposent sur une surface de neige ancienne défavorable.
Dans la partie inférieure du manteau neigeux des couches fragiles importantes sont présentes, surtout sur les pentes raides à l'ombre. Ceci particulièrement au-dessus d'environ 2000 m.

Tendance

Le danger d'avalanches subsiste.

Degré de danger 2 - Limité

Limite de la forêt

Tendance: danger d'avalanche constant
leMercredi 25 03 2026

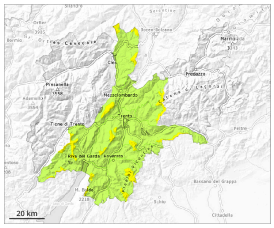

Neige soufflée
(Neige ventée)

Limite de la forêt

Neige ancienne
(Sous-couche fragile persistante)

Limite de la forêt

Attention à la neige soufflée et neige ancienne fragile.

Neige ancienne fragile à évaluer avec précaution. Ces endroits dangereux se trouvent surtout aux expositions nord-ouest à nord-est en passant par le nord. Prudence surtout sur les pentes très raides à l'ombre au-dessus de la limite de la forêt comme aux transitions entre les endroits peu enneigés et les endroits très enneigés, notamment à l'entrée des combes et des couloirs.
Les accumulations de neige soufflée peuvent être déclenchées surtout avec une surcharge importante surtout sur les pentes exposées à l'ouest à est en passant par le nord au-dessus de la limite de la forêt. Des avalanches peuvent aussi entraîner avec elles les couches profondes du manteau neigeux et atteindre une taille assez importante.
Des coulées de neige meuble humide isolées en général de petite taille sont possibles avec le réchauffement diurne et le rayonnement solaire. Ceci sur les pentes très raides au pied des parois rocheuses.

Manteau neigeux

Modèles de danger md.1: sous-couche fragile persistante | md.6: froid, neige légère et vent

Des accumulations de neige soufflée en partie fragiles se sont formées avec le vent de direction variable partiellement fort dans les derniers jours. Les accumulations récentes et déjà plus anciennes de neige soufflée reposent sur une surface de neige ancienne défavorable.
Dans la partie inférieure du manteau neigeux des couches fragiles importantes sont présentes, surtout sur les pentes raides à l'ombre. Ceci particulièrement au-dessus d'environ 2000 m.

Tendance

Le danger d'avalanches subsiste.