ICGC Institut Cartogràfic i Geològic de Catalunya

Servei Meteorològic de Catalunya meteo.cat

Boletín de peligro de aludes para el Pirineo de Catalunya
Del 23/03/2026 al 24/03/2026

(Válido fuera pistas de esquí y zonas no controladas)

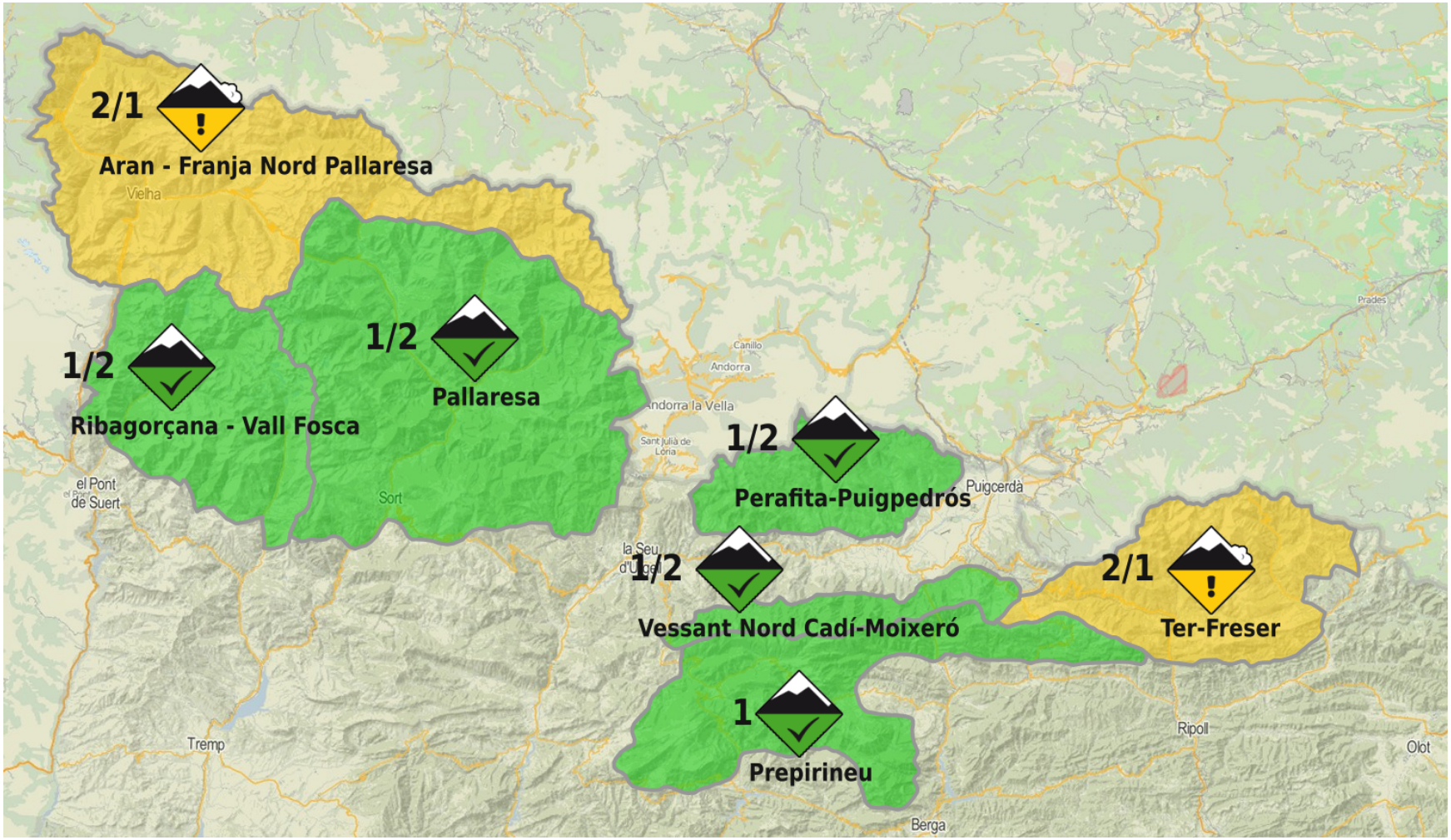

5 MUY FUERTE	4 FUERTE	3 NOTABLE	2 LIMITADO	1 DÉBIL

ICGC Institut Cartogràfic i Geològic de Catalunya

Servei Meteorològic de Catalunya meteo.cat

Boletín de peligro de aludes Aran - Franja Nord Pallaresa Del 23/03/2026 al 24/03/2026

(Válido fuera pistas de esquí y zonas no controladas)

LIMITADO (2) a partir de 2.400 m, y en las horas centrales del día.
DÉBIL (1), en el resto.

Situación primaria

Capas débiles persistentes

Distribución

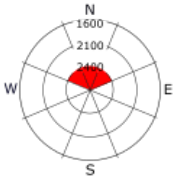

Tamaño

Origen

Tendencia

Situación secundaria

Nieve húmeda

Distribución

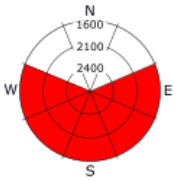

Tamaño

Origen

Tendencia

Estado del manto nivoso

El martes encontraremos un manto, en umbrías elevadas, que todavía presenta una estabilidad pobre, especialmente las placas que descansan sobre facetas o escarcha. Los lugares más delicados son las orientaciones N, NW y NE, en las laderas con cambios abruptos del terreno, poco frecuentados y en canales, por encima de los 2.400 m. De hecho, algunos perfiles de nieve y los test de estabilidad indican una estructura desfavorable del manto de nieve en estos sectores. En estos lugares podremos desencadenar aludes de tamaño 2 (medio), con capacidad de enterrar a una persona. La última nevada, débil, con viento de N, ha formado algunas placas de viento nuevas, pequeñas, bajo collados y crestas en S y E. Son probables también aludes de nieve húmeda, a partir de mediodía, de hasta tamaño 1 (pequeño), sin capacidad de cubrir a una persona, en todas las cotas, en las solanas con fuerte inclinación. No se descarta algún deslizamiento basal, en solanas, de hasta tamaño medio o incluso grande.

Distribución del manto nivoso

Hay nieve por encima de unos 1-500 m en umbrías y 1.800 m en solanas. Los espesores a unos 2.200 m son ligeramente superiores a los normales en la Franja Nord de la Pallaresa y en la mitad sur de Arán donde rondan los 170-190 cm. En la mitad norte de Arán son los normales por estas fechas con 120-140 cm de espesor total.

Tendencia para las próximas 48-72h

Entre el miércoles por la tarde y el viernes nevará, con fuerte viento del NW. Las placas de viento se engrosarán. Peligro: EN PROGRESIVO ASCENSO.

El próximo boletín será emitido el día 2026-03-24

5 MUY FUERTE	4 FUERTE	3 NOTABLE	2 LIMITADO	1 DÉBIL

EAWS EUROPEAN AVALANCHE WARNING SERVICES

ICGC Institut Cartogràfic i Geològic de Catalunya

Servei Meteorològic de Catalunya

Boletín de peligro de aludes Ribagorçana - Vall Fosca Del 23/03/2026 al 24/03/2026

(Válido fuera pistas de esquí y zonas no controladas)

DÉBIL (1), LIMITADO (2), por encima de 2.500 m, y a partir de mediodía.

Situación primaria

Nieve húmeda

Distribución

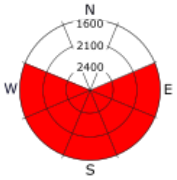

Tamaño

Origen

Tendencia

Situación secundaria

Capas débiles persistentes

Distribución

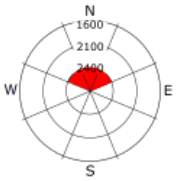

Tamaño

Origen

Tendencia

Estado del manto nivoso

El martes no se esperan cambios en la estabilidad del manto. A primera hora el manto estará rehelado, después de una madrugada fría y serena, y con el paso de las horas, debido a la radiación solar, se humedecerá. En solanas o en umbrías de cota media, en terreno con fuerte inclinación, pueden caer aludes naturales de fusión de forma natural o en nuestro paso esquiando que llegarán a tamaño 1 (pequeño), sin capacidad para enterrar a una persona. En umbrías elevadas, en el límite norte del sector, podemos encontrar, muy localmente, alguna placa antigua que con un sobrecarga fuerte, podría acabar cayendo, y generar aludes de tamaño 2 (medio), con capacidad de enterrar a un montañero. Los lugares delicados están bajo collados y cordales, por encima de 2.500 m. Habrá que vigilar con los resbalones a primera hora por la presencia de costras duras, sobre todo en solanas. Recuerde llevar siempre el DVA, pala y sonda, además del casco, crampones y el piolet.

Distribución del manto nivoso

Hay nieve en el suelo a 1.600 m en terreno umbrío, y por encima de unos 1.900 m en laderas soleadas. El manto es esquiable por encima de unos 1.800-1.900 m en umbrías. Los grosores alcanzan los 105-135 cm a unos 2.200 m. Estos valores se acercan a los normales para la época.

Tendencia para las próximas 48-72h

Entre el miércoles por la tarde y el viernes nevará, con fuerte viento del NW. Las placas de viento se engrosarán. Peligro: EN PROGRESIVO ASCENSO.

El próximo boletín será emitido el día 2026-03-24

5 MUY FUERTE	4 FUERTE	3 NOTABLE	2 LIMITADO	1 DÉBIL

EAWS EUROPEAN AVALANCHE WARNING SERVICES

ICGC Institut Cartogràfic i Geològic de Catalunya

Servei Meteorològic de Catalunya meteo.cat

Boletín de peligro de aludes Pallaresa
Del 23/03/2026 al 24/03/2026

(Válido fuera pistas de esquí y zonas no controladas)

DÉBIL (1), LIMITADO (2), por encima de 2.500 m, y a partir de mediodía.

Situación primaria

Nieve húmeda

Distribución

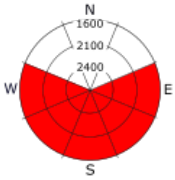

Tamaño

Origen

Tendencia

Situación secundaria

Capas débiles persistentes

Distribución

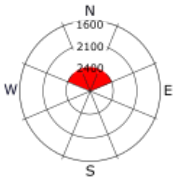

Tamaño

Origen

Tendencia

Estado del manto nivoso

El martes no se esperan cambios en la estabilidad del manto. A primera hora el manto estará rehelado, después de una madrugada fría y serena, y con el paso de las horas, debido a la radiación solar, se humedecerá. En solanas o en umbrías de cota media, en terreno con fuerte inclinación, pueden caer aludes naturales de fusión de forma natural o en nuestro paso esquiando que llegarán a tamaño pequeño, sin capacidad para enterrar a una persona. En umbrías elevadas, en el límite norte del sector, podemos encontrar, muy localmente, alguna placa antigua que descanse sobre facetas o escarcha y que con una sobrecarga fuerte, podría acabar cayendo, y generar aludes de tamaño medio, con capacidad de enterrar a un montañero. Los lugares delicados están bajo collados y cordales, por encima de 2.500 m. Habrá que vigilar con los resbalones a primera hora por la presencia de costras duras, sobre todo en solanas. Recuerde llevar siempre el DVA, pala y sonda, además del casco, crampones y el piolet.

Distribución del manto nivoso

Hay nieve en el suelo a 1.600 m en N, y a 1.800-1.900 m en S. El manto es esquiable por encima de unos 1.800-1.900 m en umbrías. Los espesores alcanzan los 115-155 cm en cotas medias, variable según los efectos del viento.

Tendencia para las próximas 48-72h

Entre el miércoles por la tarde y el viernes nevará, con fuerte viento del NW. Las placas de viento se engrosarán. Peligro: EN PROGRESIVO ASCENSO.

El próximo boletín será emitido el día 2026-03-24

5 MUY FUERTE	4 FUERTE	3 NOTABLE	2 LIMITADO	1 DÉBIL

EAWS EUROPEAN AVALANCHE WARNING SERVICES

ICGC Institut Cartogràfic i Geològic de Catalunya

meteo.cat Servei Meteorològic de Catalunya

Boletín de peligro de aludes Perafita-Puigpedrós Del 23/03/2026 al 24/03/2026

(Válido fuera pistas de esquí y zonas no controladas)

DÉBIL (1), LIMITADO (2), durante las horas centrales del día.

Situación primaria

Nieve húmeda

Distribución

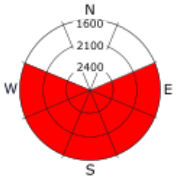

Tamaño

Origen

Tendencia

Estado del manto nivoso

Seguiremos con un manto bien asentado, con una mañana de buen rehielo y una progresiva transformación de la nieve, en las horas centrales del día, debido a la radiación solar. Con el humedecimiento de las costras superficiales pueden caer aludes de fusión de forma natural o a nuestro paso, esquiando, que llegarán a tamaño 1 (pequeño), sin capacidad para enterrar a una persona. El terreno más afectado por aludes de fusión son las salidas de puntos oscuros (rocas y árboles) y terreno con fuerte inclinación a solanas, como canales y pasillos. En umbrías elevadas, en el límite norte del sector, podemos encontrar, muy localmente, alguna placa antigua que con un sobrecarga fuerte, podría acabar cayendo, y generar aludes de tamaño 2 (medio), con capacidad de enterrar a un montañero. Habrá que vigilar con los resbalones a primera hora, por la presencia de costras duras, sobre todo en solanas. Recuerde llevar siempre el DVA, pala y sonda, además del casco, crampones y el piolet.

Distribución del manto nivoso

En umbrías hay nieve por encima de 1.500 m y en las solanas está presente por encima de 1.800 m. Los espesores, aunque irregulares, rondan los 85-105 cm en cotas medias. Son grosores por encima de los habituales en esta época.

Tendencia para las próximas 48-72h

Entre el miércoles por la noche y el viernes nevará, con fuerte viento del NW. Las placas de viento se engrosarán. Peligro: EN PROGRESIVO ASCENSO.

El próximo boletín será emitido el día 2026-03-24

5 MUY FUERTE	4 FUERTE	3 NOTABLE	2 LIMITADO	1 DÉBIL

EAWS EUROPEAN AVALANCHE WARNING SERVICES

ICGC Institut Cartogràfic i Geològic de Catalunya

Servei Meteorològic de Catalunya

Boletín de peligro de aludes
Vessant Nord Cadí-Moixeró
Del 23/03/2026 al 24/03/2026

(Válido fuera pistas de esquí y zonas no controladas)

DÉBIL (1), LIMITADO (2), durante las horas centrales del día por encima de los 2.200 m.

Situación primaria

Nieve húmeda

Distribución

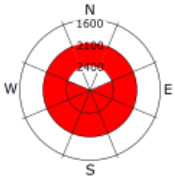

Tamaño

Origen

Tendencia

Estado del manto nivoso

Seguiremos con un manto rehelado y endurecido a primera hora. Con el avance de la jornada, la radiación solar provocará el humedecimiento superficial del manto y ablandará las costras. En las solanas más elevadas pueden caer aludes pequeños de fusión de forma natural y también a nuestro paso, esquiando, sin capacidad para enterrar a una persona, excepto en terreno trampa donde habrá que evitar pasar mientras la nieve no rehiele, durante las horas centrales del día. El terreno más afectado por aludes de fusión son las zonas de salida de puntos oscuros como rocas y árboles. Habrá que vigilar los resbalones, sobre todo en lo alto de las Canals y bajo collados y crestas más elevadas.

Distribución del manto nivoso

En umbrías hay presencia discontinua de nieve por encima de 1.600 m y es esquiable por encima de 1.900 m. Los grosores están alrededor de 160-180 cm a 2.200 m. Estos valores son muy excedentarios para la época del año.

Tendencia para las próximas 48-72h

Se podrán formar algunas placas, pequeñas, bajo collados o cordales, con los chubascos con viento previstos. Peligro: SIN CAMBIOS o EN LEVE ASCENSO.

El próximo boletín será emitido el día 2026-03-24

5 MUY FUERTE	4 FUERTE	3 NOTABLE	2 LIMITADO	1 DÉBIL

EAWS EUROPEAN AVALANCHE WARNING SERVICES

ICGC Institut Cartogràfic i Geològic de Catalunya

Servei Meteorològic de Catalunya

Boletín de peligro de aludes Prepirineu
Del 23/03/2026 al 24/03/2026

(Válido fuera pistas de esquí y zonas no controladas)

DÉBIL (1).

Situación primaria

Nieve húmeda

Distribución

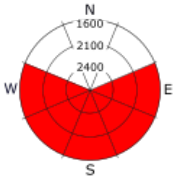

Tamaño

Origen

Tendencia

Estado del manto nivoso

Los últimos chubascos han dejado 1 cm de nieve granulada. El manto sigue bastante endurecido internamente, con presencia de costras duras, grano fino y algunas formas mixtas. El martes se espera rehielo, después de una madrugada serena, y el manto se mostrará asentado. Debido a la transformación de la nieve por la radiación solar, a partir de mediodía, con el humedecimiento diurno, no se descarta la caída de bolas o de algún alud húmedo, pequeño, que no tendrá capacidad para enterrar a una persona, excepto en terreno trampa donde habrá que evitar pasar durante las horas de más calor. Las orientaciones más sensibles a la caída de aludes de nieve húmeda son las orientadas a Este, Sur y Oeste, así como las umbrías de cota media. Habrá que vigilar con los resbalones, sobre todo por la mañana. Recuerde llevar siempre el DVA, pala y sonda, además del casco, los crampones y el piolet.

Distribución del manto nivoso

En umbrías hay nieve por encima de 1700 m. En solanas la nieve está presente por encima de 1.900 m. Los espesores, aunque irregulares, rondan los 65-85 cm en cotas medias.

Tendencia para las próximas 48-72h

Seguiremos con un manto asentado y endurecido. Entre el jueves y el viernes caerán algunos chubascos, con viento. Peligro: EN LEVE ASCENSO.

El próximo boletín será emitido el día 2026-03-24

5 MUY FUERTE	4 FUERTE	3 NOTABLE	2 LIMITADO	1 DÉBIL

EAWS EUROPEAN AVALANCHE WARNING SERVICES

ICGC Institut Cartogràfic i Geològic de Catalunya

Servei Meteorològic de Catalunya

Boletín de peligro de aludes Ter-Freser
Del 23/03/2026 al 24/03/2026

(Válido fuera pistas de esquí y zonas no controladas)

LIMITADO (2), por encima de 2.500 m, y a partir de mediodía.
DÉBIL (1), en el resto.

Situación primaria

Nieve venteada

Distribución

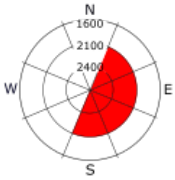

Tamaño

Origen

Tendencia

Situación secundaria

Nieve húmeda

Distribución

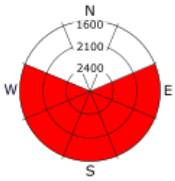

Tamaño

Origen

Tendencia

Estado del manto nivoso

La última nevada ha dejado de 5 a 10 cm acompañada de viento del N. Se han formado placas de viento a sotavento, orientaciones S y E. El martes, se esperan aludes a nuestro paso, en forma de placa de viento, que pueden llegar, por lo general, a tamaño pequeño, y localmente, hasta tamaño medio, con capacidad de enterrar a una persona. A primera hora el manto estará rehelado, después de una madrugada fría y serena, y con el paso de las horas, debido a la radiación solar, se humedecerá. En solanas o en umbrías de cota media, en terreno con fuerte inclinación, pueden caer aludes naturales de fusión de forma natural o en nuestro paso esquiando que llegarán a tamaño 1(pequeño), sin capacidad para enterrar a una persona. Habrá que vigilar con los resbalones a primera hora por la presencia de costras duras, sobre todo en solanas. Además, la nieve reciente o venteada habrá tapado las costras resbaladizas. Recuerde llevar siempre el DVA, pala y sonda, además del casco, crampones y el piolet.

Distribución del manto nivoso

Hay nieve en el suelo por encima de 1.700 m. El manto es esquiable en umbrías a partir de unos 1.700 m. Los grosores son muy excedentarios para la época del año y en lugares no afectados por el viento oscilan entre 85-105 cm a unos 2.000 m y más de 150 cm por encima de 2.400 m.

Tendencia para las próximas 48-72h

Entre el jueves y el viernes nevará, con fuerte viento del NW. Las placas de viento se engrosarán. Peligro: EN ASCENSO.

El próximo boletín será emitido el día 2026-03-24

5 MUY FUERTE	4 FUERTE	3 NOTABLE	2 LIMITADO	1 DÉBIL

EAWS EUROPEAN AVALANCHE WARNING SERVICES