BUTLLETÍ DEL PERILL D'ALLAUS DEL PRINCIPAT D'ANDORRA

Servei meteorològic nacional
Principat d'Andorra

Elaborat el 23/03/2026 16:00
Propera actualització 24/03/2026 a les 16h

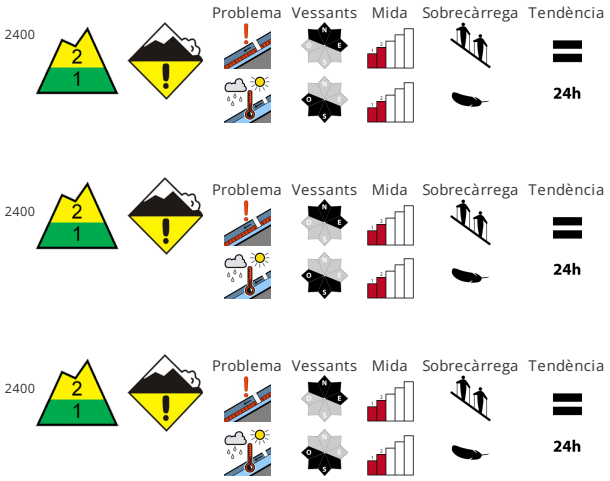

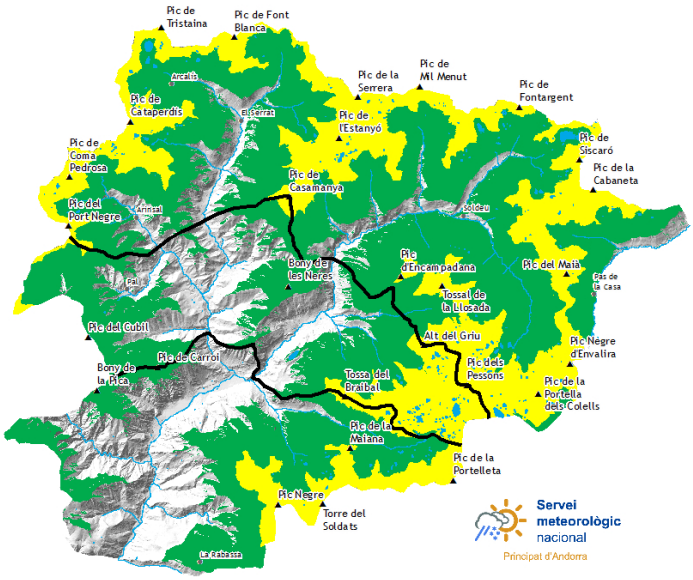

ESTABILITAT DEL MANTELL NIVAL

En alguns indrets la neu recent reposa sovint a sobre de capes toves. A cotes altes als vessants obacs :. A la part superior del mantell de neu hi ha capes febles de cristalls grossos. Aquestes poden ser desencadenades sobretot per una sobrecàrrega forta i assolir mida mitjana. Les capes febles a la part superior del mantell de neu requereixen cautela. A més del perill de ser enterrat per una allau, cal tenir en compte el perill de ser arrossegat cap a una trampa del terreny. Amb la penetració de la humitat, en el transcurs de la jornada són possibles allaus de neu humida, però majoritàriament petites. Això es dona especialment en vessants assolellats inclinats. A més, són possibles algunes allaus de lliscament basal.

QUALITAT DE LA NEU

El temps serà força assolellat. Als vessants inclinats assolellats :. La superfície del mantell de neu es regelarà tot just i s'estovarà al llarg del dia. Als vessants inclinats orientats a nord-oest, nord i nord-est i a cotes altes :. La part superior del mantell és tova , amb una superfície formada per neu de feble cohesió. Prop de les carenes els gruixos de neu varien molt per la influència del vent.

GRUIXOS DEL MANTELL NIVAL FORA DE PISTA

Zona nord		Gruix neu		
Mantell Nival		1500m	2000m	2500m
N	1600 m	0 cm	150 cm	200 cm
S	1900 m	0 cm	100 cm	150 cm

Zona centre		Gruix neu		
Mantell Nival		1500m	2000m	2500m
N	1600 m	0 cm	150 cm	200 cm
S	1900 m	0 cm	100 cm	150 cm

Zona sud		Gruix neu		
Mantell Nival		1500m	2000m	2500m
N	1600 m	0 cm	120 cm	150 cm
S	1900 m	0 cm	60 cm	100 cm

Govern d'Andorra

EAWS
EUROPEAN AVALANCHE WARNING SERVICES

Aquest butlletí ha estat elaborat seguint les normes i recomanacions de l'**European Avalanche Warning Services**, del qual el **Servei meteorològic Nacional** n'és membre

BUTLLETÍ DEL PERILL D'ALLAUS DEL PRINCIPAT D'ANDORRA

Servei meteorològic nacional
Principat d'Andorra

Informació detallada per espais naturals protegits

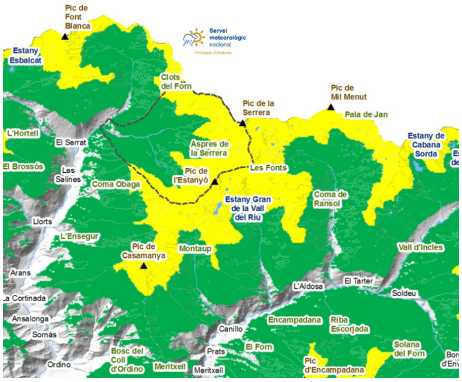

SORTENY

Les febles nevades de la nit del diumenge no han canviat l´estabilitat del mantell. Haurem de continuar mantenint la cautela en els vessants nord i est on poden haver-hi capes febles persistents formades per gran angulosos, lleugerament recobertes per la neu recent. En el transcurs de la jornada i amb la penetració de la humitat, tornarem a tenir neu tova per sota de 2.400 metres.

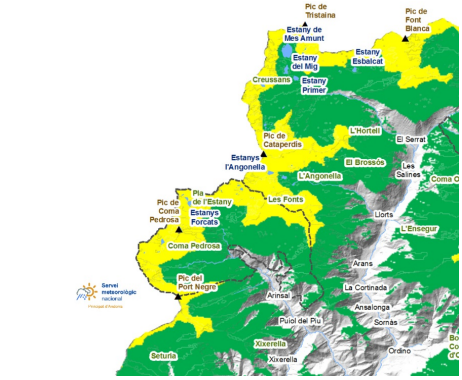

COMAPEDROSA

Com a tot el país, als vessants nord i est en alçada trobarem capes febles encara sol·licitables, amb les que haurem de fer atenció. A mida que avanci el dia també haurem de prestar atenció als problemes de neu humida en els vessants assolellats més inclinats i als peus de parets rocoses. Pot haver-hi activitat d´allaus de fons amb les esquerdes obertes.

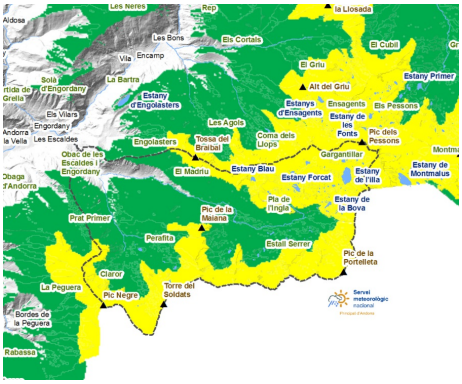

MADRIU-PERAFITA-CLAROR

Tot i que els darrers dies la neu ha patit un retrocés important a cotes baixes, encara hi ha neu suficient per fer nombroses rutes. Haurem de ser especialment cautelosos als vessants amb problemes de capes febles persistents.

Govern d'Andorra

EAWS
EUROPEAN AVALANCHE WARNING SERVICES

Aquest butlletí ha estat elaborat seguint les normes i recomanacions de l'**European Avalanche Warning Services**, del qual el **Servei meteorològic Nacional** n'és membre

BUTLLETÍ DEL PERILL D'ALLAUS DEL PRINCIPAT D'ANDORRA

Servei meteorològic nacional
Principat d'Andorra

Gruixos de neu nova dels darrers dies (de les últimes 24h mesurat a les 06:00h UTC)

	19/03/2026	20/03/2026	21/03/2026	22/03/2026
FEDA (Central)	0 cm	0 cm	0 cm	0 cm
Engolasters - FEDA	0 cm	0 cm	0 cm	0 cm
Bony de les Neres	0 cm	0 cm	0 cm	3 cm
Sorteny	0 cm	0 cm	0 cm	4 cm
Les Fonts d'Arinsal	0 cm	0 cm	0 cm	7 cm
Perafita	0 cm	0 cm	0 cm	7 cm
Tossa Espiolets	0 cm	0 cm	0 cm	3 cm
Grau Roig - FEDA	0 cm	0 cm	0 cm	7 cm
Fontverd	0 cm	0 cm	0 cm	0 cm
Ransol - FEDA	0 cm	0 cm	0 cm	2 cm
Caborreu	0 cm	0 cm	0 cm	0 cm
La Solana	0 cm	0 cm	0 cm	10 cm
Envalira Antenes	0 cm	0 cm	0 cm	6 cm
Vall del Riu FEDA	0 cm	0 cm	0 cm	5 cm