MINISTERO DELLA DIFESA

meteomont
Servizio Nazionale di previsione neve e valanghe

EAWS EUROPEAN AVALANCHE WARNING SERVICES

CARABINIERI

AERONAUTICA MILITARE SERVIZIO METEOROLOGICO

MAJELLA

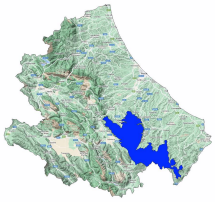

Bollettino Valanghe N. 370/2026 del 23/03/2026 ore 14.00
Validità 48 ore prossima emissione 24/03/2026

A cura del Servizio METEOMONT dell'ARMA dei CARABINIERI
In collaborazione con Servizio Meteorologico dell'Aeronautica militare

SITUAZIONE alle 14:00 del 23/03/2026

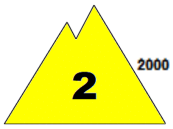

SITUAZIONE TIPO: neve a debole coesione e vento.

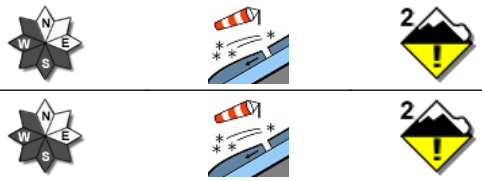

SITUAZIONE TIPO: neve a debole coesione e vento.

Quota neve (mslm)	Nord	Sud
	800 - 900	900 - 1000

Altezza Neve (cm)	Neve al suolo	Neve Fresca	Quota (mslm)
	063	002	1650
	018	003	1270

VALANGHE OSSERVATE: -.

PREVISIONI 24/03/2026

GRADO DI PERICOLO: MODERATO 2

SITUAZIONE TIPO: neve a debole coesione e vento.

SITUAZIONE TIPO: situazione primaverile.

MANTO NEVOSO: La stabilità del manto nevoso è discreta su alcuni punti (aree) per versanti da sud est a nord ovest al di sopra di 2000 mslm, possibili valanghe di dimensioni medie.
La stabilità del manto nevoso è discreta su alcuni punti (aree) per versanti al sole al di sotto di 2000 mslm, possibili valanghe di dimensioni medie.

AVVERTENZE

A seguito dell'attività eolica registrata sono da evitare le zone di accumulo, conche, canaloni, cambi di pendenza e pendii sotto vento in genere.

SCALA EUROPEA DEL GRADO DI PERICOLO VALANGHE

5 - MOLTO FORTE | 4 - FORTE | 3 - MARCATO | 2 - MODERATO | 1 - DEBOLE | NO NEVE | NO INFO

LEGENDA PROBLEMA

NEVE FRESCA | LASTRONI DA VENTO | STRATI DEBOLI PERSISTENTI | NEVE BAGNATA | SLITTAMENTO | CORNICI | NESSUN PROBLEMA VALANGHIVO EVIDENTE | NO_INFO

Bollettino realizzato su scala sinottica-regionale (standard EAWS). La sua valutazione non può escludere in alcun modo la necessità di una seria e capace valutazione locale del pericolo (singolo pendio) che può essere anche sensibilmente diverso. Le previsioni meteorologiche sono relative all'orario UTC (per l'Italia +1 in inverno e +2 in estate).

MINISTERO DELLA DIFESA

meteomont
Servizio Nazionale di previsione neve e valanghe

EAWS EUROPEAN AVALANCHE WARNING SERVICES

CARABINIERI

MAJELLA

PREVISIONE METEO

Quota		24/03/2026 h6:00	24/03/2026 h12:00	24/03/2026 h18:00
1000	Venti	03 Nodi da Nord	03 Nodi da Nord	03 Nodi da Nord
	Temperature	-02 °C	-01 °C	-01 °C
	Temp.percepita	-4 °C	-3 °C	-3 °C
2000	Venti	08 Nodi da Nord	08 Nodi da Nord	06 Nodi da Nord
	Temperature	-04 °C	-03 °C	-03 °C
	Temp.percepita	-9 °C	-8 °C	-7 °C
3000	Venti	09 Nodi da N-Est	10 Nodi da N-Est	10 Nodi da N-Est
	Temperature	-09 °C	-09 °C	-09 °C
	Temp.percepita	-16 °C	-16 °C	-16 °C
Zero termico		1300-1500 m.	1500-1700 m.	1400-1600 m.
Fenomeno		—	—	—
Stato del cielo				

LEGENDA FENOMENI

Assenza Fenomeni · Nebbia · Foschia · Pioggia debole · Pioggia moderata · Pioggia forte · Temporali · Nevicata debole · Nevicata moderata · Nevicata forte

STATO DEL CIELO

Sereno · Poco nuvoloso · Nuvoloso · Molto nuvoloso · Coperto

Parametri meteonivometrici registrati presso i campi di rilevamento il 23/03/2026.

Località	Comune	Quota (m.s.l.m.)	Altezza neve (cm)	Neve caduta nelle 24 ore (cm)	Temp. Min (°C)	Temp. Max (°C)	Condizioni del tempo
QUARTARANA	Campo di Giove (AQ)	1200	18	0	0	+5	Pioggia debole intermittente
PASSOLANCIANO	Lettomanoppello (PE)	1300	45	2	0	+6	Nebbia con cielo non visibile
VALICO DELLA FORCHETTA	Palena (CH)	1270	18	0	-1	+2	Nebbia con cielo non visibile
VALLE DEL SOLE	Pizzoferrato (CH)	1440	18	1	-1	+3	Nevicata debole continua
MAIELETTA MAMMA ROSA	Pretoro (CH)	1650	63	2	-4	+2	Nevicata debole intermittente
PASSO SAN LEONARDO	Sant'Eufemia a Maiella (PE)	1145	14	0	-1	+9	Nevicata debole continua

(*) Rilievi fuori campo

L'INFORMAZIONE E' PREVENZIONE - LEGGI L'ATTUALE GRADO DI PERICOLO VALANGHE!

IL CAPO DEL CENTRO NAZIONALE METEOMONT
(Ten. Col. RFI Emanuela Gini)
FIRMA AUTOGRAFA OMESSA AI SENSI
DELL'ART.3 DEL D.LGS N.39/1993

Bollettino realizzato su scala sinottica-regionale (standard EAWS). La sua valutazione non può escludere in alcun modo la necessità di una seria e capace valutazione locale del pericolo (singolo pendio) che può essere anche sensibilmente diverso. Le previsioni meteorologiche sono relative all'orario UTC (per l'Italia +1 in inverno e +2 in estate).