Bulletin d'estimation du risque d'avalanche

(valable en dehors des pistes balisées et ouvertes)

MASSIF : Oisans

Rédigé le lundi 23 mars 2026 à 15h

Estimation des risques pour le : MARDI 24 MARS

RARES MINCES PLAQUES EN NORD D'ALTITUDE... EN FACES ENSOLEILLEES, RARES COULES OU PETITES AVALANCHES DE SURFACE...

2

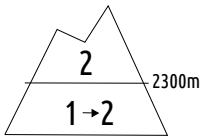

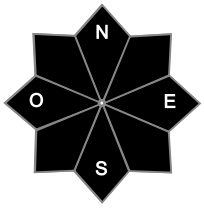

Localisées

Au-dessus de 2300m indice de risque limité, plus bas indice faible évoluant en limité.

Départs spontanés : En pentes raides ensoleillées, près des rochers, quelques coulées ou rares petites avalanches possibles (de taille 1, rarement 2)..

Déclenchements provoqués : Près des hautes crêtes, rares petites plaques en faces froides, sous le vent de Nord-Est ? Au soleil en neige bien humidifiée, possible coulée ponctuelle sous les skis...

Indices de risque : 5 très fort - 4 fort - 3 marqué - 2 limité - 1 faible -- En noir : les pentes les plus dangereuses

Stabilité du manteau neigeux

Situation avalancheuse typique : neige humide neige ventée

Les 15/20 cm tombés dimanche tendent à se stabiliser. Rares instabilités mardi et souvent superficielles...

Déclenchements provoqués :

Rares plaques vers les hautes crêtes, en versant froid. Le récent vent de Nord-Est a pu former de petites accumulations en altitude, parfois instables au passage de skieur ?
Indices : manteau ridé, quelques congères , plutôt vers le Taillefer? Cassures 10/20 cm environ, peu larges.
En pentes bien ensoleillées, humidifiées, la neige récente peut éventuellement glisser sous les skis.

Départs spontanés :

Des coulées de surface se sont déjà produites. Mardi la douceur gagne plus en altitude... Suivant la course du soleil, en pentes raides, près des rochers, on s'attend à de rares nouvelles coulées voire une avalanche de surface (de taille 1 à 2).

Autres : Neige localement et temporairement croutée/cassante, ski parfois délicat.

Qualité de la neige

Qualification de l'enneigement : L'enneigement est bon pour la saison en versants ombragés au dessus de 1300/1500 m, voire abondant en combes d'altitude. En Sud il est moins bon mais correct dès 1700 m environ.
Limites skiables : Vers 1300/1700 m selon les versants.

Qualité de la neige mardi : Neige récente parfois croutée par le soleil de la veille, délicate à skier avant le dégel.
En faces Nord d'altitude, neige encore poudreuse au dessus de 2000/2300m, avec jusque 20 cm de neige récente sur le Nord Oisans et Taillefer... Petite couche assez légère, agréable à skier avec du givre en surface et parfois un peu ventée vers les hautes crêtes ?.

Aperçu météo pour le mardi 24 mars

nuit	matin	après-midi	soir

Nuit de lundi à mardi claire et froide. Mardi, beau soleil et redoux en adrets...

Pluie-Neige				
Iso 0 °C	2 000 m	2 400 m	2 600 m	2 700 m
Vent 2500 m	↘ 10 km/h	↘ 10 km/h	↘ 10 km/h	→ 5 km/h
Vent 3500 m	↘ 20 km/h	↓ 15 km/h	→ 10 km/h	↘ 10 km/h

Épaisseur de neige hors-piste

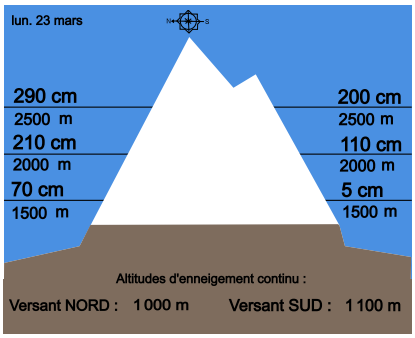

Précipitations à 1800 m

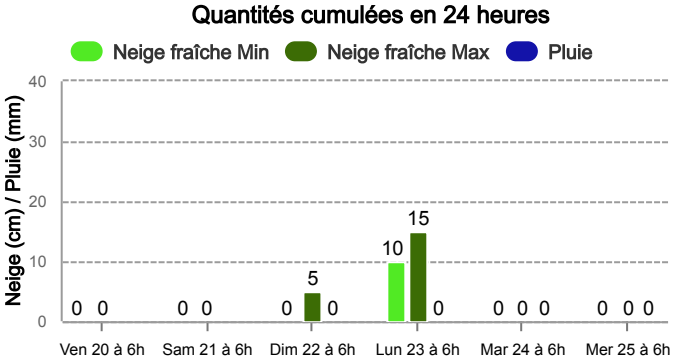

Tendance du mercredi 25 mars

3 **Indice de risque marqué**

Risque d'avalanche en hausse mercredi après-midi/soir, en altitude : Vent d'Ouest puis Nord-Ouest chassant la neige en altitude et averses de neige prévues, 5 puis 10 cm de fraîche... De nouvelles plaques en formation...

Pour consulter la vigilance en cours, veuillez vous rendre sur le site https://vigilance.meteofrance.fr/fr

Météo-France - 73 avenue de Paris, 94165 Saint-Mandé cedex - Contact : contact@meteo.fr

Rédigé par Météo-France avec la contribution des observateurs du réseau nivo-météorologiques. Partenariat : ANMSM (Maires de Stations de Montagne), DSF (Domaines Skiables de France), ADSP (Directeurs de Pistes et de la Sécurité des Stations de Sports d'Hiver) et autres acteurs de la montagne.

Bulletin neige & avalanches par téléphone au **0 892 68 10 20** Service 0,35 € / min + prix appel

RÉPUBLIQUE FRANÇAISE
Liberté Égalité Fraternité

METEO FRANCE
À VOS CÔTÉS, DANS UN CLIMAT QUI CHANGE

Bulletin d'estimation du risque d'avalanche
(valable en dehors des pistes balisées et ouvertes)

MASSIF : Oisans

Rédigé le lundi 23 mars 2026 à 15h

Conditions nivo-météo des 7 derniers jours

	mar. 17/03				mer. 18/03				jeu. 19/03				ven. 20/03				sam. 21/03				dim. 22/03				lun. 23/03			
	03h	09h	15h	21h	03h	09h	15h	21h	03h	09h	15h	21h	03h	09h	15h	21h	03h	09h	15h	21h	03h	09h	15h	21h	03h	09h	15h	21h
Météo																												
Vent (km/h)	30	20	20	25	35	35	40	55	55	35	20	30	35	30	20	5	10	10	10	10	5	10	10	5	20	20	20	25
à 3500m	↙	↙	→	↓	↓	↙	←	←	←	←	↙	↙	↙	↙	↓	↗	↓	↓	↓	↓	↗	↗	←	↙	↙	↓	↓	↙
Vent (km/h)	15	10	10	15	15	15	25	35	40	15	10	10	15	15	5	0	5	0	5	5	0	5	5	0	10	15	15	15
à 2500m	↓	↙	↘	↓	↙	←	←	←	←	←	↓	↙	↓	↙	↓	↓	↓	↙	↗	↓	↓	↗	→	↓	←	↙	↓	↙

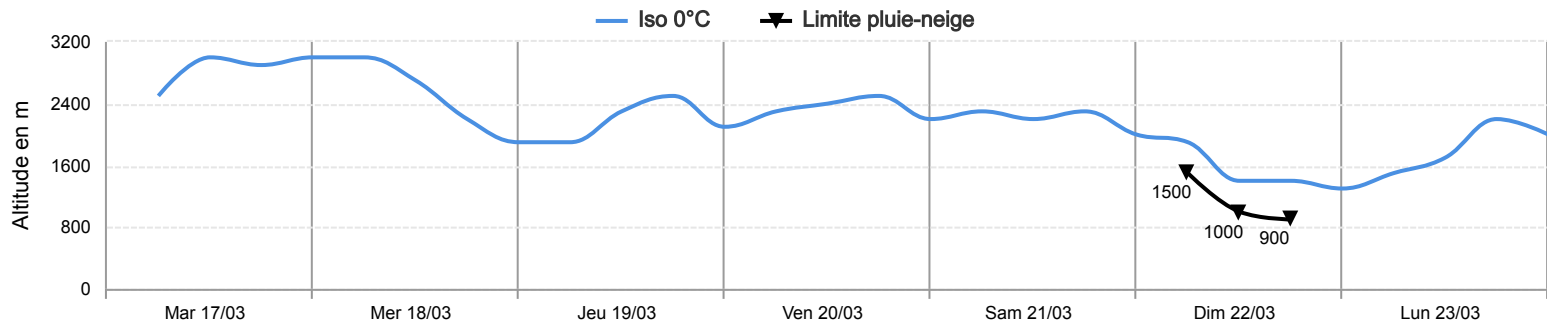

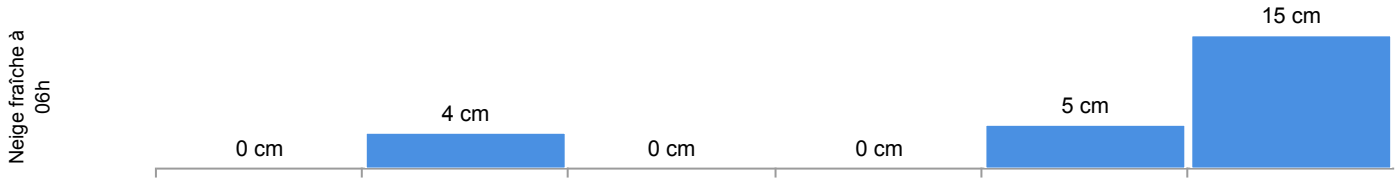

Risque d'avalanche	mar. 17/03	mer. 18/03	jeu. 19/03	ven. 20/03	sam. 21/03	dim. 22/03	lun. 23/03
	3	3	3	2	2	2	2

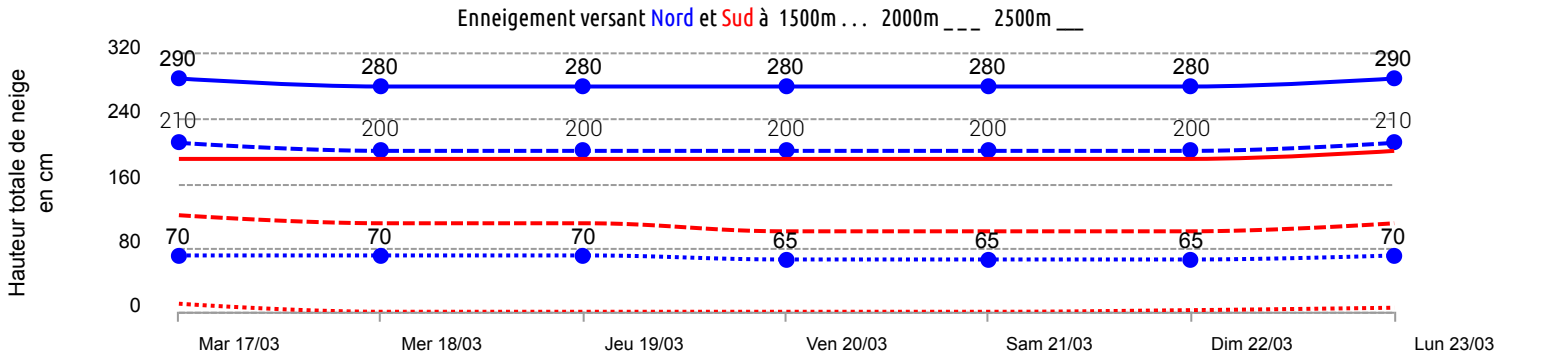

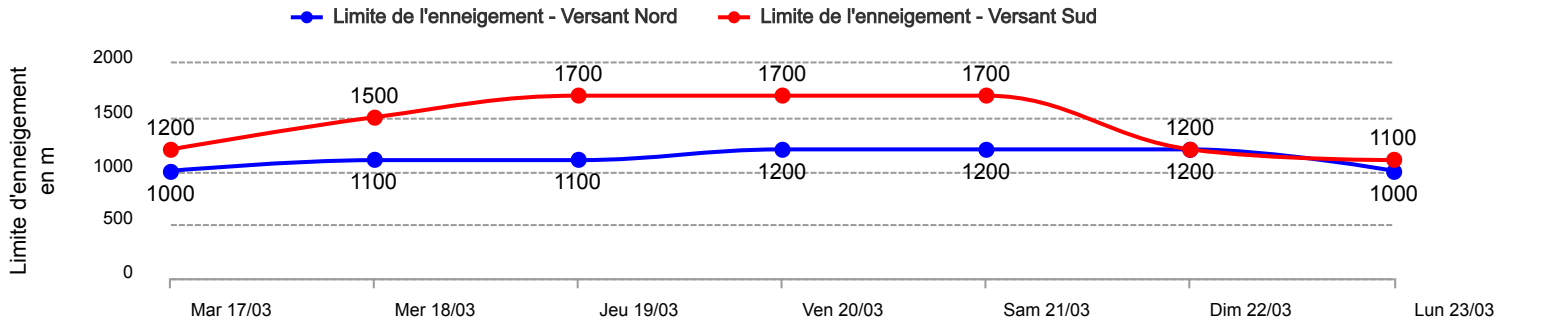

Pour consulter la vigilance en cours, veuillez vous rendre sur le site https://vigilance.meteofrance.fr/fr

Météo-France - 73 avenue de Paris, 94165 Saint-Mandé cedex - Contact : contact@meteo.fr

Rédigé par Météo-France avec la contribution des observateurs du réseau nivo-météorologiques. Partenariat : ANMSM (Maires de Stations de Montagne), DSF (Domaines Skiables de France), ADSP (Directeurs de Pistes et de la Sécurité des Stations de Sports d'Hiver) et autres acteurs de la montagne.

Bulletin neige & avalanches par téléphone au
0 892 68 10 20 Service 0,35 € / min + prix appel