Bulletin d'estimation du risque d'avalanche

(valable en dehors des pistes balisées et ouvertes)

MASSIF : Aravis

Rédigé le lundi 23 mars 2026 à 16h

Estimation des risques pour le : MARDI 24 MARS

MANTEAU NEIGEUX FROID VENTÉ EN ALTITUDE MAIS PLUS PRINTANIER SOUS 2300/2400 M.

2

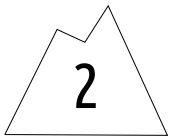

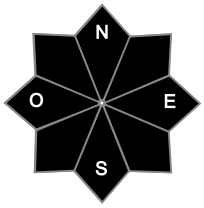

Indice de risque limité.

Départs spontanés : Petits départs de neige humide avec le réchauffement diurne.

Déclenchements provoqués : Plaques à vent formées par le vent de SO/SE à NE de ces derniers jours en altitude.

Indices de risque : 5 très fort - 4 fort - 3 marqué - 2 limité - 1 faible -- En noir : les pentes les plus dangereuses

Stabilité du manteau neigeux

Situation avalancheuse typique : neige ventée neige humide

Déclenchements provoqués :

* Vers les crêtes et arêtes : rares plaques à vent. Formées par le vent de NE. Les plaques sont globalement d'aspect friables. Déclenchables par un·e skieur·euse. Taille 1 à 2 (petite à moyenne).

Observables : accumulation de neige, vaguelettes, fissures sous les skis.

* Facteur aggravant : au-dessus de 2100 m en versants E/N/O : une couche fragile persistante enfouie est présente localement. Très difficilement déclenchable à skis mais elle peut être sollicitée par une forte surcharge (avalanche en cascade, chute de corniche...) et engendrer une avalanche de plus grande ampleur. Taille 2 (moyenne) à 3 (grande).
* De la neige humide peut couler sous les skis. Plus nombreux au fil de l'ensoleillement. Taille 1 (petite), rarement 2 (moyenne).

Départs spontanés :

* Petits départs en neige humide. Principalement dans les pentes raides au soleil et dans les rochers/falaises. Taille 1 (petite) rarement 2 (moyenne).
* Très rares plaques de fond : possibles en tous versants, à toute heure du jour comme de la nuit. Principalement dans les pentes raides et lisses (pentes herbeuses, dalles rocheuses). Taille 1 à 2 (petite à moyenne).

Qualité de la neige

Enneigement : Enneigement correct pour la saison. En-dessous de 1100/1300 m, la neige est presque inexistante.
On peut chausser les skis vers 1200/1300 m en versants peu ensoleillés et vers 1400/1500 m ailleurs.
Des grosses corniches sont présentes.

Qualité de la neige ce mardi :

* En-dessous de 2300/2400 m : croûte peu portante le matin qui décaille rapidement avec la course du soleil et le réchauffement diurne. La neige devient alors molle à humide.
* Au-dessus de 2300/2400 m : Neige encore froide, soit durcie travaillée par le vent de SO/SE puis de NE de ces derniers jours (surtout vers les crêtes/arêtes), soit encore légère et poudreuse (7/15 cm) sur un fond dur.

Aperçu météo pour le mardi 24 mars

nuit	matin	après-midi	soir

Ensoleillé, des cumulus se forment l'après-midi. Hausse de l'isotherme-0°C. Bise faible.

Pluie-Neige				
Iso 0 °C	1 900 m	2 200 m	2 200 m	2 600 m
Vent 2000 m	↓ 5 km/h	↙ 5 km/h	↻ 5 km/h	↻ 5 km/h
Vent 2500 m	↙ 10 km/h	↙ 15 km/h	↙ 15 km/h	↓ 10 km/h

Épaisseur de neige hors-piste

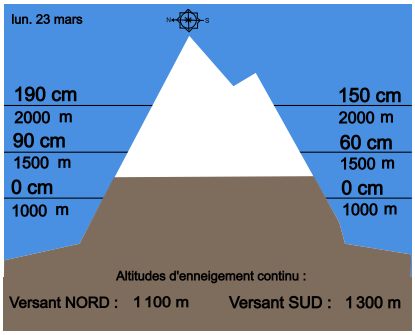

Précipitations à 1800 m

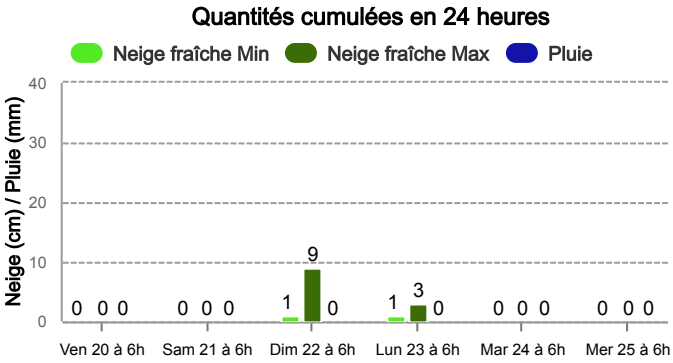

Tendance du mercredi 25 mars

2

Indice de risque limité

De nouvelles chutes de neige s'installent et le vent de Nord-Ouest à Nord se renforce. Formation de nouvelles instabilités dans cette neige fraîche, de plus en plus nombreuses au fil des chutes.

Pour consulter la vigilance en cours, veuillez vous rendre sur le site https://vigilance.meteofrance.fr/fr

Météo-France - 73 avenue de Paris, 94165 Saint-Mandé cedex - Contact : contact@meteo.fr

Rédigé par Météo-France avec la contribution des observateurs du réseau nivo-météorologiques. Partenariat : ANMSM (Maires de Stations de Montagne), DSF (Domaines Skiables de France), ADSP (Directeurs de Pistes et de la Sécurité des Stations de Sports d'Hiver) et autres acteurs de la montagne.

Bulletin neige & avalanches par téléphone au

0 892 68 10 20 Service 0,35 € / min + prix appel

RÉPUBLIQUE FRANÇAISE
Liberté Égalité Fraternité

METEO FRANCE
À VOS CÔTÉS, DANS UN CLIMAT QUI CHANGE

Bulletin d'estimation du risque d'avalanche
(valable en dehors des pistes balisées et ouvertes)

MASSIF : Aravis

Rédigé le lundi 23 mars 2026 à 16h

Conditions nivo-météo des 7 derniers jours

	mar. 17/03				mer. 18/03				jeu. 19/03				ven. 20/03				sam. 21/03				dim. 22/03				lun. 23/03			
	03h	09h	15h	21h	03h	09h	15h	21h	03h	09h	15h	21h	03h	09h	15h	21h	03h	09h	15h	21h	03h	09h	15h	21h	03h	09h	15h	21h
Météo																												
Vent (km/h)	25	30	30	35	45	20	60	50	25	30	25	30	30	20	10	10	10	15	15	15	30	35	40	15	20	30	25	20
à 2500m																												
Vent (km/h)	10	15	15	15	15	10	50	30	10	20	15	20	20	10	5	5	5	10	10	5	20	25	25	5	15	25	20	15
à 2000m																												

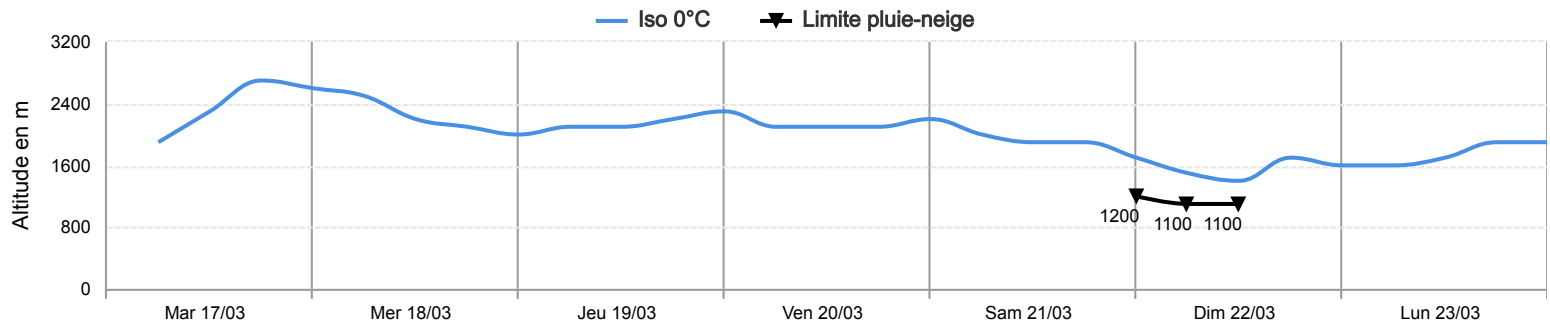

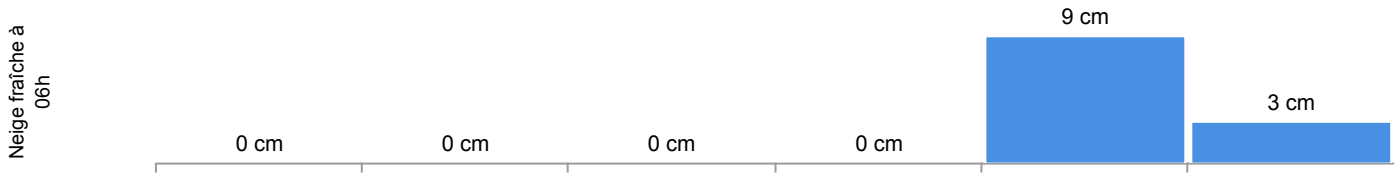

Risque d'avalanche	mar. 17/03	mer. 18/03	jeu. 19/03	ven. 20/03	sam. 21/03	dim. 22/03	lun. 23/03
	2	3	3	2	2	2	2

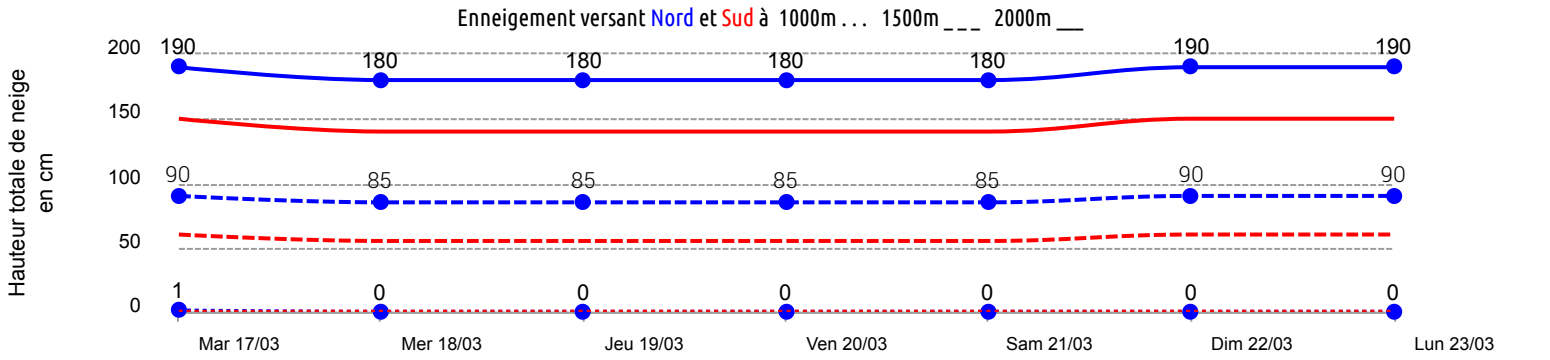

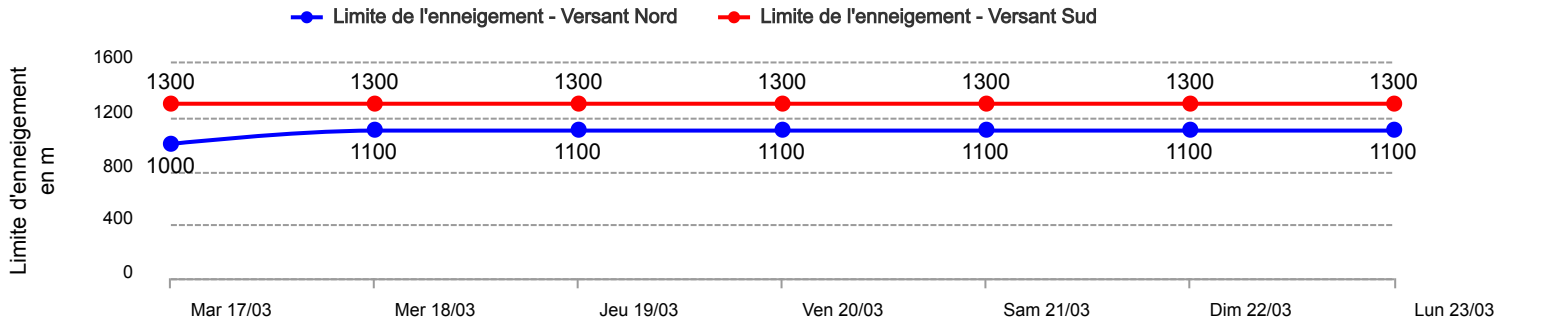

Pour consulter la vigilance en cours, veuillez vous rendre sur le site https://vigilance.meteofrance.fr/fr

Météo-France - 73 avenue de Paris, 94165 Saint-Mandé cedex - Contact : contact@meteo.fr

Rédigé par Météo-France avec la contribution des observateurs du réseau nivo-météorologiques. Partenariat : ANMSM (Maires de Stations de Montagne), DSF (Domaines Skiables de France), ADSP (Directeurs de Pistes et de la Sécurité des Stations de Sports d'Hiver) et autres acteurs de la montagne.

Bulletin neige & avalanches par téléphone au

0 892 68 10 20 Service 0,35 € / min + prix appel