Bulletin d'estimation du risque d'avalanche
(valable en dehors des pistes balisées et ouvertes)

MASSIF : Bauges

Rédigé le lundi 23 mars 2026 à 16h

Estimation des risques pour le : MARDI 24 MARS

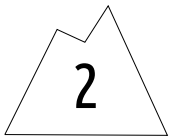

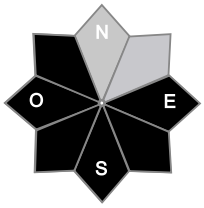

Indice de risque limité.

Départs spontanés : Petits départs de neige humide avec le réchauffement diurne.

Déclenchements provoqués : Neige humide sous les skis.

Indices de risque : 5 très fort - 4 fort - 3 marqué - 2 limité - 1 faible -- En noir : les pentes les plus dangereuses

Stabilité du manteau neigeux

Situation avalancheuse typique : neige humide

Déclenchements provoqués :
* De la neige humide peut couler sous les skis. Plus nombreux au fil de l'ensoleillement. Taille 1 (petite), rarement 2 (moyenne).
* Très rares plaques à vent, dans les pentes non chauffées par le soleil, au-dessus de 2000 m. Formées par le vent de NE. Les plaques sont globalement d'aspect friables. Déclenchables par un·e skieur·euse. Taille 1 à 2 (petite à moyenne).

Départs spontanés :
* Petits départs en neige humide. Principalement dans les pentes raides au soleil et dans les rochers/falaises. Taille 1 (petite) rarement 2 (moyenne).
* Très rares plaques de fond : possibles en tous versants, à toute heure du jour comme de la nuit. Principalement dans les pentes raides et lisses (pentes herbeuses, dalles rocheuses). Taille 1 à 2 (petite à moyenne).

Qualité de la neige

Enneigement : Enneigement correct pour la saison. On peut chausser les skis vers 1200/1300 m en versants peu ensoleillés et vers 1400/1500 m ailleurs.
Des grosses corniches sont présentes.

Qualité de la neige ce mardi :
Croûte peu portante le matin qui décaille rapidement avec la course du soleil et le réchauffement diurne. La neige devient alors molle à humide.

Aperçu météo pour le mardi 24 mars

nuit	matin	après-midi	soir

Ensoleillé, des cumulus se forment l'après-midi. Hausse de l'isotherme-0°C. Bise faible.

Pluie-Neige				
Iso 0 °C	1 900 m	2 300 m	2 300 m	2 600 m
Vent 1500 m	10 km/h	10 km/h	5 km/h	5 km/h
Vent 2000 m	15 km/h	15 km/h	10 km/h	5 km/h

Épaisseur de neige hors-piste

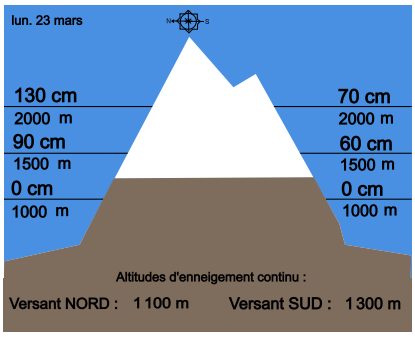

Précipitations à 1800 m

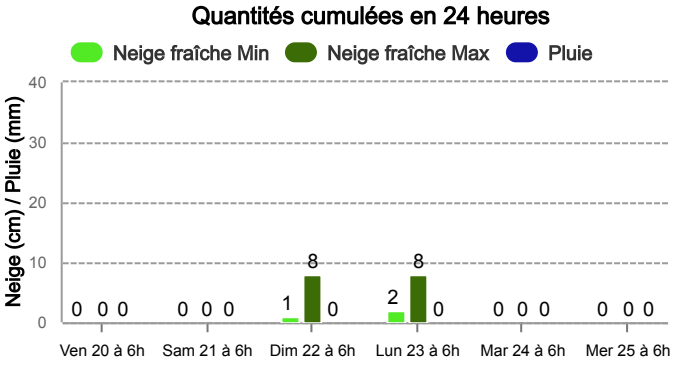

Tendance du mercredi 25 mars

Indice de risque limité

De nouvelles chutes de neige s'installent et le vent de Nord-Ouest à Nord se renforce. Formation de nouvelles instabilités dans cette neige fraîche, de plus en plus nombreuses au fil des chutes.

Pour consulter la vigilance en cours, veuillez vous rendre sur le site https://vigilance.meteofrance.fr/fr

Météo-France - 73 avenue de Paris, 94165 Saint-Mandé cedex - Contact : contact@meteo.fr

Rédigé par Météo-France avec la contribution des observateurs du réseau nivo-météorologiques. Partenariat : ANMSM (Maires de Stations de Montagne), DSF (Domaines Skiables de France), ADSP (Directeurs de Pistes et de la Sécurité des Stations de Sports d'Hiver) et autres acteurs de la montagne.

Bulletin neige & avalanches par téléphone au
0 892 68 10 20 Service 0,35 € / min + prix appel

RÉPUBLIQUE FRANÇAISE
Liberté Égalité Fraternité

METEO FRANCE
À VOS CÔTÉS, DANS UN CLIMAT QUI CHANGE

Bulletin d'estimation du risque d'avalanche
(valable en dehors des pistes balisées et ouvertes)

MASSIF : Bauges

Rédigé le lundi 23 mars 2026 à 16h

Conditions nivo-météo des 7 derniers jours

	mar. 17/03				mer. 18/03				jeu. 19/03				ven. 20/03				sam. 21/03				dim. 22/03				lun. 23/03			
	03h	09h	15h	21h	03h	09h	15h	21h	03h	09h	15h	21h	03h	09h	15h	21h	03h	09h	15h	21h	03h	09h	15h	21h	03h	09h	15h	21h
Météo																												
Vent (km/h)	25	25	30	30	25	20	70	40	40	20	20	20	15	10	5	5	5	10	10	10	20	25	35	10	20	20	25	30
à 2000m																												
Vent (km/h)	15	15	20	20	15	15	40	35	35	15	20	10	5	5	0	0	0	5	5	5	10	15	20	5	10	15	20	25
à 1500m																												

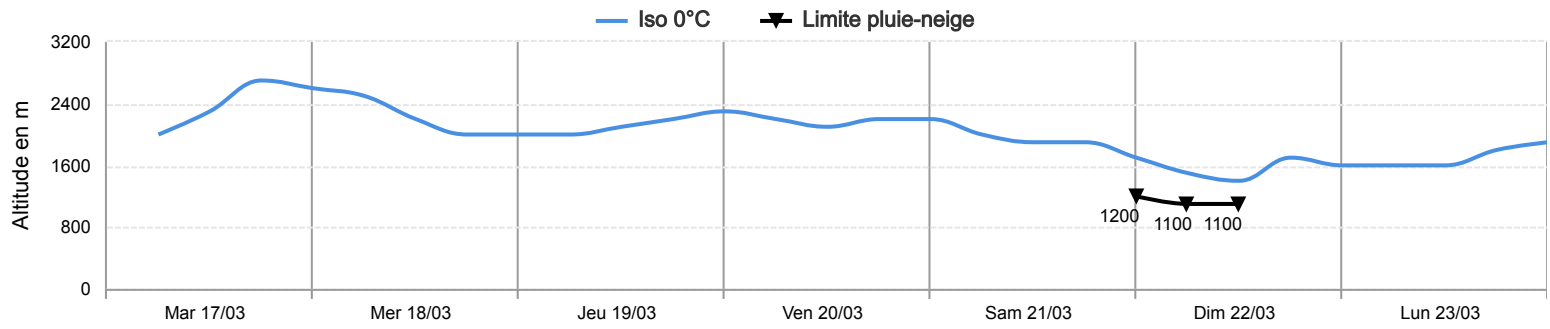

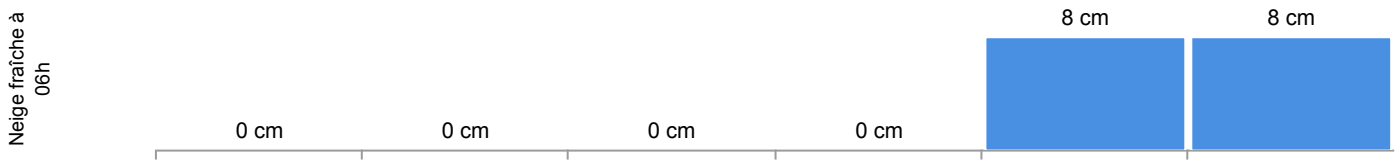

Risque d'avalanche	mar. 17/03	mer. 18/03	jeu. 19/03	ven. 20/03	sam. 21/03	dim. 22/03	lun. 23/03
	2	2	2	2	1	2	2

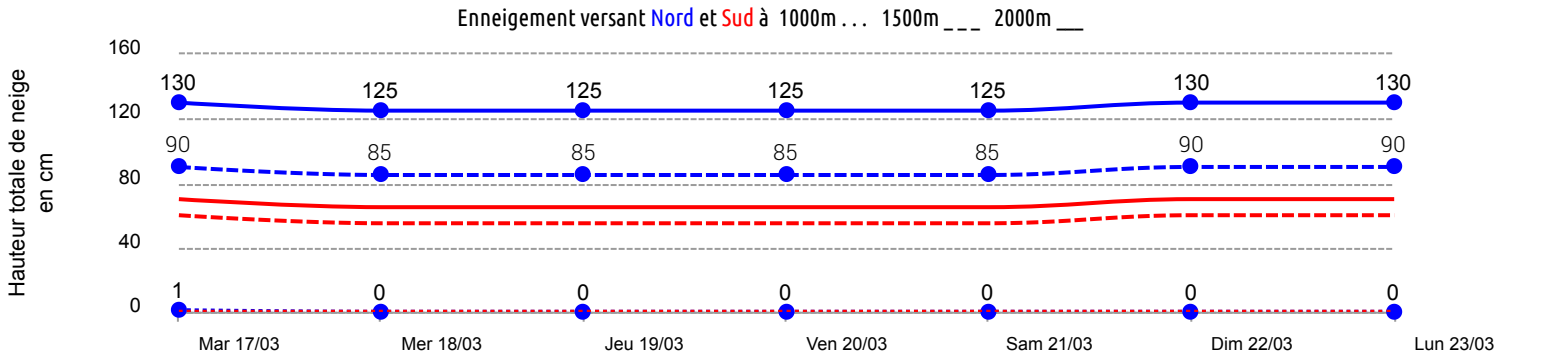

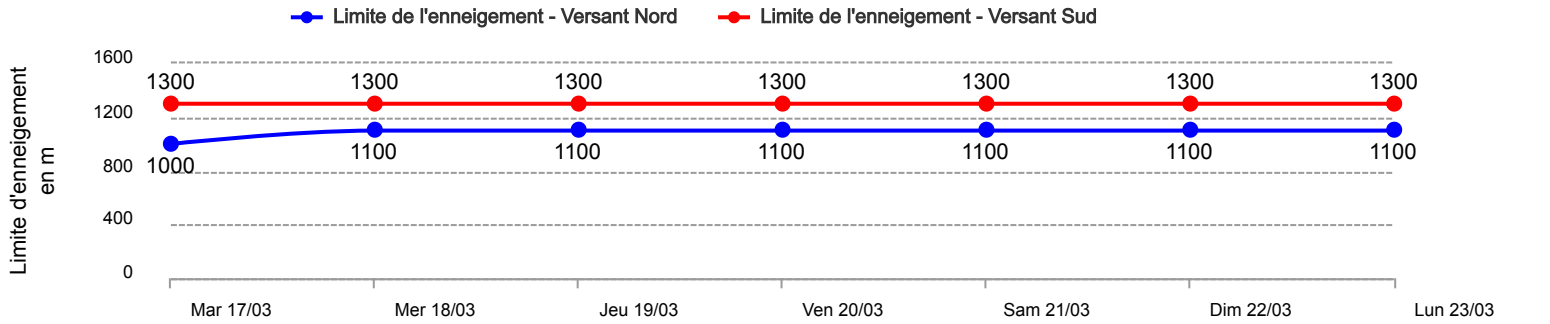

Pour consulter la vigilance en cours, veuillez vous rendre sur le site https://vigilance.meteofrance.fr/fr

Météo-France - 73 avenue de Paris, 94165 Saint-Mandé cedex - Contact : contact@meteo.fr

Rédigé par Météo-France avec la contribution des observateurs du réseau nivo-météorologiques. Partenariat : ANMSM (Maires de Stations de Montagne), DSF (Domaines Skiables de France), ADSP (Directeurs de Pistes et de la Sécurité des Stations de Sports d'Hiver) et autres acteurs de la montagne.

Bulletin neige & avalanches par téléphone au
0 892 68 10 20 Service 0,35 € / min + prix appel