Bulletin d'estimation du risque d'avalanche

(valable en dehors des pistes balisées et ouvertes)

MASSIF : Beaufortain

Rédigé le lundi 23 mars 2026 à 16h

Estimation des risques pour le : MARDI 24 MARS

MANTEAU PLUTÔT STABLE EN TRANSITION PRINTANIÈRE.

2

2

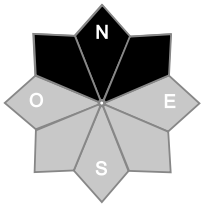

Indice de risque limité.

Départs spontanés : purges au soleil.

Déclenchements provoqués : quelques plaques en ubacs.

Indices de risque : 5 très fort - 4 fort - 3 marqué - 2 limité - 1 faible -- En noir : les pentes les plus dangereuses

Stabilité du manteau neigeux

Situation avalancheuse typique : neige ventée — neige humide

Déclenchements provoqués : Quelques plaques résiduelles sont en place suite à l'épisode transport de neige par le vent de ce dimanche. Elles sont globalement peu réactives mais encore déclenchables : en Nord là où il restait un peu de poudre, derrière les ruptures de pente et près des crêtes, en altitude. Taille 1 à 2 avec des cassures de 15 à 30 cm.
Observables : accumulation de neige derrière une rupture de pente, test de stabilité, fissures devant les skis.

Départs spontanés : Rares petits départs en poire sont possibles dans les pentes raides qui chauffent au soleil. Taille 1, rarement 2 si la pente le permet.

Qualité de la neige

Enneigement : Encore un peu au dessus de la moyenne, sauf aux plus basses altitudes où les hauteurs de neige sont tout juste correctes pour la saison.

Limite skiable : 1100 m au mieux en Nord. Plutôt 1400/1500 m en sud pas trop raide.

Qualité de la neige :
En adrets : manteau en cours de transition, seules les pentes Sud raides peuvent être en vraies conditions de printemps, alors qu'en Est et Ouest ou pente peu raide persiste une croûte peu voire pas portante par manque de cycle de regel. Partout, la surface s'humidifie en suivant la course du soleil.
En ubacs : on peut encore trouver de la poudreuse (10 à 20 cm), parfois un peu densifiée par le vent.

Aperçu météo pour le mardi 24 mars

	nuit	matin	après-midi	soir
Très belle journée. Petits cumulus sur les sommets l'après-midi. Grande douceur dans les adrets.				
Pluie-Neige				
Iso 0 °C	1 900 m	2 400 m	2 400 m	2 500 m
Vent 2000 m	5 km/h	5 km/h	10 km/h	5 km/h
Vent 3000 m	20 km/h	25 km/h	20 km/h	15 km/h

Épaisseur de neige hors-piste

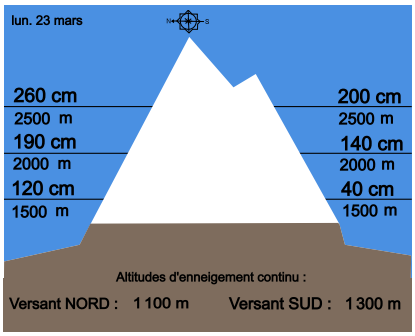

Précipitations à 1800 m

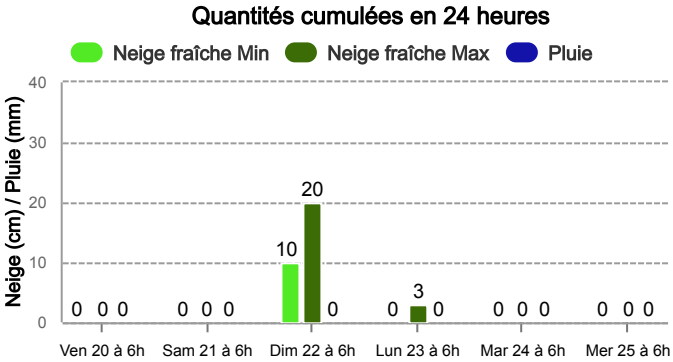

Tendance du mercredi 25 mars

2

Indice de risque limité

Dégradation l'après-midi, chutes de neige ventées prévus : aggravation du risque.

Pour consulter la vigilance en cours, veuillez vous rendre sur le site https://vigilance.meteofrance.fr/fr

Météo-France - 73 avenue de Paris, 94165 Saint-Mandé cedex - Contact : contact@meteo.fr

Rédigé par Météo-France avec la contribution des observateurs du réseau nivo-météorologiques. Partenariat : ANMSM (Maires de Stations de Montagne), DSF (Domaines Skiables de France), ADSP (Directeurs de Pistes et de la Sécurité des Stations de Sports d'Hiver) et autres acteurs de la montagne.

Bulletin neige & avalanches par téléphone au 0 892 68 10 20 Service 0,35 € / min + prix appel

RÉPUBLIQUE FRANÇAISE
Liberté Égalité Fraternité

METEO FRANCE
À VOS CÔTÉS, DANS UN CLIMAT QUI CHANGE

Bulletin d'estimation du risque d'avalanche

(valable en dehors des pistes balisées et ouvertes)

MASSIF : Beaufortain

Rédigé le lundi 23 mars 2026 à 16h

Conditions nivo-météo des 7 derniers jours

	mar. 17/03				mer. 18/03				jeu. 19/03				ven. 20/03				sam. 21/03				dim. 22/03				lun. 23/03			
	03h	09h	15h	21h	03h	09h	15h	21h	03h	09h	15h	21h	03h	09h	15h	21h	03h	09h	15h	21h	03h	09h	15h	21h	03h	09h	15h	21h
Météo																												
Vent (km/h)	20	20	20	20	20	35	60	50	35	20	20	20	25	25	15	10	15	25	20	15	15	25	20	10	20	30	25	20
à 3000m																												
Vent (km/h)	10	10	10	10	10	20	40	35	20	10	10	10	5	5	0	0	5	10	20	10	10	30	25	15	10	10	15	10
à 2000m																												

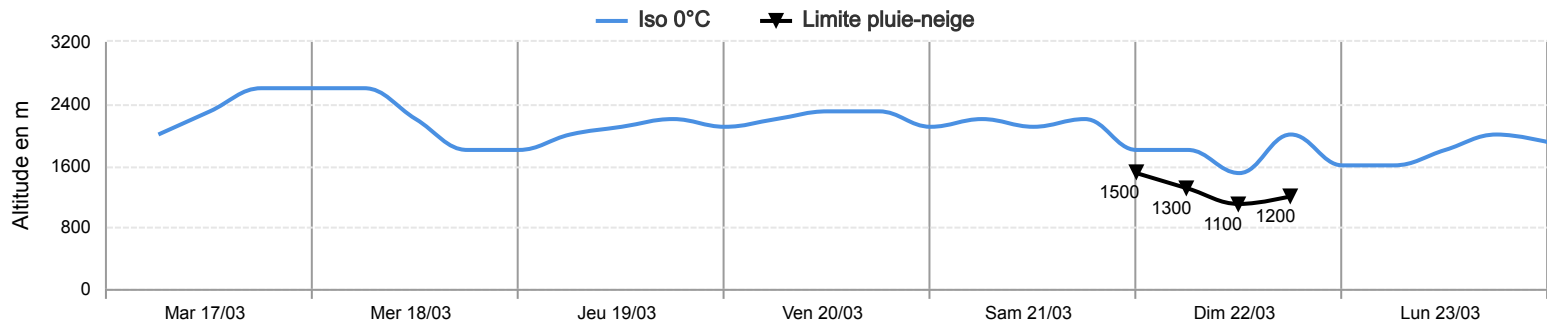

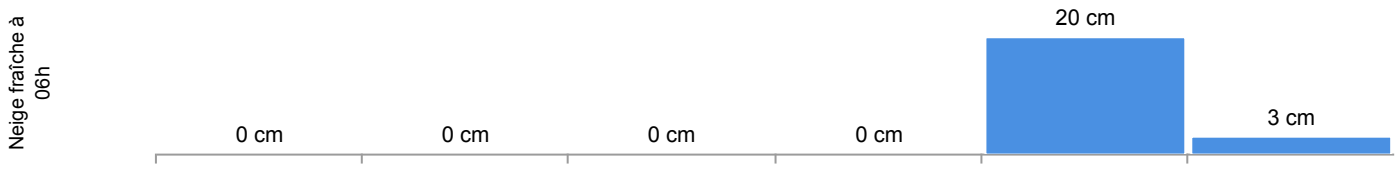

Risque d'avalanche	mar. 17/03	mer. 18/03	jeu. 19/03	ven. 20/03	sam. 21/03	dim. 22/03	lun. 23/03
	2	3	3	2	2	2	2

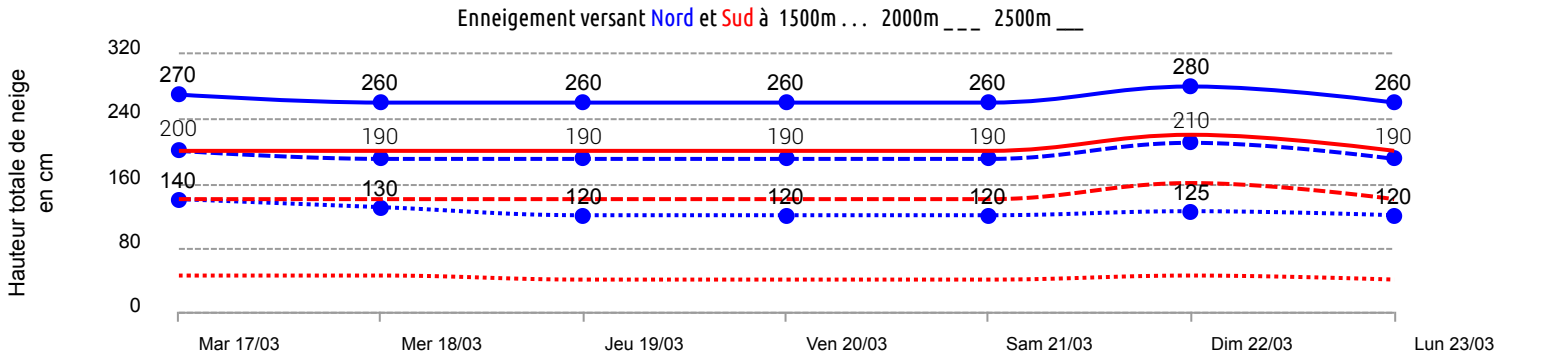

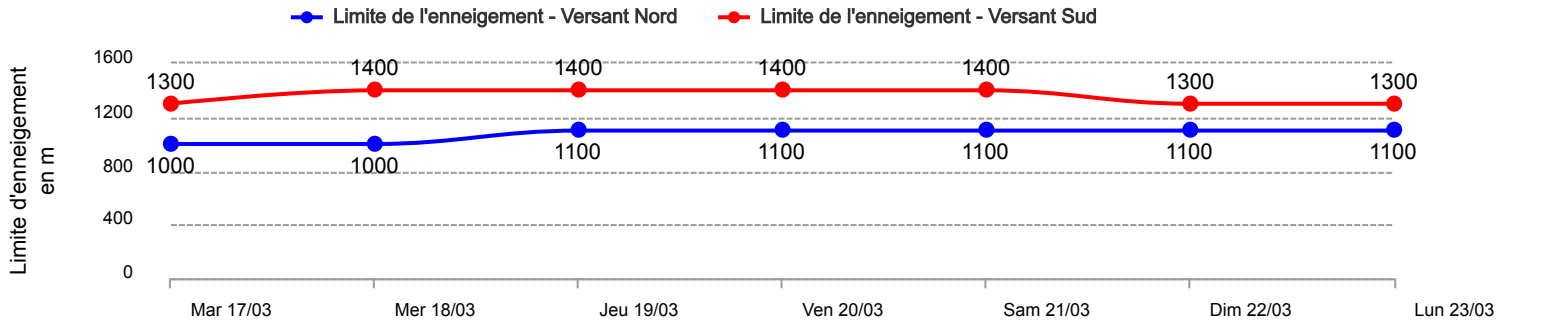

Pour consulter la vigilance en cours, veuillez vous rendre sur le site https://vigilance.meteofrance.fr/fr

Météo-France - 73 avenue de Paris, 94165 Saint-Mandé cedex - Contact : contact@meteo.fr

Rédigé par Météo-France avec la contribution des observateurs du réseau nivo-météorologiques. Partenariat : ANMSM (Maires de Stations de Montagne), DSF (Domaines Skiables de France), ADSP (Directeurs de Pistes et de la Sécurité des Stations de Sports d'Hiver) et autres acteurs de la montagne.

Bulletin neige & avalanches par téléphone au

0 892 68 10 20 Service 0,35 € / min + prix appel