Bulletin d'estimation du risque d'avalanche

(valable en dehors des pistes balisées et ouvertes)

MASSIF : Cerdagne Canigou

Rédigé le lundi 23 mars 2026 à 16h

Estimation des risques pour le : MARDI 24 MARS

PLAQUES EN HAUTE MONTAGNE, NEIGE HUMIDE EN SECONDE PARTIE DE JOURNÉE SURTOUT.

2

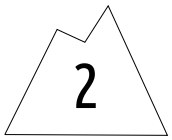

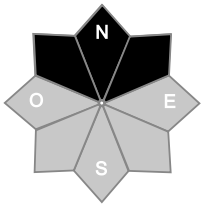

Indice de risque limité.

Départs spontanés : Avalanches de fond ou de neige humide avec la hausse du mercure, surtout après la mi journée.

Déclenchements provoqués : Quelques plaques à vent localisés, possibles dès 2100/2200 m, mais surtout au delà de 2500 m en versants froids.

Indices de risque : 5 très fort - 4 fort - 3 marqué - 2 limité - 1 faible -- En noir : les pentes les plus dangereuses

Stabilité du manteau neigeux

Situation avalancheuse typique : couche fragile persistante neige humide

Déclenchements provoqués :

- Quelques structures de plaques de faible épaisseur ont pu se former durant le bref épisode perturbé de dimanche soir.

Au delà de 2100/2200 m, une instabilité demeure localement dans les 10/20 cm de neige récente accumulée localement sous certaines crêtes, plutôt dans une large secteur nord, déclenchable par un skieur.

En haute montagne (> 2500 m), les conditions demeurent hivernales dans les versants froids, et des plaques reposant sur d'anciennes sous-couches fragiles persistantes sont toujours à envisager (neige roulée ou givre de surface).
Elles sont localisées dans les pentes sommitales des crêtes frontalières. Cassures de 30/40 cm éventuellement possibles en cas de déclenchement.

Observables : neige récente travaillée par le vent, enfoncement des bâtons supérieur à 20/30 cm, fissures devant les skis.

Départs spontanés :

Avec le soleil et la hausse du mercure, l'humidification reprend jusqu'à haute altitude dans les pentes ensoleillées. Petite activité avalancheuse mobilisant la petite couche de neige récente possible en matinée taille 1 (couloirs raides ensoleillés).
Ponctuellement dans les pentes très raides, possibilité d'une avalanche (éventuellement de fond) de plus grande taille dans un versant surchauffé par le soleil, préférentiellement après la mi-journée.

Qualité de la neige

Enneigement :

Enneigement reste très bon pour la saison, après plusieurs hivers déficitaires.
En altitude, les cumuls sont très conséquents mais les crêtes et sommets exposés au vent d'Ouest à Nord-ouest sont parfois complètement déneigés.
On peut encore chausser les skis dans les secteurs ombragés vers 1700/1800 m en configuration très favorable.

Qualité de la neige :

7/15 centimètres de neige récente sont tombés ici et là dans la nuit de dimanche à lundi, et devraient encore être présents dans les pentes au-delà de 2000 m ou le soleil demeure rasant.
Partout ailleurs, après un bon et fort regel matinal, reprise de l'humidification en surface et neige ramollie plus ou moins en profondeur suivant l'altitude et les expositions.

Aperçu météo pour le mardi 24 mars

	nuit	matin	après-midi	soir
grand beau temps doux et ensoleillé.				
Pluie-Neige				
Iso 0 °C	2 200 m	2 500 m	2 600 m	3 000 m
Vent 2000 m	↘ 15 km/h	↙ 10 km/h	↗ 10 km/h	↘ 10 km/h
Vent 3000 m	↘ 25 km/h	↘ 20 km/h	↑ 20 km/h	↘ 20 km/h

Pour consulter la vigilance en cours, veuillez vous rendre sur le site https://vigilance.meteofrance.fr/fr

Météo-France - 73 avenue de Paris, 94165 Saint-Mandé cedex - Contact : contact@meteo.fr

Rédigé par Météo-France avec la contribution des observateurs du réseau nivo-météorologiques. Partenariat : ANMSM (Maires de Stations de Montagne), DSF (Domaines Skiables de France), ADSP (Directeurs de Pistes et de la Sécurité des Stations de Sports d'Hiver) et autres acteurs de la montagne.

Bulletin neige & avalanches par téléphone au 0 892 68 10 20 Service 0,35 € / min + prix appel

RÉPUBLIQUE FRANÇAISE
Liberté Égalité Fraternité

METEO FRANCE
À VOS CÔTÉS, DANS UN CLIMAT QUI CHANGE

Bulletin d'estimation du risque d'avalanche
(valable en dehors des pistes balisées et ouvertes)

MASSIF : Cerdagne Canigou

Rédigé le lundi 23 mars 2026 à 16h

Épaisseur de neige hors-piste

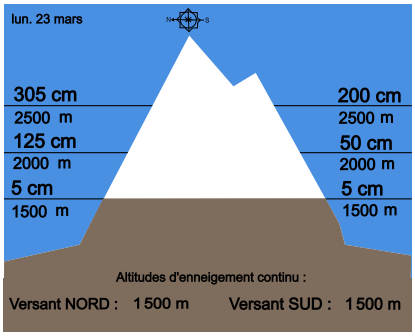

Précipitations à 1800 m

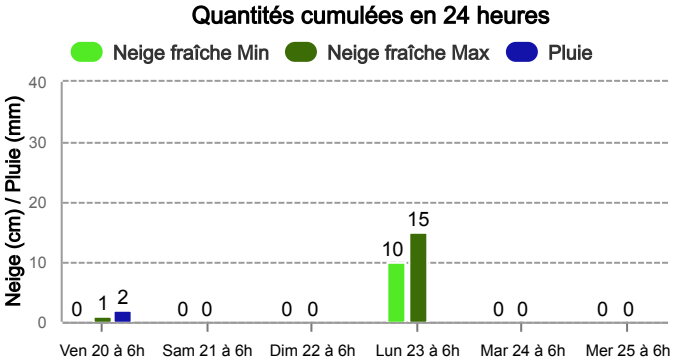

Tendance du mercredi 25 mars

Indice de risque limité

Stationnaires.

Pour consulter la vigilance en cours, veuillez vous rendre sur le site https://vigilance.meteofrance.fr/fr

Météo-France - 73 avenue de Paris, 94165 Saint-Mandé cedex - Contact : contact@meteo.fr

Rédigé par Météo-France avec la contribution des observateurs du réseau nivo-météorologiques. Partenariat : ANMSM (Maires de Stations de Montagne), DSF (Domaines Skiables de France), ADSP (Directeurs de Pistes et de la Sécurité des Stations de Sports d'Hiver) et autres acteurs de la montagne.

Bulletin neige & avalanches par téléphone au
0 892 68 10 20 Service 0,35 € / min + prix appel

Bulletin d'estimation du risque d'avalanche

(valable en dehors des pistes balisées et ouvertes)

MASSIF : Cerdagne Canigou

Rédigé le lundi 23 mars 2026 à 16h

Conditions nivo-météo des 7 derniers jours

	mar. 17/03				mer. 18/03				jeu. 19/03				ven. 20/03				sam. 21/03				dim. 22/03				lun. 23/03			
	03h	09h	15h	21h	03h	09h	15h	21h	03h	09h	15h	21h	03h	09h	15h	21h	03h	09h	15h	21h	03h	09h	15h	21h	03h	09h	15h	21h
Météo																												
Vent (km/h)	45	25	15	15	15	15	20	30	35	35	30	25	20	20	20	25	15	15	20	20	25	25	35	45	50	50	40	30
à 3000m																												
Vent (km/h)	25	15	10	10	10	10	15	20	25	25	20	10	10	10	10	10	10	10	15	10	15	15	25	35	35	35	30	20
à 2000m																												

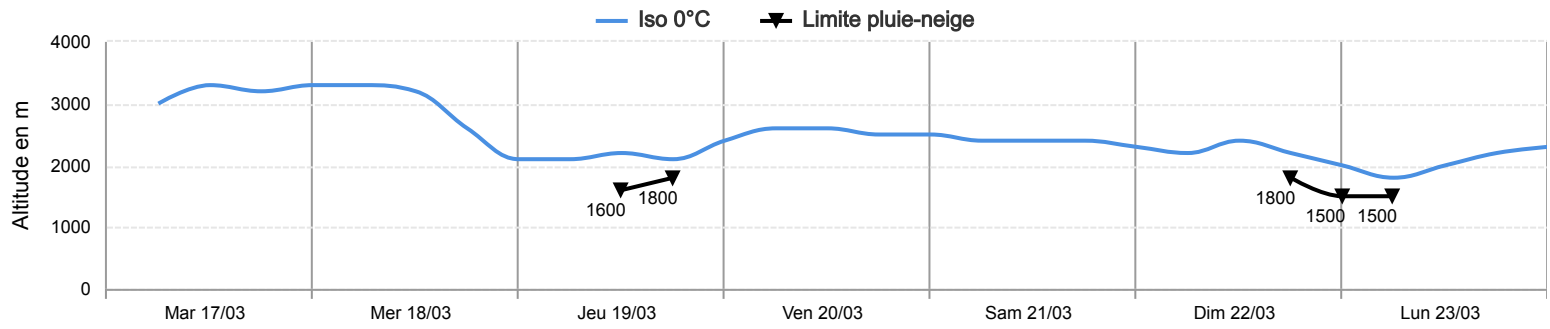

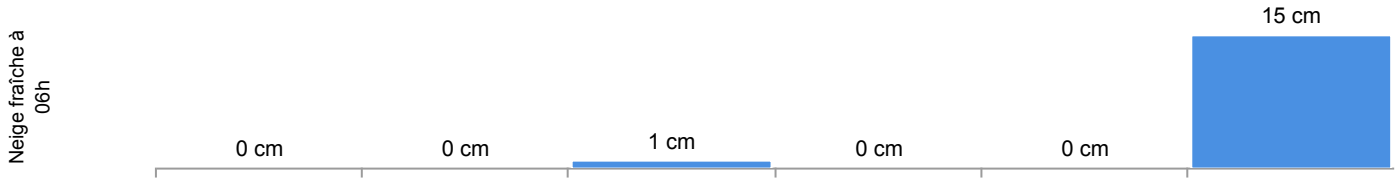

Risque d'avalanche	mar. 17/03	mer. 18/03	jeu. 19/03	ven. 20/03	sam. 21/03	dim. 22/03	lun. 23/03
	3	3	2	2	2	2	2

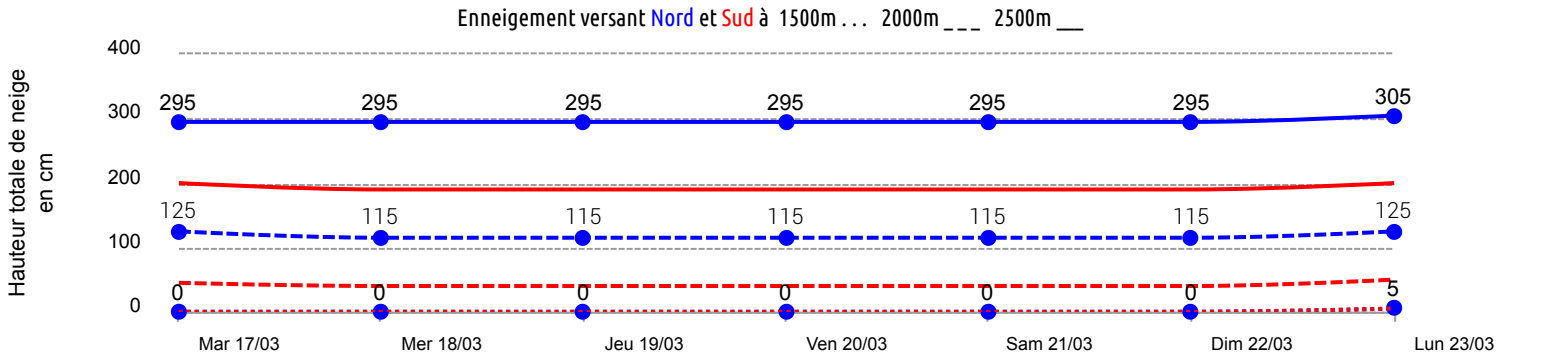

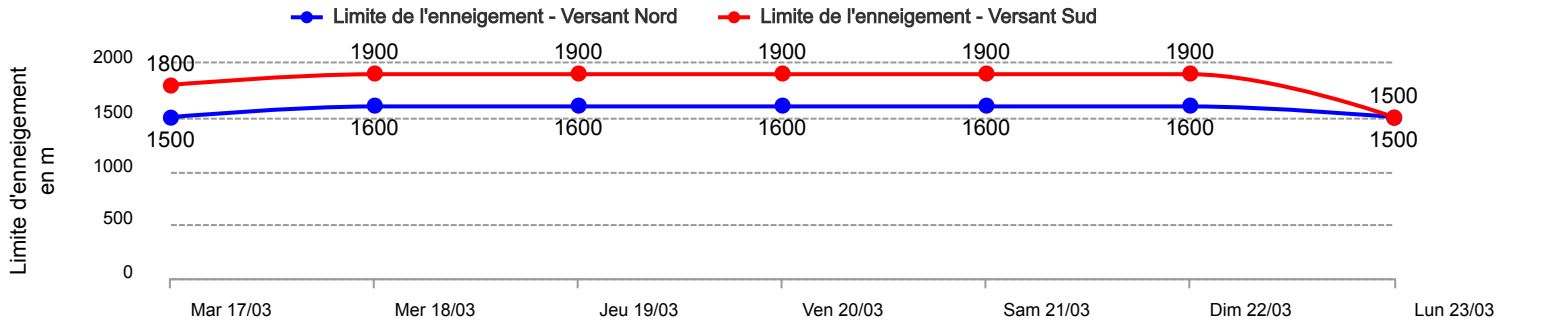

Pour consulter la vigilance en cours, veuillez vous rendre sur le site https://vigilance.meteofrance.fr/fr

Météo-France - 73 avenue de Paris, 94165 Saint-Mandé cedex - Contact : contact@meteo.fr

Rédigé par Météo-France avec la contribution des observateurs du réseau nivo-météorologiques. Partenariat : ANMSM (Maires de Stations de Montagne), DSF (Domaines Skiables de France), ADSP (Directeurs de Pistes et de la Sécurité des Stations de Sports d'Hiver) et autres acteurs de la montagne.

Bulletin neige & avalanches par téléphone au

0 892 68 10 20 Service 0,35 € / min + prix appel