Bulletin d'estimation du risque d'avalanche

(valable en dehors des pistes balisées et ouvertes)

MASSIF : Cinto Rotondo

Rédigé le lundi 23 mars 2026 à 16h

Estimation des risques pour le : MARDI 24 MARS

PERSISTANCE D'INSTABILITÉS EN ALTITUDE DANS LA NEIGE RÉCENTE VENTÉE, QUELQUES COULÉES DE NEIGE HUMIDE EN JOURNÉE DANS LES PENTES ENSOLEILLÉES

2

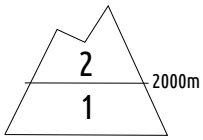

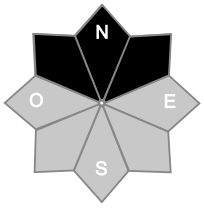

Au-dessus de 2000m indice de risque limité, plus bas indice faible.

Départs spontanés : Quelques coulées de neige fraîche ce lundi soir après les averses de neige sur l'Ouest du massif, puis quelques coulées de neige humide en journée de mardi dans les pentes ensoleillées

Déclenchements provoqués : Plaques à vent difficilement sollicitables, encore présentes en altitude au-dessus de 2000 m

Indices de risque : 5 très fort - 4 fort - 3 marqué - 2 limité - 1 faible -- En noir : les pentes les plus dangereuses

Stabilité du manteau neigeux

Situation avalancheuse typique : neige ventée

Déclenchements provoqués : De rares plaques sont encore en place en altitude dans les pentes Nord-Ouest à Nord-Est, au-dessus de 2000 m environ. Certaines instabilités peuvent encore céder au passage d'un skieur dans les pentes raides, parfois cachées sous une fine couche de neige fraîche. Elles peuvent engendrer des avalanches de taille petite à moyenne (taille 1 à 2).
En dessous de 2000 m, la neige fraîche repose sur une sous-couche regelée et plus stable.
Départs spontanés : Ce lundi après-midi, des averses déposent quelques centimètres de neige fraîche sur l'Ouest du massif. Jusqu'en soirée, quelques coulées de neige fraîche se déclenchent dans les pentes raides, voire quelques avalanches de taille moyenne (taille 1 à 2).
En journée de mardi, à la faveur de l'ensoleillement, la couche de neige récente s'humidifie et des coulées se produisent dans les pentes Sud-Est à Sud-Ouest, voire une avalanche de taille moyenne.
Autres : Nombreuses surfaces dures et glacées, pouvant être recouvertes de quelques centimètres de neige fraîche.
Présence de corniches parfois volumineuses, dont certaines commencent à se détacher (apparition de fissures).

Qualité de la neige

Qualification de l'enneigement : L'enneigement est excellent pour la saison au-dessus de 1600 m. Sur la Maniccia, à 2400 m d'altitude dans le massif du Rotondo, on relève 3m15 de hauteur de neige totale.
Limite d'enneigement skiable : 1500 à 1600 m selon le versant.
État de la neige : La neige récente s'est humidifiée en surface dans les pentes SE à SO bien exposées au soleil, surtout en dessous de 2000m. Plus haut, en pentes NE à NO, elle reste plus froide et assez légère, ou bien densifiée ou durcie sur les zones qui ont été exposées au Grecale. Le net refroidissement a permis une consolidation par regel des couches de neige humide. Les croûtes épaisses et les surfaces dures sont très fréquentes, pouvant être recouvertes de quelques centimètres de neige fraîche sur l'Ouest du massif. À noter également la présence de corniches parfois volumineuses.

Aperçu météo pour le mardi 24 mars

	nuit	matin	après-midi	soir
Ciel dégagé.				
Pluie-Neige				
Iso 0 °C	1 700 m	1 800 m	2 100 m	2 200 m
Vent 1500 m	25 km/h	20 km/h	15 km/h	15 km/h
Vent 3000 m	30 km/h	30 km/h	30 km/h	25 km/h

Épaisseur de neige hors-piste

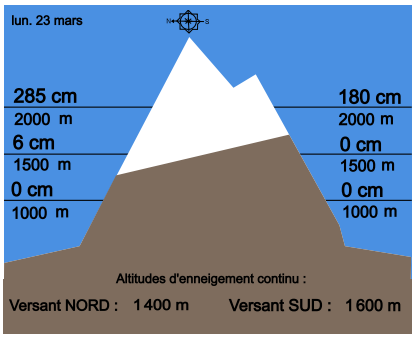

Précipitations à 1800 m

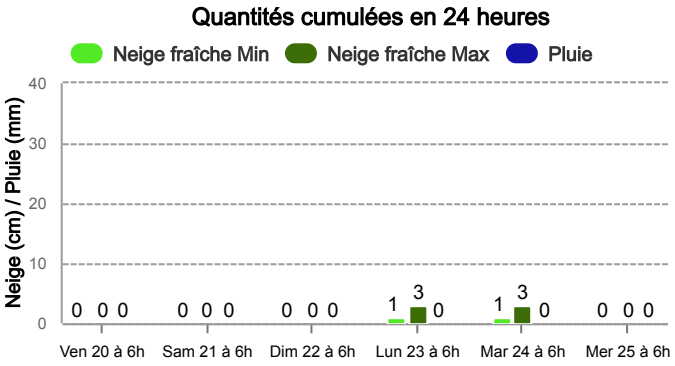

Tendance du mercredi 25 mars

2 **Indice de risque limité**

Conditions bien ensoleillées et net redoux, engendrant des coulées de neige humide et quelques avalanches de taille moyenne, notamment en moyenne montagne ainsi que dans les orientations Sud plus en altitude. En versants Nord, les dernières plaques se stabilisent grâce au redoux.

Pour consulter la vigilance en cours, veuillez vous rendre sur le site https://vigilance.meteofrance.fr/fr

Météo-France - 73 avenue de Paris, 94165 Saint-Mandé cedex - Contact : contact@meteo.fr

Rédigé par Météo-France avec la contribution des observateurs du réseau nivo-météorologiques. Partenariat : ANMSM (Maires de Stations de Montagne), DSF (Domaines Skiables de France), ADSP (Directeurs de Pistes et de la Sécurité des Stations de Sports d'Hiver) et autres acteurs de la montagne.

Bulletin neige & avalanches par téléphone au 0 892 68 10 20 Service 0,35 € / min + prix appel

RÉPUBLIQUE FRANÇAISE
Liberté Égalité Fraternité

METEO FRANCE
À VOS CÔTÉS, DANS UN CLIMAT QUI CHANGE

Bulletin d'estimation du risque d'avalanche

(valable en dehors des pistes balisées et ouvertes)

MASSIF : Cinto Rotondo

Rédigé le lundi 23 mars 2026 à 16h

Conditions nivo-météo des 7 derniers jours

	mar. 17/03				mer. 18/03				jeu. 19/03				ven. 20/03				sam. 21/03				dim. 22/03				lun. 23/03			
	03h	09h	15h	21h	03h	09h	15h	21h	03h	09h	15h	21h	03h	09h	15h	21h	03h	09h	15h	21h	03h	09h	15h	21h	03h	09h	15h	21h
Météo																												
Vent (km/h)	50	45	35	40	45	35	40	65	45	30	50	80	80	80	40	50	50	30	15	20	15	20	15	10	10	15	20	40
à 3000m																												
Vent (km/h)	5	10	5	10	10	30	20	25	40	35	20	30	30	30	25	25	25	15	10	10	5	10	5	5	5	10	15	30
à 1500m																												

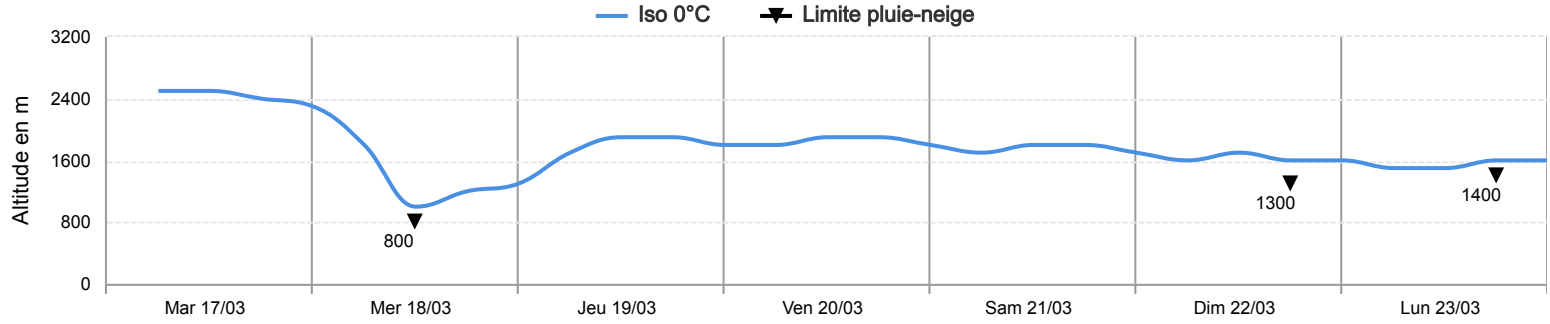

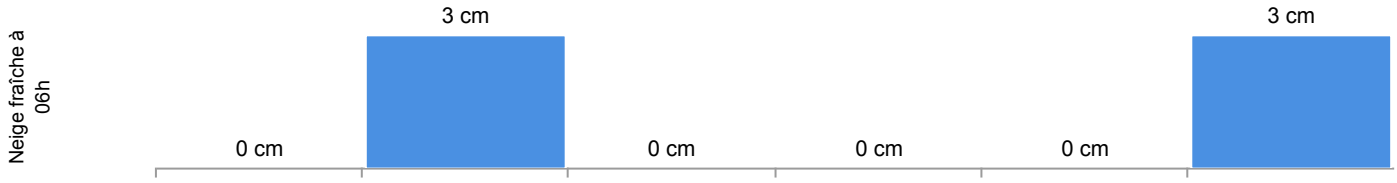

Risque d'avalanche	mar. 17/03	mer. 18/03	jeu. 19/03	ven. 20/03	sam. 21/03	dim. 22/03	lun. 23/03
	2	2	2	2	2	2	2

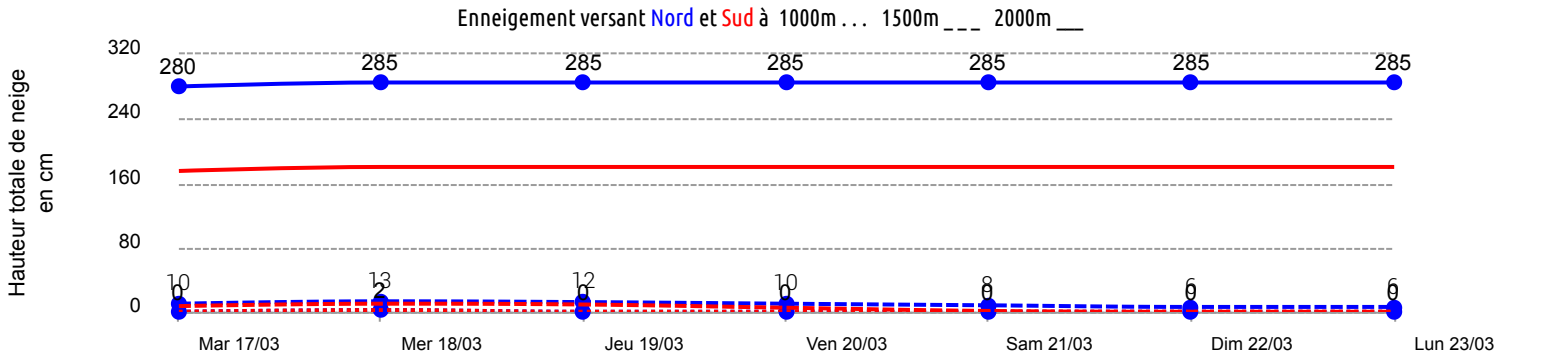

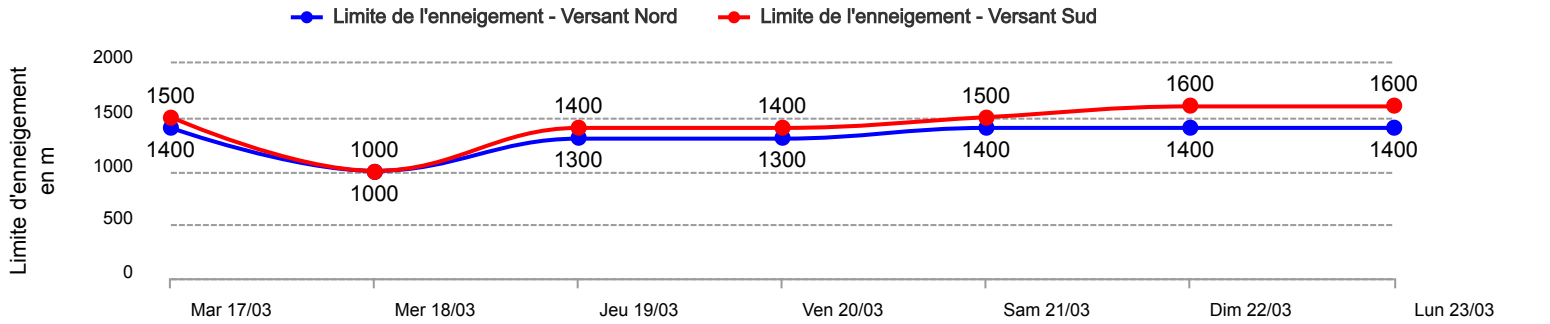

Pour consulter la vigilance en cours, veuillez vous rendre sur le site https://vigilance.meteofrance.fr/fr

Météo-France - 73 avenue de Paris, 94165 Saint-Mandé cedex - Contact : contact@meteo.fr

Rédigé par Météo-France avec la contribution des observateurs du réseau nivo-météorologiques. Partenariat : ANMSM (Maires de Stations de Montagne), DSF (Domaines Skiables de France), ADSP (Directeurs de Pistes et de la Sécurité des Stations de Sports d'Hiver) et autres acteurs de la montagne.

Bulletin neige & avalanches par téléphone au
0 892 68 10 20 Service 0,35 € / min + prix appel