Bulletin d'estimation du risque d'avalanche

(valable en dehors des pistes balisées et ouvertes)

MASSIF : Queyras

Rédigé le lundi 23 mars 2026 à 16h

Estimation des risques pour le : MARDI 24 MARS

ENCORE QUELQUES INSTABILITÉS DANS LA NEIGE RÉCENTE. UN PEU D'ACTIVITÉ NATURELLE AU SOLEIL.

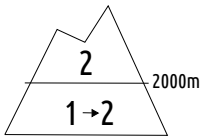

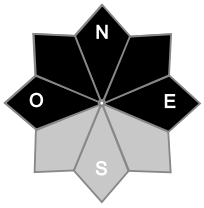

Au-dessus de 2000m indice de risque limité, plus bas indice faible évoluant en limité.

Départs spontanés : quelques départs ponctuels en neige humide au soleil

Déclenchements provoqués : quelques avalanches de plaque en neige sèche récente en altitude, encore faciles à déclencher

Indices de risque : 5 très fort - 4 fort - 3 marqué - 2 limité - 1 faible -- En noir : les pentes les plus dangereuses

Stabilité du manteau neigeux

Situation avalancheuse typique : neige ventée neige humide

Déclenchements provoqués : quelques plaques à vent dans la neige récente, encore déclenchables par un skieur. Principalement présentes dans les orientations est / nord /ouest au-dessus de 2000/2200 m, plutôt aux abords des ruptures de pente et des crêtes. Avalanches de taille petite à moyenne.
Par ailleurs, un skieur évoluant tardivement en pente raide ensoleillée peut provoquer un départ ponctuel en neige humide.

Départs spontanés : quelques départs ponctuels en neige humide. Peu probables en début de journée, puis devenant possibles dès la fin de matinée en pentes raides ensoleillées. Avalanches de petite taille à moyenne.

Qualité de la neige

L'enneigement est proche des normales à excédentaire pour une fin mars.
Hauteurs de neige observées : 168 cm en versant nord du col Izoard à 2300 m, 154 cm au-dessus de St Véran à 2700 m, 108 cm à la Nivôse du Col Agnel à 2630 m, 60cm à Ristolas à 1670 m.

Limite d'enneigement skiable : au plus bas à 1600 m en ubacs bien protégés ou sur pistes forestières, plutôt 2000 m en adrets.

État de la neige de surface : 10/20 cm de neige récente, localement 20/40 cm secteur Ceillac/St Véran/Col Agnel, reposant généralement sur un fond dur/regelé, mais en ubacs au-dessus de 2200/2300 m sur de la neige sèche. Regelée en surface sous 1800/2100 m, s'humidifiant au soleil jusqu'à haute altitude en journée.

Aperçu météo pour le mardi 24 mars

nuit	matin	après-midi	soir

Nuit froide et claire. Mardi, bien ensoleillé. Redoux en adrets.

Pluie-Neige				
Iso 0 °C	2 100 m	2 300 m	2 500 m	2 600 m
Vent 2000 m	← 10 km/h	↗ 10 km/h	↗ 15 km/h	→ 5 km/h
Vent 3000 m	← 15 km/h	↘ 10 km/h	→ 15 km/h	→ 10 km/h

Épaisseur de neige hors-piste

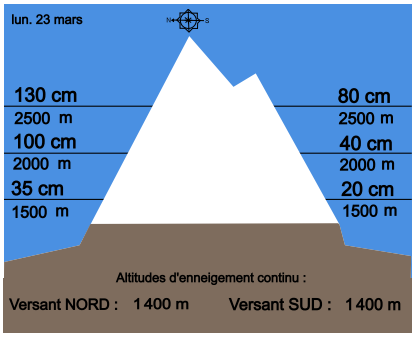

Précipitations à 1800 m

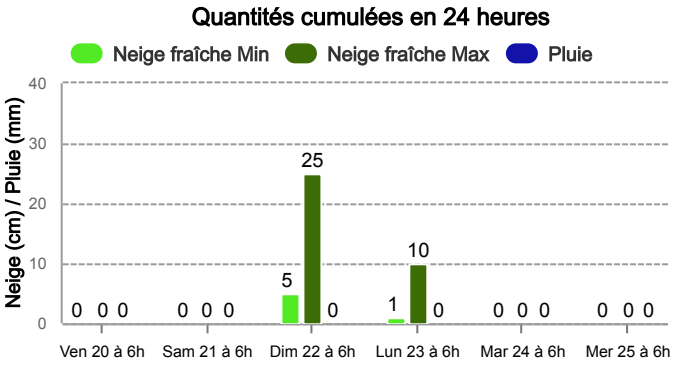

Tendance du mercredi 25 mars

Indice de risque limité

Risque limité. Rares plaques résiduelles, mais d'autres en formation vers les hauts sommets avec le vent. Activité naturelle limitée.

Pour consulter la vigilance en cours, veuillez vous rendre sur le site https://vigilance.meteofrance.fr/fr

Météo-France - 73 avenue de Paris, 94165 Saint-Mandé cedex - Contact : contact@meteo.fr

Rédigé par Météo-France avec la contribution des observateurs du réseau nivo-météorologiques. Partenariat : ANMSM (Maires de Stations de Montagne), DSF (Domaines Skiables de France), ADSP (Directeurs de Pistes et de la Sécurité des Stations de Sports d'Hiver) et autres acteurs de la montagne.

Bulletin neige & avalanches par téléphone au
0 892 68 10 20 Service 0,35 € / min + prix appel

RÉPUBLIQUE FRANÇAISE
Liberté Égalité Fraternité

METEO FRANCE
À VOS CÔTÉS, DANS UN CLIMAT QUI CHANGE

Bulletin d'estimation du risque d'avalanche
(valable en dehors des pistes balisées et ouvertes)

MASSIF : Queyras

Rédigé le lundi 23 mars 2026 à 16h

Conditions nivo-météo des 7 derniers jours

	mar. 17/03				mer. 18/03				jeu. 19/03				ven. 20/03				sam. 21/03				dim. 22/03				lun. 23/03			
	03h	09h	15h	21h	03h	09h	15h	21h	03h	09h	15h	21h	03h	09h	15h	21h	03h	09h	15h	21h	03h	09h	15h	21h	03h	09h	15h	21h
Météo																												
Vent (km/h)	25	15	20	15	20	40	70	70	55	35	30	25	20	15	5	10	15	15	15	15	20	30	40	35	25	20	20	15
à 3000m																												
Vent (km/h)	10	10	15	10	10	30	40	30	25	20	20	15	15	10	15	5	5	10	15	10	15	25	30	30	20	15	20	10
à 2000m																												

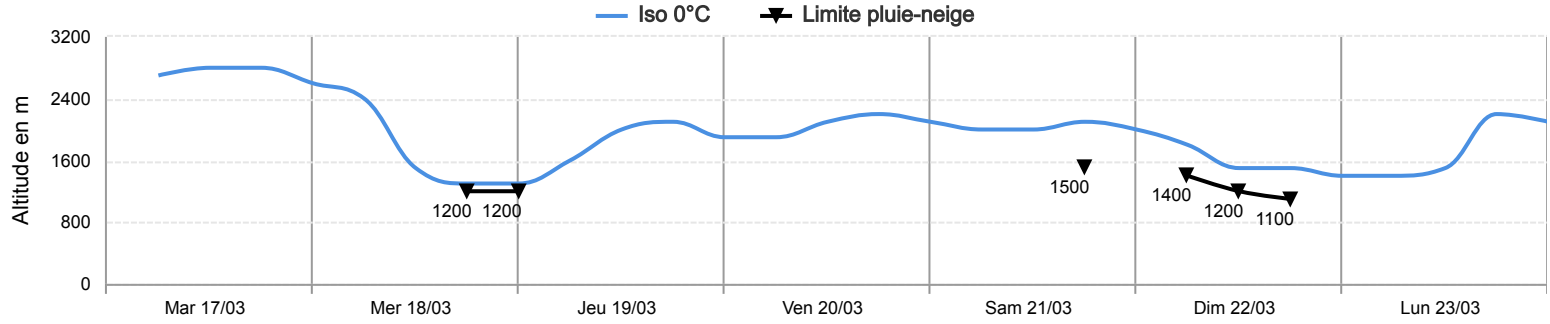

Risque d'avalanche	mar. 17/03	mer. 18/03	jeu. 19/03	ven. 20/03	sam. 21/03	dim. 22/03	lun. 23/03
	3	3	3	2	2	3	3

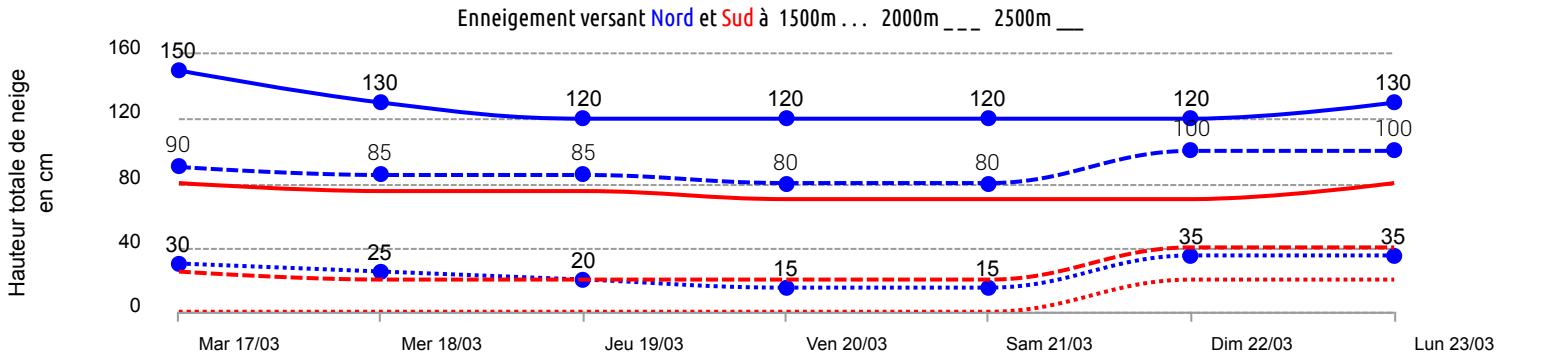

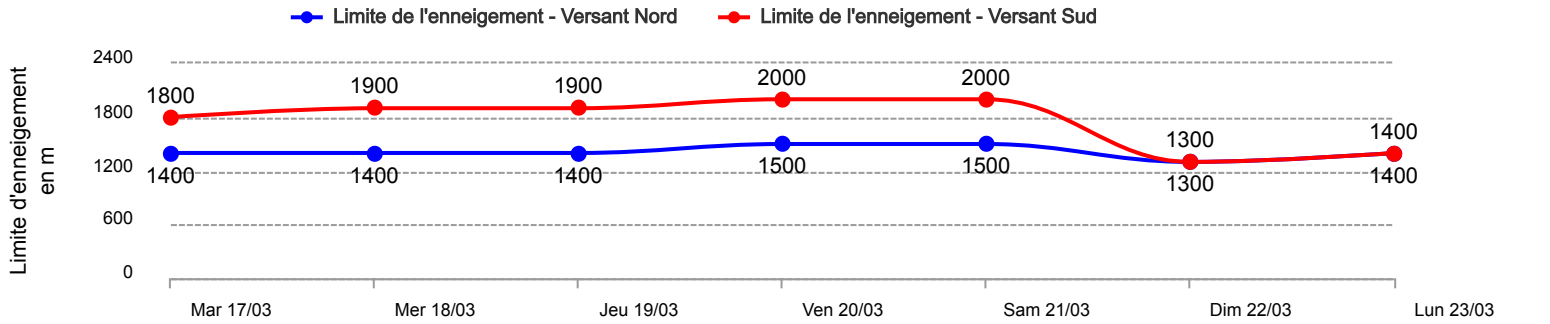

Pour consulter la vigilance en cours, veuillez vous rendre sur le site https://vigilance.meteofrance.fr/fr

Météo-France - 73 avenue de Paris, 94165 Saint-Mandé cedex - Contact : contact@meteo.fr

Rédigé par Météo-France avec la contribution des observateurs du réseau nivo-météorologiques. Partenariat : ANMSM (Maires de Stations de Montagne), DSF (Domaines Skiables de France), ADSP (Directeurs de Pistes et de la Sécurité des Stations de Sports d'Hiver) et autres acteurs de la montagne.

Bulletin neige & avalanches par téléphone au

0 892 68 10 20 Service 0,35 € / min + prix appel