Bulletin d'estimation du risque d'avalanche

(valable en dehors des pistes balisées et ouvertes)

MASSIF : Ubaye

Rédigé le lundi 23 mars 2026 à 16h

Estimation des risques pour le : MARDI 24 MARS

QUELQUES PLAQUES DANS LA NEIGE RÉCENTE - QUELQUES DÉPARTS SUPERFICIELS EN NEIGE HUMIDE

2

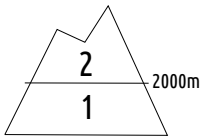

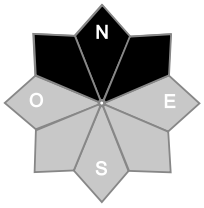

Au-dessus de 2000m indice de risque limité, plus bas indice faible.

Départs spontanés : départs superficiels de neige récente s'humidifiant au soleil, de faible ampleur.

Déclenchements provoqués : encore quelques plaques dans la neige récente ventée, notamment vers le crêtes.

Indices de risque : 5 très fort - 4 fort - 3 marqué - 2 limité - 1 faible -- En noir : les pentes les plus dangereuses

Stabilité du manteau neigeux

Situation avalancheuse typique : neige ventée — neige humide

Déclenchements provoqués : quelques plaques sont encore en place dans la neige récente, principalement dans les orientations nord-ouest, nord et nord-est au-dessus de 2000/2200 m environ, là où la neige récente ne s'est pas encore humidifiée. Elles deviennent progressivement difficiles à déclencher, mais peuvent encore céder au passage d'un skieur. Elles sont facilement identifiables, présentes notamment dans les zones d'accumulation, à proximité des crêtes et ruptures de pente. Elles génèrent des avalanches de taille petite à moyenne (taille 1 à 2). En versant nord de haute altitude, des départs un peu plus volumineux sont possibles en cas de rupture d'une couche fragile persistante plus profondément enfouie, suite à un premier départ de surface par exemple. Dans ce cas, avalanche restant généralement de taille moyenne.

Départs spontanés : peu probables au lever du jour puis rares départs de neige récente dans les pentes raides bien ensoleillées. Avalanches petites en général, plus rarement moyennes.

Qualité de la neige

Enneigement proche des normales.
Hauteurs de neige observées : 75 cm à la Nivôse de Restefond à 2550 m (secteur venté), 98 cm au-dessus de Larche à 2270 m en adret.

Enneigement skiable : vers 1500 m en ubacs, 1800/1900 m en adrets peu pentus.

État de la neige en surface : on retrouve encore la couche de neige récente (15 à 30 cm), travaillée par le vent de nord-est proche des crêtes, et déjà fortement humidifiée jusqu'à haute altitude dans les versants bien ensoleillés. Elle peut rester froide et légère dans les versants nord-ouest, nord et nord-est au-dessus de 2000/2200 m. Elle repose en général sur un fond dur/regelé, excepté en ubacs au-dessus de 2000/2200 m, où la couche de neige légère peut être plus importante dans les combes abritées du vent.

Aperçu météo pour le mardi 24 mars

nuit	matin	après-midi	soir

Temps bien ensoleillé et doux.

Pluie-Neige				
Iso 0 °C	2 000 m	2 200 m	2 500 m	2 700 m
Vent 2000 m	5 km/h	5 km/h	10 km/h	5 km/h
Vent 3000 m	25 km/h	30 km/h	25 km/h	20 km/h

Épaisseur de neige hors-piste

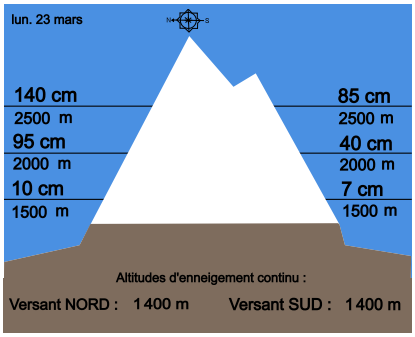

Précipitations à 1800 m

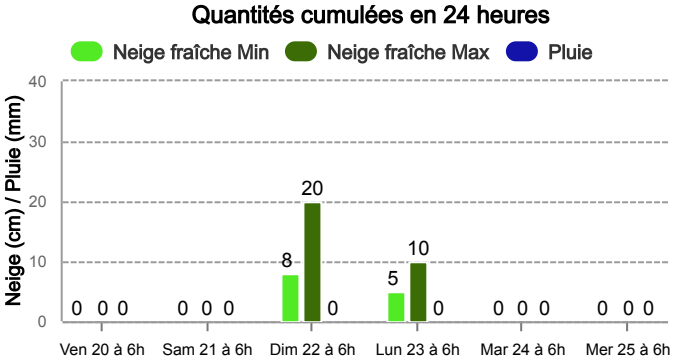

Tendance du mercredi 25 mars

2

Indice de risque limité

Maintien d'un risque limité en journée. Le renforcement du vent de nord-ouest en fin d'après-midi entraine la formation de nouvelles plaques sensibles au passage d'un skieur, aux plus hautes altitudes du massif.

Pour consulter la vigilance en cours, veuillez vous rendre sur le site https://vigilance.meteofrance.fr/fr

Météo-France - 73 avenue de Paris, 94165 Saint-Mandé cedex - Contact : contact@meteo.fr

Rédigé par Météo-France avec la contribution des observateurs du réseau nivo-météorologiques. Partenariat : ANMSM (Maires de Stations de Montagne), DSF (Domaines Skiables de France), ADSP (Directeurs de Pistes et de la Sécurité des Stations de Sports d'Hiver) et autres acteurs de la montagne.

Bulletin neige & avalanches par téléphone au 0 892 68 10 20 Service 0,35 € / min + prix appel

RÉPUBLIQUE FRANÇAISE
Liberté Égalité Fraternité

METEO FRANCE
À VOS CÔTÉS, DANS UN CLIMAT QUI CHANGE

Bulletin d'estimation du risque d'avalanche

(valable en dehors des pistes balisées et ouvertes)

MASSIF : Ubaye

Rédigé le lundi 23 mars 2026 à 16h

Conditions nivo-météo des 7 derniers jours

	mar. 17/03				mer. 18/03				jeu. 19/03				ven. 20/03				sam. 21/03				dim. 22/03				lun. 23/03			
	03h	09h	15h	21h	03h	09h	15h	21h	03h	09h	15h	21h	03h	09h	15h	21h	03h	09h	15h	21h	03h	09h	15h	21h	03h	09h	15h	21h
Météo																												
Vent (km/h)	25	30	25	20	25	50	70	80	70	50	30	30	20	15	15	10	15	15	20	15	15	25	35	40	35	25	20	20
à 3000m	↓	↓	↓	↘	↓	←	←	←	←	←	←	←	←	↓	→	↘	↘	↘	→	↘	→	↖	←	←	←	↙	↙	←
Vent (km/h)	10	10	15	10	10	30	50	50	45	30	20	15	10	10	15	5	5	10	20	10	10	15	25	30	25	15	15	10
à 2000m	←	↗	→	←	↘	←	←	←	←	←	←	←	←	↙	→	↖	↗	→	→	→	↗	←	←	←	←	←	←	↙

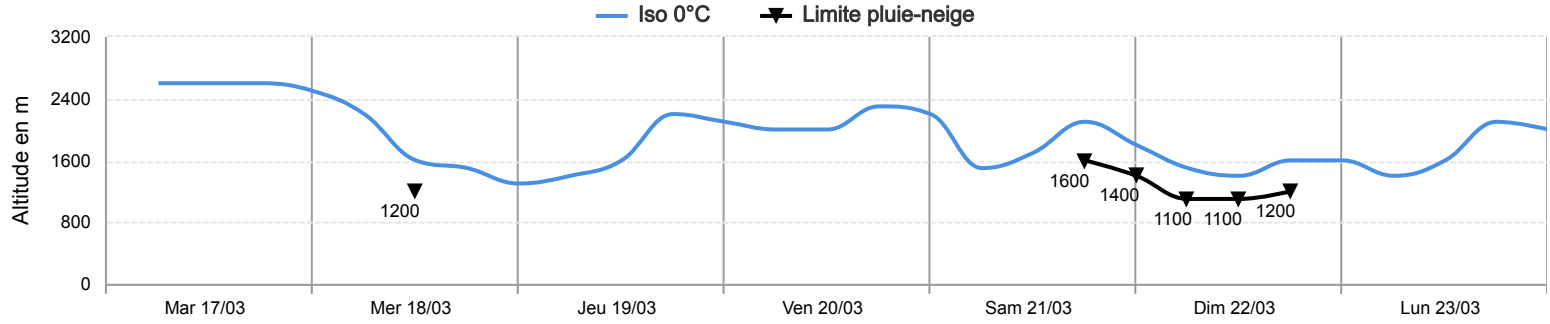

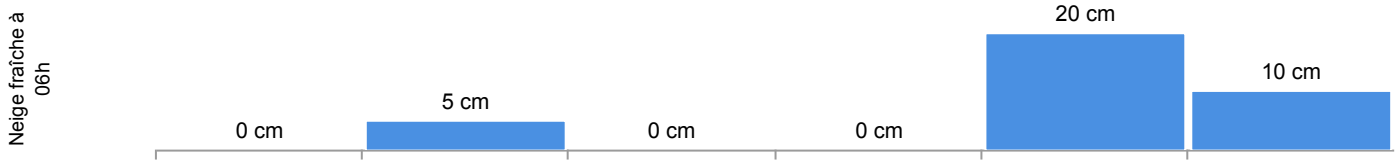

Risque d'avalanche	mar. 17/03	mer. 18/03	jeu. 19/03	ven. 20/03	sam. 21/03	dim. 22/03	lun. 23/03
	2	3	3	2	2	3	3

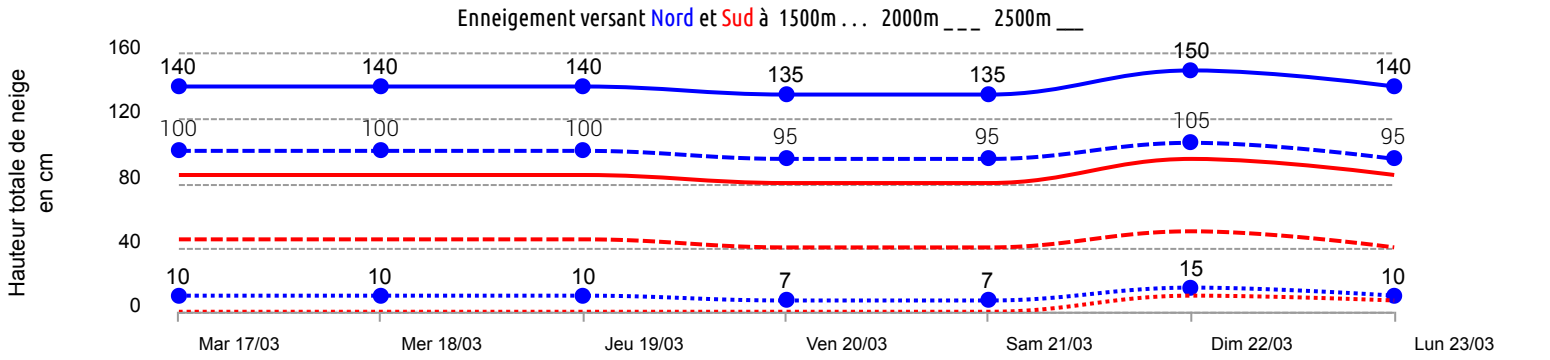

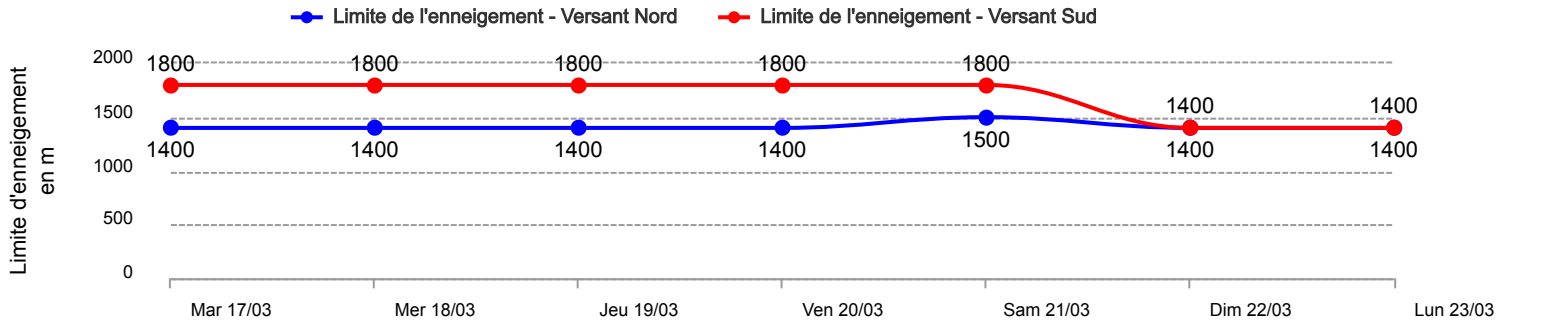

Pour consulter la vigilance en cours, veuillez vous rendre sur le site https://vigilance.meteofrance.fr/fr

Météo-France - 73 avenue de Paris, 94165 Saint-Mandé cedex - Contact : contact@meteo.fr

Rédigé par Météo-France avec la contribution des observateurs du réseau nivo-météorologiques. Partenariat : ANMSM (Maires de Stations de Montagne), DSF (Domaines Skiables de France), ADSP (Directeurs de Pistes et de la Sécurité des Stations de Sports d'Hiver) et autres acteurs de la montagne.

Bulletin neige & avalanches par téléphone au
0 892 68 10 20 Service 0,35 € / min + prix appel