GOBIERNO DE ESPAÑA
VICEPRESIDENCIA TERCERA DEL GOBIERNO
MINISTERIO PARA LA TRANSICIÓN ECOLÓGICA Y EL RETO DEMOGRÁFICO

Boletín de información nivológica y de peligro de aludes

Pirineo Catalán

aemet Agencia Estatal de Meteorología

martes, 24 de marzo de 2026

Pronóstico hasta las 24 horas del miércoles, día 25 de marzo

(Válido fuera de pistas de esquí balizadas y abiertas)

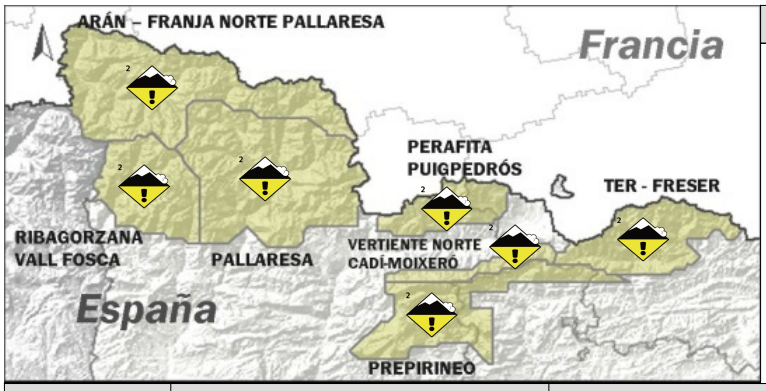

Problemas de aludes

Nieve húmeda

Capas débiles persistentes

Macizo	Peligro	Problemas de aludes, cota, orientación, tamaño	Innivación observada (m)
Arán - Franja norte Pallaresa	2 / 2 / **Limitado**	**Nieve húmeda** 2 — **Capas débiles persistentes** 2400 — 2	2026-03-24 — Cota más baja caras N
Ribagorzana - Vall Fosca	2 / 2 / **Limitado**	**Nieve húmeda** 2 — **Capas débiles persistentes** 2400 — 2	2026-03-24 — Cota más baja caras N
Pallaresa	2 / 2 / **Limitado**	**Nieve húmeda** 2 — **Capas débiles persistentes** 2400 — 2	2026-03-24 — Cota más baja caras N

AEMET. Se autoriza la reproducción de su contenido citando la fuente.

Boletín de información nivológica y de peligro de aludes

Pirineo Catalán

Perafita - Puigpedrós	2 **Limitado**	**Nieve húmeda**	**Capas débiles persistentes** 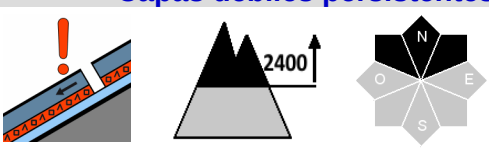	2026-03-24 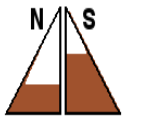 Cota más baja caras N
Ter - Freser	2 **Limitado**	**Nieve húmeda**	**Capas débiles persistentes** 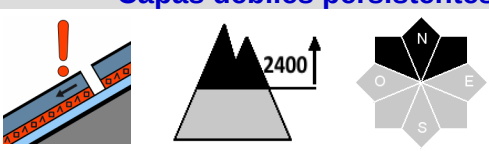	2026-03-24 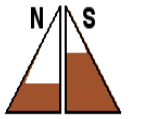 Cota más baja caras N
Vertiente norte Cadí - Moixeró	2 **Limitado**	**Nieve húmeda**		2026-03-24 Cota más baja caras N
Prepirineo	2 **Limitado**	**Nieve húmeda**		2026-03-24 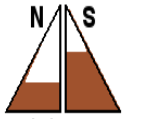 Cota más baja caras N

Estado del manto y observaciones recientes

Durante las últimas 24 horas la nieve depositada en jornadas previas se ha ido compactando, con una disminución de espesores de hasta 10 cm en el área oriental. Con todo, el manto sigue presentando continuidad desde medianías, a mayor altitud en orientaciones sur, con espesores que continúan siendo importantes y situándose muy por encima de lo que puede considerarse normal a estas alturas de la temporada, superando los 200 cm por encima de 2.200 metros en bastantes zonas.

La nieve se encuentra muy humedecida en zonas medias y bajas, con una ligera capa superficial de nieve reciente en algunas áreas en proceso de rápida transformación. En las altas umbrías predomina la nieve más seca, venteada y encostrada, pudiendo existir estratos débiles en el interior del manto localizados a no demasiada profundidad.

Evolución del manto y peligro de aludes para el miércoles, día 25

Situación de nieve húmeda, y de capas débiles persistentes en cotas altas.

AEMET. Se autoriza la reproducción de su contenido citando la fuente.

Continuará el régimen de fusión diurna y rehielo nocturno, con formación de costras sobre la superficie del manto que tenderán a mantenerlo estable a primeras horas, aunque, por otra parte, esa capa externa congelada incrementará el peligro de resbalones durante el tránsito. Con el aumento de la insolación a lo largo de la mañana esta costra irá fundiéndose y reblandeciéndose la nieve, lo que aumentará la probabilidad de purgas de nieve húmeda en pendientes con suficiente inclinación, siendo más probables en áreas de solana. En general serán de tamaño pequeño o mediano, sin poder descartase algún deslizamiento basal en laderas herbosas o de roca lisa. De cara al final del día, la entrada de un frente frío en frontolisis provocará un marcado descenso de las temperaturas, por lo que los problemas asociados a la nieve húmeda tenderán a remitir.

En umbrías de la alta montaña persisten estratos débiles en el interior del manto sobre los cuales puede descansar alguna placa de viento antigua, sobre todo en cercanías de crestas y collados. Estas estructuras podrán romperse fracturarse ante una sobrecarga débil, como es el paso de un esquiador, dando lugar a algún alud de dimensiones medianas, suficiente como para enterrar a una persona.

Predicción meteorológica para el miércoles, día 25

Poco nuboso o despejado a primeras horas, aumentando la nubosidad durante la tarde hasta quedar los cielos muy nubosos o cubiertos en el valle de Arán y resto de la divisoria fronteriza, y nubosos o muy nubosos en las demás zonas. Se esperan precipitaciones débiles en Arán y Franja Norte Pallaresa al final del día, con cota de nieve bajando de 1.600 a unos 800 ó 1.000 metros. Temperaturas en ligero o moderado ascenso, excepto en el valle de Arán, donde las máximas descenderán ligeramente. Heladas débiles, localmente moderadas. Vientos flojos o moderados de componentes oeste y norte, aumentando a fuertes por la tarde, con rachas muy fuertes en cotas altas y zonas expuestas.

Datos en la atmósfera libre:

Altitud de la isoterma de 0 ºC: 3.000 m
Altitud de la isoterma de -10 ºC: 4.900 m

Viento a 1500 m: NW 30 km/h
Viento a 3000 m: NW 40 km/h

Evolución para el jueves día 26

Nivel de peligro por nieve húmeda en descenso, como consecuencia del acusado descenso térmico en la jornada del jueves.

Escala europea de peligro de aludes

Débil | Limitado | Notable | Fuerte | Muy Fuerte

Problemas de aludes

Nieve reciente | Placas de viento | Capas débiles persistentes | Nieve húmeda | Deslizamientos basales | Sin problema evidente

Nota1: Se recuerda que, siempre que haya nieve, la ausencia total de peligro no existe. Hay que tener presente que en circunstancias desfavorables, con aludes de tamaño 1 (alud pequeño o colada) y tamaño 2 (alud mediano), se pueden sufrir severos daños personales.

Nota2: Los BPA se elaboran en base a información meteorológica así como al estado del manto nivoso a través de sondeos puntuales. Se advierte a los usuarios de la variabilidad de esta información al extrapolarla a zonas extensas de montaña. Por ello, AEMET no se hace responsable de su uso para la toma de decisiones que conciernen a la seguridad personal, ni de los riesgos físicos o materiales de ellas derivadas.

AEMET. Se autoriza la reproducción de su contenido citando la fuente.