GOBIERNO DE ESPAÑA
VICEPRESIDENCIA TERCERA DEL GOBIERNO
MINISTERIO PARA LA TRANSICIÓN ECOLÓGICA Y EL RETO DEMOGRÁFICO

Boletín de información nivológica y de peligro de aludes

Pirineo Navarro y Aragonés

aemet Agencia Estatal de Meteorología

martes, 24 de marzo de 2026

Pronóstico hasta las 24 horas del miércoles, día 25 de marzo

(Válido fuera de pistas de esquí balizadas y abiertas)

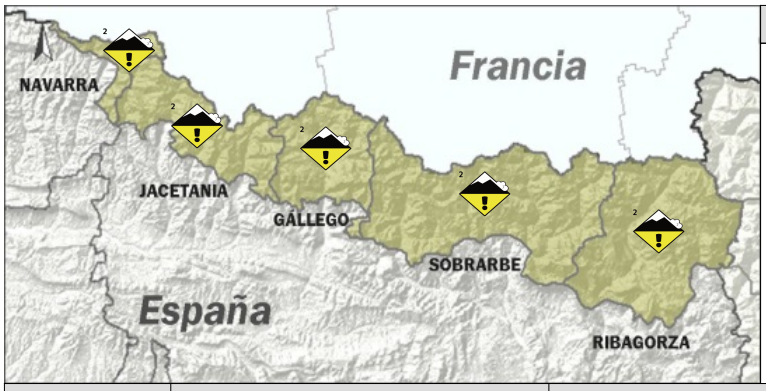

Problemas de aludes

Nieve húmeda

Capas débiles persistentes

Macizo	Peligro	Problemas de aludes, cota, orientación, tamaño	Innivación observada (m)
Navarra	2 **Limitado**	**Nieve húmeda** 2	2026-03-24 Cota más baja caras N
Jacetania	2 **Limitado**	**Nieve húmeda** 2 **Capas débiles persistentes** 2400 2	2026-03-24 Cota más baja caras N
Gállego	2 **Limitado**	**Nieve húmeda** 2 **Capas débiles persistentes** 2400 2	2026-03-24 Cota más baja caras N
Sobrarbe	2 **Limitado**	**Nieve húmeda** 2 **Capas débiles persistentes** 2400 2	2026-03-24 Cota más baja caras N

AEMET. Se autoriza la reproducción de su contenido citando la fuente.

Boletín de información nivológica y de peligro de aludes

Pirineo Navarro y Aragonés

Ribagorza	**Limitado**	**Nieve húmeda** 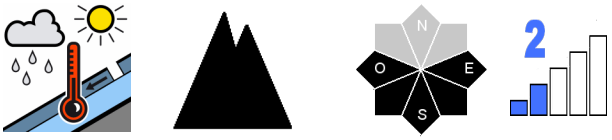 **Capas débiles persistentes** 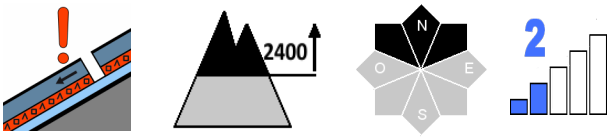	2026-03-24 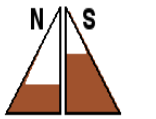 Cota más baja caras N

Estado del manto y observaciones recientes

Continúa el apelmazamiento de la nieve y la mengua progresiva del grosor del manto, con una disminución de entre 1 y 5 cm durante las últimas 24 horas en los diferentes puntos de observación. Pese a ello sigue presentando continuidad desde medianías, a mayor altitud en orientaciones sur, con una disimetría entre solanas y umbrías en aumento. Los espesores rondan los 40 a 140 cm en torno a 1.800 metros y van incrementándose conforme ascendemos, de tal manera que pueden superarse en algunas áreas los 180 a 200 cm en cota 2.100.

La nieve se encuentra muy humedecida en zonas medias y bajas así como en solanas de cotas altas, aunque aquí de manera más superficial, y se ve sometida al ciclo de fusión diurna y rehielo nocturno. En las altas umbrías predomina la nieve más seca, venteada y encostrada, pudiendo existir estratos débiles en el interior del manto localizados a no demasiada profundidad.

Se han registrado varios aludes de nieve húmeda en orientaciones sur, de tamaño mediano por lo general, y algún deslizamiento basal.

Evolución del manto y peligro de aludes para el miércoles, día 25

Situación de nieve húmeda, y de capas débiles persistentes en cotas altas.

Continuará el régimen de fusión diurna y rehielo nocturno, con formación de costras sobre la superficie del manto que lo mantendrán suficientemente estable a primeras horas, aunque esa capa más externa congelada podrá incrementar el peligro de resbalones durante el tránsito. Con el aumento de la insolación a lo largo de la mañana esta costra irá fundiéndose y reblandeciéndose la nieve, lo que aumentará la probabilidad de purgas de nieve húmeda en pendientes con suficiente inclinación, siendo más probables en áreas de solana. En general serán de tamaño pequeño o mediano, sin poder descartase algún deslizamiento basal en laderas herbosas o de roca lisa. De cara al final del día, la entrada de un frente frío en frontolisis provocará un marcado descenso de las temperaturas, por lo que los problemas asociados a la nieve húmeda tenderán a remitir.

En umbrías de la alta montaña persisten estratos débiles en el interior del manto sobre los cuales puede descansar alguna placa de viento antigua, sobre todo en cercanías de crestas y collados. Estas estructuras podrían romperse fracturarse ante una sobrecarga débil, como es el paso de un esquiador, dando lugar a algún alud de dimensiones medianas, suficiente como para enterrar a una persona.

AEMET. Se autoriza la reproducción de su contenido citando la fuente.

Predicción meteorológica para el miércoles, día 25

Poco nuboso o despejado a primeras horas, aumentando la nubosidad durante la tarde hasta quedar los cielos muy nubosos o cubiertos en el Pirineo navarro y la divisoria fronteriza del aragonés, donde habrá precipitaciones débiles o localmente moderadas, y nubosos o muy nubosos en el resto de las zonas, donde no se descarta que se produzca alguna precipitación de carácter débil. Cota de nieve: bajando de 1.600 a unos 800 ó 1.000 metros. Temperaturas mínimas en ligero ascenso, y máximas sin cambios o en ligero descenso. Heladas débiles, localmente moderadas. Vientos flojos o moderados del norte y noroeste, aumentando a fuertes por la tarde, con rachas muy fuertes en cotas altas y zonas expuestas.

Datos en la atmósfera libre:

Altitud de la isoterma de 0 ºC: 2.900 m
Altitud de la isoterma de -10 ºC: 5.000 m

Viento a 1500 m: NW 40 km/h
Viento a 3000 m: NW 50 km/h

Evolución para el jueves día 26

Nivel de peligro por nieve húmeda en descenso, como consecuencia del acusado descenso térmico en la jornada del jueves.

(Información elaborada a partir de los datos recibidos de los refugios de Linza, Lizara, Panticosa, Bachimaña, Góriz, Pineta, Estós, Angel Orús, La Renclusa, Cap de Llauset y Belagua, de las estaciones de esquí de Formigal y Panticosa (lagos), de la estación de esquí de fondo de Llanos del Hospital y de Ordesa Pradera)

Escala europea de peligro de aludes

1 Débil | 2 Limitado | 3 Notable | 4 Fuerte | 5 Muy Fuerte

Problemas de aludes

Nieve reciente | Placas de viento | Capas débiles persistentes | Nieve húmeda | Deslizamientos basales | Sin problema evidente

Nota1: Se recuerda que, siempre que haya nieve, la ausencia total de peligro no existe. Hay que tener presente que en circunstancias desfavorables, con aludes de tamaño 1 (alud pequeño o colada) y tamaño 2 (alud mediano), se pueden sufrir severos daños personales.

Nota2: Los BPA se elaboran en base a información meteorológica así como al estado del manto nivoso a través de sondeos puntuales. Se advierte a los usuarios de la variabilidad de esta información al extrapolarla a zonas extensas de montaña. Por ello, AEMET no se hace responsable de su uso para la toma de decisiones que conciernen a la seguridad personal, ni de los riesgos físicos o materiales de ellas derivadas.

AEMET. Se autoriza la reproducción de su contenido citando la fuente.