Mittwoch 25.03.2026

Veröffentlicht am 24.03.2026 um 17:00

Vormittag

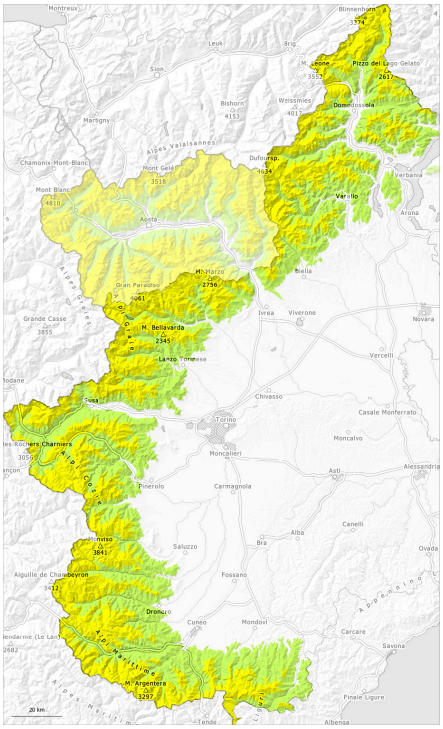

Nachmittag

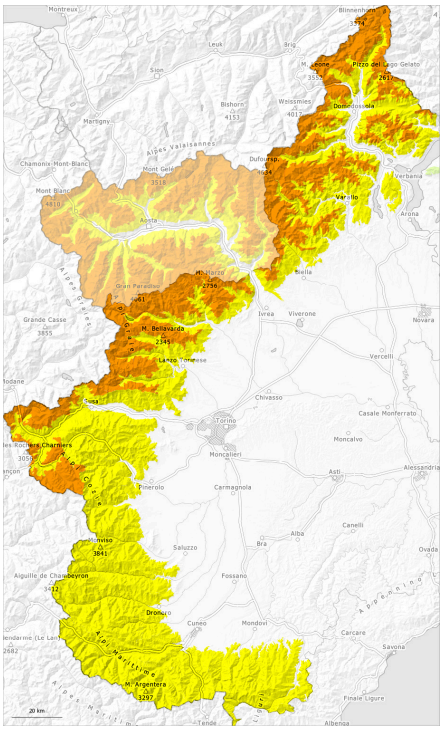

1	2	3	4	5
gering	mäßig	erheblich	groß	sehr groß

Mittwoch 25.03.2026

Veröffentlicht am 24.03.2026 um 17:00

Gefahrenstufe 3 - Erheblich

AM:

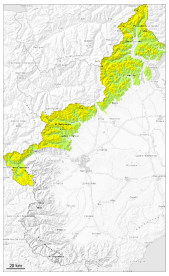

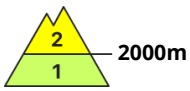

Tendenz: Lawinengefahr steigt
am Donnerstag, den 26.03.2026

Triebschnee

2000m

PM:

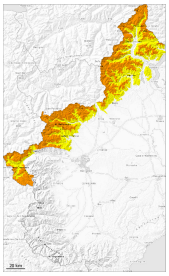

Tendenz: Lawinengefahr steigt
am Donnerstag, den 26.03.2026

Triebschnee

2000m

Nassschnee

2300m

Triebschnee und Nassschnee sind die Hauptgefahr. Nachmittag: Die spontane Lawinenaktivität nimmt mit dem zunehmend starken Westwind schnell zu.

Mit der tageszeitlichen Erwärmung und der Sonneneinstrahlung sind im Tagesverlauf feuchte und nasse Lawinen möglich, vor allem solche mittlerer Größe, Vorsicht an steilen Grashängen in tiefen und mittleren Lagen sowie an Felswandfüßen.

Nachmittag: Es fällt vor allem entlang der Grenze zu Frankreich und entlang der Grenze zur Schweiz etwas Schnee. Mit der markanten Abkühlung, Schneefall und mäßigem bis starkem Westwind entstehen frische Triebschneeansammlungen.
In Rinnen, Mulden und hinter Geländekanten sind Schneebrettlawinen möglich, auch recht große. Lawinen können schon von einzelnen Wintersportlern ausgelöst werden oder spontan abgehen. Dies vor allem an steilen Schattenhängen in mittleren und hohen Lagen.
Touren erfordern Vorsicht und Zurückhaltung.

Schneedecke

Gefahrenmuster gm.6: lockerer schnee und wind | gm.10: frühjahrssituation

Am Morgen ist es mild. Sonne und Wärme führen am Vormittag vor allem in tiefen und mittleren Lagen zu einer allmählichen Anfeuchtung der Schneedecke.
Nachmittag: Mit der markanten Abkühlung und mäßigem bis starkem Westwind entstehen in den nächsten Tagen frische Triebschneeansammlungen.

Vor allem mittlere Lagen und steile Sonnenhänge: Die Schneedecke ist weitgehend stabil, mit einer oft tragfähigen Kruste an der Oberfläche.
Hohe Lagen und Hochgebirge: Der Triebschnee liegt auf einer glatten Altschneeoberfläche.

Tendenz

Es ist kalt. Lokaler Anstieg der Lawinengefahr mit dem starken bis stürmischen Nordwestwind. Bis am Freitag entstehen in Rinnen, Mulden und hinter Geländekanten sowie in hohen Lagen und im Hochgebirge weitere Triebschneeansammlungen. Entlang der Grenze zu Frankreich und entlang der Grenze zur Schweiz sind die Gefahrenstellen häufiger und die Gefahr höher.

Gefahrenstufe 2 - Mäßig

AM:

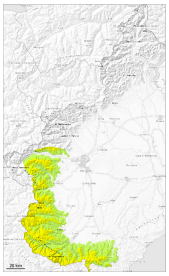

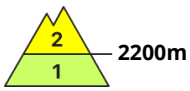

Tendenz: Lawinengefahr bleibt gleich
am Donnerstag, den 26.03.2026

Triebschnee

2200m

PM:

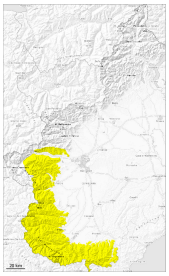

Tendenz: Lawinengefahr bleibt gleich
am Donnerstag, den 26.03.2026

Triebschnee

2200m

Nassschnee

2500m

Feuchte und nasse Lawinen sind tagsüber möglich. Schneebrettlawinen beachten, vor allem am Nachmittag in den Gebieten mit viel Wind.

Mit der tageszeitlichen Erwärmung und der Sonneneinstrahlung sind im Tagesverlauf feuchte und nasse Lawinen möglich, vor allem solche mittlerer Größe.
Mit mäßigem bis starkem Westwind entstehen am Nachmittag vor allem in Kamm- und Passlagen sowie in der Höhe gut sichtbare Triebschneeansammlungen. Lawinen können v.a. an steilen Schattenhängen in den verschiedenen Triebschneeschichten anreißen und vereinzelt groß werden. Dies vor allem an Übergängen von wenig zu viel Schnee wie z.B. bei der Einfahrt in Rinnen und Mulden in hohen Lagen und im Hochgebirge.
Triebschneeansammlungen können vereinzelt schon von einzelnen Wintersportlern ausgelöst werden.

Touren erfordern eine vorsichtige Routenwahl.

Schneedecke

Gefahrenmuster gm.6: lockerer schnee und wind | gm.10: frühjahrssituation

Am Morgen ist es sehr mild. Sonne und Wärme führen am Vormittag vor allem in tiefen und mittleren Lagen zu einer deutlichen Anfeuchtung der Schneedecke.
Nachmittag: Mit der markanten Abkühlung und mäßigem bis starkem Westwind entstehen in den nächsten Tagen frische Triebschneeansammlungen.
Vor allem mittlere Lagen und steile Sonnenhänge: Der Neuschnee überlagert eine recht günstige Altschneedecke. Die Schneedecke ist weitgehend stabil, mit einer oft tragfähigen Kruste an der Oberfläche.

Hohe Lagen und Hochgebirge: Der Triebschnee liegt auf einer glatten Altschneeoberfläche. Vor allem in Gipfellagen liegen je nach Windeinfluss sehr unterschiedliche Schneehöhen.

Tendenz

Es ist kalt. Lokaler Anstieg der Lawinengefahr mit dem starken Nordwestwind. Entlang der Grenze zu Frankreich und in der Höhe sind die Gefahrenstellen häufiger und die Gefahr höher.