Mittwoch 25.03.2026

Veröffentlicht am 24.03.2026 um 17:00

Vormittag

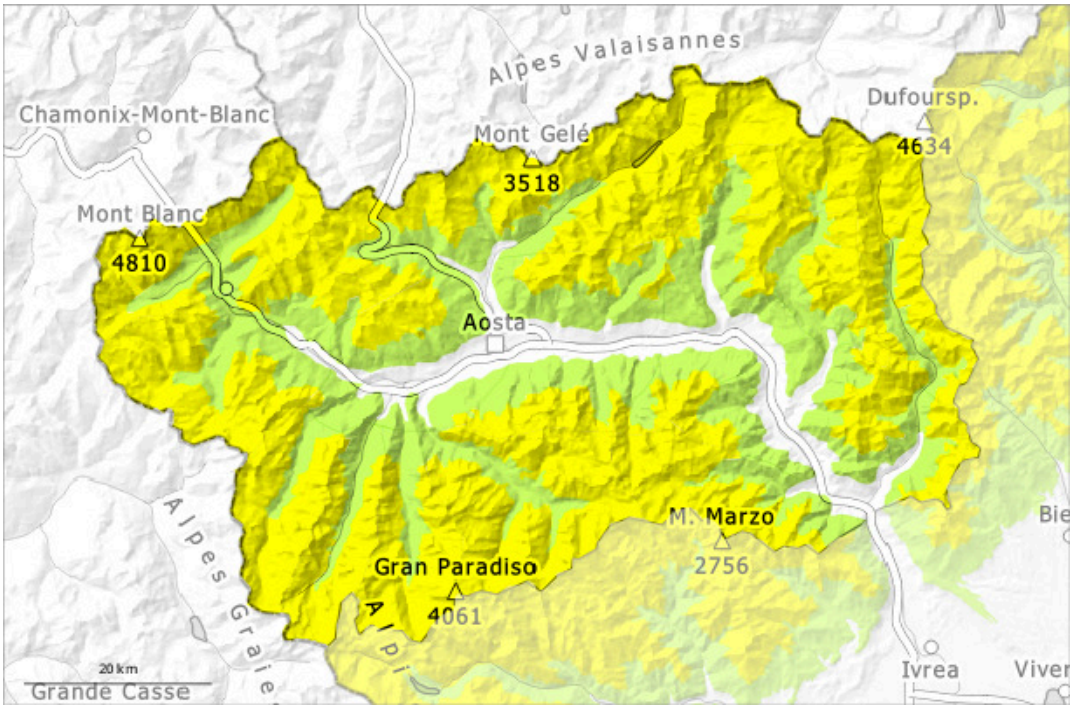

Nachmittag

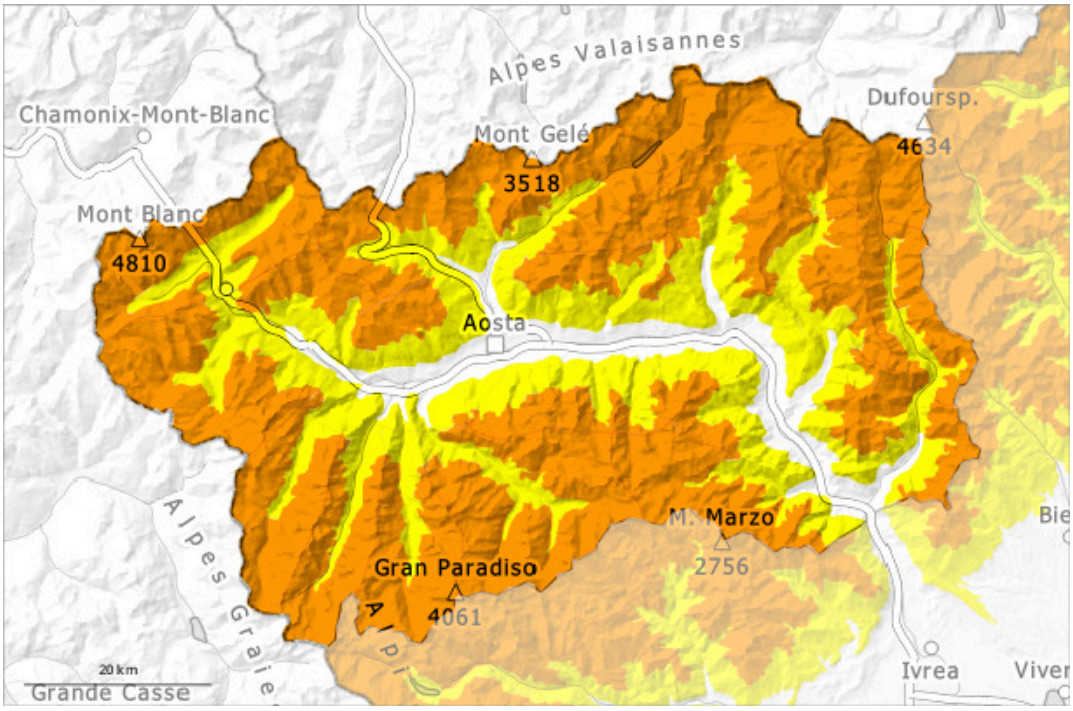

1	2	3	4	5
gering	mäßig	erheblich	groß	sehr groß

Mittwoch 25.03.2026

Veröffentlicht am 24.03.2026 um 17:00

Gefahrenstufe 3 - Erheblich

AM:

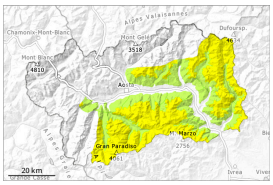

2000m

Tendenz: Lawinengefahr steigt
am Donnerstag, den 26.03.2026

Neuschnee

2000m

PM:

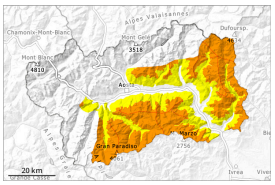

2100m

Tendenz: Lawinengefahr steigt
am Donnerstag, den 26.03.2026

Triebschnee

2100m

Neuschnee

2000m

Allmählicher Anstieg der Gefahr von trockenen Lawinen mit dem starken Wind.

Vormittag: Besonders Kammlagen, Rinnen und Mulden: Der Neuschnee vom Sonntag sowie die teils mächtigen Triebschneeansammlungen können von einzelnen Wintersportlern ausgelöst werden. Dies vor allem an sehr steilen Hängen. Sie sind oft mittelgroß.
Vor allem im felsdurchsetzten Steilgelände und an Sonnenhängen sind mit der Sonneneinstrahlung einzelne meist kleine nasse Lawinen möglich. Nachmittag: Mit der markanten Abkühlung und starkem bis stürmischem Nordwestwind entsteht in den nächsten zwei Tagen eine heimtückische Lawinensituation. Diese Bedingungen bewirken ab dem Mittag eine allmähliche Zunahme der Gefahr von trockenen Lawinen. In Kamm- und Passlagen und kammfern sind mittlere und vereinzelt große trockene Schneebrettlawinen möglich.
Touren erfordern Vorsicht und Zurückhaltung.

Schneedecke

Gefahrenmuster gm.6: lockerer schnee und wind

Am Mittwoch fallen in allen Höhenlagen 2 bis 5 cm Schnee, lokal auch mehr. Der obere Teil der Schneedecke ist weich, mit einer lockeren Oberfläche. Der Wind verfrachtet Neu- und Altschnee.
Am Sonntag fielen 10 bis 30 cm Schnee, lokal bis zu 50 cm. Insbesondere in die an das Piemont grenzen. Wo sich die Lage allmählich beruhigt. Der Wind blies in Kammlagen schwach bis mäßig.
Der Neuschnee liegt stellenweise auf einer weichen Altschneeoberfläche. Oder auf Krusten.
In der Schneedecke sind v.a. an steilen Schattenhängen Schwachschichten vorhanden.

Besonders Kammlagen aller Expositionen: Verbreitet liegen je nach Windeinfluss sehr unterschiedliche Schneehöhen.

Tendenz

Es ist kalt. Verbreitet stürmischer Nordwind: Die Lawinengefahr steigt innerhalb der Gefahrenstufe an. Oberhalb der Waldgrenze sind die Gefahrenstellen häufiger.

Gefahrenstufe 3 - Erheblich

AM:

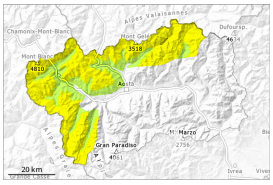

2500m

Tendenz: Lawinengefahr steigt
am Donnerstag, den 26.03.2026

Triebschnee

2500m

Neuschnee

2200m

PM:

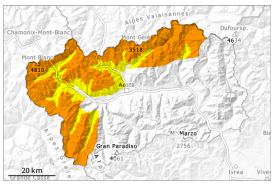

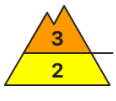

2100m

Tendenz: Lawinengefahr steigt
am Donnerstag, den 26.03.2026

Triebschnee

2100m

Neuschnee

1900m

Markanter Anstieg der Gefahr von trockenen Lawinen mit Neuschnee und Sturm.

Vormittag: Besonders Kammlagen, Rinnen und Mulden: Der Neuschnee vom Sonntag sowie die teils mächtigen Triebschneeansammlungen können von einzelnen Wintersportlern ausgelöst werden. Dies vor allem an sehr steilen Hängen. Sie sind vereinzelt mittelgroß.
Vor allem im felsdurchsetzten Steilgelände und an Sonnenhängen sind mit der Sonneneinstrahlung einzelne meist kleine nasse Lawinen möglich.
Nachmittag: Mit der markanten Abkühlung und starkem bis stürmischem Nordwestwind entsteht eine heimtückische Lawinensituation. Die Gefahrenstellen nehmen zu. Diese Bedingungen bewirken ab dem Mittag eine Zunahme der Gefahr von trockenen Lawinen. In Kamm- und Passlagen und kammfern sind mittlere und vereinzelt große trockene Schneebrettlawinen möglich.
Touren erfordern Vorsicht und Zurückhaltung.

Schneedecke

Gefahrenmuster gm.6: lockerer schnee und wind

Am Mittwoch fallen in allen Höhenlagen 10 bis 30 cm Schnee, lokal auch mehr. Der obere Teil der Schneedecke ist weich, mit einer lockeren Oberfläche. Der Wind verfrachtet den Neuschnee intensiv.

Am Sonntag fielen 10 bis 30 cm Schnee. Insbesondere in die an das Piemont grenzen. Wo sich die Lage allmählich beruhigt. Der Wind blies in Kammlagen schwach bis mäßig.
Der Neuschnee liegt stellenweise auf einer weichen Altschneeoberfläche. Oder auf Krusten.
In der Schneedecke sind v.a. an steilen Schattenhängen Schwachschichten vorhanden.
Besonders Kammlagen aller Expositionen: Verbreitet liegen je nach Windeinfluss sehr unterschiedliche Schneehöhen.

Tendenz

Es ist kalt. Verbreitet stürmischer Nordwind: Die Lawinengefahr steigt innerhalb der Gefahrenstufe an. Entlang der Grenze zu Frankreich sind die Gefahrenstellen häufiger und die Gefahr höher.