ICGC Institut Cartogràfic i Geològic de Catalunya

Servei Meteorològic de Catalunya meteo.cat

Boletín de peligro de aludes para el Pirineo de Catalunya
Del 24/03/2026 al 25/03/2026

(Válido fuera pistas de esquí y zonas no controladas)

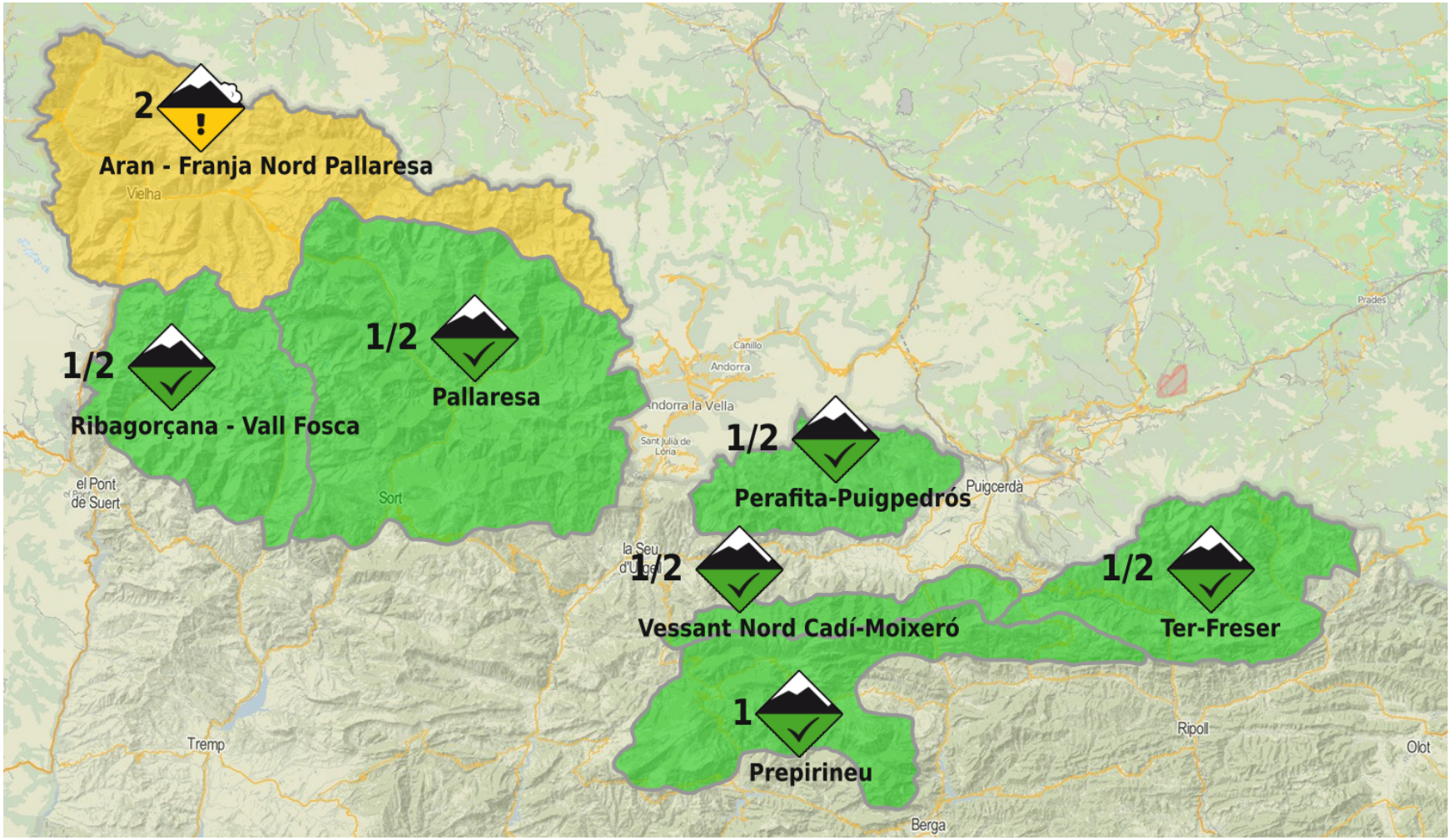

5 MUY FUERTE	4 FUERTE	3 NOTABLE	2 LIMITADO	1 DÉBIL

ICGC Institut Cartogràfic i Geològic de Catalunya

Servei Meteorològic de Catalunya

Boletín de peligro de aludes Aran - Franja Nord Pallaresa Del 24/03/2026 al 25/03/2026

(Válido fuera pistas de esquí y zonas no controladas)

LIMITADO (2).

Situación primaria

Capas débiles persistentes

Distribución

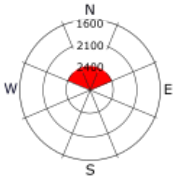

Tamaño

Origen

Tendencia

Situación secundaria

Nieve venteada

Distribución

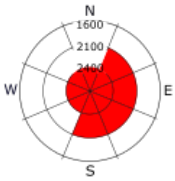

Tamaño

Origen

Tendencia

Estado del manto nivoso

Las placas que descansan sobre facetas o escarcha siguen reactivas. Los lugares más delicados son las orientaciones N, NW y NE, en las laderas con cambios abruptos del terreno, poco frecuentados y en canales, por encima de los 2.400 m. En estos lugares podremos desencadenar aludes de tamaño 2 (medio), con capacidad de enterrar a una persona. La última nevada, débil, con viento de N, ha formado algunas placas de viento nuevas, pequeñas, bajo collados y cordales en S y E. El viento del N-NW y los nuevos chubascos de nieve previstos para el miércoles por la tarde engrosarán estas placas. Son probables también aludes de nieve húmeda, sobre todo accidentales, a nuestro paso esquiando, a partir de mediodía (cuando se ablanden las costras). Llegarán hasta tamaño 1 (pequeño), sin capacidad de cubrir a una persona. Podrán caer en las solanas de fuerte inclinación. No se descarta algún deslizamiento basal, en solanas, muy residual.

Distribución del manto nivoso

Hay nieve por encima de unos 1-500 m en umbrías y 1.800 m en solanas. Los espesores a unos 2.200 m son ligeramente superiores a los normales en la Franja Norte de la Pallaresa y en la mitad sur de Arán donde rondan los 180-220 cm. En la mitad norte de Arán son los normales por estas fechas con unos 120-140 cm de espesor total.

Tendencia para las próximas 48-72h

Caerán nuevas nevadas con fuerte viento del NW. Seguirán los problemas por placas de viento. Peligro: EN PROGRESIVO ASCENSO.

El próximo boletín será emitido el día 2026-03-25

5 MUY FUERTE	4 FUERTE	3 NOTABLE	2 LIMITADO	1 DÉBIL

EAWS EUROPEAN AVALANCHE WARNING SERVICES

ICGC Institut Cartogràfic i Geològic de Catalunya

Servei Meteorològic de Catalunya

Boletín de peligro de aludes Ribagorçana - Vall Fosca Del 24/03/2026 al 25/03/2026

(Válido fuera pistas de esquí y zonas no controladas)

DÉBIL (1), LIMITADO (2), por encima de 2.500 m, y a partir de mediodía.

Situación primaria

Nieve húmeda

Distribución

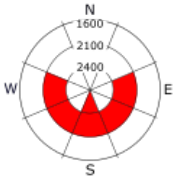

Tamaño

Origen

Tendencia

Situación secundaria

Capas débiles persistentes

Distribución

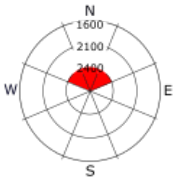

Tamaño

Origen

Tendencia

Estado del manto nivoso

El manto sigue endurecido, con una costra en todas las orientaciones desde los 2.000 m hasta las cotas más altas. Para el miércoles, a primera hora, el manto estará rehelado y con el paso de las horas, debido a la radiación solar, se humedecerá. En solanas, en terreno con fuerte inclinación, pueden caer aludes naturales de fusión de forma natural o a nuestro paso esquiando que llegarán a tamaño 1 (pequeño), sin capacidad para enterrar a una persona. En umbrías elevadas, en el límite norte con el Aran, podemos encontrar, muy localmente, alguna placa antigua sobre niveles débiles que con un sobrecarga fuerte, podría caer y generar aludes de tamaño 2 (medio), con capacidad de enterrarnos. Los lugares delicados están bajo collados y cordales, por encima de 2.500 m. A última hora se intensificará el viento en altura. Habrá que vigilar con los resbalones a primera hora por la presencia de costras duras. Recuerde llevar siempre el DVA, pala y sonda, además del casco, crampones y el piolet.

Distribución del manto nivoso

Hay nieve en el suelo a 1.600 m en terreno umbrío. El manto es esquiable en esta cota, en umbrías, y por encima de los 2.200 m en solanas. Los grosores alcanzan los 100-130 cm a unos 2.200 m. Estos valores se acercan a los normales para la época.

Tendencia para las próximas 48-72h

Caerán algunos chubascos con fuerte viento del NW, con problemas por placas de viento. Peligro: EN PROGRESIVO ASCENSO.

El próximo boletín será emitido el día 2026-03-25

5 MUY FUERTE	4 FUERTE	3 NOTABLE	2 LIMITADO	1 DÉBIL

EAWS EUROPEAN AVALANCHE WARNING SERVICES

ICGC Institut Cartogràfic i Geològic de Catalunya

Servei Meteorològic de Catalunya

Boletín de peligro de aludes Pallaresa
Del 24/03/2026 al 25/03/2026

(Válido fuera pistas de esquí y zonas no controladas)

DÉBIL (1), LIMITADO (2), por encima de 2.500 m, y a partir de mediodía.

Situación primaria

Nieve húmeda

Distribución

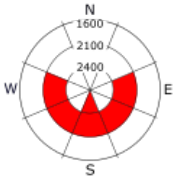

Tamaño

Origen

Tendencia

Situación secundaria

Capas débiles persistentes

Distribución

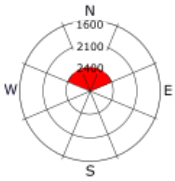

Tamaño

Origen

Tendencia

Estado del manto nivoso

El manto sigue endurecido, encostrado en todas las orientaciones desde los 2.000 m hasta las cotas más altas. Para el miércoles, a primera hora, el manto estará rehelado y con el paso de las horas, debido a la radiación solar, se humedecerá. En solanas, en terreno con fuerte inclinación, pueden caer aludes naturales de fusión de forma natural o a nuestro paso esquiando que llegarán a tamaño 1 (pequeño), sin capacidad para enterrar a una persona. En umbrías elevadas, en el límite norte con el Aran, podemos encontrar, muy localmente, alguna placa antigua sobre niveles débiles que con un sobrecarga fuerte, podría caer y generar aludes de tamaño 2 (medio), con capacidad de enterrarnos. Los lugares delicados están bajo collados y cordales, por encima de 2.500 m. A última hora se intensificará el viento en altura. Habrá que vigilar con los resbalones a primera hora por la presencia de costras duras. Recuerde llevar siempre el DVA, pala y sonda, además del casco, crampones y el piolet.

Distribución del manto nivoso

Hay nieve en el suelo a 1.600 m en N, y a 1.800-1.900 m en S. El manto es esquiable por encima de unos 1.800-1.900 m en umbrías. Los espesores alcanzan los 115-155 cm en cotas medias, variable según los efectos del viento.

Tendencia para las próximas 48-72h

Caerán algunos chubascos con fuerte viento del NW, con problemas por placas de viento. Peligro: EN PROGRESIVO ASCENSO.

El próximo boletín será emitido el día 2026-03-25

5 MUY FUERTE	4 FUERTE	3 NOTABLE	2 LIMITADO	1 DÉBIL

EAWS EUROPEAN AVALANCHE WARNING SERVICES

ICGC Institut Cartogràfic i Geològic de Catalunya

Servei Meteorològic de Catalunya meteo.cat

Boletín de peligro de aludes Perafita-Puigpedrós Del 24/03/2026 al 25/03/2026

(Válido fuera pistas de esquí y zonas no controladas)

DÉBIL (1), LIMITADO (2), durante las horas centrales del día.

Situación primaria

Nieve húmeda

Distribución

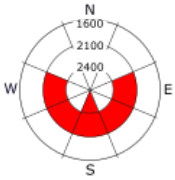

Tamaño

Origen

Tendencia

Estado del manto nivoso

Seguiremos con un manto bien asentado, con una mañana de buen rehielo y una progresiva transformación de la nieve, en las horas centrales del día, debido a la radiación solar. Con el humedecimiento de las costras superficiales pueden caer aludes de fusión de forma natural oa nuestro paso, esquiando, que llegarán a tamaño 1 (pequeño), sin capacidad para enterrar a una persona. El terreno más afectado por aludes de fusión son las salidas de puntos oscuros (rocas y árboles) y terreno con fuerte inclinación a solanas, como canales y pasillos. En umbrías elevadas, en el límite norte con el Aran, podemos encontrar, muy localmente, alguna placa antigua sobre niveles débiles con un sobrecarga fuerte, podría acabar cayendo, y generar aludes de tamaño 2 (medio), con capacidad de enterrar a un montañero. Habrá que vigilar con los resbalones a primera hora, por la presencia de costras duras. Recuerde llevar siempre el DVA, pala y sonda, además del casco, crampones y el piolet.

Distribución del manto nivoso

En umbrías hay nieve por encima de 1.600 m y las solanas está presente por encima de 1.900 m. Los espesores, aunque irregulares, rondan los 80-100 cm en umbrías, a 2.300 m. Son grosores por encima de los habituales en esta época.

Tendencia para las próximas 48-72h

Entre el miércoles por la noche y el viernes nevará, con fuerte viento del NW. Las placas de viento se engrosarán. Peligro: EN PROGRESIVO ASCENSO.

El próximo boletín será emitido el día 2026-03-25

5 MUY FUERTE	4 FUERTE	3 NOTABLE	2 LIMITADO	1 DÉBIL

EAWS EUROPEAN AVALANCHE WARNING SERVICES

ICGC Institut Cartogràfic i Geològic de Catalunya

Servei Meteorològic de Catalunya meteo.cat

Boletín de peligro de aludes
Vessant Nord Cadí-Moixeró
Del 24/03/2026 al 25/03/2026

(Válido fuera pistas de esquí y zonas no controladas)

DÉBIL (1), LIMITADO (2), durante las horas centrales del día por encima de los 2.200 m.

Situación primaria

Nieve húmeda

Distribución

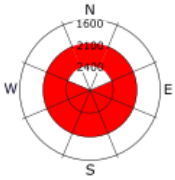

Tamaño

Origen

Tendencia

Estado del manto nivoso

Seguiremos con un manto rehelado y endurecido, sobre todo a primera hora. Con el avance de la jornada, la radiación solar provocará el humedecimiento superficial del manto y ablandará las costras. En las solanas más elevadas pueden caer aludes pequeños de fusión de forma natural y también a nuestro paso, esquiando, sin capacidad para enterrar a una persona, excepto en terreno trampa donde habrá que evitar pasar mientras la nieve no rehiele, durante las horas centrales del día. El terreno más afectado por aludes de fusión son las zonas de salida de puntos oscuros como rocas y árboles. Habrá que vigilar los resbalones, sobre todo en lo alto de las Canals y bajo collados y crestas más elevadas.

Distribución del manto nivoso

En umbrías hay presencia discontinua de nieve por encima de 1.600 m y es esquiable por encima de 1.900 m. Los grosores están alrededor de 160-180 cm a 2.200 m. Estos valores son muy excedentarios para la época del año.

Tendencia para las próximas 48-72h

Se podrán formar algunas placas, pequeñas, bajo collados o cordales, con los chubascos con viento previstos. Peligro: SIN CAMBIOS o EN LEVE ASCENSO.

El próximo boletín será emitido el día 2026-03-25

5 MUY FUERTE	4 FUERTE	3 NOTABLE	2 LIMITADO	1 DÉBIL

EAWS EUROPEAN AVALANCHE WARNING SERVICES

ICGC Institut Cartogràfic i Geològic de Catalunya

Servei Meteorològic de Catalunya

Boletín de peligro de aludes Prepirineu
Del 24/03/2026 al 25/03/2026

(Válido fuera pistas de esquí y zonas no controladas)

DÉBIL (1).

Situación primaria

Nieve húmeda

Distribución

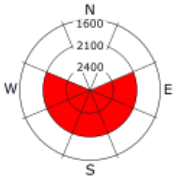

Tamaño

Origen

Tendencia

Estado del manto nivoso

El manto sigue bastante endurecido internamente, con presencia de costras duras, grano fino y algunas formas mixtas. Para el miércoles se espera rehielo, después de una madrugada serena, y el manto seguirá asentado y con condiciones bastante estables. Debido a la transformación de la nieve por la radiación solar, a partir de mediodía, con el humedecimiento diurno, no se descarta la caída de bolas o de algún alud húmedo, pequeño, accidental, a nuestro paso con los esquís, que no tendrá capacidad para enterrar a una persona, excepto en terreno trampa donde habrá que evitar pasar durante las horas. Las orientaciones más sensibles a la caída de aludes de nieve húmeda son las orientadas a Sur y Oeste. Habrá que vigilar con los resbalones, sobre todo por la mañana. Recuerde llevar siempre el DVA, pala y sonda, además del casco, los crampones y el piolet.

Distribución del manto nivoso

En umbrías hay nieve por encima de 1700 m. En solanas la nieve está presente por encima de 1.900 m, discontinua. Los espesores, aunque irregulares, rondan los 100-120 cm cm a 2.300 m.

Tendencia para las próximas 48-72h

Seguiremos con un manto asentado y endurecido. Peligro: SIN CAMBIOS.

El próximo boletín será emitido el día 2026-03-25

5 MUY FUERTE	4 FUERTE	3 NOTABLE	2 LIMITADO	1 DÉBIL

EAWS EUROPEAN AVALANCHE WARNING SERVICES

ICGC Institut Cartogràfic i Geològic de Catalunya

Servei Meteorològic de Catalunya

Boletín de peligro de aludes Ter-Freser
Del 24/03/2026 al 25/03/2026

(Válido fuera pistas de esquí y zonas no controladas)

DÉBIL (1), LIMITADO (2), por encima de 2.500 m, y a partir de mediodía.

Situación primaria

Nieve venteada

Distribución

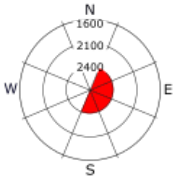

Tamaño

Origen

Tendencia

Situación secundaria

Nieve húmeda

Distribución

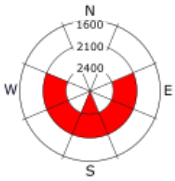

Tamaño

Origen

Tendencia

Estado del manto nivoso

Seguiremos con problemas por placa de viento a causa del viento previsto. Estas placas formadas con la última nevada se engrosarán con el refuerzo del viento del N y las encontraremos a sotavento, por encima de 2.400 m, en orientaciones Sur y Este. El miércoles se esperan aludes a nuestro paso, en forma de placa, que pueden llegar, por lo general, a medida 1 (pequeño), sin capacidad de enterrar a una persona. A primera hora el manto estará rehelado, después de una madrugada fría y serena, y con el paso de las horas, debido a la radiación solar, se humedecerá. En solanas o en umbrías de cota media, en terreno con fuerte inclinación, pueden caer aludes de nieve húmeda, sobre todo a nuestro paso esquiando, que llegarán a tamaño 1 (pequeño), sin capacidad para enterrar a una persona. Habrá que vigilar con los resbalones a primera hora por la presencia de costras duras, sobre todo en solanas. Recuerde llevar siempre el DVA, pala y sonda, además del casco, crampones y el piolet.

Distribución del manto nivoso

Hay nieve en el suelo por encima de 1.700 m. El manto es esquiable a umbrías a partir de unos 1.800 m. Los grosores son muy excedentarios para la época del año y en lugares no afectados por el viento oscilan entre 80-100 cm a unos 2.000 my más de 150 cm por encima de 2.400 m.

Tendencia para las próximas 48-72h

Las placas de viento continuarán reactivas, bajo collados y crestas elevadas, a sotavento del viento del Norte. Peligro: EN LEVE ASCENSO.

El próximo boletín será emitido el día 2026-03-25

5 MUY FUERTE	4 FUERTE	3 NOTABLE	2 LIMITADO	1 DÉBIL

EAWS EUROPEAN AVALANCHE WARNING SERVICES