BUTLLETÍ DEL PERILL D'ALLAUS DEL PRINCIPAT D'ANDORRA

Elaborado el 24/03/2026 16:00
Proxima actualización 25/03/2026 a las 16h

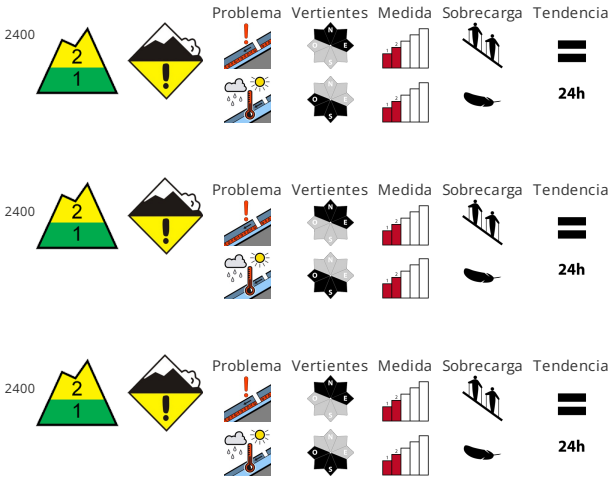

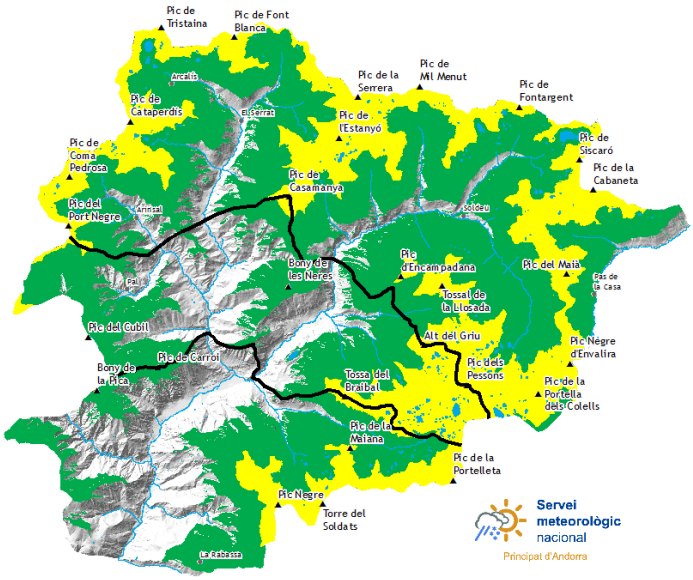

CALIDAD DE LA NIEVE

La nieve reciente del domingo descansa encima de capas blandas en laderas umbrías. Todavía aquí en la parte superior del manto de nieve hay capas débiles de cristales gruesos. Estos pueden ser desencadenadas sobre todo por una sobrecarga fuerte y alcanzar un tamaño mediano. Las capas débiles en la parte superior del manto de nieve requieren cautela. Además del peligro de ser enterrado por un alud, se debe tener en cuenta el peligro de ser arrastrado hacia una trampa del terreno. En las laderas inclinadas solanas :. Con la penetración de la humedad, en el transcurso de la jornada son posibles avalanchas de nieve húmeda, pero en su mayoría pequeñas. Además son posibles algunos aludes de deslizamiento basal. Con el enfriamiento, el jueves el peligro de aludes de nieve húmeda disminuirá.

ESTABILIDAD DEL MANTO NIVOSO

En las laderas inclinadas solanas :. La superficie del manto de nieve se volverá a helar para formar una costra portante y se ablandará durante el día. Debido a la costra dura hay el peligro de resbalar y caer en las laderas inclinadas. En las laderas inclinadas orientadas a noroeste, norte y nordeste y en cotas altas :. La parte superior del manto es blanda , con una superficie formada por nieve de débil cohesión. Cerca de los cordales los espesores de nieve varían mucho por la influencia del viento.

ESPESORES DEL MANTO NIVOSO FUERA DE PISTA

BUTLLETÍ DEL PERILL D'ALLAUS DEL PRINCIPAT D'ANDORRA

Servei meteorològic nacional
Principat d'Andorra

Zona norte		Espesor nieve		
Manto Nival		1500m	2000m	2500m
N	1600 m	0 cm	150 cm	200 cm
S	1900 m	0 cm	100 cm	150 cm

Zona centro		Espesor nieve		
Manto Nival		1500m	2000m	2500m
N	1600 m	0 cm	150 cm	200 cm
S	1900 m	0 cm	100 cm	150 cm

Zona sur		Espesor nieve		
Manto Nival		1500m	2000m	2500m
N	1600 m	0 cm	120 cm	150 cm
S	1900 m	0 cm	60 cm	100 cm

BUTLLETÍ DEL PERILL D'ALLAUS DEL PRINCIPAT D'ANDORRA

Servei meteorològic nacional
Principat d'Andorra

Información detallada por espacios naturales protegidos

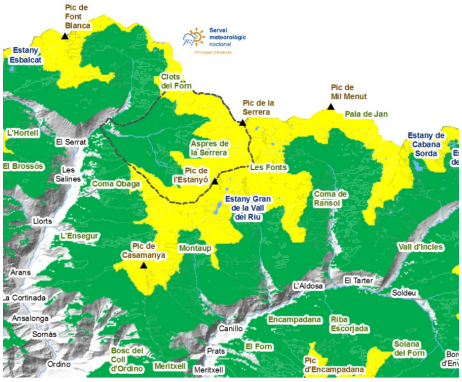

SORTENY

Las débiles nevadas de la noche del domingo no han cambiado la estabilidad del manto. Deberemos continuar manteniendo la cautela en las vertientes norte y este donde pueden existir capas débiles persistentes formadas por gran angulosos, ligeramente recubiertas por la nieve reciente, no transformada. En el transcurso de la jornada y con la penetración de la humedad, volveremos a tener nieve blanda por debajo de 2.400 metros.

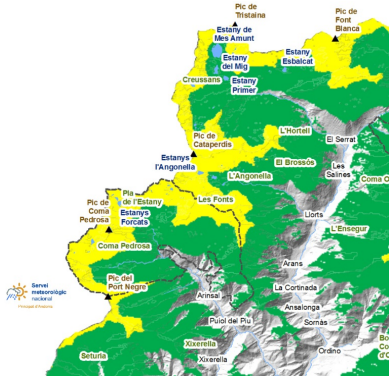

COMAPEDROSA

Como en todo el país, en las vertientes norte y este en altura encontraremos capas débiles todavía solicitables, con las que tendremos que prestar atención. A medida que avance el día también deberemos prestar atención a los problemas de nieve húmeda en las vertientes soleadas más inclinadas ya los pies de paredes rocosas. Puede haber actividad de aludes de fondo con las grietas abiertas.

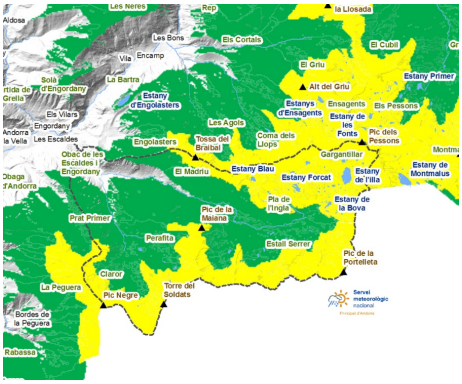

MADRIU-PERAFITA-CLAROR

Aunque en los últimos días la nieve ha sufrido un retroceso importante en cotas bajas, todavía hay nieve suficiente para realizar numerosas rutas. Deberemos ser especialmente cautelosos en las laderas con problemas de capas débiles persistentes.

Govern d'Andorra

EAWS
EUROPEAN AVALANCHE WARNING SERVICES

Aquest butlletí ha estat elaborat seguint les normes i recomanacions de l'**European Avalanche Warning Services**, del qual el **Servei meteorològic Nacional** n'és membre

BUTLLETÍ DEL PERILL D'ALLAUS DEL PRINCIPAT D'ANDORRA

Servei meteorològic nacional
Principat d'Andorra

Espesores de nieve nueva de los últimos días (de las ultimas 24h mesurado a las 06:00h UTC)

	20/03/2026	21/03/2026	22/03/2026	23/03/2026
FEDA (Central)	0 cm	0 cm	0 cm	0 cm
Engolasters - FEDA	0 cm	0 cm	0 cm	0 cm
Bony de les Neres	0 cm	0 cm	3 cm	0 cm
Sorteny	0 cm	0 cm	4 cm	0 cm
Les Fonts d'Arinsal	0 cm	0 cm	7 cm	0 cm
Perafita	0 cm	0 cm	7 cm	0 cm
Tossa Espiolets	0 cm	0 cm	3 cm	0 cm
Grau Roig - FEDA	0 cm	0 cm	7 cm	0 cm
Fontverd	0 cm	0 cm	0 cm	0 cm
Ransol - FEDA	0 cm	0 cm	2 cm	0 cm
Caborreu	0 cm	0 cm	0 cm	0 cm
La Solana	0 cm	0 cm	10 cm	0 cm
Envalira Antenes	0 cm	0 cm	6 cm	0 cm
Vall del Riu FEDA	0 cm	0 cm	5 cm	0 cm