BUTLLETÍ DEL PERILL D'ALLAUS DEL PRINCIPAT D'ANDORRA

Préparé le 24/03/2026 16:00
Prochaine mise à jour le 25/03/2026 à 16h

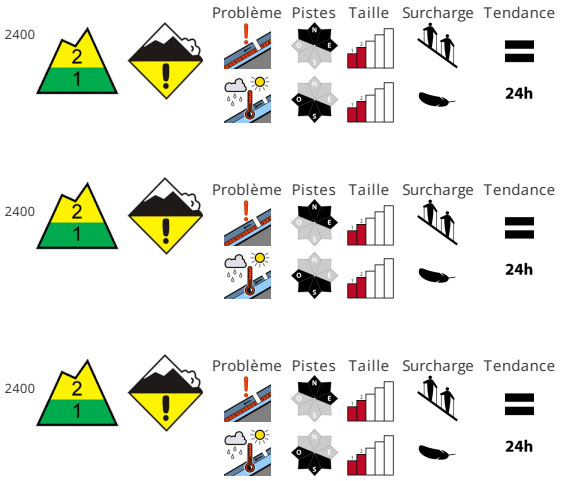

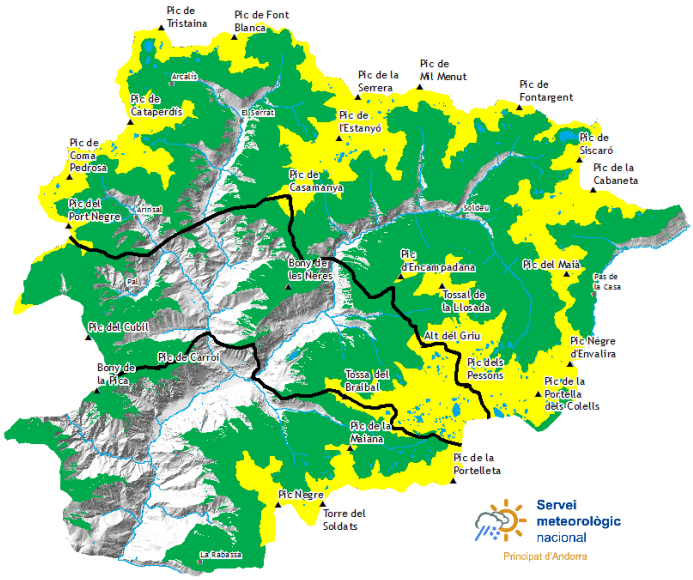

STABILITÉ DU MANTEAU NEIGEUX

La neige fraîche de dimanche repose sur des couches meubles au sur les pentes à l'ombre. Dans la partie supérieure du manteau neigeux des couches fragiles à gros grains sont présentes ils se rencontrent , aussi dans ces endroits. Celles-ci peuvent peut être déchaîné surtout avec une surcharge importante et atteindre une taille moyenne.. Des couches fragiles en partie supérieure du manteau neigeux demandent de la prudence.. A côté du danger d'ensevelissement, il faut penser au danger d'être emporté et de chuter.. Sur les pentes raides ensoleillées (-):. Avec l'humidification totale en cours de journée des avalanches humides sont possibles ils sont , mais en général uniquement de petite taille. En outre, des avalanches de glissement isolées sont possibles.. Avec le refroidissement le danger d'avalanches humides diminue jeudi.

QUALITÈ DE LA NEIGE

Sur les pentes raides ensoleillées (-):. La surface de la neige regèle et devient porteuse et se ramollit en cours de journée.. Sur la croûte dure il existe en terrain raide un risque de chute.. Sur les pentes raides exposées au nord-ouest , au nord et au nord-est et à haute altitude (-):. La zone supérieure du manteau neigeux est meuble , avec une surface de neige meuble. À proximité des crêtes on trouve suivant l'influence du vent des hauteurs de neiges très différentes.

EPAISSEUR DE NEIGE HORS PISTE

Zone nord		Epaisseur de neige		
Nival manteau		1500m	2000m	2500m
N	1600 m	0 cm	150 cm	200 cm
S	1900 m	0 cm	100 cm	150 cm

Zone centre		Epaisseur de neige		
Nival manteau		1500m	2000m	2500m
N	1600 m	0 cm	150 cm	200 cm
S	1900 m	0 cm	100 cm	150 cm

Zone sud		Epaisseur de neige		
Nival manteau		1500m	2000m	2500m
N	1600 m	0 cm	120 cm	150 cm
S	1900 m	0 cm	60 cm	100 cm

Govern d'Andorra

EAWS EUROPEAN AVALANCHE WARNING SERVICES

Aquest butlletí ha estat elaborat seguint les normes i recomanacions de l'**European Avalanche Warning Services**, del qual el **Servei meteorològic Nacional** n'és membre

BUTLLETÍ DEL PERILL D'ALLAUS DEL PRINCIPAT D'ANDORRA

Servei meteorològic nacional
Principat d'Andorra

Des informations détaillées par espace naturel protégé

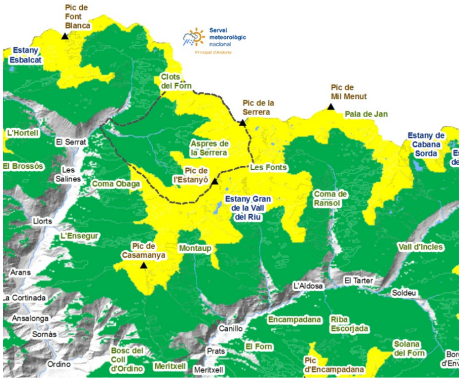

SORTENY

Les légères chutes de neige de dimanche soir n'ont pas modifié la stabilité du manteau. Il faudra continuer à rester prudent sur les versants nord et est où pourraient persister des couches faibles persistantes formées de grosses anguleuses, légèrement recouvertes de neige récente non transformée. Au cours de la journée et avec la pénétration de l'humidité, nous aurons à nouveau de la neige molle en dessous de 2 400 mètres. , , , , ,

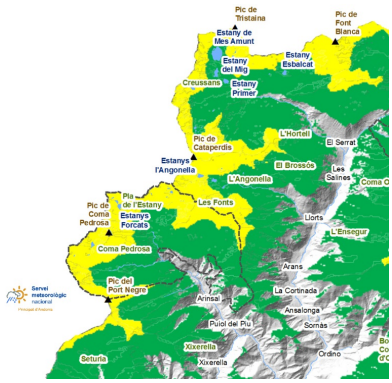

COMAPEDROSA

Comme dans tout le pays, sur les pentes nord et est en hauteur, nous trouverons des couches faibles encore applicables, auxquelles nous devrons faire attention. Au fil de la journée, il faudra également faire attention aux problèmes de neige mouillée sur les pentes plus raides et ensoleillées et au pied des parois rocheuses. Il peut y avoir une activité avalancheuse en arrière-plan avec les fissures ouvertes. , , , , ,

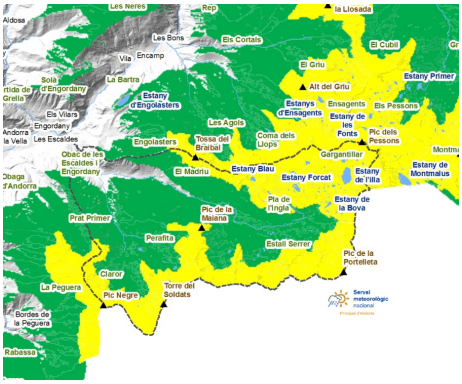

MADRIU-PERAFITA-CLAROR

Même si la neige a nettement reculé dans les basses altitudes ces derniers jours, il reste encore suffisamment de neige pour parcourir de nombreux itinéraires. Il faudra être particulièrement prudent sur les pentes présentant des problèmes persistants de couches fragiles. , , ,

Govern d'Andorra

EAWS
EUROPEAN AVALANCHE WARNING SERVICES

Aquest butlletí ha estat elaborat seguint les normes i recomanacions de l'**European Avalanche Warning Services**, del qual el **Servei meteorològic Nacional** n'és membre

BUTLLETÍ DEL PERILL D'ALLAUS DEL PRINCIPAT D'ANDORRA

Servei meteorològic nacional
Principat d'Andorra

Couche de neige fraiche des derniers jours (De 24 h mesurée à 06:00 h UTC)

	20/03/2026	21/03/2026	22/03/2026	23/03/2026
FEDA (Central)	0 cm	0 cm	0 cm	0 cm
Engolasters - FEDA	0 cm	0 cm	0 cm	0 cm
Bony de les Neres	0 cm	0 cm	3 cm	0 cm
Sorteny	0 cm	0 cm	4 cm	0 cm
Les Fonts d'Arinsal	0 cm	0 cm	7 cm	0 cm
Perafita	0 cm	0 cm	7 cm	0 cm
Tossa Espiolets	0 cm	0 cm	3 cm	0 cm
Grau Roig - FEDA	0 cm	0 cm	7 cm	0 cm
Fontverd	0 cm	0 cm	0 cm	0 cm
Ransol - FEDA	0 cm	0 cm	2 cm	0 cm
Caborreu	0 cm	0 cm	0 cm	0 cm
La Solana	0 cm	0 cm	10 cm	0 cm
Envalira Antenes	0 cm	0 cm	6 cm	0 cm
Vall del Riu FEDA	0 cm	0 cm	5 cm	0 cm