MINISTERO DELLA DIFESA

meteomont
Servizio Nazionale di previsione neve e valanghe

EAWS EUROPEAN AVALANCHE WARNING SERVICES

CARABINIERI

P.N. ABRUZZO

Bollettino Valanghe N. 339/2026 del 24/03/2026 ore 14.00
Validità 48 ore prossima emissione 25/03/2026

A cura del Servizio METEOMONT dell'ARMA dei CARABINIERI
In collaborazione con Servizio Meteorologico dell'Aeronautica militare

SITUAZIONE alle 14:00 del 24/03/2026

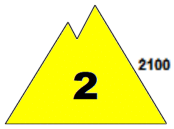

SITUAZIONE TIPO: neve a debole coesione e vento.

SITUAZIONE TIPO: situazione primaverile.

Quota neve (mslm)	Nord	Sud
	1300 - 1400	1400 - 1500

Altezza Neve (cm)	Neve al suolo	Neve Fresca	Quota (mslm)
	010	009	1520
	010	004	1456

VALANGHE OSSERVATE: Nessuna valanga.

PREVISIONI 25/03/2026

GRADO DI PERICOLO: MODERATO 2

SITUAZIONE TIPO: neve a debole coesione e vento.

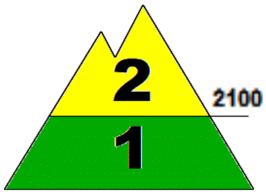

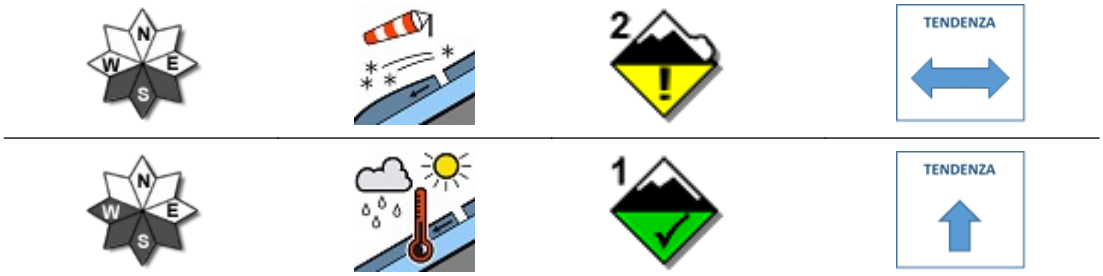

SITUAZIONE TIPO: situazione primaverile.

MANTO NEVOSO: La stabilità del manto nevoso è discreta su alcuni punti (aree) per versanti meridionali al di sopra di 2100 mslm, possibili valanghe di dimensioni medie.
La stabilità del manto nevoso è discreta su alcuni punti (aree) per versanti al sole al di sotto di 2100 mslm, possibili valanghe di dimensioni piccole.

AVVERTENZE

Il rialzo termico diurno richiede un'attenta valutazione temporale dell'escursione che eviti l'attraversamento di pendii ripidi nelle ore più calde della giornata.

SCALA EUROPEA DEL GRADO DI PERICOLO VALANGHE

LEGENDA PROBLEMA

Bollettino realizzato su scala sinottica-regionale (standard EAWS). La sua valutazione non può escludere in alcun modo la necessità di una seria e capace valutazione locale del pericolo (singolo pendio) che può essere anche sensibilmente diverso. Le previsioni meteorologiche sono relative all'orario UTC (per l'Italia +1 in inverno e +2 in estate).

MINISTERO DELLA DIFESA

meteomont
Servizio Nazionale di previsione neve e valanghe

EAWS EUROPEAN AVALANCHE WARNING SERVICES

CARABINIERI

P.N. ABRUZZO

PREVISIONE METEO

Quota		25/03/2026 h6:00	25/03/2026 h12:00	25/03/2026 h18:00
1000	Venti	02 Nodi da Nord	03 Nodi da Ovest	02 Nodi da S-Ovest
	Temperature	+01 °C	+06 °C	+03 °C
	Temp.percepita	1 °C	5 °C	3 °C
2000	Venti	03 nodi da N-Ovest	03 nodi da N-Ovest	10 Nodi da Ovest
	Temperature	-01 °C	+00 °C	+00 °C
	Temp.percepita	-3 °C	-2 °C	-5 °C
3000	Venti	06 Nodi da Nord	07 nodi da N-Ovest	13 Nodi da Ovest
	Temperature	-06 °C	-04 °C	-01 °C
	Temp.percepita	-11 °C	-9 °C	-7 °C
Zero termico		1800-2000 m.	2000-2200 m.	1800-2000 m.
Fenomeno		—	—	—
Stato del cielo				

LEGENDA FENOMENI

— Assenza Fenomeni · Nebbia · Foschia · Pioggia debole · Pioggia moderata · Pioggia forte · Temporali

Nevicata debole · Nevicata moderata · Nevicata forte

STATO DEL CIELO

Sereno · Poco nuvoloso · Nuvoloso · Molto nuvoloso · Coperto

Parametri meteonivometrici registrati presso i campi di rilevamento il 24/03/2026.

Località	Comune	Quota (m.s.l.m.)	Altezza neve (cm)	Neve caduta nelle 24 ore (cm)	Temp. Min (°C)	Temp. Max (°C)	Condizioni del tempo
FORCA D'ACERO	Pescasseroli (AQ)	1480	13	13	-4	+6	Assenza di precipitazioni
VALLE GELATA	Pescocostanzo (AQ)	1466	13	2	-1	+7	Assenza di precipitazioni
COPPO DELL'ORSO	Villetta Barrea (AQ)	1520	10	9	-5	+1	Assenza di precipitazioni
LA PESCINA	Rivisondoli (AQ)	1470	13	6	-3	+2	Assenza di precipitazioni
PIANO AREMOGNA	Roccaraso (AQ)	1456	10	4	+1	+5	Assenza di precipitazioni
MIMOLA	Scanno (AQ)	1495	9	5	-3	+7	Assenza di precipitazioni

(*) Rilievi fuori campo

L'INFORMAZIONE E' PREVENZIONE - LEGGI L'ATTUALE GRADO DI PERICOLO VALANGHE!

IL CAPO DEL CENTRO NAZIONALE METEOMONT
(Ten. Col. RFI Emanuela Gini)
FIRMA AUTOGRAFA OMESSA AI SENSI
DELL'ART.3 DEL D.LGS N.39/1993

Bollettino realizzato su scala sinottica-regionale (standard EAWS). La sua valutazione non può escludere in alcun modo la necessità di una seria e capace valutazione locale del pericolo (singolo pendio) che può essere anche sensibilmente diverso. Le previsioni meteorologiche sono relative all'orario UTC (per l'Italia +1 in inverno e +2 in estate).