Bulletin d'estimation du risque d'avalanche

(valable en dehors des pistes balisées et ouvertes)

MASSIF : Chartreuse

Rédigé le mardi 24 mars 2026 à 15h

Estimation des risques pour le : MERCREDI 25 MARS

INTEMPERIES A PARTIR DE MERCREDI APRES-MIDI, NEIGE FRAICHE TRES SOUFFLEE ; PETITES PLAQUES EN FORMATION...

2

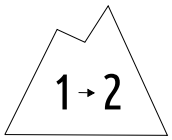

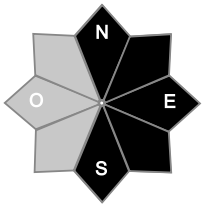

AP-MIDI en altitude

Indice de risque faible évoluant en limité.

Départs spontanés : Peu probables puis mercredi soir, coulées superficielles en terrain raide, chargé par le vent...

Déclenchements provoqués : Mercredi en fin d'après-midi petites plaques se formant sous le vent de Nord-Ouest , parfois assez loin des crêtes...

Indices de risque : 5 très fort - 4 fort - 3 marqué - 2 limité - 1 faible -- En noir : les pentes les plus dangereuses

Stabilité du manteau neigeux

Situation avalancheuse typique : neige ventée

En matinée, neige souvent stable et encore consolidée par regel nocturne. L'après-midi on attend jusque 10 puis 15 cm sur les hauts du massifs, bien soufflés par le vent de Nord-Ouest...

Départs spontanés :
Peu probables le matin, neige dense, encore parfois tendue par regel.
Puis en cours d'après-midi/ mercredi soir des coulées superficielles sont possibles en pentes raides, notamment en secteur chargé par le vent...
Déclenchements provoqués :
Plutôt en fin d'après-midi ou soirée, le fort vent de Nord-Ouest forme quelques accumulations et plaques temporairement instables, parfois loin des crêtes...

Qualité de la neige

Qualification de l'enneigement : L'enneigement est bon pour la saison, notamment en faces Nord, dès la moyenne montagne (hors sapins où la neige manque). Peu de sous couche en plein Sud, anciens secteurs de reptation (herbes à nu localement)...
Limites skiables : Vers 1200/1600m.

Qualité de la neige mercredi : Neige dense croutée ou durcie par regel nocturne. Puis humidification locale au soleil du mercredi matin... L'après-midi coup de frais en vue. Averses de neige dès 1400 puis 1100m, 900m le soir.
Rapide formation d'une petite couche de fraîche, très ventée... En altitude alternance de secteurs dénudés et congères...

Aperçu météo pour le mercredi 25 mars

nuit	matin	après-midi	soir

Nuit calme/ regel. Mercredi matin assez beau, déjà venté vers les sommets. L'après-midi arrivée d'un front d'averses neigeuses, bourrasques/froid...

Pluie-Neige			1 100 m	600 m
Iso 0 °C	2 600 m	2 300 m	1 400 m	1 000 m
Vent 1500 m	↗ 10 km/h	↗ 25 km/h	↘ 55 km/h	↓ 50 km/h
Vent 2000 m	↗ 25 km/h	→ 40 km/h	↘ 65 km/h	↓ 70 km/h

Épaisseur de neige hors-piste

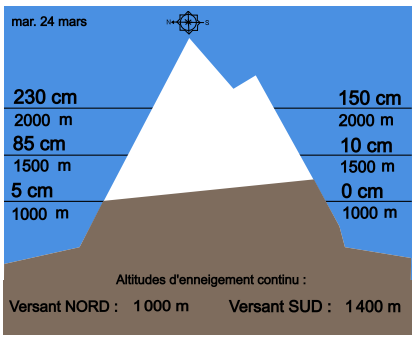

Précipitations à 1800 m

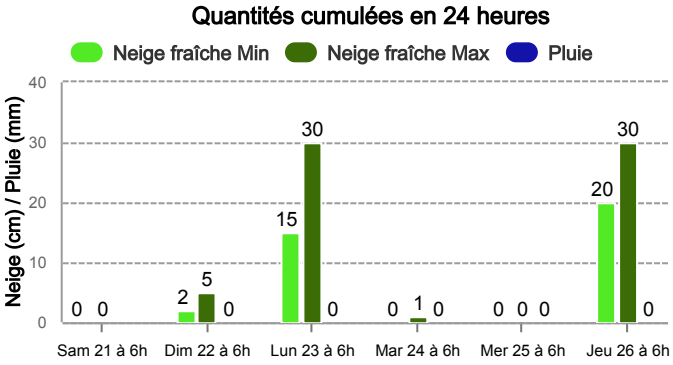

Tendance du jeudi 26 mars

3

Indice de risque marqué

Jeudi risque d'avalanche probablement marqué en Chartreuse avec jusque 40 puis 50/60 cm de neige froide très soufflée. Risque de plaques instables dès modeste altitude, sous le vent de Nord + au fil des heures des avalanches spontanées en couloirs/pentes chargées...

Pour consulter la vigilance en cours, veuillez vous rendre sur le site https://vigilance.meteofrance.fr/fr

Météo-France - 73 avenue de Paris, 94165 Saint-Mandé cedex - Contact : contact@meteo.fr

Rédigé par Météo-France avec la contribution des observateurs du réseau nivo-météorologiques. Partenariat : ANMSM (Maires de Stations de Montagne), DSF (Domaines Skiables de France), ADSP (Directeurs de Pistes et de la Sécurité des Stations de Sports d'Hiver) et autres acteurs de la montagne.

Bulletin neige & avalanches par téléphone au

0 892 68 10 20 Service 0,35 € / min + prix appel

RÉPUBLIQUE FRANÇAISE
Liberté Égalité Fraternité

METEO FRANCE
À VOS CÔTÉS, DANS UN CLIMAT QUI CHANGE

Bulletin d'estimation du risque d'avalanche

(valable en dehors des pistes balisées et ouvertes)

MASSIF : Chartreuse

Rédigé le mardi 24 mars 2026 à 15h

Conditions nivo-météo des 7 derniers jours

	mer. 18/03				jeu. 19/03				ven. 20/03				sam. 21/03				dim. 22/03				lun. 23/03				mar. 24/03			
	03h	09h	15h	21h	03h	09h	15h	21h	03h	09h	15h	21h	03h	09h	15h	21h	03h	09h	15h	21h	03h	09h	15h	21h	03h	09h	15h	21h
Météo																												
Vent (km/h)	25	25	35	40	35	25	20	10	15	5	0	5	5	15	10	10	10	10	5	10	15	25	25	15	30	15	5	10
à 2000m	↓	↓	←	↖	↖	↙	↙	↙	↙	↙	↘	↓	↙	↙	↘	↓	→	↗	↑	↓	↙	↙	↙	↙	↓	↙	↙	→
Vent (km/h)	10	15	15	10	10	15	15	5	5	0	0	5	10	10	5	5	10	5	5	5	5	10	20	10	15	10	15	10
à 1500m	↙	↙	↘	↘	↓	↓	↘	↙	↙	↘	↙	↙	↙	↓	↓	↓	↘	→	↑	↓	↙	↓	↓	↙	↙	↙	↘	↖

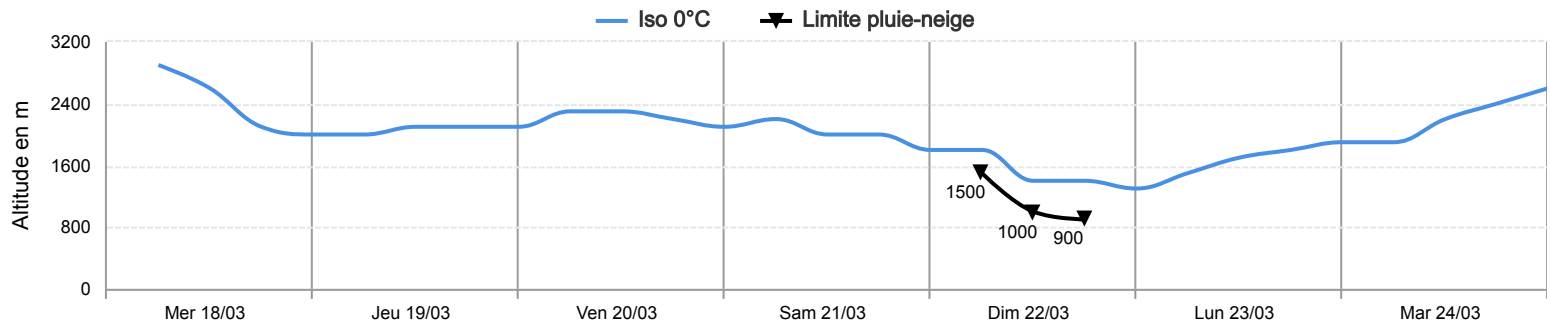

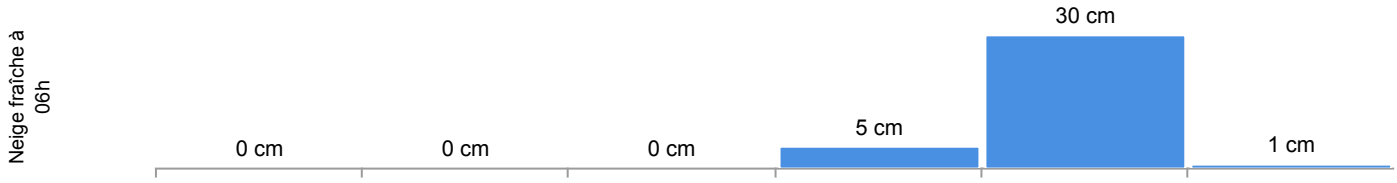

Risque d'avalanche	mer. 18/03	jeu. 19/03	ven. 20/03	sam. 21/03	dim. 22/03	lun. 23/03	mar. 24/03
	2	2	1	1	2	2	2

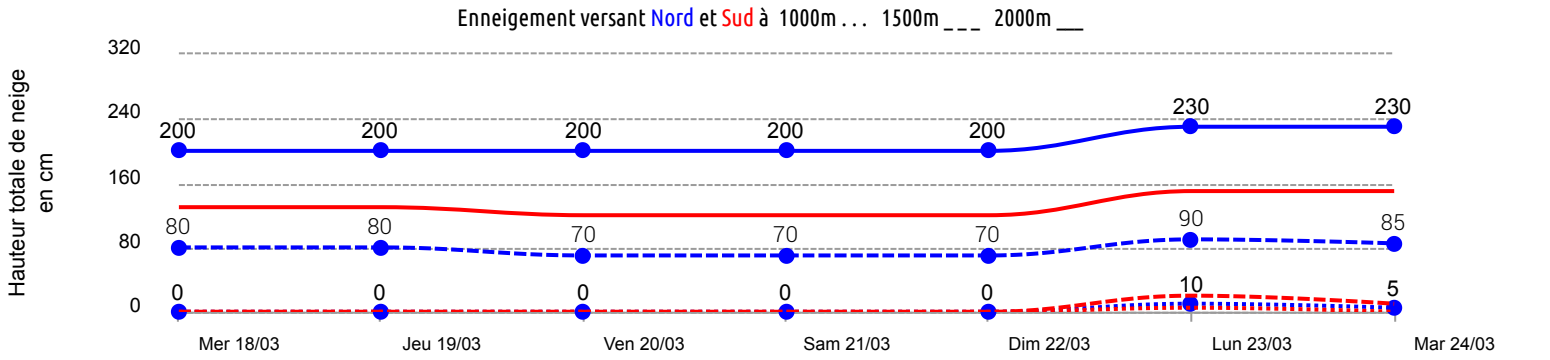

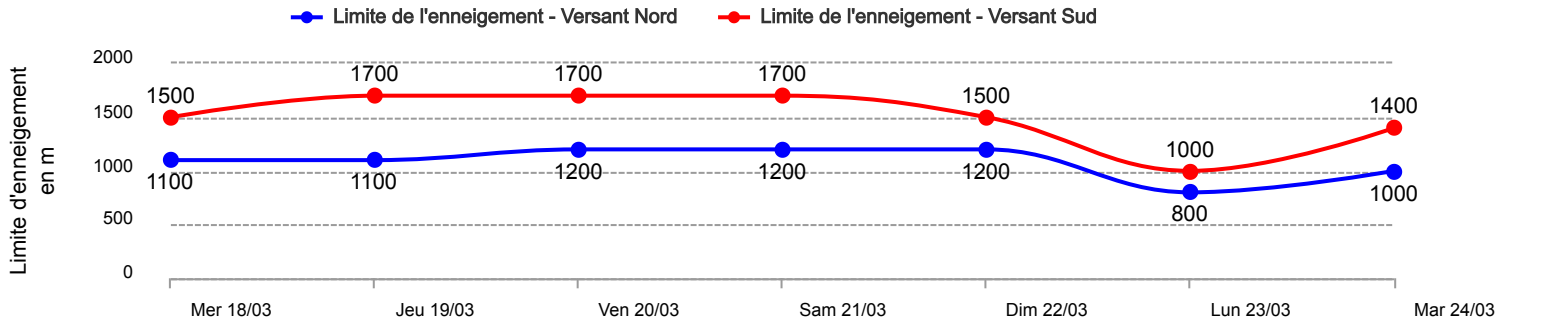

Pour consulter la vigilance en cours, veuillez vous rendre sur le site https://vigilance.meteofrance.fr/fr

Météo-France - 73 avenue de Paris, 94165 Saint-Mandé cedex - Contact : contact@meteo.fr

Rédigé par Météo-France avec la contribution des observateurs du réseau nivo-météorologiques. Partenariat : ANMSM (Maires de Stations de Montagne), DSF (Domaines Skiables de France), ADSP (Directeurs de Pistes et de la Sécurité des Stations de Sports d'Hiver) et autres acteurs de la montagne.

Bulletin neige & avalanches par téléphone au

0 892 68 10 20 Service 0,35 € / min + prix appel