RÉPUBLIQUE FRANÇAISE
*Liberté Égalité Fraternité*

METEO FRANCE
À VOS CÔTÉS, DANS UN CLIMAT QUI CHANGE

# Bulletin d'estimation du risque d'avalanche
## (valable en dehors des pistes balisées et ouvertes)
# MASSIF : Cinto Rotondo

Rédigé le mardi 24 mars 2026 à 15h

## Estimation des risques pour le : MERCREDI 25 MARS

**PERSISTANCE D'INSTABILITÉS EN ALTITUDE DANS LA NEIGE RÉCENTE VENTÉE, QUELQUES COULÉES DE NEIGE HUMIDE EN JOURNÉE DANS LES PENTES ENSOLEILLÉES**

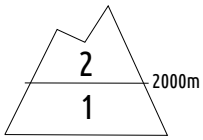


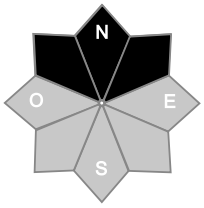


Au-dessus de 2000m indice de risque limité, plus bas indice faible.

**Départs spontanés :** Départs en neige humide au soleil

**Déclenchements provoqués :** Plaques à vent difficilement sollicitables, encore présentes en altitude au-dessus de 2000 m

Indices de risque : 5 très fort - 4 fort - 3 marqué - 2 limité - 1 faible -- En noir : les pentes les plus dangereuses

## Stabilité du manteau neigeux

**Situation avalancheuse typique :** neige ventée neige humide

**Déclenchements provoqués :** De rares plaques sont encore en place en altitude dans les pentes Nord-Ouest à Nord-Est, au-dessus de 2000 m environ. Certaines instabilités peuvent encore céder au passage d'un skieur dans les pentes raides, parfois cachées sous une fine couche de neige fraîche. Elles peuvent engendrer des avalanches de taille petite à moyenne (taille 1 à 2). En dessous de 2000 m, la neige fraîche repose sur une sous-couche regelée et plus stable.
**Départs spontanés :** En journée, à la faveur d'un redoux et de l'ensoleillement, la neige s'humidifie. Dans les pentes Est à Sud-Ouest, quelques coulées ou avalanches de neige humide (taille 1 à 2) sont possibles dans les pentes raides bien ensoleillées.
**Autres :** Nombreuses surfaces dures et glacées, pouvant être recouvertes de quelques centimètres de neige fraîche.
Présence de corniches parfois volumineuses, dont certaines commencent à se détacher (apparition de fissures).

## Qualité de la neige

**Qualification de l'enneigement :** L'enneigement est excellent pour la saison au-dessus de 1600 m. Sur la Maniccia, à 2400 m d'altitude dans le massif du Rotondo, on relève 3m15 de hauteur de neige totale.
**Limite d'enneigement skiable :** 1500 à 1600 m selon le versant.
**État de la neige** : Sur les versants ensoleillés, la neige devient collante et lourde l'après-midi, particulièrement en-dessous de 2000 m. Plus haut, en pentes NE à NO, elle reste plus froide et assez légère, ou bien densifiée ou durcie sur les zones qui ont été exposées au Grecale. Les croûtes épaisses et les surfaces dures sont très fréquentes. À noter également la présence de corniches parfois volumineuses.

## Aperçu météo pour le mercredi 25 mars

| | nuit | matin | après-midi | soir |
|---|---|---|---|---|
| | | | | |

Redoux prononcé sous un ciel dégagé. Tempête DEBORAH arrivant en soirée.

| | | | | |
|---|---|---|---|---|
| **Pluie-Neige** | | | | 1 200 m |
| **Iso 0 °C** | 2 200 m | 2 200 m | 2 500 m | 1 600 m |
| **Vent 1500 m** | → 10 km/h | ↗ 30 km/h | → 50 km/h | → 80 km/h |
| **Vent 3000 m** | ↘ 20 km/h | ↘ 60 km/h | → 80 km/h | ↗ 120 km/h |

## Épaisseur de neige hors-piste

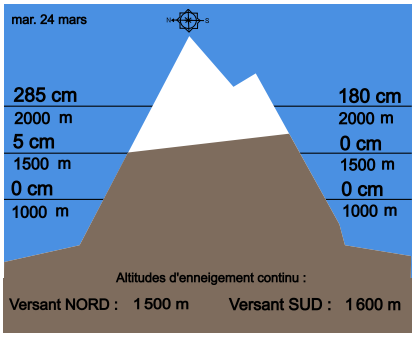


## Précipitations à 1800 m

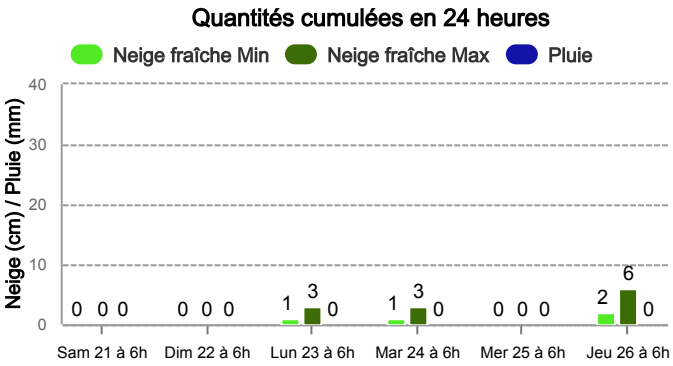


## Tendance du jeudi 26 mars

**Indice de risque limité**

Net refroidissement jeudi avec de faibles chutes de neige à basse altitude. Vent violent.
Maintien d'un risque limité.

Pour consulter la vigilance en cours, veuillez vous rendre sur le site https://vigilance.meteofrance.fr/fr

Météo-France - 73 avenue de Paris, 94165 Saint-Mandé cedex - Contact : contact@meteo.fr

Rédigé par Météo-France avec la contribution des observateurs du réseau nivo-météorologiques. Partenariat : ANMSM (Maires de Stations de Montagne), DSF (Domaines Skiables de France), ADSP (Directeurs de Pistes et de la Sécurité des Stations de Sports d'Hiver) et autres acteurs de la montagne.

Bulletin neige & avalanches par téléphone au
**0 892 68 10 20** Service 0,35 € / min + prix appel

RÉPUBLIQUE FRANÇAISE
*Liberté Égalité Fraternité*

METEO FRANCE
À VOS CÔTÉS, DANS UN CLIMAT QUI CHANGE

# Bulletin d'estimation du risque d'avalanche

(valable en dehors des pistes balisées et ouvertes)

# MASSIF : Cinto Rotondo

Rédigé le mardi 24 mars 2026 à 15h

## Conditions nivo-météo des 7 derniers jours

| | mer. 18/03 | | | | jeu. 19/03 | | | | ven. 20/03 | | | | sam. 21/03 | | | | dim. 22/03 | | | | lun. 23/03 | | | | mar. 24/03 | | | |
|---|---|---|---|---|---|---|---|---|---|---|---|---|---|---|---|---|---|---|---|---|---|---|---|---|---|---|---|---|
| | 03h | 09h | 15h | 21h | 03h | 09h | 15h | 21h | 03h | 09h | 15h | 21h | 03h | 09h | 15h | 21h | 03h | 09h | 15h | 21h | 03h | 09h | 15h | 21h | 03h | 09h | 15h | 21h |
| Météo | | | | | | | | | | | | | | | | | | | | | | | | | | | | |
| Vent (km/h) | 45 | 35 | 40 | 65 | 45 | 30 | 50 | 80 | 80 | 80 | 40 | 50 | 50 | 30 | 15 | 20 | 15 | 20 | 15 | 10 | 10 | 15 | 20 | 40 | 30 | 25 | 20 | 20 |
| à 3000m | | | | | | | | | | | | | | | | | | | | | | | | | | | | |
| Vent (km/h) | 10 | 30 | 20 | 25 | 40 | 35 | 20 | 30 | 30 | 30 | 25 | 25 | 25 | 15 | 10 | 10 | 5 | 10 | 5 | 5 | 5 | 10 | 15 | 30 | 5 | 10 | 10 | 10 |
| à 1500m | | | | | | | | | | | | | | | | | | | | | | | | | | | | |

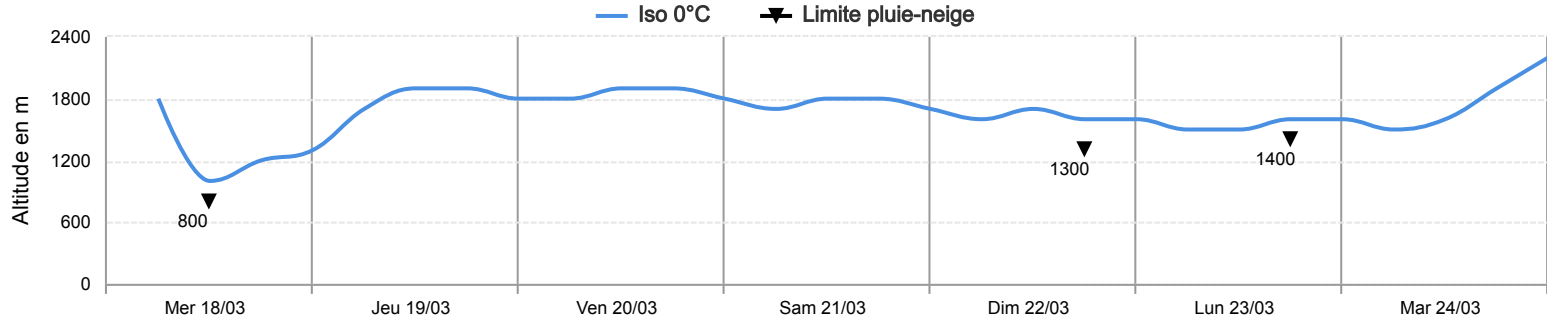


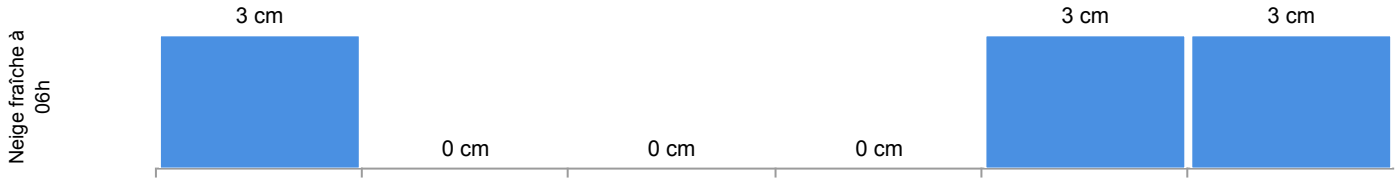


| Risque d'avalanche | mer. 18/03 | jeu. 19/03 | ven. 20/03 | sam. 21/03 | dim. 22/03 | lun. 23/03 | mar. 24/03 |
|---|---|---|---|---|---|---|---|
| | 2 | 2 | 2 | 2 | 2 | 2 | 2 |

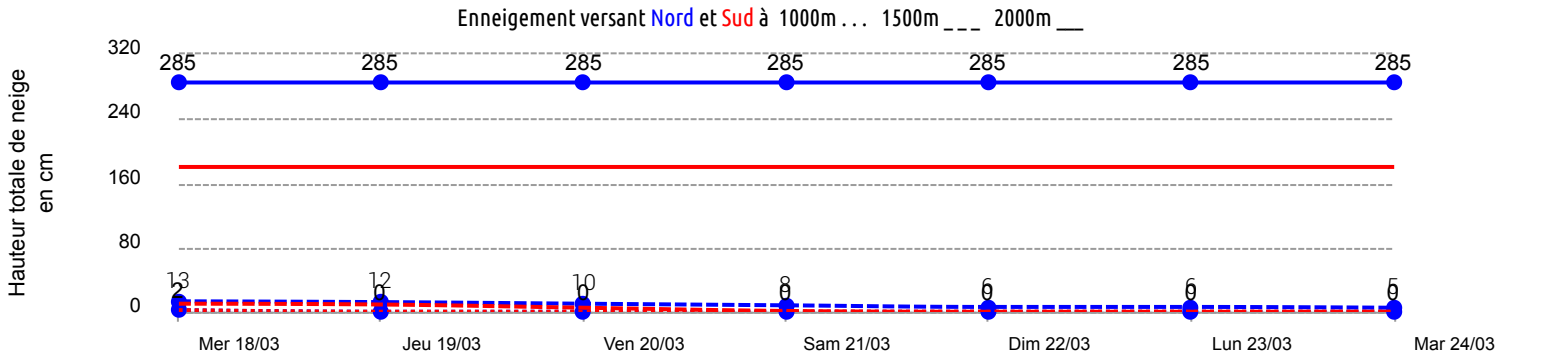


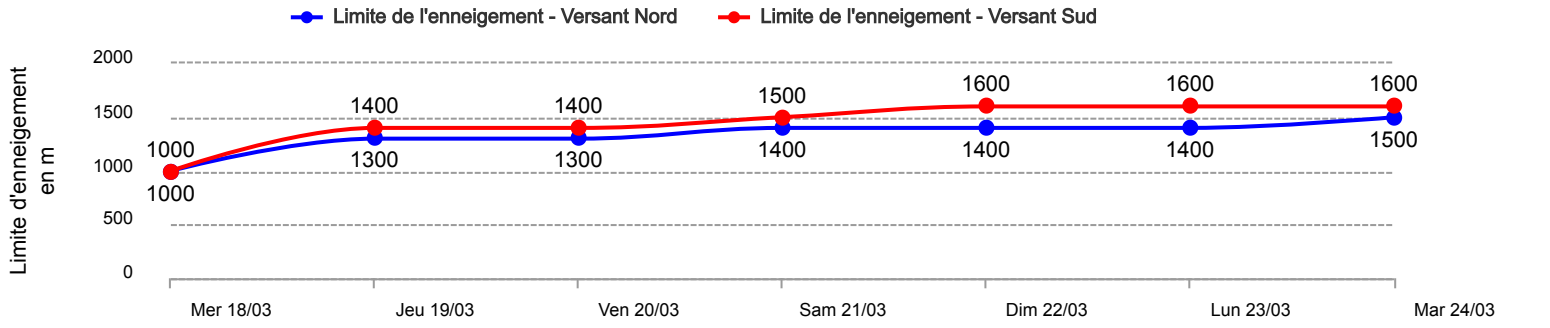


Pour consulter la vigilance en cours, veuillez vous rendre sur le site https://vigilance.meteofrance.fr/fr


Météo-France - 73 avenue de Paris, 94165 Saint-Mandé cedex - Contact : contact@meteo.fr


Bulletin neige & avalanches par téléphone au

0 892 68 10 20 Service 0,35 € / min + prix appel


Rédigé par Météo-France avec la contribution des observateurs du réseau nivo-météorologiques. Partenariat : ANMSM (Maires de Stations de Montagne), DSF (Domaines Skiables de France), ADSP (Directeurs de Pistes et de la Sécurité des Stations de Sports d'Hiver) et autres acteurs de la montagne.