RÉPUBLIQUE FRANÇAISE
Liberté Égalité Fraternité

METEO FRANCE
À VOS CÔTÉS, DANS UN CLIMAT QUI CHANGE

Bulletin d'estimation du risque d'avalanche

(valable en dehors des pistes balisées et ouvertes)

MASSIF : Grandes-Rousses

Rédigé le mardi 24 mars 2026 à 15h

Estimation des risques pour le : MERCREDI 25 MARS

LE MATIN FORMATION DE QUELQUES PLAQUES EN FACES NORD D'ALTITUDE ; L'APRES-MIDI CHUTES DE NEIGE ET VENT PLUS FORT : PLAQUES PLUS NOMBREUSES AU FIL DES HEURES...

3

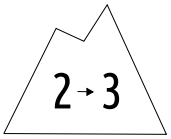

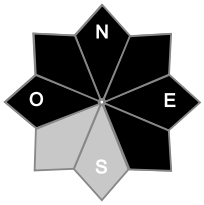

Altitude/ AP-MIDI

Indice de risque limité évoluant en marqué.

Départs spontanés : Le matin rares départs spontanés de plaques sous le vent d'Ouest (faces Nord d'altitude, de taille 1, voire 2 ?). L'après-midi et le soir des coulées sous les chutes de neige, rarement une avalanche en couloir très chargé ?

Déclenchements provoqués : Possibles parfois dès le matin, en faces Nord d'altitude. L'après-midi et le soir plaques plus nombreuses se formant sous le vent de Nord-Ouest (Peu de volume mais davantage de secteurs concernés)...

Indices de risque : 5 très fort - 4 fort - 3 marqué - 2 limité - 1 faible -- En noir : les pentes les plus dangereuses

Stabilité du manteau neigeux

Situation avalancheuse typique : neige ventée

En matinée risque localisé de plaques (bien instables) en faces Nord d'altitude, sous l'action du vent d'Ouest. Dégradation l'après-midi et le soir avec un peu de fraîche attendue, bien soufflée par Nord-Ouest...

Départs spontanés :

Risque accidentel évoluant au fil de la journée de mercredi.

Le matin, vent d'Ouest à haute altitude soufflant la neige poudreuse en place dans les faces Nord d'altitude (15 cm environ). Cette neige a peu de cohésion, plaque a priori très localisée mais bien instable/réactive avec larges cassures possibles au passage d'une personne.

En cours d''après-midi, neige attendue (10 puis 15 cm) et vent de Nord-Ouest très fort/turbulent. De nouvelles (petites) plaques se forment au fil des intempéries, dans pas mal de pentes, et parfois loin des crêtes. Risque accru en faces Nord où le fond est resté poudreux...

Déclenchements provoqués :

En matinée, rares ruptures de plaques en faces Nord à Nord-Est d'altitude, sous le vent d'Ouest (pentes bien raides, pieds de parois). Celles ci seraient de taille petites à moyenne (1, rarement 2)

L'après-midi et le soir au fil des intempéries, du vent : Nombreuses coulées de surface de neige fraîche, parfois une avalanche de taille moyenne (notamment en couloirs chargés ou faces Nord d'altitude ?).

Qualité de la neige

Qualification de l'enneigement : L'enneigement est bon pour la saison en versants ombragés au dessus de 1400/1600 m, voire abondant en combes d'altitude. Vers les crêtes et sommets il est en revanche plus médiocre. En Sud il est juste correct au dessus de 1700 m.

Limites skiables : Vers 1300/1700 m selon les versants.

Qualité de la neige mercredi : En pentes ensoleillées et sous 2000/2200m neige croutée ou durcie par regel nocturne.

En faces Nord d'altitude, neige poudreuse sans cohésion devenant localement soufflée/plaquée par vent d'Ouest en matinée.

En cours d'après-midi on attend du fort vent de Nord-Ouest et jusque 10 puis 15 cm de neige fraîche sur l'Ouest du massif vers Rissiou/Vaujany, formation de nouvelles congères/plaques jusque assez loin des crêtes...

Aperçu météo pour le mercredi 25 mars

	nuit	matin	après-midi	soir

Nuit calme/ regel. Mercredi matin assez beau, déjà venté vers les sommets. L'après-midi arrivée d'un front d'averses neigeuses, bourrasques/froid...

Pluie-Neige			1 100 m	600 m
Iso 0 °C	2 600 m	2 600 m	1 400 m	1 000 m
Vent 2000 m	↘ 10 km/h	↘ 20 km/h	↘ 50 km/h	↘ 60 km/h
Vent 3000 m	↗ 25 km/h	→ 45 km/h	↘ 70 km/h	↓ 80 km/h

Pour consulter la vigilance en cours, veuillez vous rendre sur le site https://vigilance.meteofrance.fr/fr

Météo-France - 73 avenue de Paris, 94165 Saint-Mandé cedex - Contact : contact@meteo.fr

Rédigé par Météo-France avec la contribution des observateurs du réseau nivo-météorologiques. Partenariat : ANMSM (Maires de Stations de Montagne), DSF (Domaines Skiables de France), ADSP (Directeurs de Pistes et de la Sécurité des Stations de Sports d'Hiver) et autres acteurs de la montagne.

Bulletin neige & avalanches par téléphone au

0 892 68 10 20 Service 0,35 € / min + prix appel

Bulletin d'estimation du risque d'avalanche

(valable en dehors des pistes balisées et ouvertes)

MASSIF : Grandes-Rousses

Rédigé le mardi 24 mars 2026 à 15h

Épaisseur de neige hors-piste

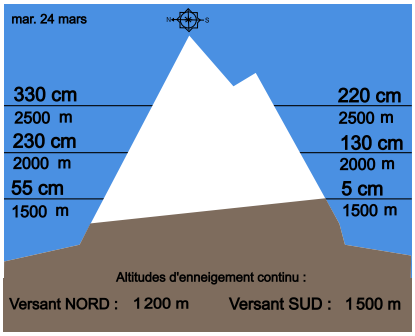

Précipitations à 1800 m

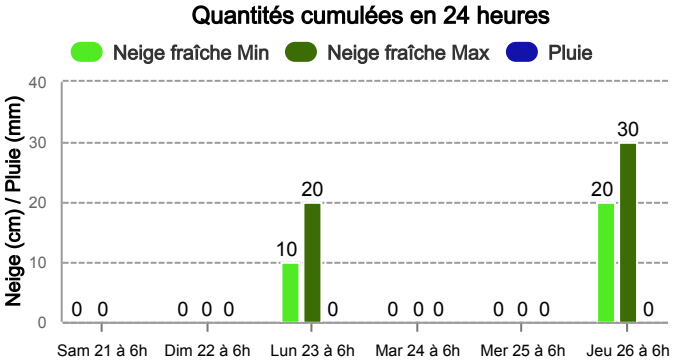

Tendance du jeudi 26 mars

Indice de risque marqué

Jeudi risque d'avalanche marqué sur les Grandes Rousses avec jusque 30 puis 40 cm de neige froide très soufflée. Des avalanches spontanées en couloirs/faces chargées par le vent de Nord-Nord-Ouest et un risque de plaques dès assez basse altitude.
En haute montagne alternance de plaques dures et zones décapées, risque plus localisé ?

Pour consulter la vigilance en cours, veuillez vous rendre sur le site https://vigilance.meteofrance.fr/fr

Météo-France - 73 avenue de Paris, 94165 Saint-Mandé cedex - Contact : contact@meteo.fr

Rédigé par Météo-France avec la contribution des observateurs du réseau nivo-météorologiques. Partenariat : ANMSM (Maires de Stations de Montagne), DSF (Domaines Skiables de France), ADSP (Directeurs de Pistes et de la Sécurité des Stations de Sports d'Hiver) et autres acteurs de la montagne.

Bulletin neige & avalanches par téléphone au

0 892 68 10 20 Service 0,35 € / min + prix appel

RÉPUBLIQUE FRANÇAISE
Liberté Égalité Fraternité

METEO FRANCE
À VOS CÔTÉS, DANS UN CLIMAT QUI CHANGE

Bulletin d'estimation du risque d'avalanche

(valable en dehors des pistes balisées et ouvertes)

MASSIF : Grandes-Rousses

Rédigé le mardi 24 mars 2026 à 15h

Conditions nivo-météo des 7 derniers jours

	mer. 18/03				jeu. 19/03				ven. 20/03				sam. 21/03				dim. 22/03				lun. 23/03				mar. 24/03			
	03h	09h	15h	21h	03h	09h	15h	21h	03h	09h	15h	21h	03h	09h	15h	21h	03h	09h	15h	21h	03h	09h	15h	21h	03h	09h	15h	21h
Météo																												
Vent (km/h)	30	30	45	55	60	35	20	15	20	15	10	10	15	20	15	20	15	15	15	10	10	30	25	30	25	15	10	10
à 3000m																												
Vent (km/h)	15	15	40	40	40	20	15	0	5	0	5	0	0	0	5	10	10	5	5	5	5	25	20	15	10	10	10	5
à 2000m																												

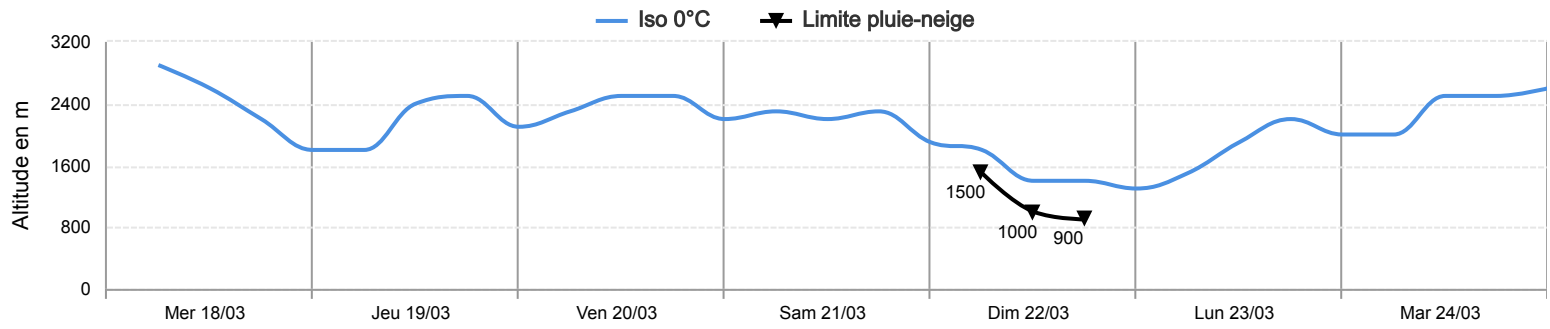

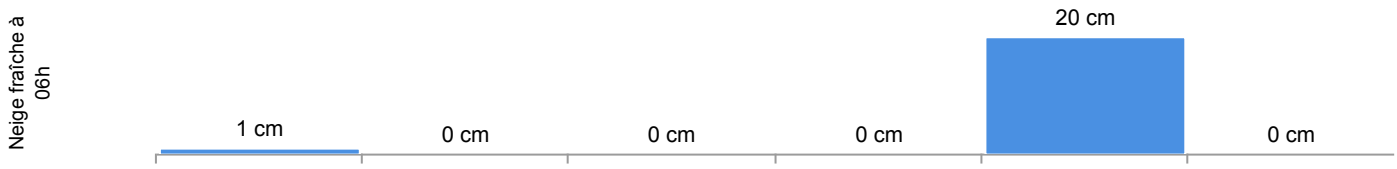

Risque d'avalanche	mer. 18/03	jeu. 19/03	ven. 20/03	sam. 21/03	dim. 22/03	lun. 23/03	mar. 24/03
	3	3	3	2	2	2	2

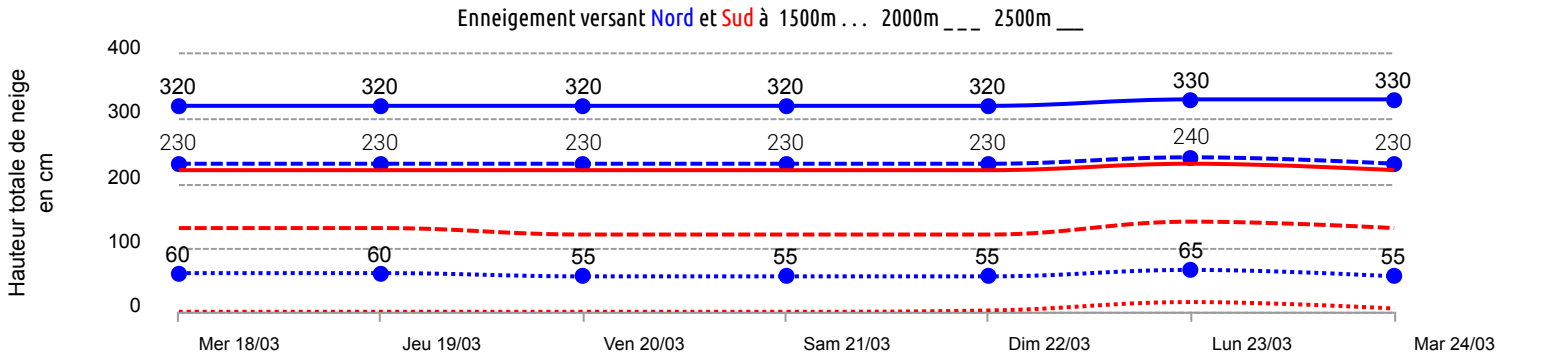

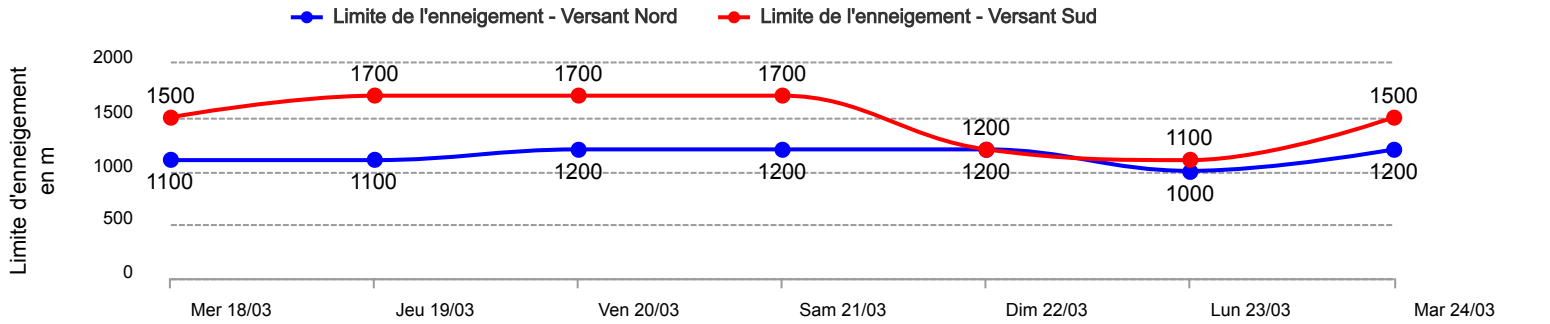

Pour consulter la vigilance en cours, veuillez vous rendre sur le site https://vigilance.meteofrance.fr/fr

Météo-France - 73 avenue de Paris, 94165 Saint-Mandé cedex - Contact : contact@meteo.fr

Rédigé par Météo-France avec la contribution des observateurs du réseau nivo-météorologiques. Partenariat : ANMSM (Maires de Stations de Montagne), DSF (Domaines Skiables de France), ADSP (Directeurs de Pistes et de la Sécurité des Stations de Sports d'Hiver) et autres acteurs de la montagne.

Bulletin neige & avalanches par téléphone au
0 892 68 10 20 Service 0,35 € / min + prix appel