RÉPUBLIQUE FRANÇAISE
Liberté Égalité Fraternité

METEO FRANCE
À VOS CÔTÉS, DANS UN CLIMAT QUI CHANGE

Bulletin d'estimation du risque d'avalanche
(valable en dehors des pistes balisées et ouvertes)

MASSIF : Aravis

Rédigé le mardi 24 mars 2026 à 16h

Estimation des risques pour le : MERCREDI 25 MARS

NOUVELLES INSTABILITÉS FORMÉES PAR LE VENT DANS LA NEIGE FRAICHE.

3

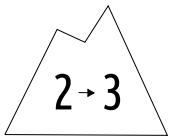

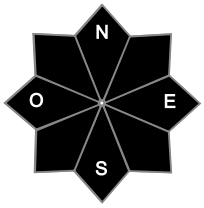

Sous le vent

Indice de risque limité évoluant en marqué.

Départs spontanés : Quelques départs pendant les chutes de neige.

Déclenchements provoqués : Nouvelles plaques à vent dans la neige fraiche en cours d'après-midi.

Indices de risque : 5 très fort - 4 fort - 3 marqué - 2 limité - 1 faible -- En noir : les pentes les plus dangereuses

Stabilité du manteau neigeux

Situation avalancheuse typique : neige ventée

Déclenchements provoqués :

* De nombreuses plaques à vent se forment en journée de mercredi. Dès la matinée, le vent de sud-ouest souffle mais ne vient créer que de petites instabilités, plutôt d'aspect dur. **En cours d'après-midi, des chutes de neige ventées** se mettent en place et ainsi, sous le vent d'W, de **nombreuses plaques à vent** sont en train de se créer, et deviennent un peu plus épaisses. Taille 1 à 2 (petites à moyennes). Ces plaques sont facilement déclenchables au passage d'un skieur et sont un peu plus nombreuses près des crêtes et des arêtes. Elles sont plutôt d'aspect friable. La crête des Aravis prend un peu plus de neige que Borne/Bargy/Tournette et ainsi, les plaques y sont potentiellement un peu plus épaisses.

Observables : accumulation de neige, vaguelettes, fissures sous les skis.

* Dans les **secteurs concernés par les averses**, une fine couche de neige roulée peut servir de couche fragile temporaire et ainsi favoriser la propagation d'une rupture. Localement une avalanche de taille 3 (grande) n'est pas exclue.

Départs spontanés :

* En matinée, rares avalanches de neige humide dans les versants sud à est sous le soleil matinal, en dessous de 2200 m. Taille 1.
* L'après-midi, rares avalanches de neige fraiche durant les chutes, en tous versants, au-dessus de 1800 m. Taille 1, rarement 2.

Qualité de la neige

Enneigement : Enneigement correct pour la saison. La neige est présente au plus bas dès 1100/1300 m.
En début d'après-midi de mercredi, la neige tombe et tient au sol dès 1000m mais vient seulement cacher le sol nu.

Qualité de la neige ce mercredi :

* En matinée sous 2100/2200m, la neige croutée se transforme et subit une évolution de printemps dans les orientations sud à est. Dans les autres orientations et altitudes, la neige est travaillée par le vent, et reste parfois encore légère (en nord au-dessus de 1800m notamment) et n'a pas vraiment le temps de se transformer avant les chutes de neige.
* En fin de matinée dès 1000m, les chutes de neige commencent et viennent se poser sur ce fond dur/transformé selon les orientations. On attend environ 15cm de neige fraîche, qui peuvent tomber de façon assez intense sous une averse. Ces chutes de neige sont ventées, et ainsi les croupes sont décapées rapidement et dans certains secteurs, le travail du vent se fait ressentir.

Aperçu météo pour le mercredi 25 mars

	nuit	matin	après-midi	soir

Temps perturbé à partir de la mi-journée. Vent fort et forte baisse des températures.

Pluie-Neige			1 100 m	500 m
Iso 0 °C	2 400 m	2 200 m	1 400 m	900 m
Vent 2000 m	↗ 30 km/h	↗ 40 km/h	↘ 50 km/h	↘ 40 km/h
Vent 2500 m	→ 40 km/h	↗ 60 km/h	→ 70 km/h	↓ 60 km/h

Épaisseur de neige hors-piste

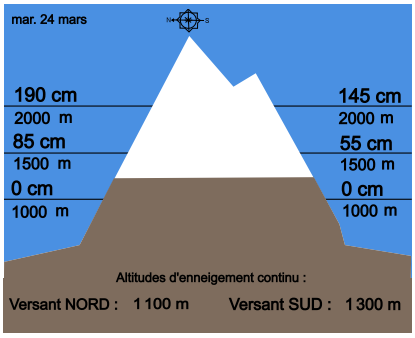

Précipitations à 1800 m

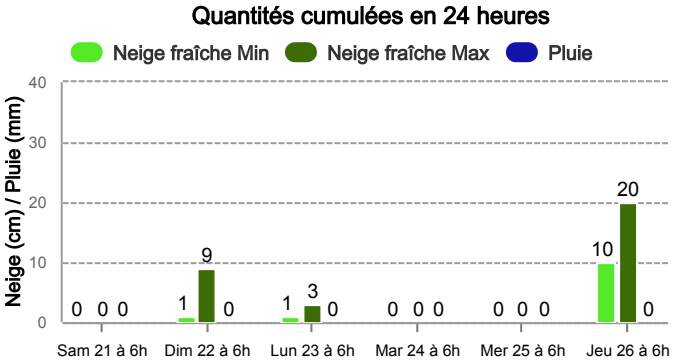

Tendance du jeudi 26 mars

3

Indice de risque marqué

Averses de neige et vent fort en altitude, formant de nouvelles instabilités dans la neige fraiche. Le risque se maintient toute la journée.

Pour consulter la vigilance en cours, veuillez vous rendre sur le site https://vigilance.meteofrance.fr/fr

Météo-France - 73 avenue de Paris, 94165 Saint-Mandé cedex - Contact : contact@meteo.fr

Rédigé par Météo-France avec la contribution des observateurs du réseau nivo-météorologiques. Partenariat : ANMSM (Maires de Stations de Montagne), DSF (Domaines Skiables de France), ADSP (Directeurs de Pistes et de la Sécurité des Stations de Sports d'Hiver) et autres acteurs de la montagne.

Bulletin neige & avalanches par téléphone au
0 892 68 10 20 Service 0,35 € / min + prix appel

RÉPUBLIQUE FRANÇAISE
Liberté Égalité Fraternité

METEO FRANCE
À VOS CÔTÉS, DANS UN CLIMAT QUI CHANGE

Bulletin d'estimation du risque d'avalanche

(valable en dehors des pistes balisées et ouvertes)

MASSIF : Aravis

Rédigé le mardi 24 mars 2026 à 16h

Conditions nivo-météo des 7 derniers jours

	mer. 18/03				jeu. 19/03				ven. 20/03				sam. 21/03				dim. 22/03				lun. 23/03				mar. 24/03			
	03h	09h	15h	21h	03h	09h	15h	21h	03h	09h	15h	21h	03h	09h	15h	21h	03h	09h	15h	21h	03h	09h	15h	21h	03h	09h	15h	21h
Météo																												
Vent (km/h)	45	20	60	50	25	30	25	30	30	20	10	10	10	15	15	15	30	35	40	15	20	30	25	20	10	15	10	10
à 2500m																												
Vent (km/h)	15	10	50	30	10	20	15	20	20	10	5	5	5	10	10	5	20	25	25	5	15	25	20	15	5	5	5	5
à 2000m																												

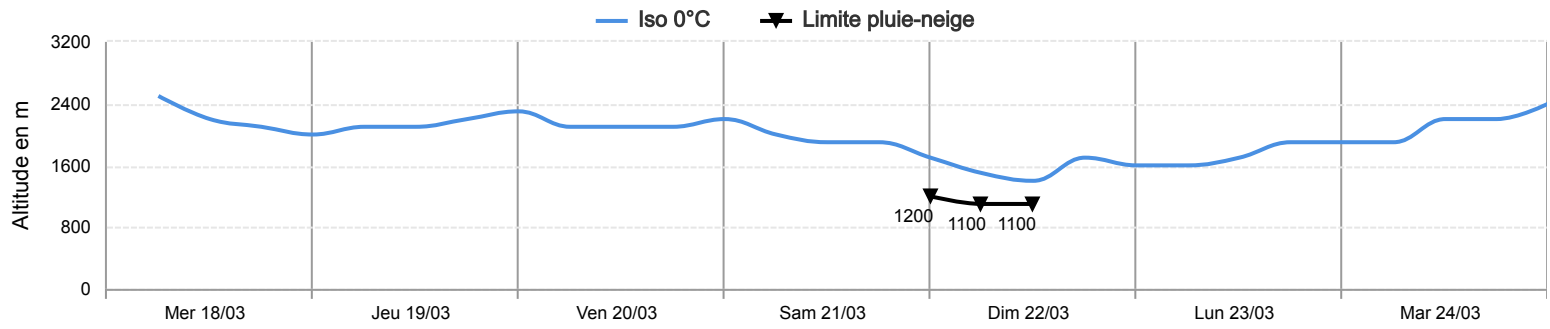

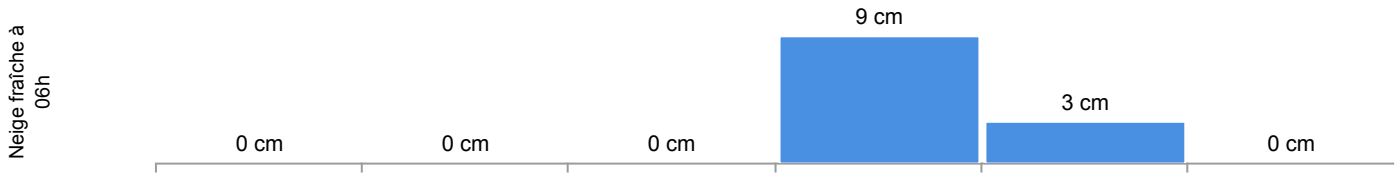

Risque d'avalanche	mer. 18/03	jeu. 19/03	ven. 20/03	sam. 21/03	dim. 22/03	lun. 23/03	mar. 24/03
	3	3	2	2	2	2	2

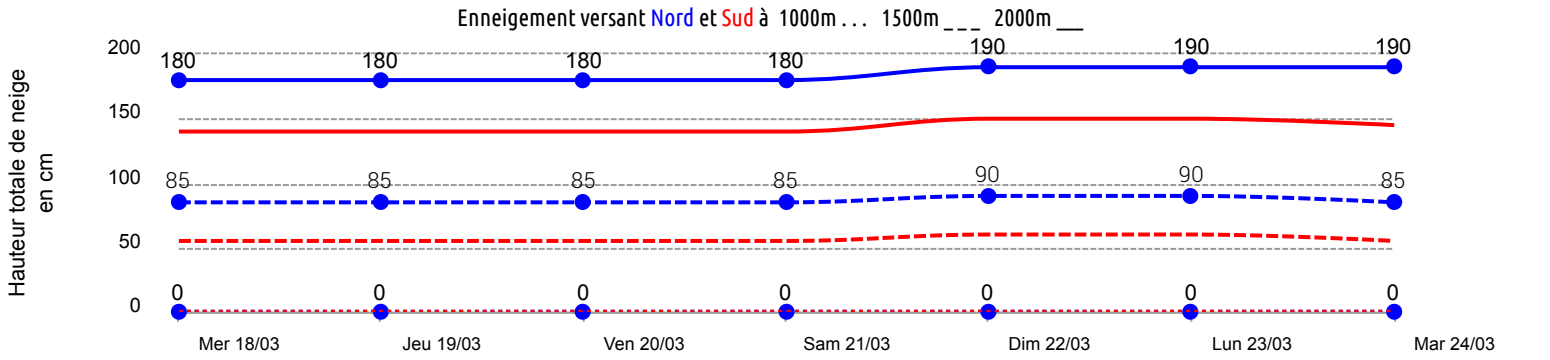

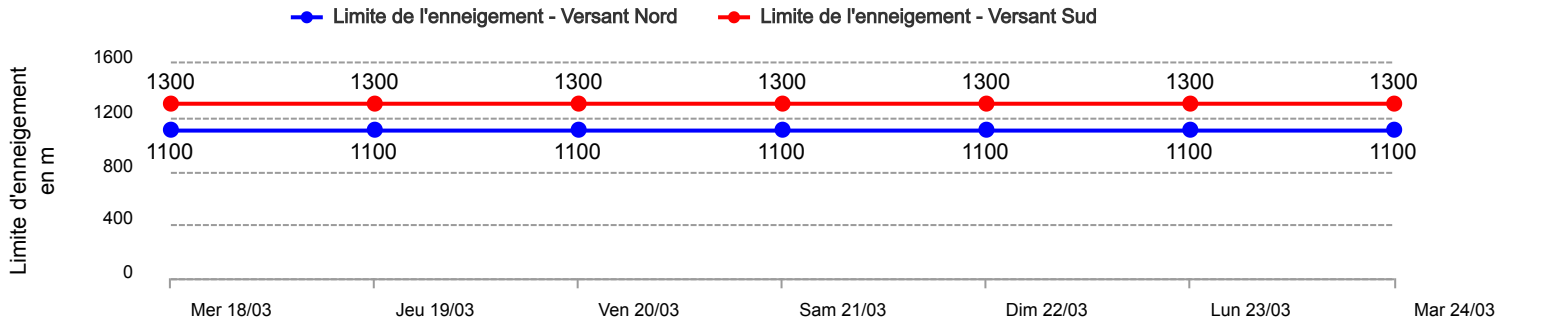

Pour consulter la vigilance en cours, veuillez vous rendre sur le site https://vigilance.meteofrance.fr/fr

Météo-France - 73 avenue de Paris, 94165 Saint-Mandé cedex - Contact : contact@meteo.fr

Rédigé par Météo-France avec la contribution des observateurs du réseau nivo-météorologiques. Partenariat : ANMSM (Maires de Stations de Montagne), DSF (Domaines Skiables de France), ADSP (Directeurs de Pistes et de la Sécurité des Stations de Sports d'Hiver) et autres acteurs de la montagne.

Bulletin neige & avalanches par téléphone au
0 892 68 10 20 Service 0,35 € / min + prix appel