Bulletin d'estimation du risque d'avalanche

(valable en dehors des pistes balisées et ouvertes)

MASSIF : Aspe Ossau

Rédigé le mardi 24 mars 2026 à 16h

Estimation des risques pour le : MERCREDI 25 MARS

RARES PLAQUES ENCORE DÉCLENCHABLES AU-DESSUS DE 2200 M, MANTEAU PRINTANIER AILLEURS.

2

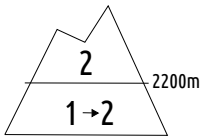

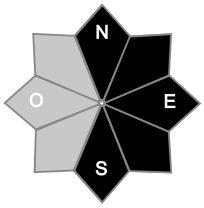

Plaques et soleil

Au-dessus de 2200m indice de risque limité, plus bas indice faible évoluant en limité.

Départs spontanés : En neige humide, avalanches de fond possibles.

Déclenchements provoqués : De rares plaques encore parfois sensibles au-dessus de 2200 m en Nord à Nord-Est

Indices de risque : 5 très fort - 4 fort - 3 marqué - 2 limité - 1 faible -- En noir : les pentes les plus dangereuses

Stabilité du manteau neigeux

Situation avalancheuse typique : neige humide couche fragile persistante

Déclenchements provoqués :

- Au-dessus de 2200 m, dans les pentes raides plein nord, dans un secteur un peu plus large au-dessus de 2500 m, des plaques à vent et des couches fragiles sont présentes dans les 30 à 60 premiers centimètres. Elles sont le plus souvent devenues difficilement déclenchables, recouvertes par une croûte, détruites par les nuits claires ou en partie humidifiées. Rarement, certaines peuvent encore être plus facilement sollicitées au passage d'un skieur, là où la croûte est cassante et où les plaques sont plus épaisses (en zones d'accumulations), l'épaisseur ralentissant la métamorphose des plaques.
- Ailleurs, en versants ensoleillés, le passage d'un skieur dans une pente raide en neige très humide peut favoriser un petit départ ponctuel.

Départs spontanés :

Peu ou pas d'activité en tout début de journée grâce à un regel efficace, puis des départs ponctuels dans la neige humide sont attendus dans les pentes raides au fil de l'ensoleillement (d'abord en est, puis sud), devenant plus fréquents au fil de la journée. Les avalanches sont généralement petites à moyennes, quelques avalanches de fond sont possibles, parfois annoncées par l'ouverture de fissures, avalanches atteignant (rarement) une grande taille surtout dans les expositions Sud-Est où des accumulations sont présentes.

L'activité devrait diminuer l'après-midi avec l'arrivée d'une masse d'air fraîche et nuageuse. Ainsi, les versants ouest devraient être peu concernés par l'humidification mercredi.

Autres : Ponts de neige et corniches encore en place, devenant fragiles au fil de l'humidification, fissures même en nord.

Qualité de la neige

Enneigement : Correct pour la saison au-dessus de 1800 à 2000 m, mais reste assez maigre en versants exposés aux vents d'ouest passés. Manteau skiable à partir de 1600 m en nord, plutôt 1900/2000 m en sud.

État de la neige : Neige croûtée en versants nord, cassante au-dessus de 2000 m, n'évoluant que peu en journée. Ailleurs, elle est regelée et portante au petit jour. Neige rapidement dégelée en surface au soleil, mais s'humidifie lentement en profondeur au-dessus de 2000/2200 m. Quelques centimètres en fin de journée ne changeant pas fondamentalement la qualité de la neige de surface.

Aperçu météo pour le mercredi 25 mars

	nuit	matin	après-midi	soir

Belle matinée, arrivée de nuages à la mi-journée, bouchant le relief et réduisant la visibilité. Faibles chutes de neige, principalement en soirée

Pluie-Neige			1 600 m	1 200 m
Iso 0 °C	3 100 m	2 900 m	1 800 m	1 400 m
Vent 1500 m	↗ 10 km/h	↓ 20 km/h	↓ 35 km/h	↓ 40 km/h
Vent 3000 m	↑ 10 km/h	↓ 20 km/h	↓ 45 km/h	↻ 60 km/h

Épaisseur de neige hors-piste

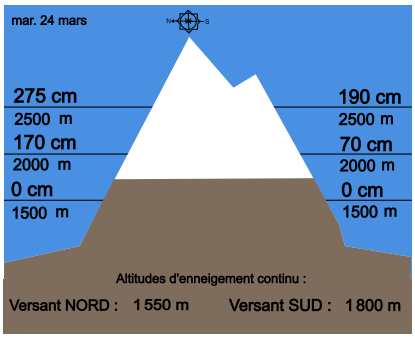

Précipitations à 1800 m

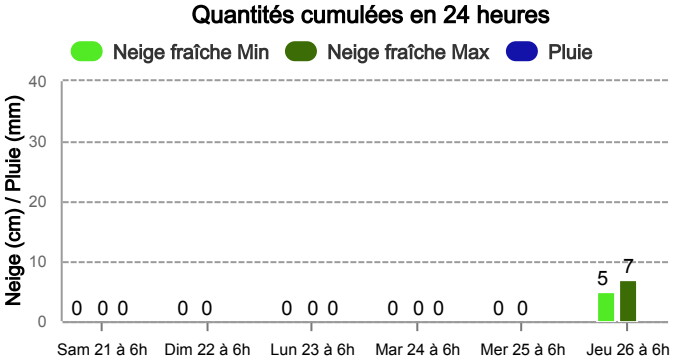

Tendance du jeudi 26 mars

2

Indice de risque limité

Fines plaques en neige récente, peu ou pas d'activité en neige humide

Pour consulter la vigilance en cours, veuillez vous rendre sur le site https://vigilance.meteofrance.fr/fr

Météo-France - 73 avenue de Paris, 94165 Saint-Mandé cedex - Contact : contact@meteo.fr

Rédigé par Météo-France avec la contribution des observateurs du réseau nivo-météorologiques. Partenariat : ANMSM (Maires de Stations de Montagne), DSF (Domaines Skiables de France), ADSP (Directeurs de Pistes et de la Sécurité des Stations de Sports d'Hiver) et autres acteurs de la montagne.

Bulletin neige & avalanches par téléphone au

0 892 68 10 20 Service 0,35 € / min + prix appel

RÉPUBLIQUE FRANÇAISE
Liberté Égalité Fraternité

METEO FRANCE
À VOS CÔTÉS, DANS UN CLIMAT QUI CHANGE

Bulletin d'estimation du risque d'avalanche

(valable en dehors des pistes balisées et ouvertes)

MASSIF : Aspe Ossau

Rédigé le mardi 24 mars 2026 à 16h

Conditions nivo-météo des 7 derniers jours

	mer. 18/03				jeu. 19/03				ven. 20/03				sam. 21/03				dim. 22/03				lun. 23/03				mar. 24/03			
	03h	09h	15h	21h	03h	09h	15h	21h	03h	09h	15h	21h	03h	09h	15h	21h	03h	09h	15h	21h	03h	09h	15h	21h	03h	09h	15h	21h
Météo																												
Vent (km/h)	15	10	15	20	25	30	30	15	15	15	20	15	15	10	10	15	5	10	25	35	35	25	20	15	10	10	15	20
à 3000m																												
Vent (km/h)	10	2	5	10	15	25	20	10	10	10	15	10	10	5	5	5	5	5	20	25	20	15	15	10	5	5	10	10
à 1500m																												

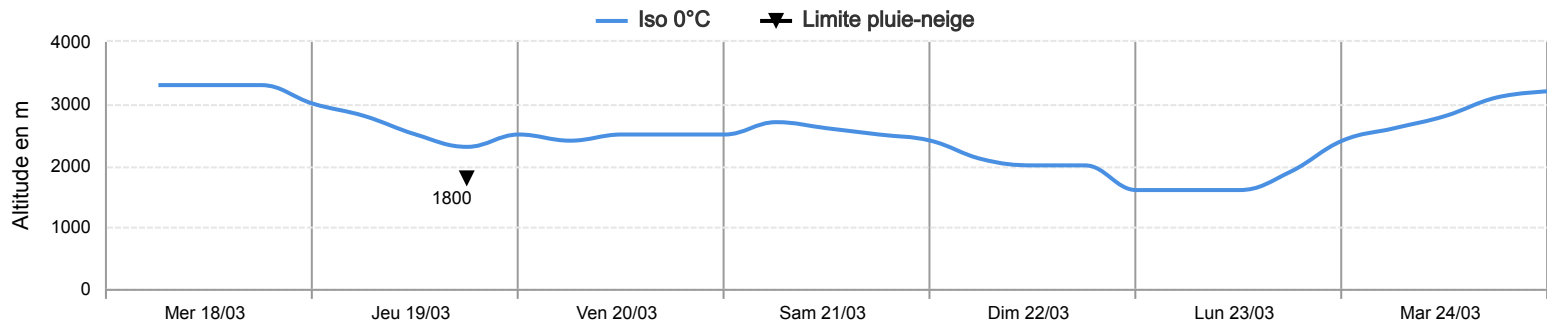

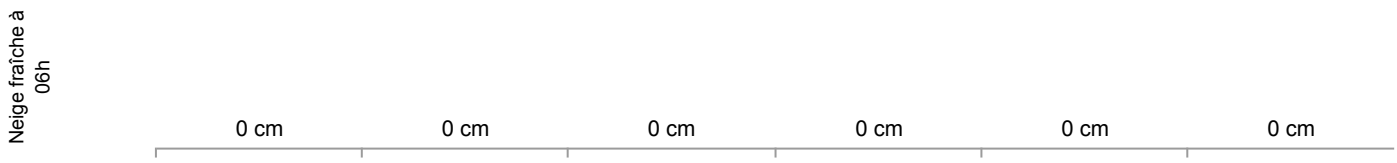

Risque d'avalanche	mer. 18/03	jeu. 19/03	ven. 20/03	sam. 21/03	dim. 22/03	lun. 23/03	mar. 24/03
	3	2	2	2	2	2	2

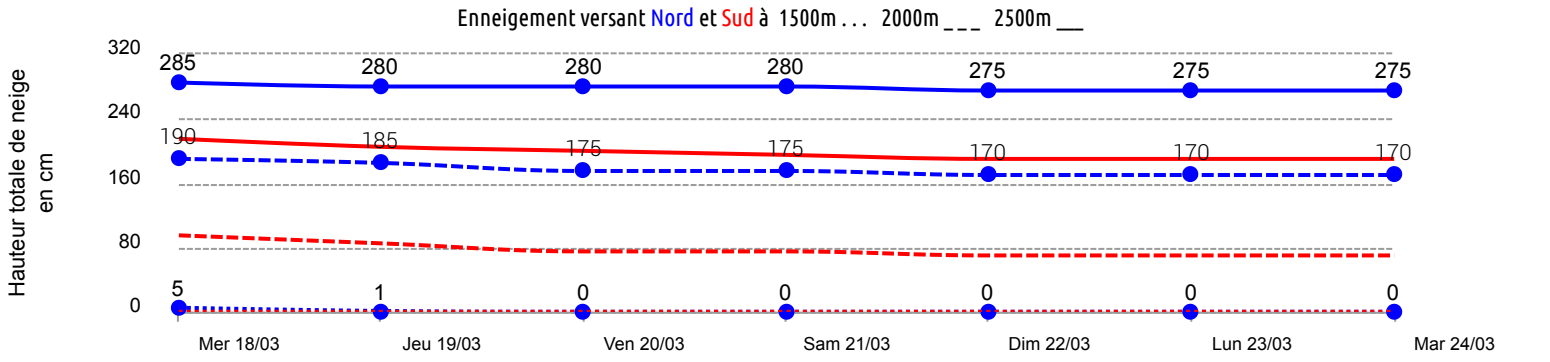

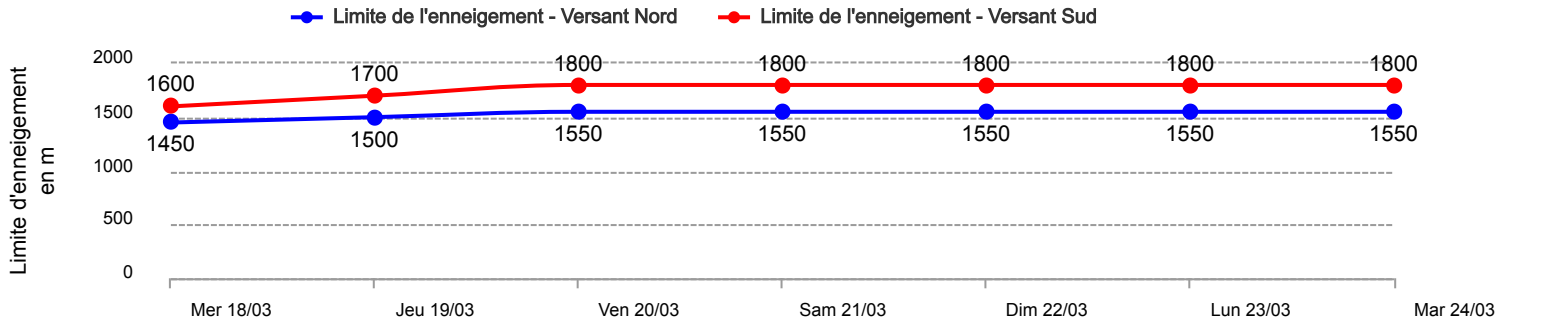

Pour consulter la vigilance en cours, veuillez vous rendre sur le site https://vigilance.meteofrance.fr/fr

Météo-France - 73 avenue de Paris, 94165 Saint-Mandé cedex - Contact : contact@meteo.fr

Rédigé par Météo-France avec la contribution des observateurs du réseau nivo-météorologiques. Partenariat : ANMSM (Maires de Stations de Montagne), DSF (Domaines Skiables de France), ADSP (Directeurs de Pistes et de la Sécurité des Stations de Sports d'Hiver) et autres acteurs de la montagne.

Bulletin neige & avalanches par téléphone au
0 892 68 10 20 Service 0,35 € / min + prix appel