Bulletin d'estimation du risque d'avalanche
(valable en dehors des pistes balisées et ouvertes)

MASSIF : Beaufortain

Rédigé le mardi 24 mars 2026 à 16h

Estimation des risques pour le : MERCREDI 25 MARS

VENT ET CHUTES DE NEIGE : NOUVELLES INSTABILITÉS, DE PLUS EN PLUS NOMBREUSES ET RÉACTIVES.

3

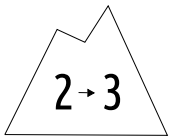

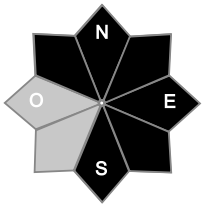

Indice de risque limité évoluant en marqué.

Départs spontanés : sous le vent.

Déclenchements provoqués : instabilités de plus en plus généralisées.

Indices de risque : 5 très fort - 4 fort - 3 marqué - 2 limité - 1 faible -- En noir : les pentes les plus dangereuses

Stabilité du manteau neigeux

Situation avalancheuse typique : neige ventée neige fraîche

Déclenchements provoqués :
Le matin, **quelques plaques** sont alimentées par le vent d'Ouest, essentiellement en ubacs (où la neige était restée poudreuse et transportable). Taille 1 à 2 (petite à moyenne) avec des cassures de 15 à 30 cm.
L'après-midi, avec les chutes de neige et le renforcement du vent de Nord-Ouest, les **plaques deviennent plus nombreuses, plus épaisses et plus réactives** au fil des heures, le **risque devient marqué en fin d'après-midi**. On les trouve jusqu'en bas des versants sous le vent, souvent derrière les ruptures de pente. Taille 1 à 2 (petite à moyenne) avec des cassures de 15 à 30 cm, localement 60 cm en ubac.
Observables : accumulation, test de stabilité, fissures devant les skis.

Départs spontanés :
Le matin sous le vent d'ouest, rares départs de petites plaques en secteur NO, Nord et NE d'altitude. **Avec les chutes de neige ventées l'après midi, quelques départs**, parfois linéaires de petites à moyennes avalanches sous les crêtes et rupture de pentes.

Qualité de la neige

Enneigement : Encore un peu au dessus de la moyenne, sauf aux plus basses altitudes où les hauteurs de neige sont tout juste correctes pour la saison.

Limite skiable : 1100 m au mieux en Nord. Plutôt 1400/1500 m en sud pas trop raide.

Qualité de la neige : Le matin, en adrets, neige dure ou croutée, qui peine à ramollir en journée là où le vent souffle; en ubacs, on peut encore trouver de la poudreuse (10 à 20 cm), parfois densifiée par le vent. Chute de neige l'après-midi : couche de fraîche s'épaississant, nombreuses accumulations par le vent.

Aperçu météo pour le mercredi 25 mars

	nuit	matin	après-midi	soir

Beau le matin, se dégradant très rapidement en début d'après-midi. Vent se renforçant. Fortes chute de neige.

Pluie-Neige			900 m	300 m
Iso 0 °C	2 500 m	2 000 m	1 100 m	500 m
Vent 2000 m	↑ 40 km/h	↗ 50 km/h	↘ 55 km/h	↘ 55 km/h
Vent 3000 m	→ 55 km/h	→ 60 km/h	↘ 65 km/h	↘ 60 km/h

Épaisseur de neige hors-piste

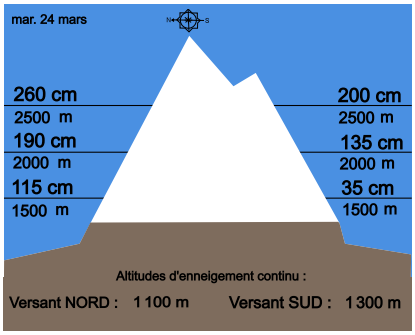

Précipitations à 1800 m

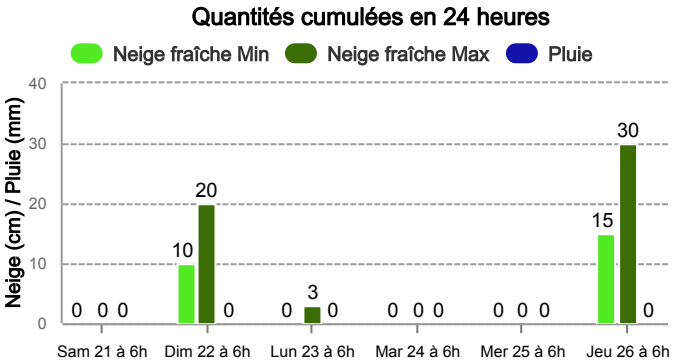

Tendance du jeudi 26 mars

3

Indice de risque marqué

Poursuite des chutes de neige et du vent : risque en hausse.

Pour consulter la vigilance en cours, veuillez vous rendre sur le site https://vigilance.meteofrance.fr/fr

Météo-France - 73 avenue de Paris, 94165 Saint-Mandé cedex - Contact : contact@meteo.fr

Rédigé par Météo-France avec la contribution des observateurs du réseau nivo-météorologiques. Partenariat : ANMSM (Maires de Stations de Montagne), DSF (Domaines Skiables de France), ADSP (Directeurs de Pistes et de la Sécurité des Stations de Sports d'Hiver) et autres acteurs de la montagne.

Bulletin neige & avalanches par téléphone au 0 892 68 10 20 Service 0,35 € / min + prix appel

RÉPUBLIQUE FRANÇAISE
Liberté Égalité Fraternité

METEO FRANCE
À VOS CÔTÉS, DANS UN CLIMAT QUI CHANGE

Bulletin d'estimation du risque d'avalanche

(valable en dehors des pistes balisées et ouvertes)

MASSIF : Beaufortain

Rédigé le mardi 24 mars 2026 à 16h

Conditions nivo-météo des 7 derniers jours

	mer. 18/03				jeu. 19/03				ven. 20/03				sam. 21/03				dim. 22/03				lun. 23/03				mar. 24/03			
	03h	09h	15h	21h	03h	09h	15h	21h	03h	09h	15h	21h	03h	09h	15h	21h	03h	09h	15h	21h	03h	09h	15h	21h	03h	09h	15h	21h
Météo																												
Vent (km/h)	20	35	60	50	35	20	20	20	25	25	15	10	15	25	20	15	15	25	20	10	20	25	20	20	20	25	35	50
à 3000m																												
Vent (km/h)	10	20	40	35	20	10	10	10	5	5	0	0	5	10	20	10	10	30	25	15	10	10	20	10	5	5	15	30
à 2000m																												

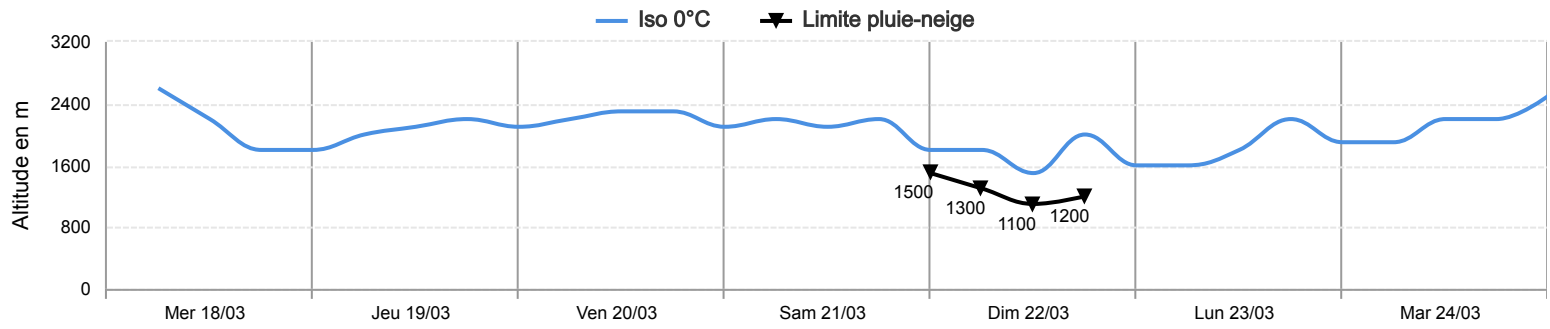

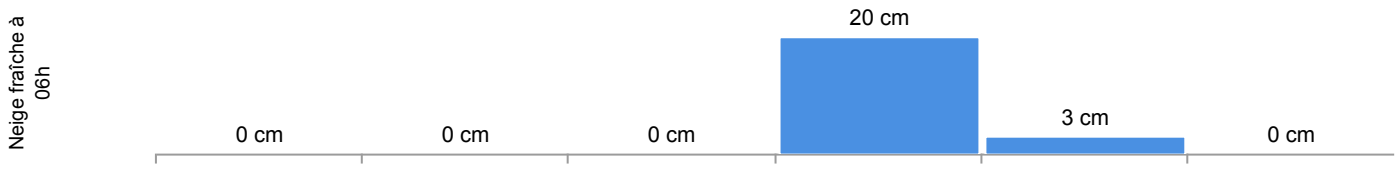

Risque d'avalanche	mer. 18/03	jeu. 19/03	ven. 20/03	sam. 21/03	dim. 22/03	lun. 23/03	mar. 24/03
	3	3	2	2	2	2	2

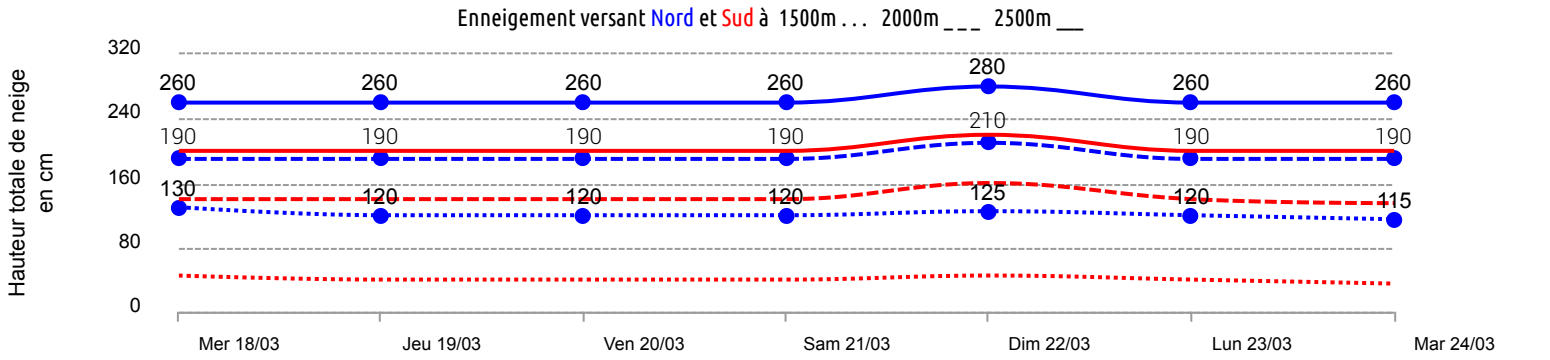

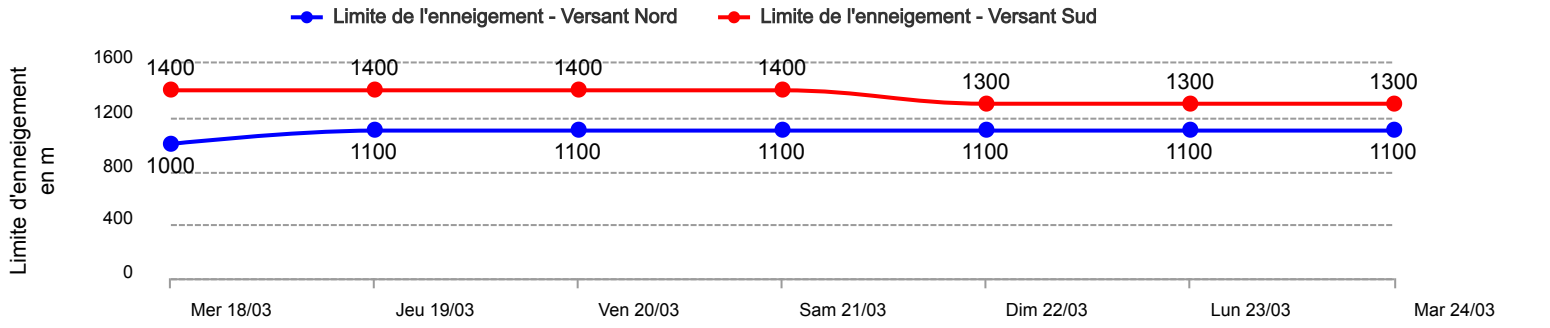

Pour consulter la vigilance en cours, veuillez vous rendre sur le site https://vigilance.meteofrance.fr/fr

Météo-France - 73 avenue de Paris, 94165 Saint-Mandé cedex - Contact : contact@meteo.fr

Rédigé par Météo-France avec la contribution des observateurs du réseau nivo-météorologiques. Partenariat : ANMSM (Maires de Stations de Montagne), DSF (Domaines Skiables de France), ADSP (Directeurs de Pistes et de la Sécurité des Stations de Sports d'Hiver) et autres acteurs de la montagne.

Bulletin neige & avalanches par téléphone au
0 892 68 10 20 Service 0,35 € / min + prix appel