RÉPUBLIQUE FRANÇAISE
Liberté Égalité Fraternité

METEO FRANCE
À VOS CÔTÉS, DANS UN CLIMAT QUI CHANGE

Bulletin d'estimation du risque d'avalanche
(valable en dehors des pistes balisées et ouvertes)
MASSIF : Capcir Puymorens

Rédigé le mardi 24 mars 2026 à 16h

Estimation des risques pour le : MERCREDI 25 MARS

PLAQUES EN HAUTE MONTAGNE, MANTEAU PRINTANIER AILLEURS

2

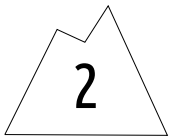

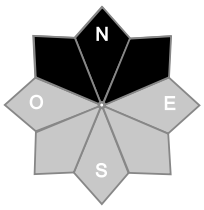

plaques à vent

Indices de risque : 5 très fort - 4 fort - 3 marqué - 2 limité - 1 faible -- En noir : les pentes les plus dangereuses

Indice de risque limité.

Départs spontanés : Avalanches de fond ou de neige humide avec la hausse du mercure, surtout après la mi journée.

Déclenchements provoqués : Plaques à vent anciennes, surtout au dessus de 2400/2500 m.

Stabilité du manteau neigeux

Situation avalancheuse typique : couche fragile persistante neige humide

Déclenchements provoqués :
- Quelques structures de plaques remontant à plus d'une semaine sont possiblement présentes au-delà de 2400/2500 m, reposant sur des couches fragiles persistantes (givres de surface ou neige roulée).
Elles sont localisées dans les pentes sommitales du massif et peuvent être masquées par les chutes de neige de la nuit de dimanche à lundi. Avalanches de taille 1 à 2 attendues.
- Les quelques structures de plaques qui ont pu se former durant le bref épisode perturbé de dimanche soir dans un large secteur nord sont en voie de stabilisation et deviennnent plus difficilement déclenchables.
Observables : neige récente travaillée par le vent, enfoncement des bâtons supérieur à 20/30 cm, fissures devant les skis.
-- Ailleurs, en versants ensoleillés, le passage d'un skieur dans une pente raide en neige très humide peut favoriser un petit départ ponctuel.

Départs spontanés :
- Peu ou pas d'activité en tout début de journée grâce à un regel efficace, puis des départs ponctuels dans la neige humide sont attendus dans les pentes raides au fil de l'ensoleillement (d'abord en est, puis sud, puis ouest), devenant plus fréquents au fil de la journée. Les avalanches sont généralement petites à moyennes (taille 1 à 2).
- Quelques avalanches de fond sont possibles, préférentiellement après la mi-journée, parfois annoncées par l'ouverture de fissures. Ces avalanches sont petites à moyennes, très rarement grandes (taille 3) dans les expositions Sud-Est où des accumulations sont présentes.

Autres :
Ponts de neige et corniches encore en place, devenant plus fragiles au fil de l'humidification.
Fissures présentes localement.

Qualité de la neige

Enneigement :
L'enneigement est excellent pour la saison, après plusieurs hivers déficitaires.
En altitude, les cumuls sont très conséquents mais les crêtes et sommets exposés au vent d'Ouest à Nord-ouest sont parfois complètement déneigés.
On peut encore chausser les skis dans les secteurs ombragés vers 1500/1600 m.

Qualité de la neige :
Les 15-20 centimètres de neige récente tombés dans la nuit de dimanche à lundi devraient encore être présents dans les pentes ombragées d'altitude.
Partout ailleurs, après un bon et fort regel matinal, reprise de l'humidification en surface et neige ramollie plus ou moins en profondeur suivant l'altitude et les expositions.

Aperçu météo pour le mercredi 25 mars

	nuit	matin	après-midi	soir
Dernière belle journée avant le retour d'un temps hivernal				
Pluie-Neige				
Iso 0 °C	3 000 m	3 200 m	1 800 m	1 200 m
Vent 2000 m	→ 15 km/h	↘ 35 km/h	↘ 50 km/h	↘ 70 km/h
Vent 3000 m	↘ 20 km/h	↘ 50 km/h	↘ 55 km/h	↘ 80 km/h

Pour consulter la vigilance en cours, veuillez vous rendre sur le site https://vigilance.meteofrance.fr/fr

Météo-France - 73 avenue de Paris, 94165 Saint-Mandé cedex - Contact : contact@meteo.fr

Rédigé par Météo-France avec la contribution des observateurs du réseau nivo-météorologiques. Partenariat : ANMSM (Maires de Stations de Montagne), DSF (Domaines Skiables de France), ADSP (Directeurs de Pistes et de la Sécurité des Stations de Sports d'Hiver) et autres acteurs de la montagne.

Bulletin neige & avalanches par téléphone au
0 892 68 10 20 Service 0,35 € / min + prix appel

Bulletin d'estimation du risque d'avalanche

(valable en dehors des pistes balisées et ouvertes)

MASSIF : Capcir Puymorens

Rédigé le mardi 24 mars 2026 à 16h

Épaisseur de neige hors-piste

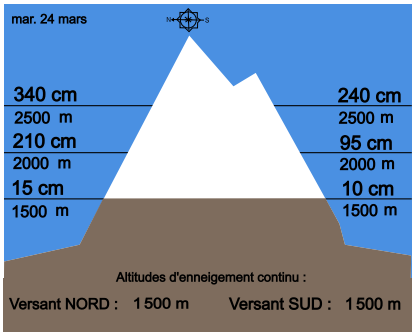

Précipitations à 1800 m

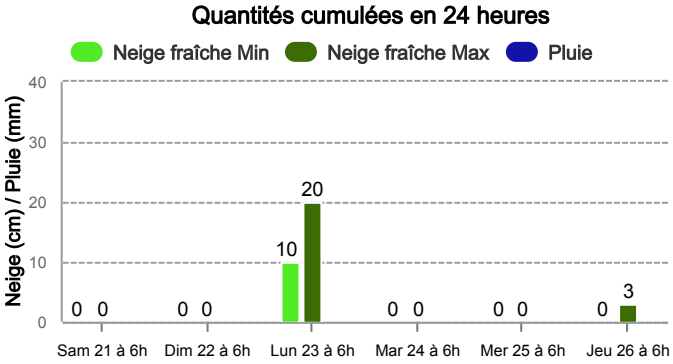

Tendance du jeudi 26 mars

Indice de risque limité

Risque en hausse avec de nouvelles chutes de neige ventée. Diminution du risque en neige humide avec le fort refroidissement.

Pour consulter la vigilance en cours, veuillez vous rendre sur le site https://vigilance.meteofrance.fr/fr

Météo-France - 73 avenue de Paris, 94165 Saint-Mandé cedex - Contact : contact@meteo.fr

Rédigé par Météo-France avec la contribution des observateurs du réseau nivo-météorologiques. Partenariat : ANMSM (Maires de Stations de Montagne), DSF (Domaines Skiables de France), ADSP (Directeurs de Pistes et de la Sécurité des Stations de Sports d'Hiver) et autres acteurs de la montagne.

Bulletin neige & avalanches par téléphone au

0 892 68 10 20 Service 0,35 € / min + prix appel

RÉPUBLIQUE FRANÇAISE
Liberté Égalité Fraternité

METEO FRANCE
À VOS CÔTÉS, DANS UN CLIMAT QUI CHANGE

Bulletin d'estimation du risque d'avalanche

(valable en dehors des pistes balisées et ouvertes)

MASSIF : Capcir Puymorens

Rédigé le mardi 24 mars 2026 à 16h

Conditions nivo-météo des 7 derniers jours

	mer. 18/03				jeu. 19/03				ven. 20/03				sam. 21/03				dim. 22/03				lun. 23/03				mar. 24/03			
	03h	09h	15h	21h	03h	09h	15h	21h	03h	09h	15h	21h	03h	09h	15h	21h	03h	09h	15h	21h	03h	09h	15h	21h	03h	09h	15h	21h
Météo																												
Vent (km/h)	15	10	15	20	30	25	30	25	30	25	20	20	10	10	20	15	25	25	35	50	50	40	35	25	20	20	20	20
à 3000m																												
Vent (km/h)	5	5	5	10	15	15	20	15	15	10	10	5	5	5	15	10	15	20	35	35	35	35	30	20	15	10	10	10
à 2000m																												

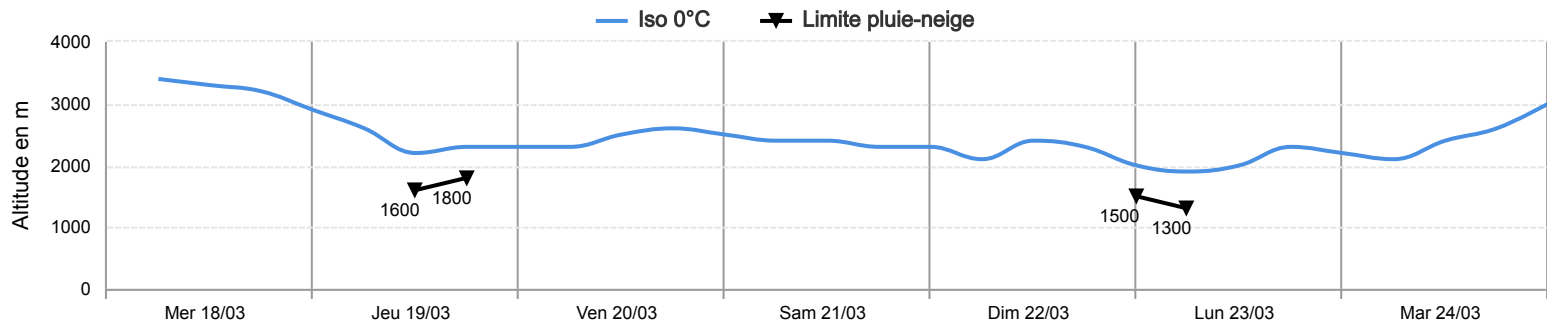

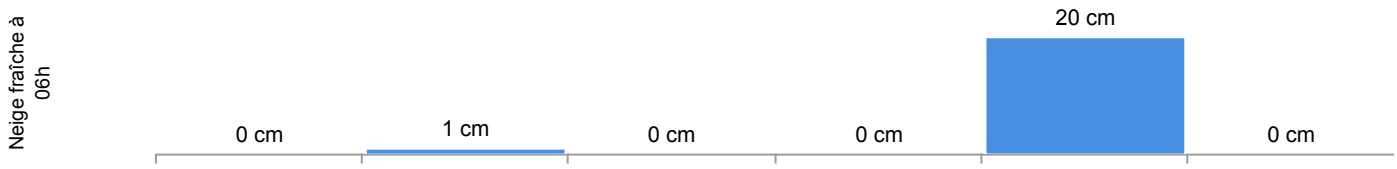

Risque d'avalanche	mer. 18/03	jeu. 19/03	ven. 20/03	sam. 21/03	dim. 22/03	lun. 23/03	mar. 24/03
	3	2	2	2	2	3	3

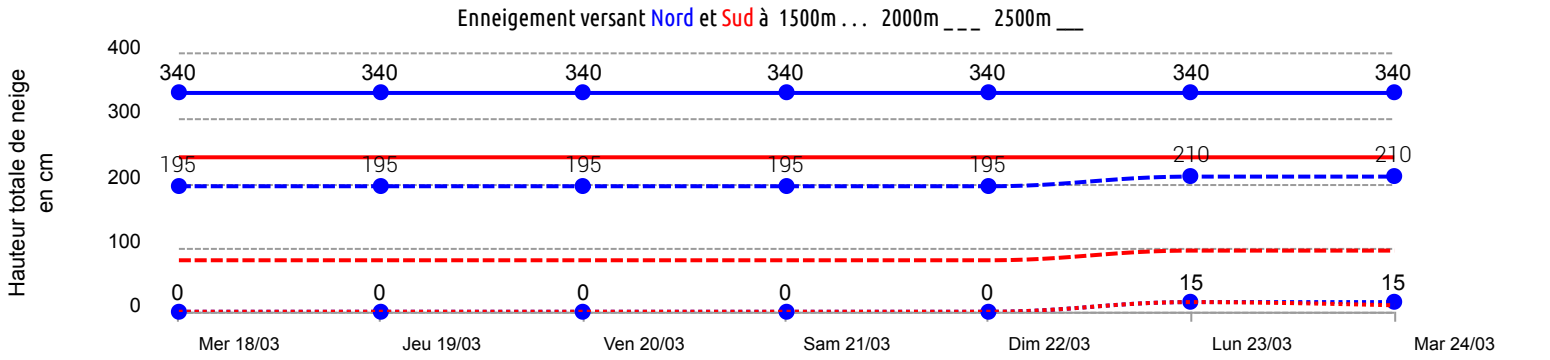

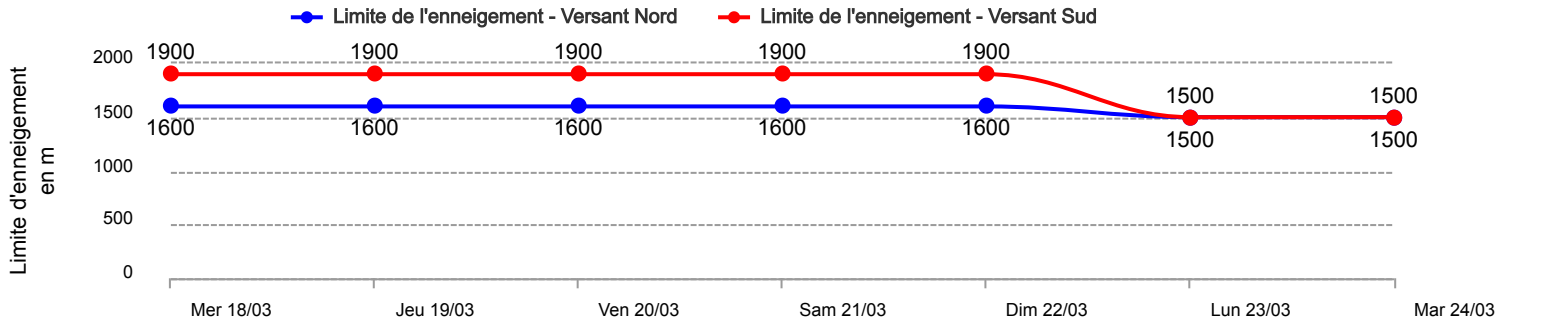

Pour consulter la vigilance en cours, veuillez vous rendre sur le site https://vigilance.meteofrance.fr/fr

Météo-France - 73 avenue de Paris, 94165 Saint-Mandé cedex - Contact : contact@meteo.fr

Rédigé par Météo-France avec la contribution des observateurs du réseau nivo-météorologiques. Partenariat : ANMSM (Maires de Stations de Montagne), DSF (Domaines Skiables de France), ADSP (Directeurs de Pistes et de la Sécurité des Stations de Sports d'Hiver) et autres acteurs de la montagne.

Bulletin neige & avalanches par téléphone au

0 892 68 10 20 Service 0,35 € / min + prix appel