Bulletin d'estimation du risque d'avalanche

(valable en dehors des pistes balisées et ouvertes)

MASSIF : Champsaur

Rédigé le mardi 24 mars 2026 à 16h

Estimation des risques pour le : MERCREDI 25 MARS

EN ALTITUDE, INSTABILITÉS RÉSIDUELLES DANS LA NEIGE RÉCENTE, D'AUTRES EN FORMATION AVEC LE VENT. UN PEU D'ACTIVITÉ NATURELLE AU SOLEIL.

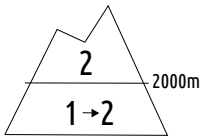

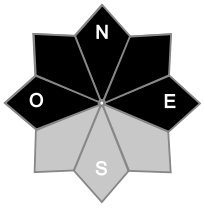

Au-dessus de 2000m indice de risque limité, plus bas indice faible évoluant en limité.

Départs spontanés : éventuels départs ponctuels en neige humide au soleil

Déclenchements provoqués : rares plaques, d'autres en formation, en altitude, faciles à déclencher

Indices de risque : 5 très fort - 4 fort - 3 marqué - 2 limité - 1 faible -- En noir : les pentes les plus dangereuses

Stabilité du manteau neigeux

Situation avalancheuse typique : neige ventée neige humide

Déclenchements provoqués : - rares plaques à vent dans la neige récente, encore déclenchables par un skieur. Principalement présentes dans les orientations de large nord au-dessus de 2000/2200 m, plutôt aux abords des ruptures de pente et des crêtes. Avalanches de taille petite à moyenne.
- Mercredi, quelques nouvelles plaques en formation avec le transport de la neige sèche par le vent, en haute altitude le matin, plus bas l'après-midi. Nouvelles instabilités, même loin des crêtes et sommets, faciles à déclencher et de taille limitée.
- Par ailleurs, un skieur évoluant tardivement en pente raide ensoleillée peut provoquer un départ ponctuel en neige humide, ou un départ linéaire alors qu'il évolue dans de la neige humidifiée en surface.

Départs spontanés : éventuels départs ponctuels en neige humide, rarement linéaire. Peu probables en début de journée, puis devenant possibles dès la fin de matinée en pentes raides ensoleillées. Avalanches de petite taille à moyenne.

Qualité de la neige

L'enneigement est proche des normales ou excédentaire pour une fin mars.
Hauteurs de neige observées : 21 cm au hameau des Portes dans le Valgaudemar à 1270 m, 133 cm à la Nivôse d'Orcières à 2280 m, et 181 cm au-dessus de Prapic à 2480 m.

Limite d'enneigement skiable : vers 1400 m en ubacs, 1700/1800 m en adrets pas trop raides.

État de la neige de surface : après un bon regel nocturne, neige croutée en adrets mais aussi en ubac sous 2000 m environ, humidification au soleil. En ubac d'altitude, neige récente restée sèche. Manteau neigeux restant hivernal à très haute altitude, travaillé par le vent.

Aperçu météo pour le mercredi 25 mars

	nuit	matin	après-midi	soir
	Largement ensoleillé mais renforcement du vent de nord-ouest. Dégradation nordique tardive.			
Pluie-Neige			1 700 m	500 m
Iso 0 °C	2 500 m	2 400 m	2 000 m	1 000 m
Vent 2000 m	↓ 5 km/h	→ 15 km/h	↘ 50 km/h	↘ 55 km/h
Vent 3000 m	→ 20 km/h	→ 35 km/h	↘ 60 km/h	↘ 70 km/h

Épaisseur de neige hors-piste

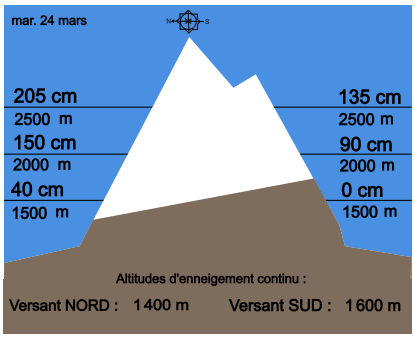

Précipitations à 1800 m

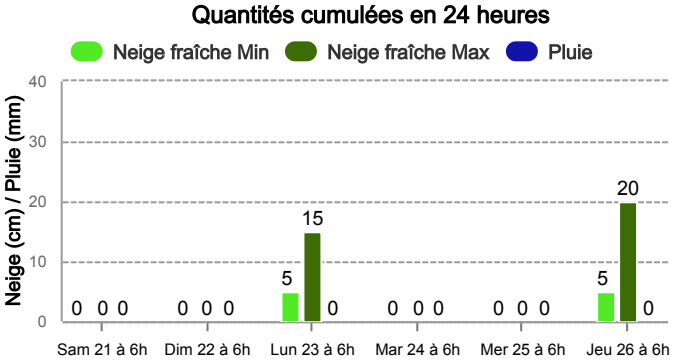

Tendance du jeudi 26 mars

Indice de risque marqué

Risque en hausse. Nouvelles instabilités avec les chutes de neige et le vent fort.

Pour consulter la vigilance en cours, veuillez vous rendre sur le site https://vigilance.meteofrance.fr/fr

Météo-France - 73 avenue de Paris, 94165 Saint-Mandé cedex - Contact : contact@meteo.fr

Rédigé par Météo-France avec la contribution des observateurs du réseau nivo-météorologiques. Partenariat : ANMSM (Maires de Stations de Montagne), DSF (Domaines Skiables de France), ADSP (Directeurs de Pistes et de la Sécurité des Stations de Sports d'Hiver) et autres acteurs de la montagne.

Bulletin neige & avalanches par téléphone au **0 892 68 10 20** Service 0,35 € / min + prix appel

RÉPUBLIQUE FRANÇAISE
Liberté Égalité Fraternité

METEO FRANCE
À VOS CÔTÉS, DANS UN CLIMAT QUI CHANGE

Bulletin d'estimation du risque d'avalanche

(valable en dehors des pistes balisées et ouvertes)

MASSIF : Champsaur

Rédigé le mardi 24 mars 2026 à 16h

Conditions nivo-météo des 7 derniers jours

	mer. 18/03				jeu. 19/03				ven. 20/03				sam. 21/03				dim. 22/03				lun. 23/03				mar. 24/03			
	03h	09h	15h	21h	03h	09h	15h	21h	03h	09h	15h	21h	03h	09h	15h	21h	03h	09h	15h	21h	03h	09h	15h	21h	03h	09h	15h	21h
Météo																												
Vent (km/h)	15	35	70	75	55	50	30	20	15	10	10	10	10	10	10	10	15	20	30	30	25	15	15	15	15	10	10	10
à 3000m	↓	←	←	←	←	↙	←	←	←	←	↗	↙	↘	↗	→	↘	→	←	←	←	←	←	↙	←	←	↓	↗	↓
Vent (km/h)	5	10	40	55	55	25	15	10	10	5	10	5	5	5	10	5	5	10	25	25	15	10	15	10	10	10	10	5
à 2000m	↓	↓	←	↙	←	←	→	←	↘	←	↗	←	↘	↘	↘	↓	↘	↖	←	←	↙	←	↘	←	↓	↘	→	←

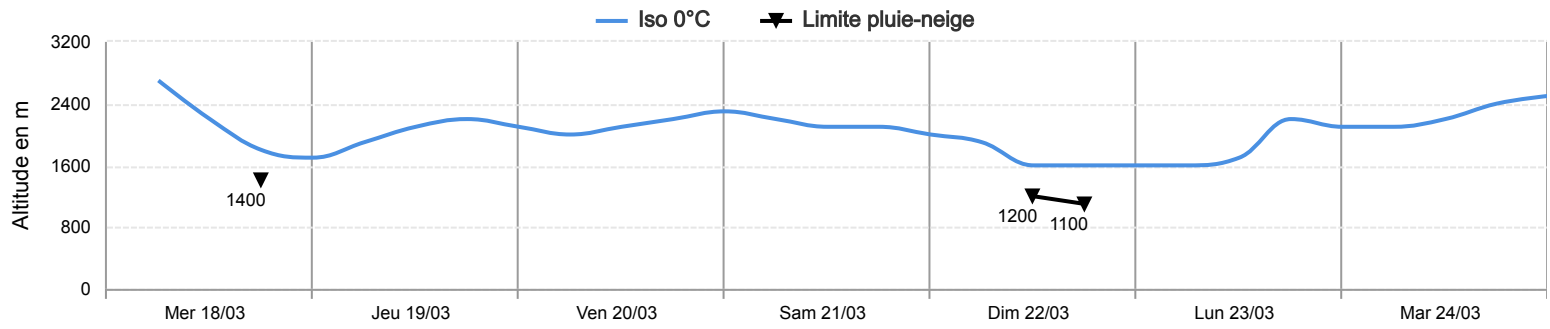

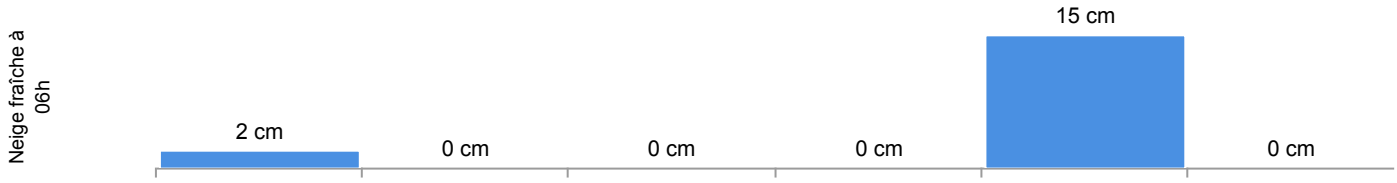

Risque d'avalanche	mer. 18/03	jeu. 19/03	ven. 20/03	sam. 21/03	dim. 22/03	lun. 23/03	mar. 24/03
	3	3	2	2	2	2	2

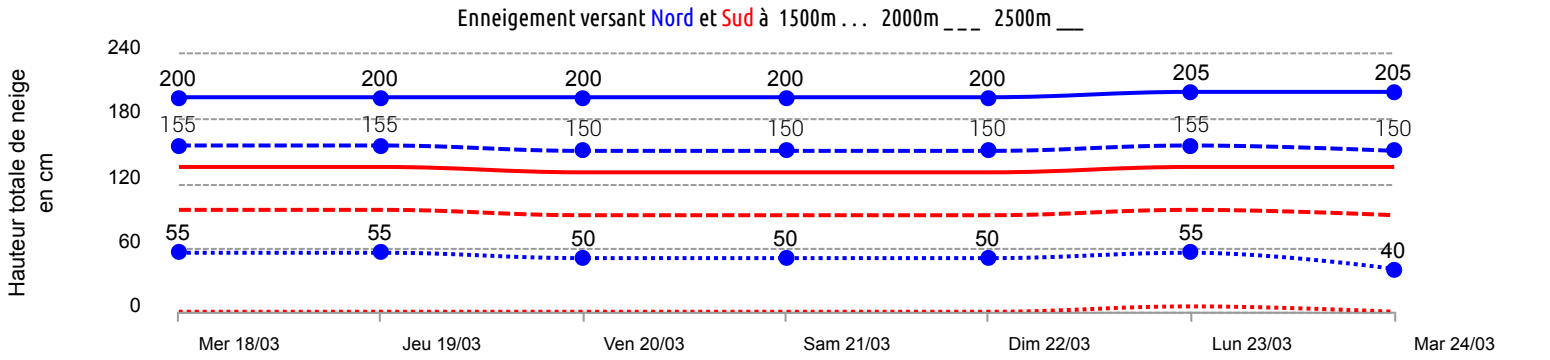

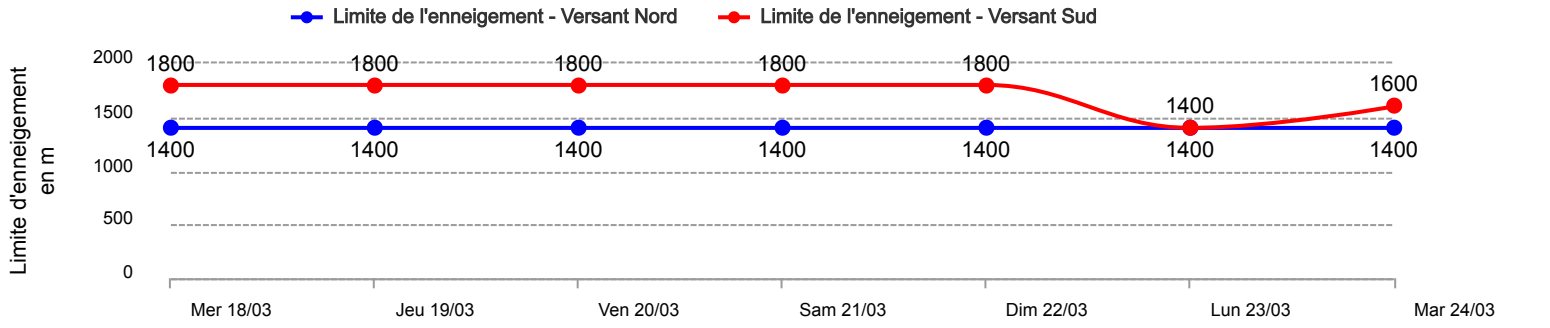

Pour consulter la vigilance en cours, veuillez vous rendre sur le site https://vigilance.meteofrance.fr/fr

Météo-France - 73 avenue de Paris, 94165 Saint-Mandé cedex - Contact : contact@meteo.fr

Rédigé par Météo-France avec la contribution des observateurs du réseau nivo-météorologiques. Partenariat : ANMSM (Maires de Stations de Montagne), DSF (Domaines Skiables de France), ADSP (Directeurs de Pistes et de la Sécurité des Stations de Sports d'Hiver) et autres acteurs de la montagne.

Bulletin neige & avalanches par téléphone au

0 892 68 10 20 Service 0,35 € / min + prix appel