# Bulletin d'estimation du risque d'avalanche

(valable en dehors des pistes balisées et ouvertes)

# MASSIF : Haut-Var Haut-Verdon

Rédigé le mardi 24 mars 2026 à 16h

## Estimation des risques pour le : MERCREDI 25 MARS

**QUELQUES PLAQUES DANS LA NEIGE RÉCENTE VENTÉE - UN PEU D'ACTIVITÉ NATURELLE AU SOLEIL**

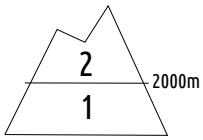


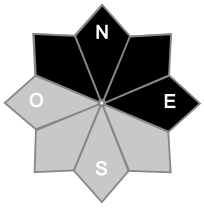


Au-dessus de 2000m indice de risque limité, plus bas indice faible.

**Départs spontanés :** départs superficiels en neige humide au soleil. Taille limitée.

**Déclenchements provoqués :** encore quelques plaques dans la neige récente, notamment vers le crêtes.

Indices de risque : 5 très fort - 4 fort - 3 marqué - 2 limité - 1 faible -- En noir : les pentes les plus dangereuses

## Stabilité du manteau neigeux

**Situation avalancheuse typique :** neige ventée neige humide

**Déclenchements provoqués :** quelques plaques en place en versants froids d'altitude formées lors des chutes ventées de dimanche dernier, d'autres en formation sous l'action du vent de nord-ouest qui se renforce mercredi après-midi, devenant tempétueux en fin de journée. Ces plaques sont facilement déclenchables et présentes notamment dans les zones d'accumulation, à proximité des crêtes et ruptures de pente. Elles génèrent des avalanches de taille petite à moyenne (taille 1 à 2). En versant nord de haute altitude, un départ un peu plus volumineux n'est pas à exclure.

**Départs spontanés :** rares départs ponctuels de neige récente dans les pentes raides bien ensoleillées. Avalanches de taille 1, rarement 2. Ces départs cessent en fin de journée avec le net refroidissement de la masse d'air.

## Qualité de la neige

**Enneigement** plutôt excédentaire dans le Haut-Verdon, proche des normales dans le Haut Var.
Hauteurs de neige observées : vers 2000 m, 190 cm dans le vallon de Valdemars, 131 cm dans le Haut Var.

**Enneigement skiable** : vers 1400/1500 m en ubacs, 1700/1800 m en adrets peu pentus.

**État de la neige en surface** : on retrouve encore la couche de neige récente (20 à 30 cm), travaillée par le vent de nord-est proche des crêtes, et déjà fortement densifiée jusqu'à haute altitude en sud. Elle peut rester froide et légère dans les versants nord-ouest, nord et nord-est au-dessus de 2000/2200 m. Elle repose en général sur un fond dur/regelé, excepté en ubacs au-dessus de 2000/2200 m, où la couche de neige légère peut être plus importante dans les combes abritées du vent.

## Aperçu météo pour le mercredi 25 mars

| nuit | matin | après-midi | soir |
|---|---|---|---|

Belle matinée puis dégradation nuageuse et venteuse en fin d'après-midi. Fort refroidissement le soir.

| Pluie-Neige | | | | |
|---|---|---|---|---|
| Iso 0 °C | 2 700 m | 3 000 m | 2 900 m | 1 500 m |
| Vent 2000 m | 10 km/h | 25 km/h | 55 km/h | 80 km/h |
| Vent 3000 m | 25 km/h | 40 km/h | 70 km/h | 100 km/h |

## Épaisseur de neige hors-piste

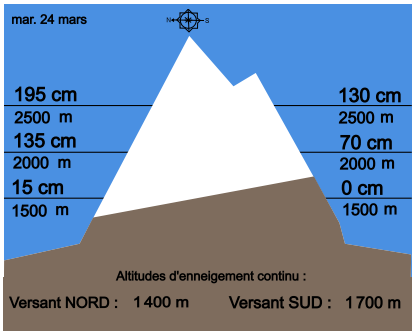


## Précipitations à 1800 m

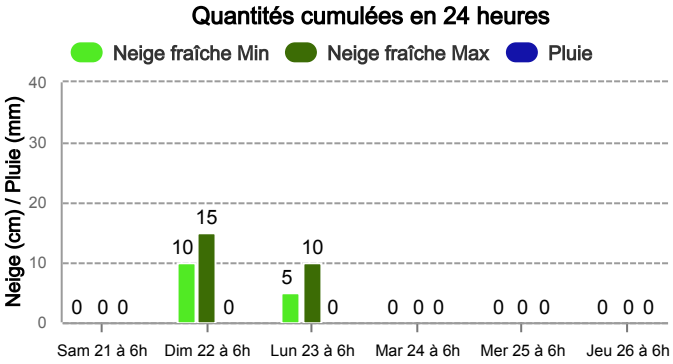


## Tendance du jeudi 26 mars

**Indice de risque limité**

Risque en hausse mais restant à priori limité. Plaques en formation vers les hauts sommets avec le fort vent de nord-ouest qui se poursuit.

Pour consulter la vigilance en cours, veuillez vous rendre sur le site https://vigilance.meteofrance.fr/fr

Météo-France - 73 avenue de Paris, 94165 Saint-Mandé cedex - Contact : contact@meteo.fr

Rédigé par Météo-France avec la contribution des observateurs du réseau nivo-météorologiques. Partenariat : ANMSM (Maires de Stations de Montagne), DSF (Domaines Skiables de France), ADSP (Directeurs de Pistes et de la Sécurité des Stations de Sports d'Hiver) et autres acteurs de la montagne.

Bulletin neige & avalanches par téléphone au 0 892 68 10 20 Service 0,35 € / min + prix appel

# Bulletin d'estimation du risque d'avalanche

(valable en dehors des pistes balisées et ouvertes)

# MASSIF : Haut-Var Haut-Verdon

Rédigé le mardi 24 mars 2026 à 16h

## Conditions nivo-météo des 7 derniers jours

| | mer. 18/03 | | | | jeu. 19/03 | | | | ven. 20/03 | | | | sam. 21/03 | | | | dim. 22/03 | | | | lun. 23/03 | | | | mar. 24/03 | | | |
|---|---|---|---|---|---|---|---|---|---|---|---|---|---|---|---|---|---|---|---|---|---|---|---|---|---|---|---|---|
| | 03h | 09h | 15h | 21h | 03h | 09h | 15h | 21h | 03h | 09h | 15h | 21h | 03h | 09h | 15h | 21h | 03h | 09h | 15h | 21h | 03h | 09h | 15h | 21h | 03h | 09h | 15h | 21h |
| Météo | | | | | | | | | | | | | | | | | | | | | | | | | | | | |
| Vent (km/h) | 20 | 50 | 80 | 80 | 65 | 50 | 30 | 30 | 25 | 15 | 15 | 15 | 10 | 15 | 20 | 15 | 20 | 20 | 35 | 45 | 40 | 25 | 20 | 25 | 20 | 10 | 15 | 15 |
| à 3000m | | | | | | | | | | | | | | | | | | | | | | | | | | | | |
| Vent (km/h) | 10 | 25 | 50 | 50 | 45 | 30 | 20 | 15 | 10 | 10 | 15 | 5 | 5 | 10 | 20 | 10 | 10 | 10 | 25 | 30 | 25 | 15 | 15 | 15 | 10 | 10 | 10 | 10 |
| à 2000m | | | | | | | | | | | | | | | | | | | | | | | | | | | | |

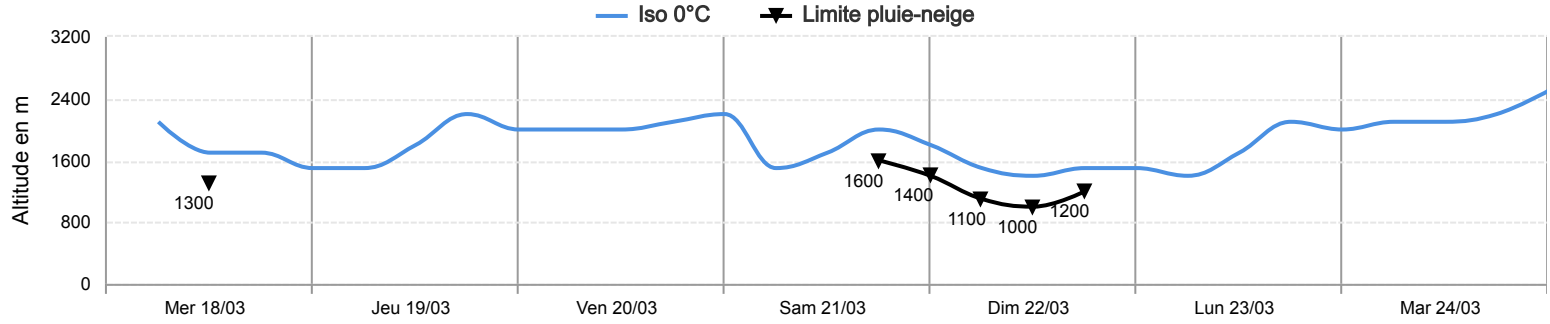


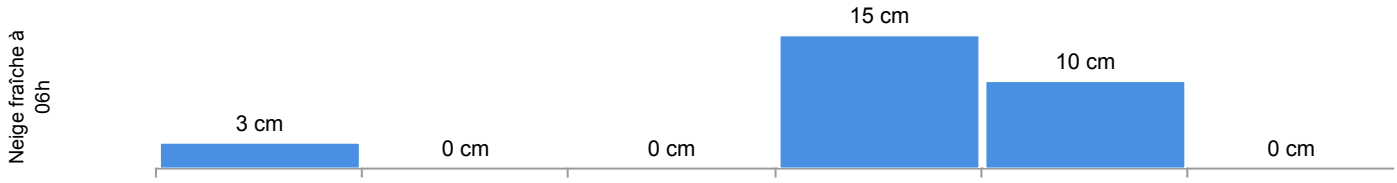


| Risque d'avalanche | mer. 18/03 | jeu. 19/03 | ven. 20/03 | sam. 21/03 | dim. 22/03 | lun. 23/03 | mar. 24/03 |
|---|---|---|---|---|---|---|---|
| | 3 | 3 | 2 | 2 | 3 | 3 | 2 |

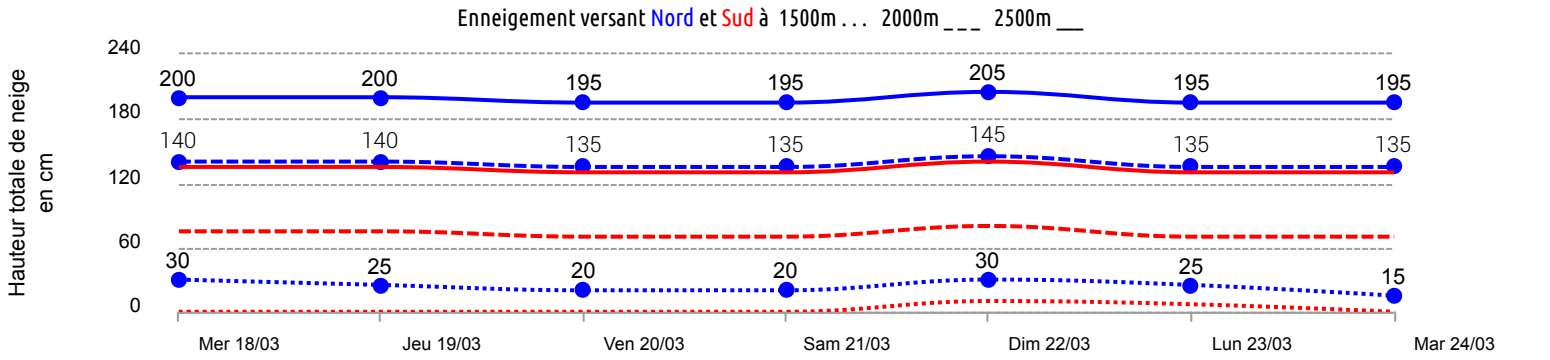


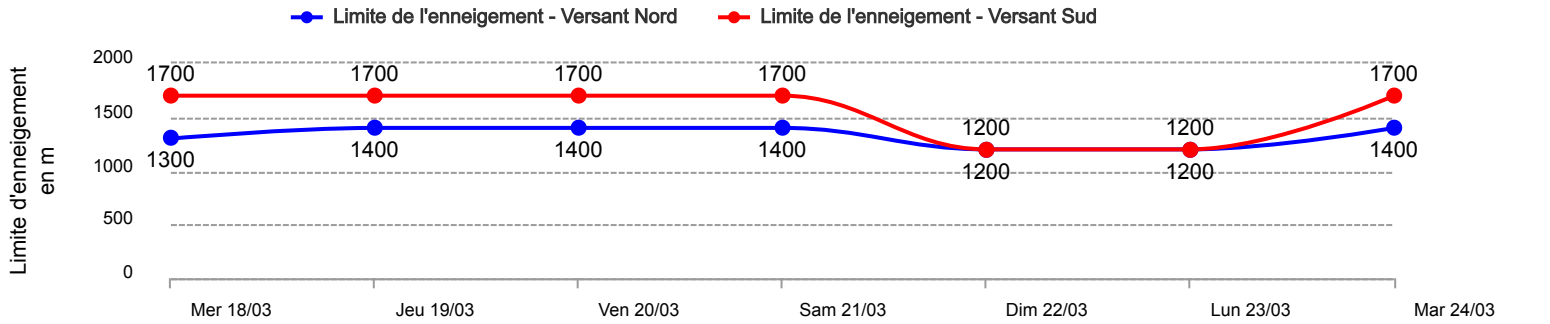


Pour consulter la vigilance en cours, veuillez vous rendre sur le site https://vigilance.meteofrance.fr/fr


Météo-France - 73 avenue de Paris, 94165 Saint-Mandé cedex - Contact : contact@meteo.fr



Rédigé par Météo-France avec la contribution des observateurs du réseau nivo-météorologiques. Partenariat : ANMSM (Maires de Stations de Montagne), DSF (Domaines Skiables de France), ADSP (Directeurs de Pistes et de la Sécurité des Stations de Sports d'Hiver) et autres acteurs de la montagne.



Bulletin neige & avalanches par téléphone au 0 892 68 10 20 Service 0,35 € / min + prix appel