Bulletin d'estimation du risque d'avalanche

(valable en dehors des pistes balisées et ouvertes)

MASSIF : Ubaye

Rédigé le mardi 24 mars 2026 à 16h

Estimation des risques pour le : MERCREDI 25 MARS

QUELQUES PLAQUES DANS LA NEIGE RÉCENTE VENTÉE - UN PEU D'ACTIVITÉ NATURELLE AU SOLEIL

2

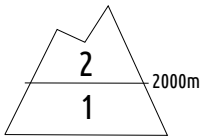

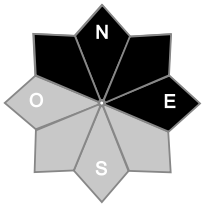

Au-dessus de 2000m indice de risque limité, plus bas indice faible.

Départs spontanés : départs superficiels en neige humide au soleil. Taille limitée.

Déclenchements provoqués : encore quelques plaques dans la neige récente, notamment vers le crêtes.

Indices de risque : 5 très fort - 4 fort - 3 marqué - 2 limité - 1 faible -- En noir : les pentes les plus dangereuses

Stabilité du manteau neigeux

Situation avalancheuse typique : neige ventée — neige humide

Déclenchements provoqués : quelques plaques en place en versants froids d'altitude formées lors des chutes ventées de dimanche dernier, d'autres en formation sous l'action du vent de nord-ouest qui se renforce mercredi après-midi, devenant tempétueux en fin de journée. Ces plaques sont facilement déclenchables et présentes notamment dans les zones d'accumulation, à proximité des crêtes et ruptures de pente. Elles génèrent des avalanches de taille petite à moyenne (taille 1 à 2). En versant nord de haute altitude, un départ un peu plus volumineux n'est pas à exclure.

Départs spontanés : rares départs ponctuels de neige récente dans les pentes raides bien ensoleillées. Avalanches de taille 1, rarement 2. Ces départs cessent en fin de journée avec le net refroidissement de la masse d'air.

Qualité de la neige

Enneigement proche des normales.
Hauteurs de neige observées : 78 cm à la Nivôse de Restefond à 2550 m (secteur venté), 94 cm au-dessus de Larche à 2270 m en adret.

Enneigement skiable : vers 1500 m en ubacs, 1800/1900 m en adrets peu pentus.

État de la neige en surface : on retrouve encore la couche de neige récente (15 à 30 cm), travaillée par le vent de nord-est proche des crêtes, et déjà fortement densifiée jusqu'à haute altitude en sud. Elle peut rester froide et légère dans les versants nord-ouest, nord et nord-est au-dessus de 2000/2200 m. Elle repose en général sur un fond dur/regelé, excepté en ubacs au-dessus de 2000/2200 m, où la couche de neige légère peut être plus importante dans les combes abritées du vent.

Aperçu météo pour le mercredi 25 mars

nuit	matin	après-midi	soir

Belle matinée puis dégradation nuageuse et venteuse. Fort refroidissement en fin de journée.

Pluie-Neige				
Iso 0 °C	2 600 m	2 700 m	2 600 m	1 200 m
Vent 2000 m	10 km/h	20 km/h	50 km/h	80 km/h
Vent 3000 m	25 km/h	40 km/h	70 km/h	100 km/h

Épaisseur de neige hors-piste

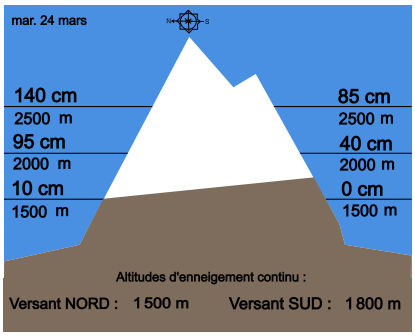

Précipitations à 1800 m

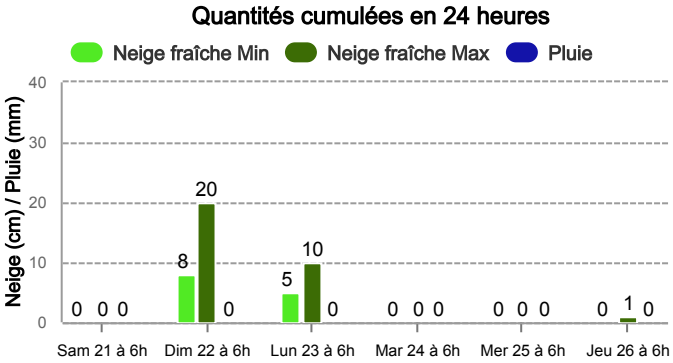

Tendance du jeudi 26 mars

2 **Indice de risque limité**

Risque en hausse mais restant à priori limité. Plaques en formation vers les hauts sommets avec le fort vent de nord-ouest qui se poursuit.

Pour consulter la vigilance en cours, veuillez vous rendre sur le site https://vigilance.meteofrance.fr/fr

Météo-France - 73 avenue de Paris, 94165 Saint-Mandé cedex - Contact : contact@meteo.fr

Rédigé par Météo-France avec la contribution des observateurs du réseau nivo-météorologiques. Partenariat : ANMSM (Maires de Stations de Montagne), DSF (Domaines Skiables de France), ADSP (Directeurs de Pistes et de la Sécurité des Stations de Sports d'Hiver) et autres acteurs de la montagne.

Bulletin neige & avalanches par téléphone au 0 892 68 10 20 Service 0,35 € / min + prix appel

RÉPUBLIQUE FRANÇAISE
Liberté Égalité Fraternité

METEO FRANCE
À VOS CÔTÉS, DANS UN CLIMAT QUI CHANGE

Bulletin d'estimation du risque d'avalanche

(valable en dehors des pistes balisées et ouvertes)

MASSIF : Ubaye

Rédigé le mardi 24 mars 2026 à 16h

Conditions nivo-météo des 7 derniers jours

	mer. 18/03				jeu. 19/03				ven. 20/03				sam. 21/03				dim. 22/03				lun. 23/03				mar. 24/03			
	03h	09h	15h	21h	03h	09h	15h	21h	03h	09h	15h	21h	03h	09h	15h	21h	03h	09h	15h	21h	03h	09h	15h	21h	03h	09h	15h	21h
Météo																												
Vent (km/h)	25	50	70	80	70	50	30	30	20	15	15	10	15	15	20	15	15	25	35	40	35	25	20	15	15	10	15	20
à 3000m																												
Vent (km/h)	10	30	50	50	45	30	20	15	10	10	15	5	5	10	20	10	10	15	25	30	25	15	15	10	5	5	5	5
à 2000m																												

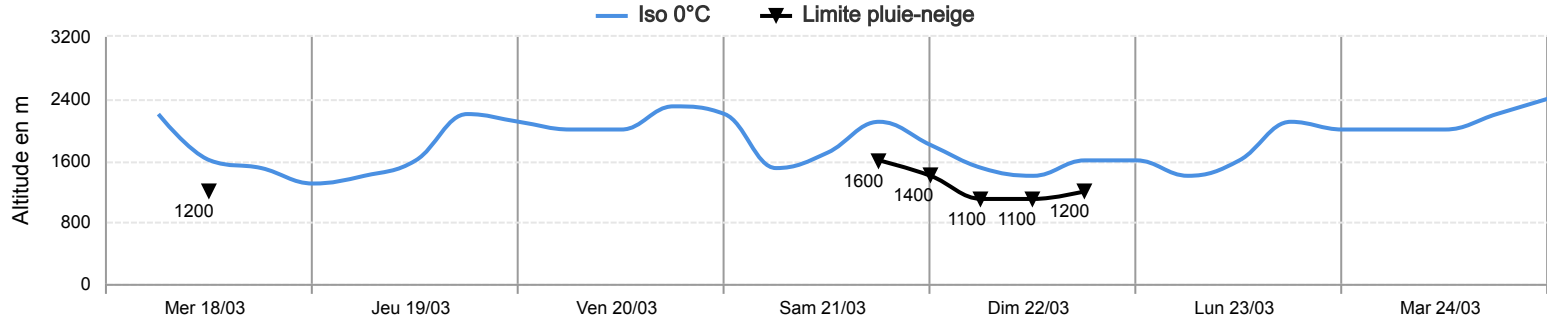

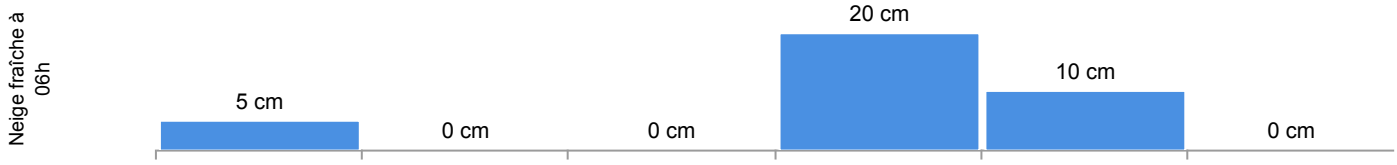

Risque d'avalanche	mer. 18/03	jeu. 19/03	ven. 20/03	sam. 21/03	dim. 22/03	lun. 23/03	mar. 24/03
	3	3	2	2	3	3	2

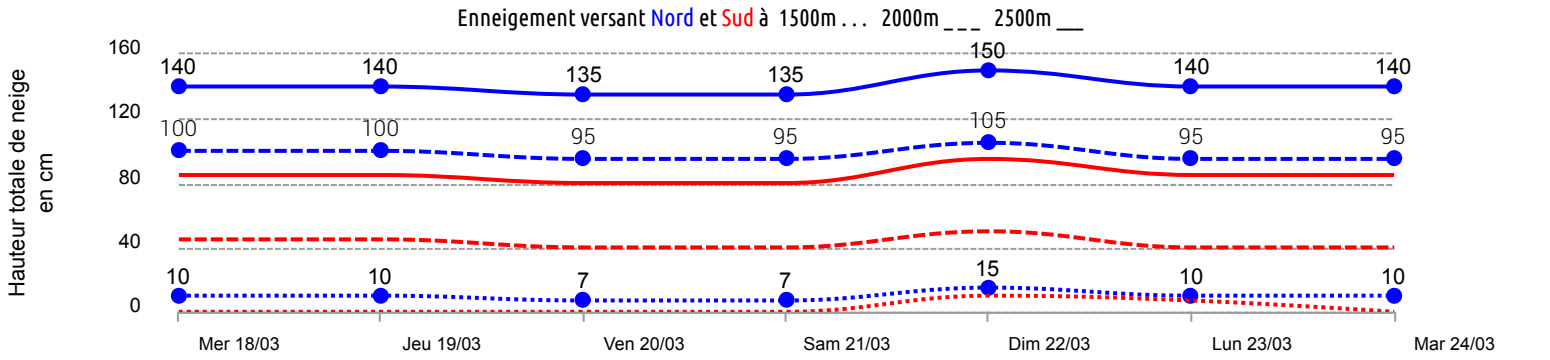

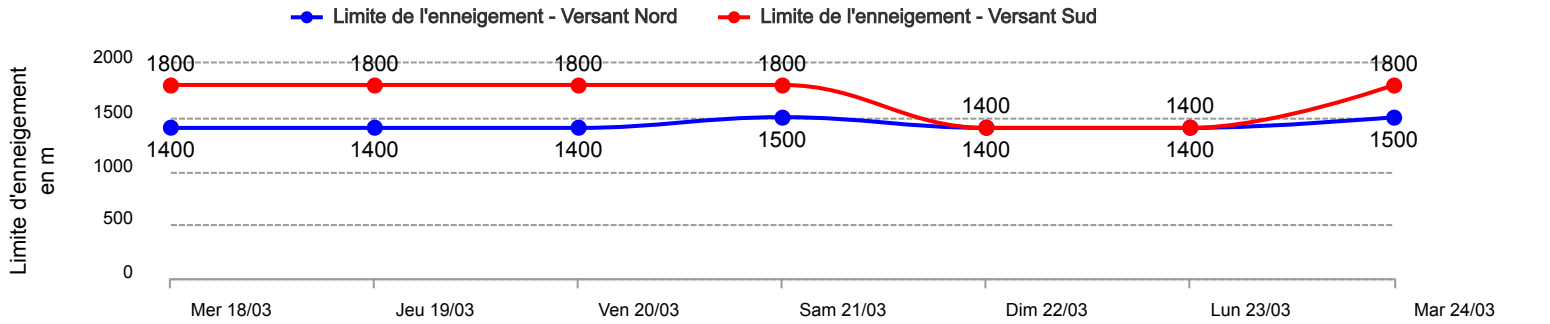

Pour consulter la vigilance en cours, veuillez vous rendre sur le site https://vigilance.meteofrance.fr/fr

Météo-France - 73 avenue de Paris, 94165 Saint-Mandé cedex - Contact : contact@meteo.fr

Bulletin neige & avalanches par téléphone au

0 892 68 10 20 Service 0,35 € / min + prix appel

Rédigé par Météo-France avec la contribution des observateurs du réseau nivo-météorologiques. Partenariat : ANMSM (Maires de Stations de Montagne), DSF (Domaines Skiables de France), ADSP (Directeurs de Pistes et de la Sécurité des Stations de Sports d'Hiver) et autres acteurs de la montagne.