GOBIERNO DE ESPAÑA
VICEPRESIDENCIA TERCERA DEL GOBIERNO
MINISTERIO PARA LA TRANSICIÓN ECOLÓGICA Y EL RETO DEMOGRÁFICO

Boletín de información nivológica y de peligro de aludes

Pirineo Catalán

aemet Agencia Estatal de Meteorología

miércoles, 25 de marzo de 2026

Pronóstico hasta las 24 horas del jueves, día 26 de marzo

(Válido fuera de pistas de esquí balizadas y abiertas)

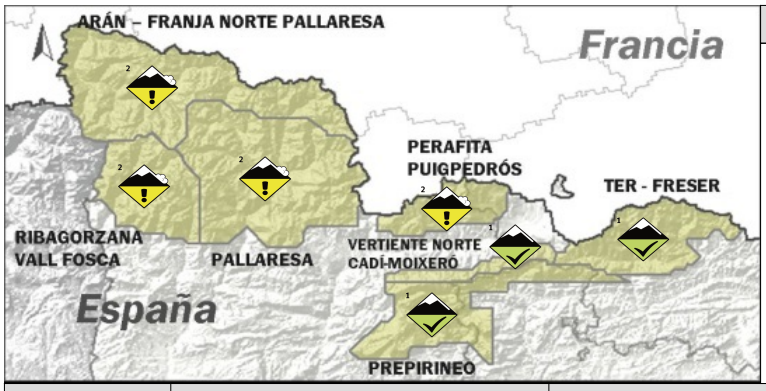

Problemas de aludes

- Placas de viento
- Nieve reciente
- Capas débiles persistentes

Macizo	Peligro	Problemas de aludes, cota, orientación, tamaño	Innivación observada (m)
Arán - Franja norte Pallaresa	2 2 / 1 — 1800 **Limitado**	**Nieve reciente** 1800 — N, O, E, S — 2 **Placas de viento** 2200 — N, O, E, S — 2	2026-03-25 N / S Cota más baja caras N
Ribagorzana - Vall Fosca	2 2 / 1 — 2200 **Limitado**	**Placas de viento** 2200 — N, O, E, S — 2 **Capas débiles persistentes** 2400 — N, O, E, S — 2	2026-03-25 N / S Cota más baja caras N
Pallaresa	2 2 / 1 — 2200 **Limitado**	**Placas de viento** 2200 — N, O, E, S — 2 **Capas débiles persistentes** 2400 — N, O, E, S — 2	2026-03-25 N / S Cota más baja caras N

AEMET. Se autoriza la reproducción de su contenido citando la fuente.

Boletín de información nivológica y de peligro de aludes

Pirineo Catalán

Perafita - Puigpedrós	2 **Limitado**	**Placas de viento** 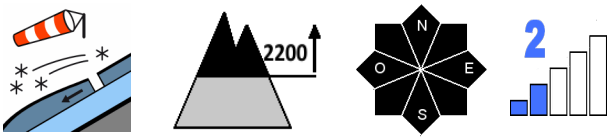 **Capas débiles persistentes** 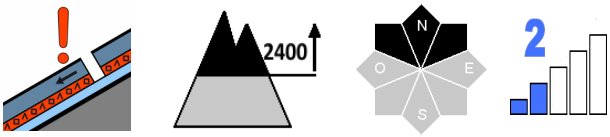	2026-03-25 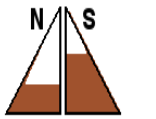 Cota más baja caras N
Ter - Freser	1 **Débil**	**Placas de viento** **Capas débiles persistentes** 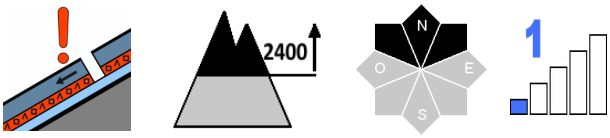	2026-03-25 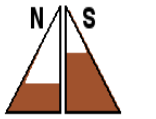 Cota más baja caras N
Vertiente norte Cadí - Moixeró	1 **Débil**	**Placas de viento**	2026-03-25 Cota más baja caras N
Prepirineo	1 **Débil**	**Placas de viento** 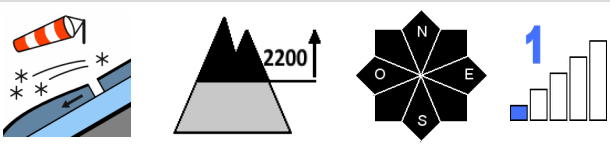	2026-03-25 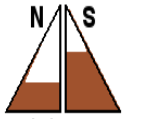 Cota más baja caras N

Estado del manto y observaciones recientes

Prosigue el apelmazamiento y disminución del manto, tanto en grosor como en extensión, con pérdidas de algunos cm durante las últimas 24 horas. Pese a ello presenta continuidad desde medianías, a mayor altitud en orientaciones sur, aunque con disimetría entre solanas y umbrías. Los espesores siguen siendo importantes, y se sitúan por encima de lo que pueden considerarse normal a estas alturas de la temporada, superando los 200 cm por encima de unos 2200 metros en bastantes zonas de la mitad occidental.

La nieve se encuentra muy humedecida en zonas medias y bajas, y de manera más superficial en solanas de cotas altas, estando sometida al ciclo de fusión diurna y rehielo nocturno. En las altas umbrías predomina la nieve más seca, venteada y encostrada, pudiendo existir estratos débiles en el interior del manto localizados a no demasiada profundidad.

Evolución del manto y peligro de aludes para el jueves, día 26

Problema de placas de viento y capas débiles persistentes en cotas altas. Problema de nieve reciente.

AEMET. Se autoriza la reproducción de su contenido citando la fuente.

Hoy, miércoles, va aumentar la nubosidad desde el oeste, que dejará precipitaciones en la cordillera, con la cota de nieve en acusado descenso. Entre hoy y mañana se esperan unos 5-15 cm en el Arán y Franja Norte Pallaresa, localmente más, sin descartar alguna nevada dispersa y ocasional en las demás zonas. Con estas condiciones se podrán producir purgas de nieve reciente en las laderas suficientemente inclinadas de las áreas afectadas por las precipitaciones, siendo de nieve más húmeda en cotas bajas, de tamaño pequeño (riesgo de caída), localmente mediano (capaz de enterrar a una persona). Tampoco se descarta algún alud de nieve húmeda en las zonas soleadas.

También soplarán fuertes vientos de componente norte, que levantarán ventiscas y formarán placas en diversas orientaciones, aunque con mayor probabilidad en vertientes sur y este, y que en las altas umbrías podrán descansar sobre los estratos débiles que aún persisten en el interior del manto. Todas estas estructuras podrán colapsar ante una sobrecarga débil (paso de un solo esquiador), ocasionando aludes de dimensiones pequeñas o medianas.

Predicción meteorológica para el jueves, día 26

Predominio de cielos muy nubosos en el valle de Arán y resto de la divisoria con Francia, con nubes bajas y visibilidad localmente reducida. Intervalos nubosos en las demás zonas, tendiendo a poco nuboso o despejado. Se esperan precipitaciones débiles o localmente moderadas en Arán y Franja Norte Pallaresa, que de manera más dispersa y ocasional podrían afectar a zonas próximas, siendo más probables de madrugada. Cota de nieve en torno a 700-800 metros, aunque transitoriamente podría estar algo más baja. Temperaturas en descenso, ligero en las mínimas y notable en las máximas. Heladas débiles o moderadas, persistentes y localmente fuertes en la alta montaña. Viento de componente norte, fuerte con rachas muy fuertes en cotas altas y zonas expuestas, moderado con intervalos fuertes en el resto.

Datos en la atmósfera libre:

Altitud de la isoterma de 0 ºC: 1500 m
Altitud de la isoterma de -10 ºC: 4000 m (W) - 3700 m (E)

Viento a 1500 m: NW de 30 km/h a 50 km/h
Viento a 3000 m: N 100 km/h

Evolución para el viernes día 27

Con pocos cambios.

Escala europea de peligro de aludes

Débil | Limitado | Notable | Fuerte | Muy Fuerte

Problemas de aludes

Nieve reciente | Placas de viento | Capas débiles persistentes | Nieve húmeda | Deslizamientos basales | Sin problema evidente

Nota1: Se recuerda que, siempre que haya nieve, la ausencia total de peligro no existe. Hay que tener presente que en circunstancias desfavorables, con aludes de tamaño 1 (alud pequeño o colada) y tamaño 2 (alud mediano), se pueden sufrir severos daños personales.

Nota2: Los BPA se elaboran en base a información meteorológica así como al estado del manto nivoso a través de sondeos puntuales. Se advierte a los usuarios de la variabilidad de esta información al extrapolarla a zonas extensas de montaña. Por ello, AEMET no se hace responsable de su uso para la toma de decisiones que conciernen a la seguridad personal, ni de los riesgos físicos o materiales de ellas derivadas.

AEMET. Se autoriza la reproducción de su contenido citando la fuente.