GOBIERNO DE ESPAÑA
VICEPRESIDENCIA TERCERA DEL GOBIERNO
MINISTERIO PARA LA TRANSICIÓN ECOLÓGICA Y EL RETO DEMOGRÁFICO

Boletín de información nivológica y de peligro de aludes

Pirineo Navarro y Aragonés

aemet Agencia Estatal de Meteorología

miércoles, 25 de marzo de 2026

Pronóstico hasta las 24 horas del jueves, día 26 de marzo

(Válido fuera de pistas de esquí balizadas y abiertas)

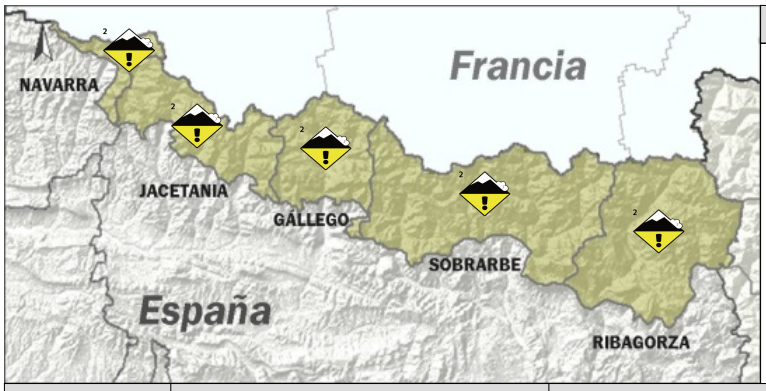

Problemas de aludes

Nieve reciente

Placas de viento

Macizo	Peligro	Problemas de aludes, cota, orientación, tamaño	Innivación observada (m)
Navarra	2 / 2 / 1 / 1800 Limitado	Nieve reciente: 1800, N O E S, 2 Placas de viento: 2200, N O E S, 2	2026-03-25 N S Cota más baja caras N
Jacetania	2 / 2 / 1 / 1800 Limitado	Nieve reciente: 1800, N O E S, 2 Placas de viento: 2200, N O E S, 2	2026-03-25 N S Cota más baja caras N
Gállego	2 / 2 / 1 / 2200 Limitado	Nieve reciente: N O E S, 1 Placas de viento: 2200, N O E S, 2	2026-03-25 N S Cota más baja caras N

AEMET. Se autoriza la reproducción de su contenido citando la fuente.

Boletín de información nivológica y de peligro de aludes

Pirineo Navarro y Aragonés

Sobrarbe	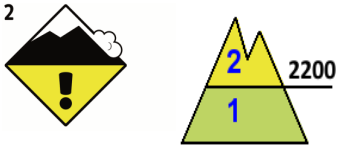 **Limitado**	**Nieve reciente** 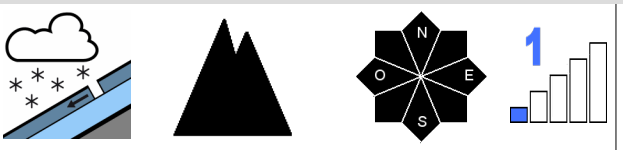 **Placas de viento** 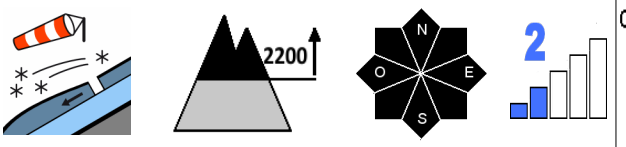	2026-03-25 Cota más baja caras N
Ribagorza	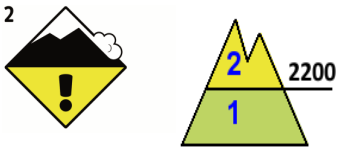 **Limitado**	**Nieve reciente** 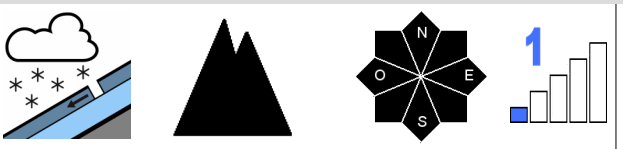 **Placas de viento** 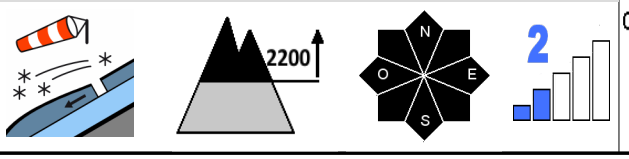	2026-03-25 Cota más baja caras N

Estado del manto y observaciones recientes

Prosigue el apelmazamiento y disminución del manto, tanto en grosor como en extensión, con una pérdida de entre 1 y 7 cm durante las últimas 24 horas en los diferentes puntos de observación. Pese a ello presenta continuidad desde medianías, a mayor altitud en orientaciones sur, aunque con disimetría entre solanas y umbrías. En general, los espesores varían de 30 a 125 cm en torno a 1800 metros y van incrementándose conforme ascendemos, de tal manera que pueden superarse los 170-180 cm en algunas áreas a 2100 metros.

La nieve se encuentra muy humedecida en zonas medias y bajas, y de manera más superficial en solanas de cotas altas, estando sometida al ciclo de fusión diurna y rehielo nocturno. En las altas umbrías predomina la nieve más seca, venteada y encostrada, pudiendo existir estratos débiles en el interior del manto localizados a no demasiada profundidad.

Evolución del manto y peligro de aludes para el jueves, día 26

Problema de placas de viento y capas débiles persistentes en cotas altas. Problema de nieve reciente.

Hoy, miércoles, va aumentar la nubosidad desde el oeste, que dejará precipitaciones en la cordillera, con la cota de nieve en acusado descenso. Entre hoy y mañana se esperan unos 10-20 cm en el sector navarro y resto de la divisoria con Francia, localmente más, sin descartar alguna nevada dispersa y ocasional en las demás zonas. Con estas condiciones se podrán producir purgas de nieve reciente en las laderas suficientemente inclinadas de las áreas afectadas por las precipitaciones, siendo de nieve más húmeda en cotas bajas, de tamaño pequeño (riesgo de caída), localmente mediano (capaz de enterrar a una persona). Tampoco se descarta algún alud de nieve húmeda en las zonas soleadas.

AEMET. Se autoriza la reproducción de su contenido citando la fuente.

También soplarán fuertes vientos de componente norte, que levantarán ventiscas y formarán placas en diversas orientaciones, aunque con mayor probabilidad en vertientes sur, y que en las altas umbrías podrán descansar sobre los estratos débiles que aún persisten en el interior del manto. Todas estas estructuras podrán colapsar ante una sobrecarga débil (paso de un solo esquiador), ocasionando aludes de dimensiones pequeñas o medianas.

Predicción meteorológica para el jueves, día 26

Pirineo navarro:

Muy nuboso o cubierto, con nubes bajas y visibilidad localmente reducida. Se esperan precipitaciones débiles o localmente moderadas, más frecuentes durante la primera mitad del día. Cota de nieve en torno a 700-800 metros. Temperaturas en descenso, ligero en las mínimas y localmente notable en las máximas. Heladas débiles, moderadas o fuertes y persistentes en cotas altas. Viento fuerte de componente norte, con rachas muy fuertes en cotas altas y zonas expuestas.

Pirineo aragonés:

Predominio de cielos muy nubosos en la divisoria fronteriza, con nubes bajas y visibilidad localmente reducida. Intervalos nubosos en el resto, tendiendo a poco nuboso o despejado. Se esperan precipitaciones en la divisoria con Francia y Jacetania, generalmente débiles, que ocasionalmente podrían afectar a zonas próximas, siendo más probables de madrugada. Cota de nieve en torno a 700-800 metros. Temperaturas en descenso, ligero en las mínimas y notable en las máximas. Heladas débiles o moderadas, persistentes y localmente fuertes en la alta montaña. Viento de componente norte, fuerte con rachas muy fuertes en cotas altas y zonas expuestas, moderado con intervalos fuertes en el resto.

Datos en la atmósfera libre:

Altitud de la isoterma de 0 ºC: 1500 m
Altitud de la isoterma de -10 ºC: 4200 m

Viento a 1500 m: N de 30 km/h a 50 km/h
Viento a 3000 m: N 100 km/h

Evolución para el viernes día 27

Con pocos cambios.

(Información elaborada a partir de los datos recibidos de los refugios de Linza, Lizara, Panticosa, Bachimaña, Góriz, Pineta, Estós, Angel Orús, La Renclusa, Cap de Llauset y Belagua, de las estaciones de esquí de Astún y Formigal, de la estación de esquí de fondo de Llanos del Hospital y de Ordesa Pradera)

Escala europea de peligro de aludes

Débil Limitado Notable Fuerte Muy Fuerte

Problemas de aludes

Nieve reciente Placas de viento Capas débiles persistentes Nieve húmeda Deslizamientos basales Sin problema evidente

Nota1: Se recuerda que, siempre que haya nieve, la ausencia total de peligro no existe. Hay que tener presente que en circunstancias desfavorables, con aludes de tamaño 1 (alud pequeño o colada) y tamaño 2 (alud mediano), se pueden sufrir severos daños personales.

AEMET. Se autoriza la reproducción de su contenido citando la fuente.

Nota2: Los BPA se elaboran en base a información meteorológica así como al estado del manto nivoso a través de sondeos puntuales. Se advierte a los usuarios de la variabilidad de esta información al extrapolarla a zonas extensas de montaña. Por ello, AEMET no se hace responsable de su uso para la toma de decisiones que conciernen a la seguridad personal, ni de los riesgos físicos o materiales de ellas derivadas.

AEMET. Se autoriza la reproducción de su contenido citando la fuente.