Donnerstag 26.03.2026

Veröffentlicht am 25.03.2026 um 17:00

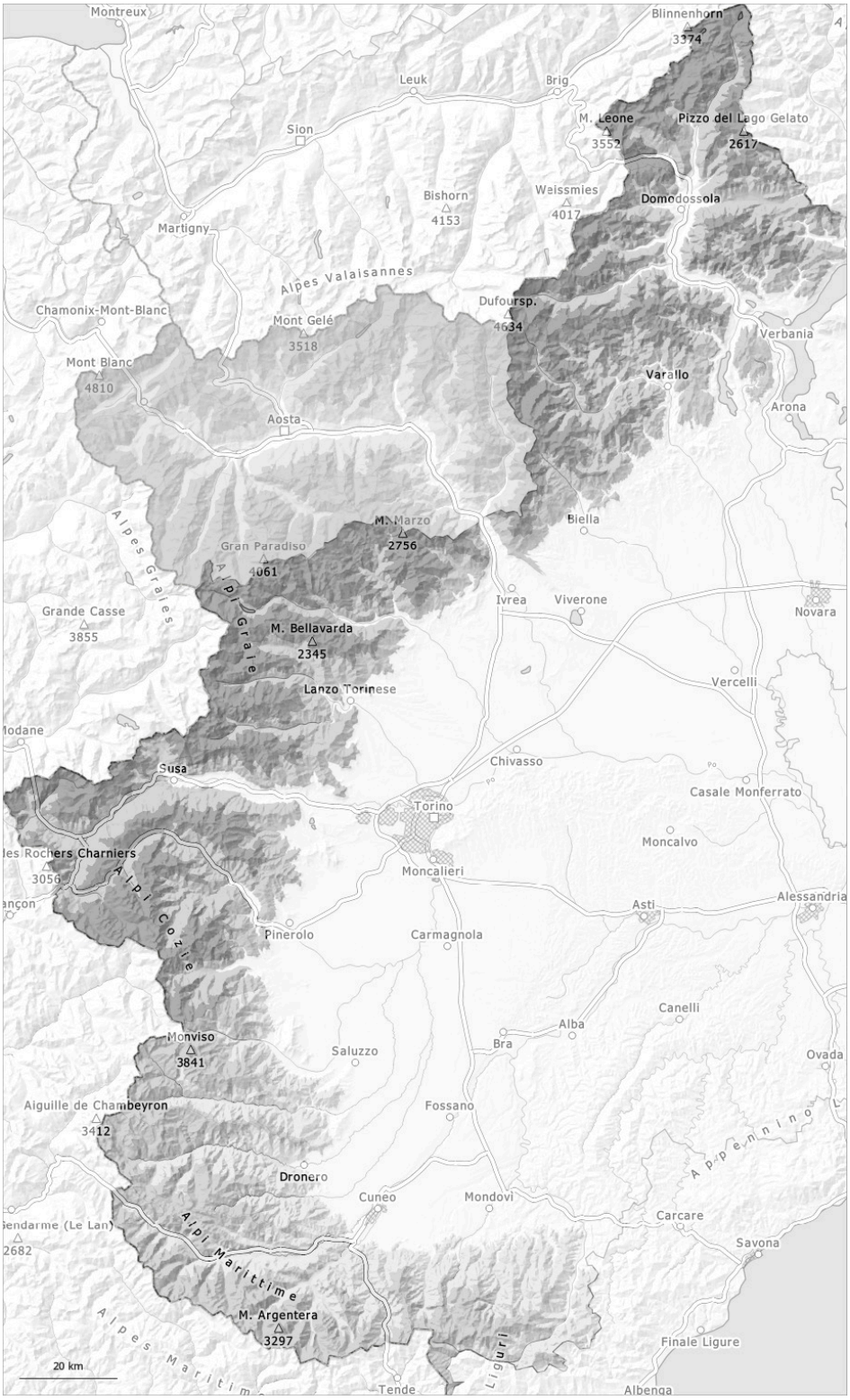

1	2	3	4	5
gering	mäßig	erheblich	groß	sehr groß

Gefahrenstufe 3 - Erheblich

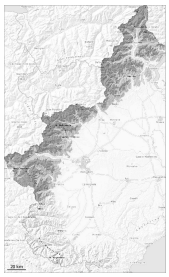

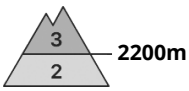

Tendenz: Lawinengefahr bleibt gleich
am Freitag, den 27.03.2026

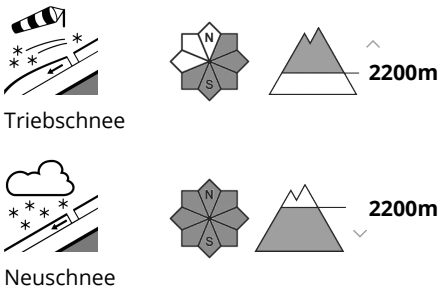

Wind und Neuschnee: Triebschnee vorsichtig beurteilen.
Die Gefahrenstellen liegen v.a. in Rinnen, Mulden und hinter Geländekanten in mittleren und hohen Lagen.

Bis am Morgen fällt vor allem entlang der Grenze zu Frankreich und entlang der Grenze zur Schweiz etwas Schnee. Der Nordwestwind verfrachtet Neu- und Altschnee intensiv.
Mit tiefen Temperaturen, Schneefall und starkem Wind wachsen die Triebschneeansammlungen an.
In Kammlagen, Rinnen und Mulden sind trockene Schneebrettlawinen möglich, auch recht große.
Lawinen können schon von einzelnen Wintersportlern ausgelöst werden oder spontan abgehen, Vorsicht vor allem an Triebschneehängen und an Übergängen von wenig zu viel Schnee wie z.B. bei der Einfahrt in Rinnen und Mulden.

Touren erfordern Vorsicht und Zurückhaltung.

Schneedecke

Gefahrenmuster gm.6: lockerer schnee und wind

Bis am Morgen fallen besonders entlang der Grenze zu Frankreich und entlang der Grenze zur Schweiz 10 bis 15 cm Schnee, lokal auch mehr.
Der Föhn verfrachtet Neu- und Altschnee intensiv.
Neu- und Triebschnee liegen verbreitet auf einer harten Kruste.

Mit tiefen Temperaturen Schneefall und mäßigem bis starkem Nordwestwind wachsen die Triebschneeansammlungen an. Die Wetterbedingungen führen vor allem in mittleren und hohen Lagen zu einem ungünstigen Aufbau der Schneedecke.

V.a. in Kammlagen in hohen Lagen liegen je nach Windeinfluss sehr unterschiedliche Schneehöhen.

Tendenz

> Es ist kalt. Starker Föhn: Bis am Freitag entstehen in Rinnen, Mulden und hinter Geländekanten sowie oberhalb der Waldgrenze weitere Triebschneeansammlungen.

Gefahrenstufe 2 - Mäßig

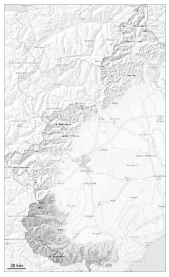

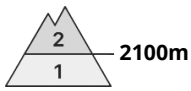

Tendenz: Lawinengefahr bleibt gleich
am Freitag, den 27.03.2026

Triebschnee

2100m

Vorsicht vor Triebschnee, vor allem entlang der Grenze zu Frankreich in den Gebieten mit viel Wind.

Mit mäßigem bis starkem Wind aus nordwestlichen Richtungen entstanden im Tagesverlauf vor allem oberhalb der Waldgrenze Triebschneeansammlungen.
Lawinen können v.a. in Rinnen und Mulden in den verschiedenen Triebschneeschichten anreißen und mittlere Größe erreichen. Einzelne mittlere bis große Lawinen sind aber nicht ausgeschlossen.

Triebschneeansammlungen können vereinzelt schon von einzelnen Wintersportlern ausgelöst werden. Dies vor allem an Übergängen von wenig zu viel Schnee wie z.B. bei der Einfahrt in Rinnen und Mulden und an steilen Hängen.
Abseits der Pisten braucht es Vorsicht.

Schneedecke

Gefahrenmuster gm.6: lockerer schnee und wind

Der Nordwestwind hat den lockeren Altschnee verfrachtet.
Mit der markanten Abkühlung und mäßigem bis starkem Föhn entstanden Triebschneeansammlungen.
Hohe Lagen und Hochgebirge: Der Triebschnee liegt auf einer glatten Altschneeoberfläche.

Vor allem in Gipfellagen liegen je nach Windeinfluss sehr unterschiedliche Schneehöhen.

Tendenz

Es ist kalt. Entlang der Grenze zu Frankreich und in der Höhe sind die Gefahrenstellen häufiger und die Gefahr höher.