ICGC Institut Cartogràfic i Geològic de Catalunya

Servei Meteorològic de Catalunya meteo.cat

Boletín de peligro de aludes para el Pirineo de Catalunya
Del 25/03/2026 al 26/03/2026

(Válido fuera pistas de esquí y zonas no controladas)

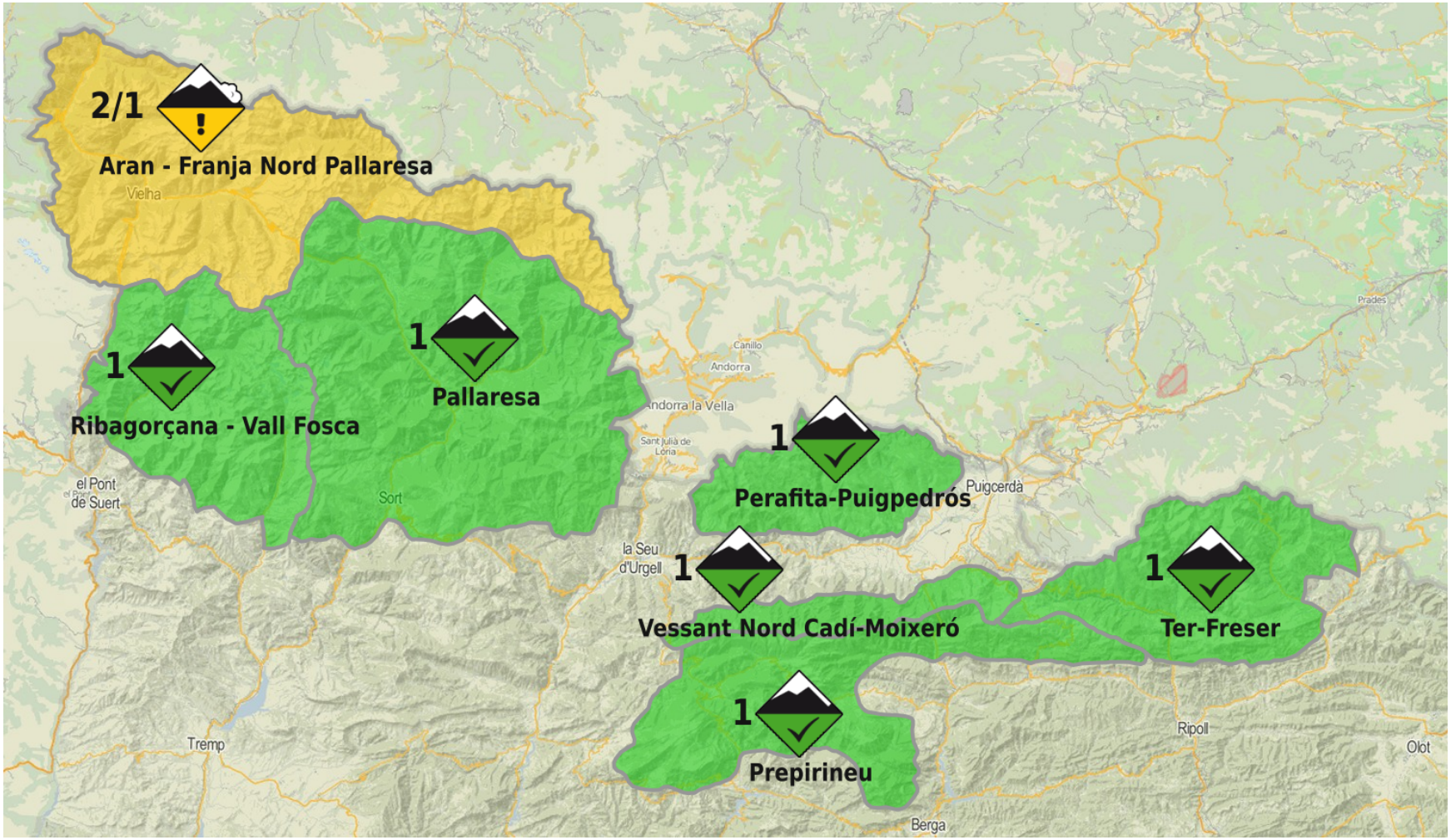

5 MUY FUERTE	4 FUERTE	3 NOTABLE	2 LIMITADO	1 DÉBIL

ICGC Institut Cartogràfic i Geològic de Catalunya

Servei Meteorològic de Catalunya

Boletín de peligro de aludes Aran - Franja Nord Pallaresa Del 25/03/2026 al 26/03/2026

(Válido fuera pistas de esquí y zonas no controladas)

LIMITADO (2), por encima de 2.200 m.
DÉBIL (1), por debajo.

Situación primaria

Nieve venteada

Distribución

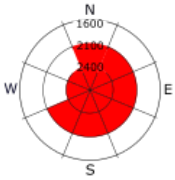

Tamaño

Origen

Tendencia

Situación secundaria

Capas débiles persistentes

Distribución

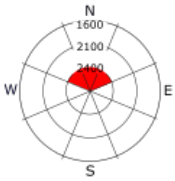

Tamaño

Origen

Tendencia

Estado del manto nivoso

El fuerte viento previsto para el miércoles y el jueves, de NW y N, podrá movilizar la nieve reciente y la nieve superficial del manto que todavía se mantiene seca en umbrías de cota alta. Se podrán formar nuevas placas por encima del límite del bosque, bajo collados y crestas, y sectores más resguardados, a cualquier orientación pero preferentemente en S y E. Las placas se mostrarán sensibles y podrán caer incluso de forma natural, generando aludes de pequeño tamaño en general. No se descarta que en momentos de sol se produzcan algunas purgas en laderas más inclinadas.

En umbrías altas, por encima de unos 2.300 m, es posible todavía encontrar alguna placa antigua que descanse sobre niveles débiles y por sobrecarga fuerte pueda romper y caer, generando aludes que pueden ser de tamaño pequeño o medio.

Distribución del manto nivoso

Hay nieve por encima de unos 1.600 m en umbrías y 1.900 m en solanas. Los espesores a unos 2.200 m son ligeramente superiores a los normales en la Franja Nord de la Pallaresa y en la mitad sur de Arán, donde rondan los 180-220 cm. En la mitad norte de Arán son los normales por estas fechas con unos 120-140 cm de espesor total.

Tendencia para las próximas 48-72h

Las placas de viento continuarán sensibles y la estabilidad del manto permanecerá con pocos cambios. Peligro: ESTACIONARIO.

El próximo boletín será emitido el día 2026-03-26

5 MUY FUERTE	4 FUERTE	3 NOTABLE	2 LIMITADO	1 DÉBIL

EAWS EUROPEAN AVALANCHE WARNING SERVICES

ICGC Institut Cartogràfic i Geològic de Catalunya

Servei Meteorològic de Catalunya

Boletín de peligro de aludes Ribagorçana - Vall Fosca Del 25/03/2026 al 26/03/2026

(Válido fuera pistas de esquí y zonas no controladas)

DÉBIL (1)

Situación primaria

Nieve venteada

Distribución

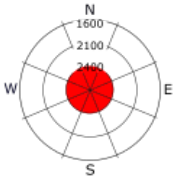

Tamaño

Origen

Tendencia

Situación secundaria

Capas débiles persistentes

Distribución

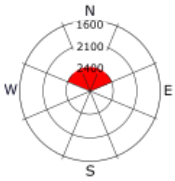

Tamaño

Origen

Tendencia

Estado del manto nivoso

El fuerte viento previsto para el miércoles y el jueves, de NW y N, podrá movilizar la nieve superficial que todavía se mantiene seca en umbrías de cota alta así como la nieve reciente prevista. Se podrán formar nuevas placas en cota alta, pequeñas y locales, bajo collados y crestas, y sectores más resguardados donde el viento no barra la nieve, a cualquier orientación pero preferentemente en S. Las placas podrán ser sensibles y ceder al paso de una persona provocando aludes de tamaño 1, pequeño, en general, muy localmente de tamaño mediano.
En umbrías muy altas es posible todavía encontrar alguna placa antigua que descanse sobre niveles débiles y por sobrecarga fuerte pueda romper y caer, generando aludes de pequeño tamaño en general.
En solanas principalmente, encontraremos un manto encostrado y endurecido, y habrá que ir con cuidado con los rebalones.

Distribución del manto nivoso

Hay nieve en el suelo a 1.700 m en N, y a unos 2.100 m en S de forma discontinua, pasando a ser continua a partir de unos 2.300 m. Los grosores alcanzan los 100-120 cm a unos 2.200 m. Estos valores se acercan a los normales para la época.

Tendencia para las próximas 48-72h

Las placas de viento continuarán sensibles y se puede formar alguna nueva. Peligro: ESTACIONARIO.

El próximo boletín será emitido el día 2026-03-26

5 MUY FUERTE	4 FUERTE	3 NOTABLE	2 LIMITADO	1 DÉBIL

EAWS EUROPEAN AVALANCHE WARNING SERVICES

ICGC Institut Cartogràfic i Geològic de Catalunya

Servei Meteorològic de Catalunya

Boletín de peligro de aludes Pallaresa
Del 25/03/2026 al 26/03/2026

(Válido fuera pistas de esquí y zonas no controladas)

1 DÉBIL (1)

Situación primaria

Nieve venteada

Distribución

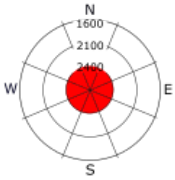

Tamaño

Origen

Tendencia

Situación secundaria

Capas débiles persistentes

Distribución

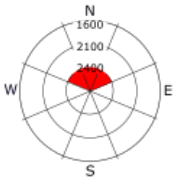

Tamaño

Origen

Tendencia

Estado del manto nivoso

El fuerte viento previsto para el miércoles y el jueves, de NW y N, podrá movilizar la nieve superficial que todavía se mantiene seca en umbrías de cota alta así como la nieve reciente prevista. Se podrán formar nuevas placas en cota alta, pequeñas y locales, bajo collados y crestas, y sectores más resguardados donde el viento no barra la nieve, a cualquier orientación pero preferentemente en S. Las placas podrán ser sensibles y ceder al paso de una persona provocando aludes de tamaño 1, pequeño, en general, muy localmente de tamaño mediano.
En umbrías muy altas es posible todavía encontrar alguna placa antigua que descanse sobre niveles débiles y por sobrecarga fuerte pueda romper y caer, generando aludes de pequeño tamaño en general.
En solanas principalmente, encontraremos un manto encostrado y endurecido, y habrá que ir con cuidado con los rebalones.

Distribución del manto nivoso

Hay nieve en el suelo a 1.700 m en N, y a unos 2.100 m en S de forma discontinua, pasando a ser continua a partir de unos 2.300 m. Los espesores alcanzan los 110-150 cm en cotas medias, puntualmente más, variable según los efectos del viento.

Tendencia para las próximas 48-72h

Las placas de viento continuarán sensibles y se puede formar alguna nueva. Peligro: ESTACIONARIO.

El próximo boletín será emitido el día 2026-03-26

5 MUY FUERTE	4 FUERTE	3 NOTABLE	2 LIMITADO	1 DÉBIL

EAWS EUROPEAN AVALANCHE WARNING SERVICES

ICGC Institut Cartogràfic i Geològic de Catalunya

Servei Meteorològic de Catalunya

Boletín de peligro de aludes Perafita-Puigpedrós Del 25/03/2026 al 26/03/2026

(Válido fuera pistas de esquí y zonas no controladas)

DÉBIL (1)

Situación primaria

Nieve venteada

Distribución

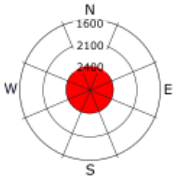

Tamaño

Origen

Tendencia

Estado del manto nivoso

El manto nivoso se encuentra bastante asentado. En umbrías de cota alta todavía encontramos superficialmente nieve seca de la última nevada, de poco grosor. Con la previsión de débiles nevadas y de la entrada de viento fuerte a partir del miércoles tarde y muy fuerte el jueves, de N, se podrán formar placas de viento en cota alta, bajo collados y crestas y sectores más resguardados, probables en cualquier orientación pero más frecuentes en orientaciones S. sensibles al paso de una persona provocando aludes a su paso, de tamaño 1, pequeño, sin capacidad de colgarla pero si derribarla. En caso de que la nevada fuera más abundante de lo previsto por los modelos, los aludes de placa podrían alcanzar tamaño 2, medio. En solanas, nos encontraremos un manto encostrado y endurecido, y habrá que tener cuidado con los resbalones.

Distribución del manto nivoso

En umbrías hay nieve por encima de unos 1.600 m y las solanas está presente por encima de unos 1.900 m. Los espesores, aunque irregulares, rondan los 70-100 cm a umbrías, a 2.300 m. Son grosores por encima de los habituales en esta época.

Tendencia para las próximas 48-72h

Las placas de viento continuarán sensibles y se puede formar alguna nueva. Peligro: ESTACIONARIO.

El próximo boletín será emitido el día 2026-03-26

5 MUY FUERTE	4 FUERTE	3 NOTABLE	2 LIMITADO	1 DÉBIL

EAWS EUROPEAN AVALANCHE WARNING SERVICES

ICGC Institut Cartogràfic i Geològic de Catalunya

Servei Meteorològic de Catalunya

Boletín de peligro de aludes
Vessant Nord Cadí-Moixeró
Del 25/03/2026 al 26/03/2026

(Válido fuera pistas de esquí y zonas no controladas)

DÉBIL (1)

Situación primaria

Nieve venteada

Distribución

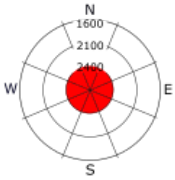

Tamaño

Origen

Tendencia

Estado del manto nivoso

El manto se ha humedecido intensamente en solanas, pero en umbrías de cota alta, superficialmente, todavía hay presencia de nieve seca, de poco grosor. A pesar de la ausencia de nevadas previstas y la baja disponibilidad de nieve movilizable, con la entrada de viento fuerte el miércoles tarde y muy fuerte el jueves, de N, se podrán formar nuevas placas de viento, locales y pequeñas, en cota alta, bajo collados y cordales, y canales y vertientes más frecuentes en este lugar. de una persona provocando aludes a su paso, de tamaño 1, pequeño, sin capacidad de colgarla pero si derribarla. Hay que prestar atención al terreno trampa, sobre todo a las canales y torrentes, donde un alud pequeño podría llegar a enterrarnos. En solanas, nos encontraremos un manto encostrado y endurecido, y habrá que tener cuidado con los resbalones.

Distribución del manto nivoso

En umbrías hay presencia discontinua de nieve por encima de unos 1.600 m y es esquiable por encima de unos 1.900 m. Los grosores están alrededor de 160-180 cm a 2.200 m. Estos valores son muy excedentarios para la época del año.

Tendencia para las próximas 48-72h

Las placas de viento continuarán sensibles y se puede formar alguna nueva. Peligro: ESTACIONARIO.

El próximo boletín será emitido el día 2026-03-26

5 MUY FUERTE	4 FUERTE	3 NOTABLE	2 LIMITADO	1 DÉBIL

EAWS EUROPEAN AVALANCHE WARNING SERVICES

ICGC Institut Cartogràfic i Geològic de Catalunya

Servei Meteorològic de Catalunya

Boletín de peligro de aludes Prepirineu
Del 25/03/2026 al 26/03/2026

(Válido fuera pistas de esquí y zonas no controladas)

DÉBIL (1).

Situación primaria

Nieve venteada	Distribución	Tamaño	Origen	Tendencia
	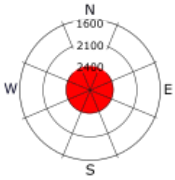			

Estado del manto nivoso

El manto nivoso se encuentra asentado y estable. A umbrías de las cotas más altas todavía se puede encontrar, localmente y de poco grosor, nieve seca superficialmente. La entrada de viento fuerte a partir del miércoles tarde, de NW, y el jueves de N, podrá formar algunas placas de viento en cota alta, bajo collados y crestas y sectores más resguardados, probables en cualquier orientación pero principalmente en orientaciones S. Con la baja disponibilidad de nieve movilizable y ausencia de nevadas, las placas de viento serán pequeñas y su paso, de tamaño 1, pequeño, sin capacidad de enterrarla pero si derribarla. En solanas, nos encontraremos un manto encostrado y endurecido, y habrá que tener cuidado con los resbalones.

Distribución del manto nivoso

En umbrías hay nieve por encima de unos 1.700 m. En solanas la nieve está presente por encima de unos 1.900 m, discontinua. Los espesores, aunque irregulares, rondan los 90-120 cm a 2.300 m.

Tendencia para las próximas 48-72h

Las placas de viento, locales y pequeñas, podrán mantenerse reactivas. Peligro: ESTACIONARIO.

El próximo boletín será emitido el día 2026-03-26

5 MUY FUERTE	4 FUERTE	3 NOTABLE	2 LIMITADO	1 DÉBIL

EAWS EUROPEAN AVALANCHE WARNING SERVICES

ICGC Institut Cartogràfic i Geològic de Catalunya

Servei Meteorològic de Catalunya

Boletín de peligro de aludes Ter-Freser Del 25/03/2026 al 26/03/2026

(Válido fuera pistas de esquí y zonas no controladas)

DÉBIL (1)

Situación primaria

Nieve venteada

Distribución

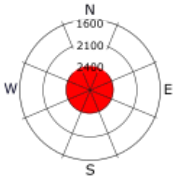

Tamaño

Origen

Tendencia

Estado del manto nivoso

El manto nivoso se encuentra bastante asentado. En umbrías de cota alta todavía encontramos superficialmente nieve seca de la última nevada, de poco grosor, y a veces en forma de facetas. Con la previsión de la entrada de viento fuerte a partir del miércoles tarde y muy fuerte el jueves, de N, se podrán formar placas de viento en cota alta, bajo collados y crestas y sectores más resguardados, probables a cualquier orientación pero más frecuentes en orientaciones S. Con la baja disponibilidad de nieve movilizable y ausencia de nevadas, las placas de viento provocando aludes a su paso, de tamaño 1, pequeño, sin capacidad de colgarla pero si derribarla. En caso de que la nevada llegara al sector, poco probable según los modelos, localmente el alud de placa podría alcanzar tamaño 2, medio. En solanas, nos encontraremos un manto encostrado y endurecido, y habrá que tener cuidado con los resbalones.

Distribución del manto nivoso

Hay nieve en el suelo por encima de unos 1.700 m. El manto es esquiable a umbrías a partir de unos 1.800 m. Los grosores son muy excedentarios para la época del año y en lugares no afectados por el viento oscilan entre 70-90 cm a unos 2.000 my más de 150 cm por encima de 2.400 m.

Tendencia para las próximas 48-72h

Las placas de viento continuarán sensibles y se puede formar alguna nueva. Peligro: ESTACIONARIO.

El próximo boletín será emitido el día 2026-03-26

5 MUY FUERTE	4 FUERTE	3 NOTABLE	2 LIMITADO	1 DÉBIL

EAWS EUROPEAN AVALANCHE WARNING SERVICES