BUTLLETÍ DEL PERILL D'ALLAUS DEL PRINCIPAT D'ANDORRA

Servei meteorològic nacional
Principat d'Andorra

Elaborat el 25/03/2026 16:35
Propera actualització 26/03/2026 a les 16h

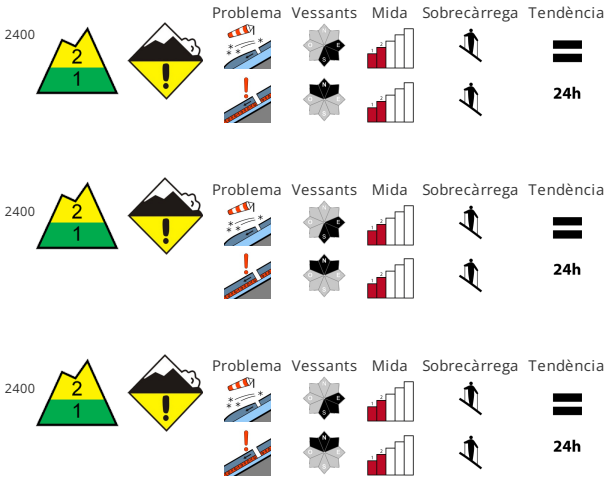

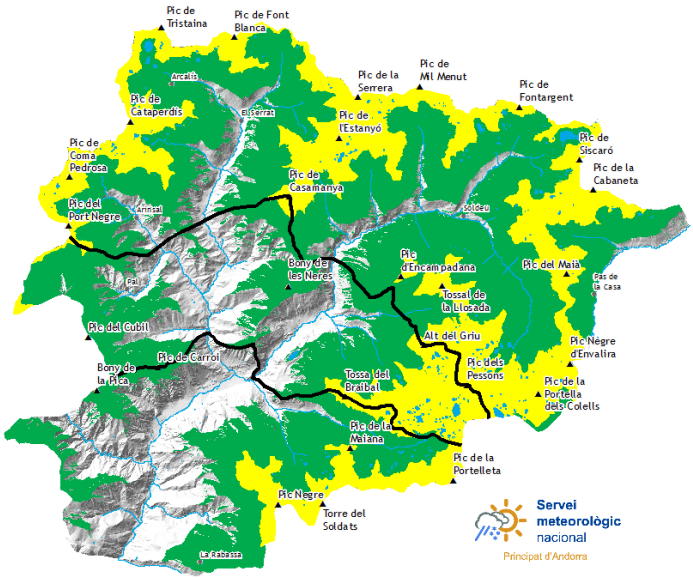

ESTABILITAT DEL MANTELL NIVAL

El vent del nord transportarà la neu recent i la neu vella. Als vessants prop de les carenes orientats a est, sud-est i sud a partir de la segona meitat de la nit les plaques de vent augmentaran de mida. Les plaques de vent noves poden ser desencadenades fàcilment i assolir mida mitjana. Encara als vessants inclinats orientats a nord-oest , nord i nord-est a la part superior del mantell de neu hi ha capes febles pronunciades. A més del perill de ser enterrat per una allau, cal tenir en compte el perill de ser arrossegat cap a una trampa del terreny.

QUALITAT DE LA NEU

Fins al divendres el vent serà localment de moderat a fort. El mantell de neu esdevindrà cada cop més extremadament variable en pocs metres de manera generalitzada. A causa de la crosta dura hi ha el perill de relliscar i caure als vessants inclinats. Prop de les carenes els gruixos de neu varien molt per la influència del vent.

GRUIXOS DEL MANTELL NIVAL FORA DE PISTA

Zona nord		Gruix neu		
Mantell Nival		1500m	2000m	2500m
N	1600 m	0 cm	150 cm	200 cm
S	1900 m	0 cm	100 cm	150 cm

Zona centre		Gruix neu		
Mantell Nival		1500m	2000m	2500m
N	1600 m	0 cm	150 cm	200 cm
S	1900 m	0 cm	100 cm	150 cm

Zona sud		Gruix neu		
Mantell Nival		1500m	2000m	2500m
N	1600 m	0 cm	120 cm	150 cm
S	1900 m	0 cm	60 cm	100 cm

Govern d'Andorra

EAWS
EUROPEAN AVALANCHE WARNING SERVICES

Aquest butlletí ha estat elaborat seguint les normes i recomanacions de l'**European Avalanche Warning Services**, del qual el **Servei meteorològic Nacional** n'és membre

BUTLLETÍ DEL PERILL D'ALLAUS DEL PRINCIPAT D'ANDORRA

Servei meteorològic nacional
Principat d'Andorra

Informació detallada per espais naturals protegits

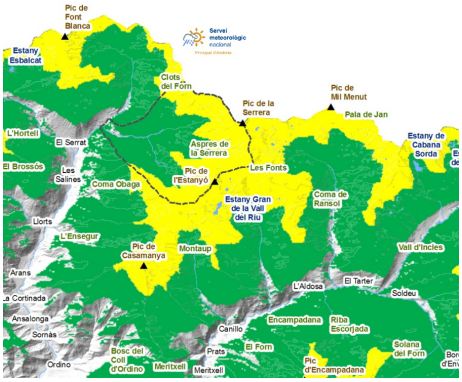

SORTENY

El vent de nord canviarà l´escenari de perill i la gestió que n´haurem de fer. Es crearan noves plaques als vessants est i sud que haurem d´evitar. A més, als vessants nord encara hi ha capes febles que poden desencadenar plaques i que ens han de fer mantenir la prudència amb la distància de seguretat.

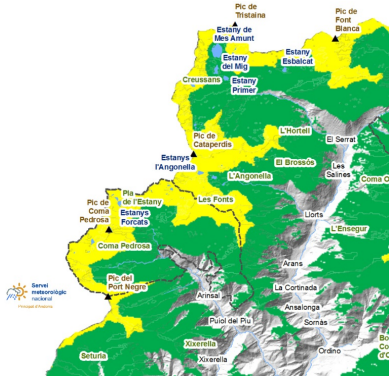

COMAPEDROSA

El vent afectarà tot el país i les plaques es formaran sobretot en altura i als vessants est i sud. Podrem distingir la neu vella de la nova pel color, i la neu vella serà més dura i regelada.

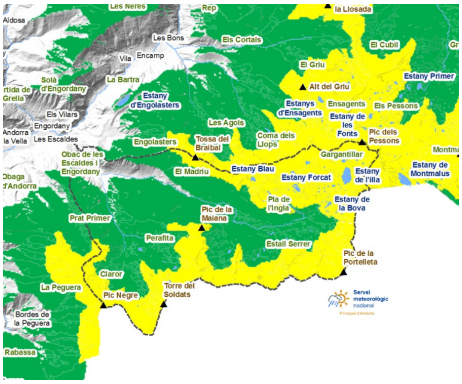

MADRIU-PERAFITA-CLAROR

Haurem d´evitar les acumulacions de neu ventada, per tant, serà més segur circular per la neu vella una mica més fosca i gelada que no pas per la neu nova. El fred dels propers dies gelarà la neu a cotes baixes i mitges.

Govern d'Andorra

EAWS
EUROPEAN AVALANCHE WARNING SERVICES

Aquest butlletí ha estat elaborat seguint les normes i recomanacions de l'**European Avalanche Warning Services**, del qual el **Servei meteorològic Nacional** n'és membre

BUTLLETÍ DEL PERILL D'ALLAUS DEL PRINCIPAT D'ANDORRA

Servei meteorològic nacional
Principat d'Andorra

Gruixos de neu nova dels darrers dies (de les últimes 24h mesurat a les 06:00h UTC)

	21/03/2026	22/03/2026	23/03/2026	24/03/2026
FEDA (Central)	0 cm	0 cm	0 cm	0 cm
Engolasters - FEDA	0 cm	0 cm	0 cm	0 cm
Bony de les Neres	0 cm	3 cm	0 cm	0 cm
Sorteny	0 cm	4 cm	0 cm	0 cm
Les Fonts d'Arinsal	0 cm	7 cm	0 cm	0 cm
Perafita	0 cm	7 cm	0 cm	0 cm
Tossa Espiolets	0 cm	3 cm	0 cm	0 cm
Grau Roig - FEDA	0 cm	7 cm	0 cm	0 cm
Fontverd	0 cm	0 cm	0 cm	0 cm
Ransol - FEDA	0 cm	2 cm	0 cm	0 cm
Caborreu	0 cm	0 cm	0 cm	0 cm
La Solana	0 cm	10 cm	0 cm	0 cm
Envalira Antenes	0 cm	6 cm	0 cm	0 cm
Vall del Riu FEDA	0 cm	5 cm	0 cm	0 cm