BUTLLETÍ DEL PERILL D'ALLAUS DEL PRINCIPAT D'ANDORRA

Elaborado el 25/03/2026 16:35
Proxima actualización 26/03/2026 a las 16h

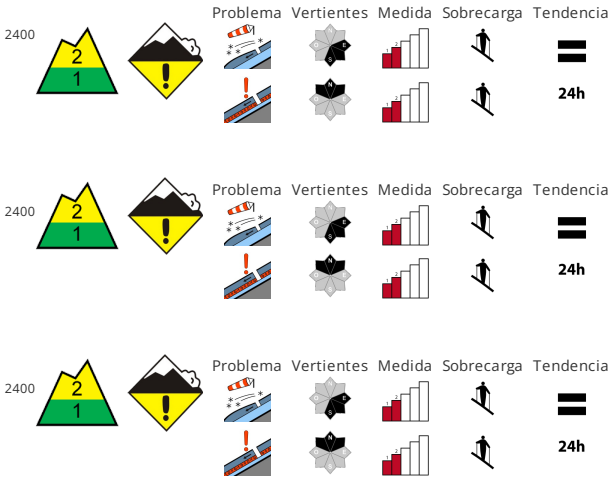

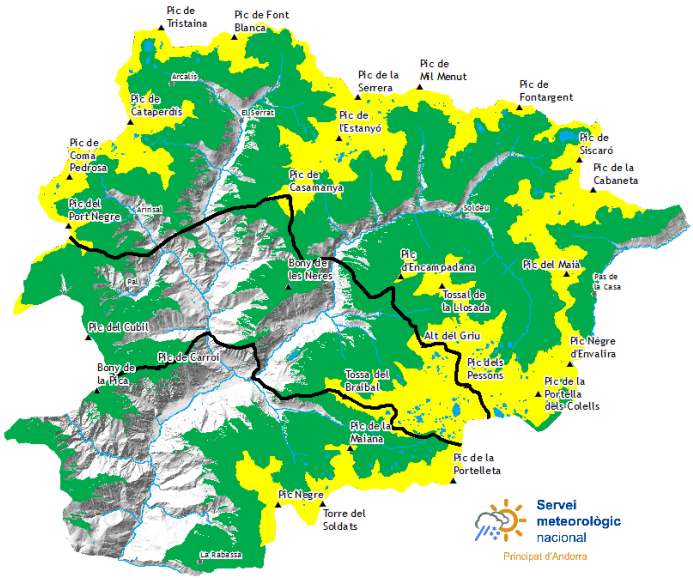

CALIDAD DE LA NIEVE

El viento del norte transportará la nieve reciente y la nieve antigua. En las laderas cercanas a los cordales orientadas a este, sudeste y sur a partir de la segunda mitad de la noche las placas de viento aumentarán de tamaño. Las placas de viento nuevas pueden ser desencadenadas fácilmente y alcanzar un tamaño mediano. Todavía en las laderas inclinadas orientadas a noroeste , norte y nordeste en la parte superior del manto de nieve hay capas débiles pronunciadas. Además del peligro de ser enterrado por un alud, se debe tener en cuenta el peligro de ser arrastrado hacia una trampa del terreno.

ESTABILIDAD DEL MANTO NIVOSO

Hasta el viernes el viento soplará localmente de moderado a fuerte. El manto de nieve se volverá cada vez más extremadamente variable en pocos metros en general. Debido a la costra dura hay el peligro de resbalar y caer en las laderas inclinadas. Cerca de los cordales los espesores de nieve varían mucho por la influencia del viento.

ESPESORES DEL MANTO NIVOSO FUERA DE PISTA

Zona norte		Espesor nieve		
Manto Nival		1500m	2000m	2500m
N	1600 m	0 cm	150 cm	200 cm
S	1900 m	0 cm	100 cm	150 cm

zona centro		Espesor nieve		
Manto Nival		1500m	2000m	2500m
N	1600 m	0 cm	150 cm	200 cm
S	1900 m	0 cm	100 cm	150 cm

Zona sur		Espesor nieve		
Manto Nival		1500m	2000m	2500m
N	1600 m	0 cm	120 cm	150 cm
S	1900 m	0 cm	60 cm	100 cm

Govern d'Andorra

EAWS EUROPEAN AVALANCHE WARNING SERVICES

Aquest butlletí ha estat elaborat seguint les normes i recomanacions de l'**European Avalanche Warning Services**, del qual el **Servei meteorològic Nacional** n'és membre

BUTLLETÍ DEL PERILL D'ALLAUS DEL PRINCIPAT D'ANDORRA

Servei meteorològic nacional
Principat d'Andorra

Información detallada por espacios naturales protegidos

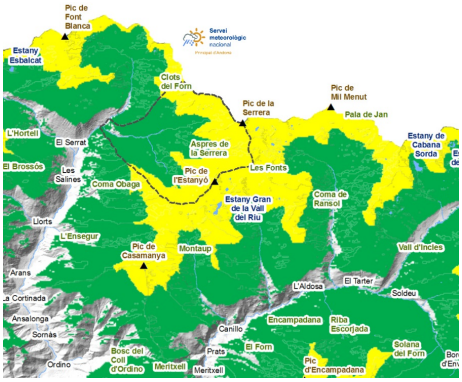

SORTENY

El viento de norte cambiará el escenario de peligro y la gestión que deberemos hacer. Se crearán nuevas placas en las vertientes este y sur que deberemos evitar. Además, en las vertientes norte todavía hay capas débiles que pueden desencadenar placas y que deben hacernos mantener la prudencia con la distancia de seguridad.

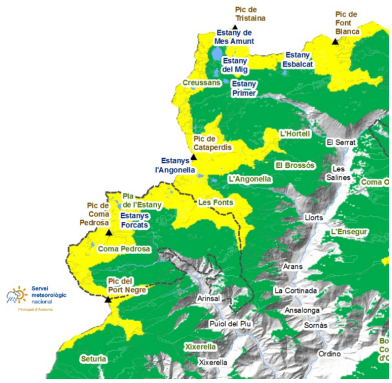

COMAPEDROSA

El viento afectará a todo el país y las placas se formarán sobre todo en altura y en las vertientes este y sur. Podremos distinguir la nieve vieja de la nueva por su color, y la nieve vieja será más dura y rehelada.

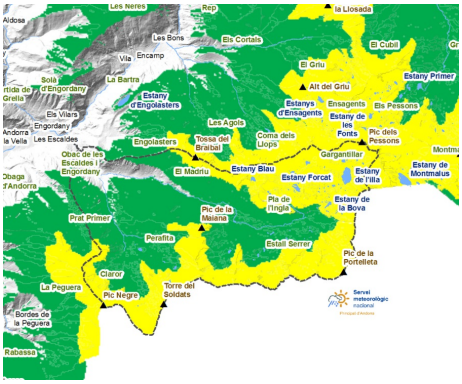

MADRIU-PERAFITA-CLAROR

Deberemos evitar las acumulaciones de nieve venteada, por tanto, será más seguro circular por la nieve vieja algo más oscura y helada que por la nieve nueva. El frío de los próximos días helará la nieve en cotas bajas y medias.

Govern d'Andorra

EAWS EUROPEAN AVALANCHE WARNING SERVICES

Aquest butlletí ha estat elaborat seguint les normes i recomanacions de l'**European Avalanche Warning Services**, del qual el **Servei meteorològic Nacional** n'és membre

BUTLLETÍ DEL PERILL D'ALLAUS DEL PRINCIPAT D'ANDORRA

Servei meteorològic nacional
Principat d'Andorra

Espesores de nieve nueva de los últimos días (de las ultimas 24h mesurado a las 06:00h UTC)

	21/03/2026	22/03/2026	23/03/2026	24/03/2026
FEDA (Central)	0 cm	0 cm	0 cm	0 cm
Engolasters - FEDA	0 cm	0 cm	0 cm	0 cm
Bony de les Neres	0 cm	3 cm	0 cm	0 cm
Sorteny	0 cm	4 cm	0 cm	0 cm
Les Fonts d'Arinsal	0 cm	7 cm	0 cm	0 cm
Perafita	0 cm	7 cm	0 cm	0 cm
Tossa Espiolets	0 cm	3 cm	0 cm	0 cm
Grau Roig - FEDA	0 cm	7 cm	0 cm	0 cm
Fontverd	0 cm	0 cm	0 cm	0 cm
Ransol - FEDA	0 cm	2 cm	0 cm	0 cm
Caborreu	0 cm	0 cm	0 cm	0 cm
La Solana	0 cm	10 cm	0 cm	0 cm
Envalira Antenes	0 cm	6 cm	0 cm	0 cm
Vall del Riu FEDA	0 cm	5 cm	0 cm	0 cm