BUTLLETÍ DEL PERILL D'ALLAUS DEL PRINCIPAT D'ANDORRA

Préparé le 25/03/2026 16:35
Prochaine mise à jour le 26/03/2026 à 16h

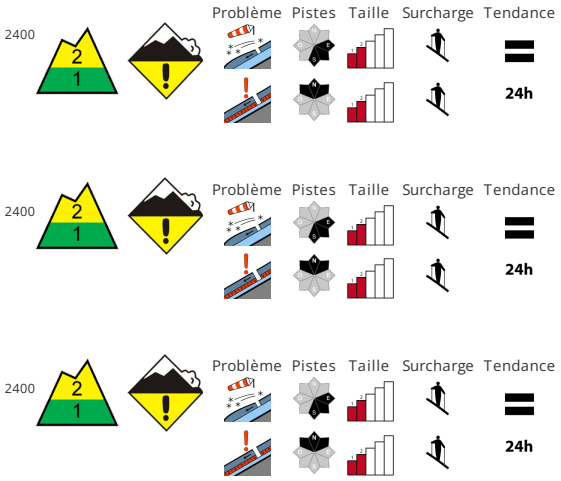

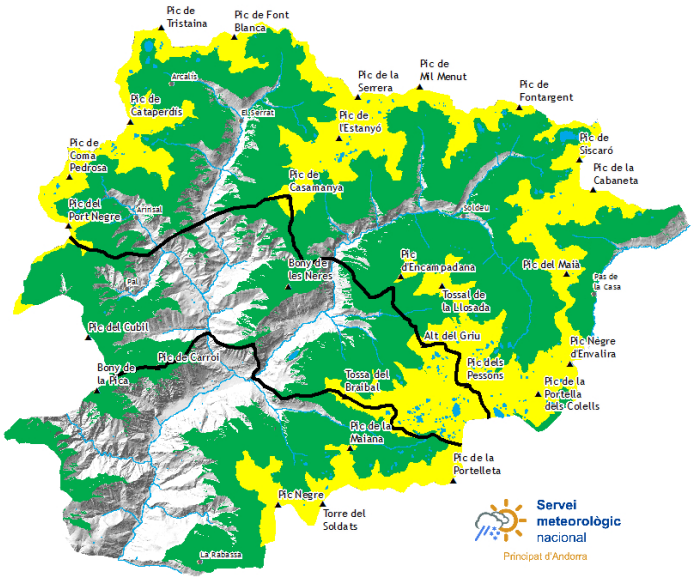

STABILITÉ DU MANTEAU NEIGEUX

Le vent du nord transporte la neige fraîche et ancienne.. À partir de la seconde moitié de nuit les accumulations de neige soufflée se développent sur les pentes proches des crêtes exposées à l'est , au sud-est et au sud. Les accumulations de neige fraîche soufflée peuvent peut être déchaîné facilement et atteindre une taille moyenne.. Dans la partie supérieure du manteau neigeux des couches fragiles importantes sont présentes ils se rencontrent , aussi sur les pentes raides exposées au nord-ouest , au nord et au nord-est. A côté du danger d'ensevelissement, il faut penser au danger d'être emporté et de chuter..

QUALITÈ DE LA NEIGE

Jusqu'à vendredi le vent soufflera localement modérément à fortement. De manière généralisée le manteau neigeux sera progressivement très variable à petite échelle.. Sur la croûte dure il existe en terrain raide un risque de chute.. À proximité des crêtes on trouve suivant l'influence du vent des hauteurs de neiges très différentes.

EPAISSEUR DE NEIGE HORS PISTE

Zone nord		Epaisseur de neige		
Nival manteau		1500m	2000m	2500m
N	1600 m	0 cm	150 cm	200 cm
S	1900 m	0 cm	100 cm	150 cm

Zone centre		Epaisseur de neige		
Nival manteau		1500m	2000m	2500m
N	1600 m	0 cm	150 cm	200 cm
S	1900 m	0 cm	100 cm	150 cm

Zone sud		Epaisseur de neige		
Nival manteau		1500m	2000m	2500m
N	1600 m	0 cm	120 cm	150 cm
S	1900 m	0 cm	60 cm	100 cm

Govern d'Andorra

EAWS EUROPEAN AVALANCHE WARNING SERVICES

Aquest butlletí ha estat elaborat seguint les normes i recomanacions de l'**European Avalanche Warning Services**, del qual el **Servei meteorològic Nacional** n'és membre

BUTLLETÍ DEL PERILL D'ALLAUS DEL PRINCIPAT D'ANDORRA

Servei meteorològic nacional
Principat d'Andorra

Des informations détaillées par espace naturel protégé

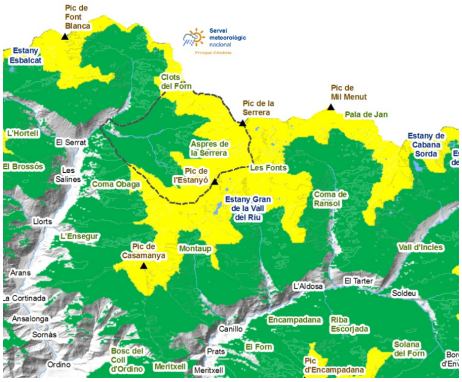

SORTENY

Le vent du nord va changer le scénario de danger et la gestion que nous devrons faire. De nouvelles plaques seront créées sur les versants Est et Sud qu'il faudra éviter. De plus, sur les versants nord, il existe encore des couches faibles qui peuvent déclencher des plaques et qui doivent nous inciter à rester prudents quant à la distance de sécurité. , , , , ,

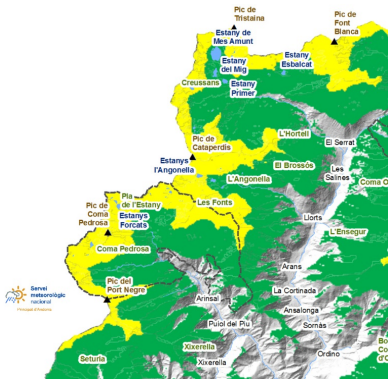

COMAPEDROSA

Le vent affectera l'ensemble du pays et les plaques se formeront principalement en altitude et sur les versants Est et Sud. Nous pourrons distinguer la vieille neige de la nouvelle par la couleur, et la vieille neige sera plus dure et gelée. , , ,

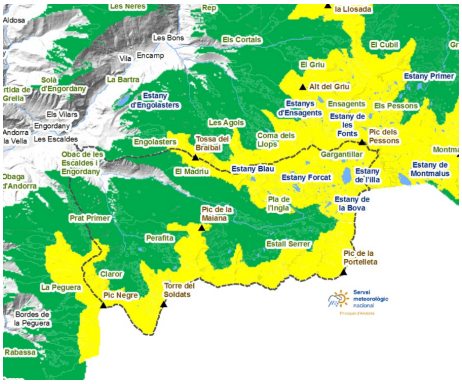

MADRIU-PERAFITA-CLAROR

Nous devrons éviter les accumulations de neige soufflée par le vent, il sera donc plus sûr de conduire sur de la vieille neige un peu plus foncée et plus froide que sur de la nouvelle neige. Le froid des prochains jours va geler la neige à basse et moyenne altitude. , , ,

Govern d'Andorra

EAWS
EUROPEAN AVALANCHE WARNING SERVICES

Aquest butlletí ha estat elaborat seguint les normes i recomanacions de l'**European Avalanche Warning Services**, del qual el **Servei meteorològic Nacional** n'és membre

BUTLLETÍ DEL PERILL D'ALLAUS DEL PRINCIPAT D'ANDORRA

Servei meteorològic nacional
Principat d'Andorra

Couche de neige fraiche des derniers jours (De 24 h mesurée à 06:00 h UTC)

	21/03/2026	22/03/2026	23/03/2026	24/03/2026
FEDA (Central)	0 cm	0 cm	0 cm	0 cm
Engolasters - FEDA	0 cm	0 cm	0 cm	0 cm
Bony de les Neres	0 cm	3 cm	0 cm	0 cm
Sorteny	0 cm	4 cm	0 cm	0 cm
Les Fonts d'Arinsal	0 cm	7 cm	0 cm	0 cm
Perafita	0 cm	7 cm	0 cm	0 cm
Tossa Espiolets	0 cm	3 cm	0 cm	0 cm
Grau Roig - FEDA	0 cm	7 cm	0 cm	0 cm
Fontverd	0 cm	0 cm	0 cm	0 cm
Ransol - FEDA	0 cm	2 cm	0 cm	0 cm
Caborreu	0 cm	0 cm	0 cm	0 cm
La Solana	0 cm	10 cm	0 cm	0 cm
Envalira Antenes	0 cm	6 cm	0 cm	0 cm
Vall del Riu FEDA	0 cm	5 cm	0 cm	0 cm