ALPI RETICHE

Bollettino Valanghe N. 386/2026 del 25/03/2026 ore 14.00
Validità 48 ore prossima emissione 26/03/2026

A cura del Servizio METEOMONT dell'ARMA dei CARABINIERI
In collaborazione con Servizio Meteorologico dell'Aeronautica militare

SITUAZIONE alle 14:00 del 25/03/2026

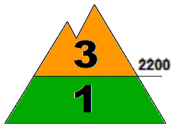

SITUAZIONE TIPO: passaggio da poca a molta neve.

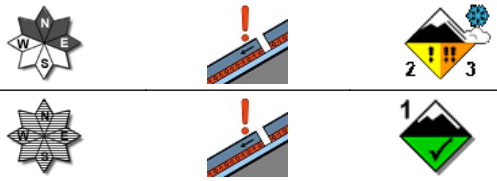

SITUAZIONE TIPO: passaggio da poca a molta neve.

Quota neve (mslm)	Nord	Sud
	1500 - 1600	2000 - 2100

Altezza Neve (cm)	Neve al suolo	Neve Fresca	Quota (mslm)
	72	0	2582
	31	0	1640

VALANGHE OSSERVATE: Alcune valanghe di medie dimensioni, Valanghe di neve a debole coesione di superficie.

PREVISIONI 26/03/2026

GRADO DI PERICOLO: MARCATO 3

SITUAZIONE TIPO: neve a debole coesione e vento.

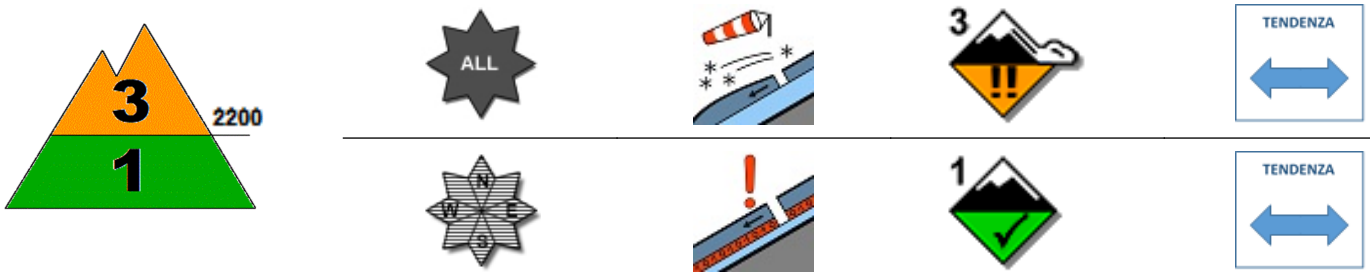

SITUAZIONE TIPO: passaggio da poca a molta neve.

MANTO NEVOSO: La stabilità del manto nevoso è molto scarsa su alcuni punti (aree) per tutte le esposizioni al di sopra di 2200 mslm, possibili valanghe di dimensioni medie.
La stabilità del manto nevoso è discreta su pochi punti (aree) per isolati pendii al di sotto di 2200 mslm, possibili valanghe di dimensioni medie.

AVVERTENZE

A seguito dell'attività eolica prevista sono da evitare le zone di accumulo, conche, canaloni, cambi di pendenza e pendii sotto vento in genere.

SCALA EUROPEA DEL GRADO DI PERICOLO VALANGHE

LEGENDA PROBLEMA

Bollettino realizzato su scala sinottica-regionale (standard EAWS). La sua valutazione non può escludere in alcun modo la necessità di una seria e capace valutazione locale del pericolo (singolo pendio) che può essere anche sensibilmente diverso. Le previsioni meteorologiche sono relative all'orario UTC (per l'Italia +1 in inverno e +2 in estate).

MINISTERO DELLA DIFESA

meteomont
Servizio Nazionale di previsione neve e valanghe

EAWS EUROPEAN AVALANCHE WARNING SERVICES

CARABINIERI

ALPI RETICHE

PREVISIONE METEO

Quota		26/03/2026 h6:00	26/03/2026 h12:00	26/03/2026 h18:00
1000	Venti	09 Nodi da Nord	08 Nodi da Nord	08 Nodi da Nord
	Temperature	-08 °C	-07 °C	-09 °C
	Temp.percepita	-15 °C	-13 °C	-15 °C
2000	Venti	09 Nodi da Nord	08 Nodi da Nord	08 Nodi da Nord
	Temperature	-08 °C	-07 °C	-09 °C
	Temp.percepita	-15 °C	-13 °C	-15 °C
3000	Venti	33 Nodi da Nord	29 Nodi da Nord	31 Nodi da Nord
	Temperature	-15 °C	-15 °C	-15 °C
	Temp.percepita	-30 °C	-29 °C	-29 °C
Zero termico		0700-0900 m.	0800-1000 m.	0600-0800 m.
Fenomeno				—
Stato del cielo				

LEGENDA FENOMENI

— Assenza Fenomeni · Nebbia · Foschia · Pioggia debole · Pioggia moderata · Pioggia forte · Temporali

Nevicata debole · Nevicata moderata · Nevicata forte

STATO DEL CIELO

Sereno · Poco nuvoloso · Nuvoloso · Molto nuvoloso · Coperto

Parametri meteonivometrici registrati presso i campi di rilevamento il 25/03/2026.

Località	Comune	Quota (m.s.l.m.)	Altezza neve (cm)	Neve caduta nelle 24 ore (cm)	Temp. Min (°C)	Temp. Max (°C)	Condizioni del tempo
VALAR	Valdidentro (SO)	1930	68	0	-7	+7	Assenza di precipitazioni
DOSSO DEL VALLONE	Valfurva (SO)	2582	72	0	-5	+2	Assenza di precipitazioni
ALPE PALU'	Chiesa in Valmalenco (SO)	2010	70	0	-5	+6	Assenza di precipitazioni
PREDA	Edolo (BS)	1580	0	0	N.P.	N.P.	Assenza di precipitazioni
COLONIA VIGILI	Ponte di Legno (BS)	1640	31	0	-5	+10	Assenza di precipitazioni
SAN COLOMBANO *	Valdisotto (SO)	2387	86	0	N.P.	N.P.	Assenza di precipitazioni
VEDRETTA DEL PISGANA *	Ponte di Legno (BS)	3030	350	0	N.P.	N.P.	Assenza di precipitazioni

(*) Rilievi fuori campo

L'INFORMAZIONE E' PREVENZIONE - LEGGI L'ATTUALE GRADO DI PERICOLO VALANGHE!

IL CAPO DEL CENTRO NAZIONALE METEOMONT
(Ten. Col. RFI Emanuela Gini)
FIRMA AUTOGRAFA OMESSA AI SENSI
DELL'ART.3 DEL D.LGS N.39/1993

Bollettino realizzato su scala sinottica-regionale (standard EAWS). La sua valutazione non può escludere in alcun modo la necessità di una seria e capace valutazione locale del pericolo (singolo pendio) che può essere anche sensibilmente diverso. Le previsioni meteorologiche sono relative all'orario UTC (per l'Italia +1 in inverno e +2 in estate).