Bulletin d'estimation du risque d'avalanche

(valable en dehors des pistes balisées et ouvertes)

MASSIF : Aure Louron

Rédigé le mercredi 25 mars 2026 à 16h

Estimation des risques pour le : JEUDI 26 MARS

FROID, FAIBLES CHUTES DE NEIGE, VENT DE NORD;

2

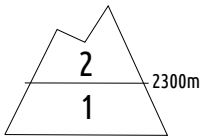

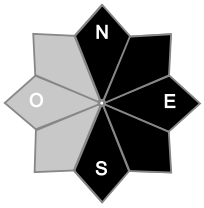

Au-dessus de 2300m indice de risque limité, plus bas indice faible.

Départs spontanés : rares, en neige récente.

Déclenchements provoqués : petites plaques instables en formation, couche fragile persistante.

Indices de risque : 5 très fort - 4 fort - 3 marqué - 2 limité - 1 faible -- En noir : les pentes les plus dangereuses

Stabilité du manteau neigeux

Situation avalancheuse typique : neige ventée couche fragile persistante

Déclenchements provoqués : possibles par **faible sollicitation au-dessus de 2300m**.
Les **chutes de neige** attendues, **faibles** en quantités, sont accompagnées de **vent de nord soutenu** : formation de **plaques peu épaisses et sensibles au passage d'un skieur ou randonneur**, bien frittées et identifiables en secteur Nord, plus meuble et d'aspect poudreux partout ailleurs à l'abri du vent (du Nord-Est au Sud).
- **au-dessus de 2000m**, les premières chutes dans la nuit de mercredi à jeudi se font sous un vent irrégulier, constituant une **petite couche plus fragile** pour les **chutes plus ventées de la journée de jeudi** : **avalanches de petite taille possibles**,
- **au-dessus de 2300m**, dans les **pentes Nord raides** puis **au-dessus de 2500m dans un secteur un peu plus large Nord à Nord-Est** où l'humidification a été moindre et plus superficielle, ces **nouvelles plaques peu épaisses** et **facilement déclenchables** se forment sur de **plus anciennes** reposant sur une **couche fragile persistante** mais **enfouie**, plus **difficiles à déclencher** : avalanches **petites à moyennes possibles par sollicitations un peu plus importantes**,
- **au-dessus de 2300m** dans les secteurs **Est à Sud**, **plaques peu épaisses mais fragiles** reposant sur un **manteau regelé, durci et stable** : **coulées ou petites avalanches** seulement possibles dans cette neige récente ventée.

Départs spontanés : **rares**, en **départs ponctuels dans les pentes raides à l'abri du vent** de nord-ouest à nord où se font de **petites accumulations au cours de la journée**.

Autres : peu de neige fraîche sur un manteau neigeux regelé, dur et glissant sous 2200m. Refroidissement éolien important.

Qualité de la neige

Enneigement : correct pour la saison au-dessus de 2000m, mais restant assez maigre en versants exposés au vent d'ouest. Maigre et hétérogène plus bas, débutant entre 1500 et 1600m en Nord, mais skiable à partir de 1700m, plutôt 1900m en Sud.
État de la neige : au petit matin, un peu de neige fraîche légère posée sur un manteau regelé, dur et glissant. Au fil de la journée, quelques centimètres de neige fraîche supplémentaires, de plus en plus travaillée par le vent en gagnant en altitude.

Aperçu météo pour le jeudi 26 mars

	nuit	matin	après-midi	soir
	Temps froid, averses de neige, vent de nord soutenu.			
Pluie-Neige	700 m	900 m	1 000 m	700 m
Iso 0 °C	1 000 m	1 200 m	1 300 m	1 000 m
Vent 1500 m	35 km/h	30 km/h	25 km/h	30 km/h
Vent 3000 m	90 km/h	80 km/h	75 km/h	80 km/h

Épaisseur de neige hors-piste

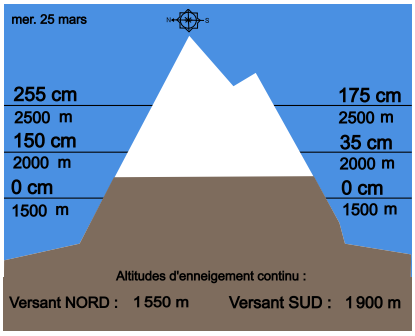

Précipitations à 1800 m

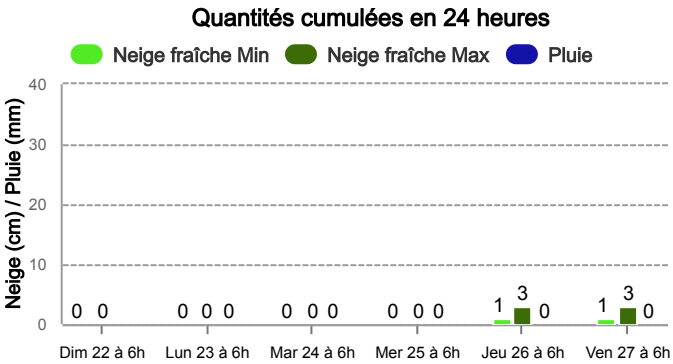

Tendance du vendredi 27 mars

2 **Indice de risque limité**

Temps froid mais plus sec alternant entre nuages et éclaircies : le risque restera limité.

Pour consulter la vigilance en cours, veuillez vous rendre sur le site https://vigilance.meteofrance.fr/fr

Météo-France - 73 avenue de Paris, 94165 Saint-Mandé cedex - Contact : contact@meteo.fr

Rédigé par Météo-France avec la contribution des observateurs du réseau nivo-météorologiques. Partenariat : ANMSM (Maires de Stations de Montagne), DSF (Domaines Skiables de France), ADSP (Directeurs de Pistes et de la Sécurité des Stations de Sports d'Hiver) et autres acteurs de la montagne.

Bulletin neige & avalanches par téléphone au 0 892 68 10 20 Service 0,35 € / min + prix appel

RÉPUBLIQUE FRANÇAISE
Liberté Égalité Fraternité

METEO FRANCE
À VOS CÔTÉS, DANS UN CLIMAT QUI CHANGE

Bulletin d'estimation du risque d'avalanche

(valable en dehors des pistes balisées et ouvertes)

MASSIF : Aure Louron

Rédigé le mercredi 25 mars 2026 à 16h

Conditions nivo-météo des 7 derniers jours

	jeu. 19/03				ven. 20/03				sam. 21/03				dim. 22/03				lun. 23/03				mar. 24/03				mer. 25/03			
	03h	09h	15h	21h	03h	09h	15h	21h	03h	09h	15h	21h	03h	09h	15h	21h	03h	09h	15h	21h	03h	09h	15h	21h	03h	09h	15h	21h
Météo																												
Vent (km/h)	30	25	20	20	25	25	20	15	10	10	15	15	30	30	50	55	50	40	30	25	35	20	20	60	70	70	75	80
à 3000m																												
Vent (km/h)	15	15	15	10	10	10	5	5	5	5	10	5	5	10	30	25	20	10	15	10	5	5	10	10	10	20	25	25
à 1500m																												

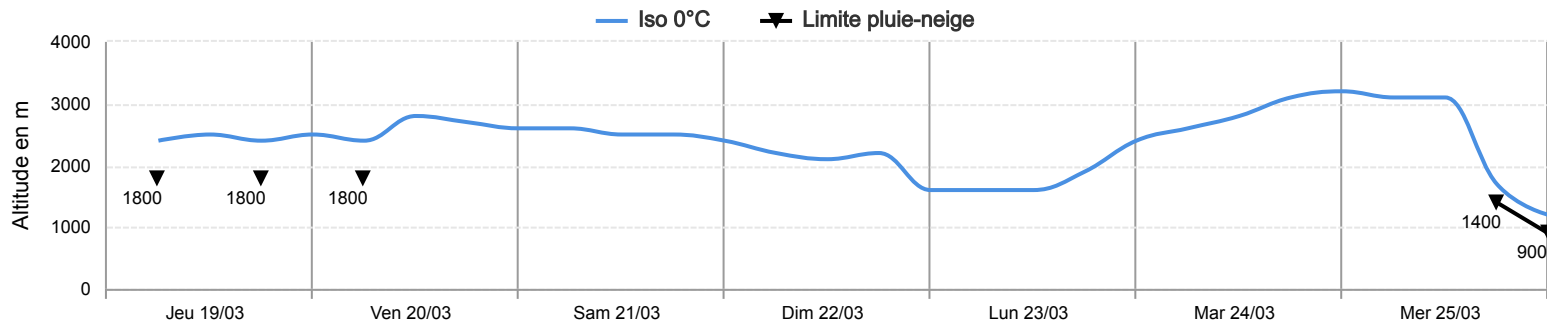

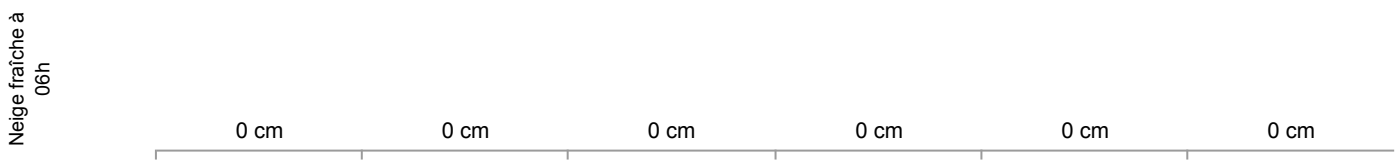

Risque d'avalanche	jeu. 19/03	ven. 20/03	sam. 21/03	dim. 22/03	lun. 23/03	mar. 24/03	mer. 25/03
	2	2	2	2	2	2	2

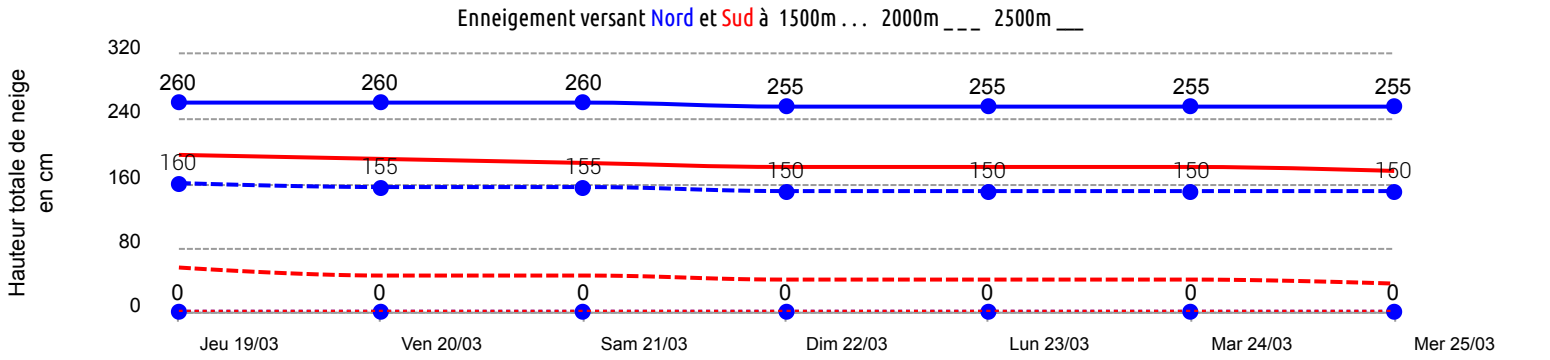

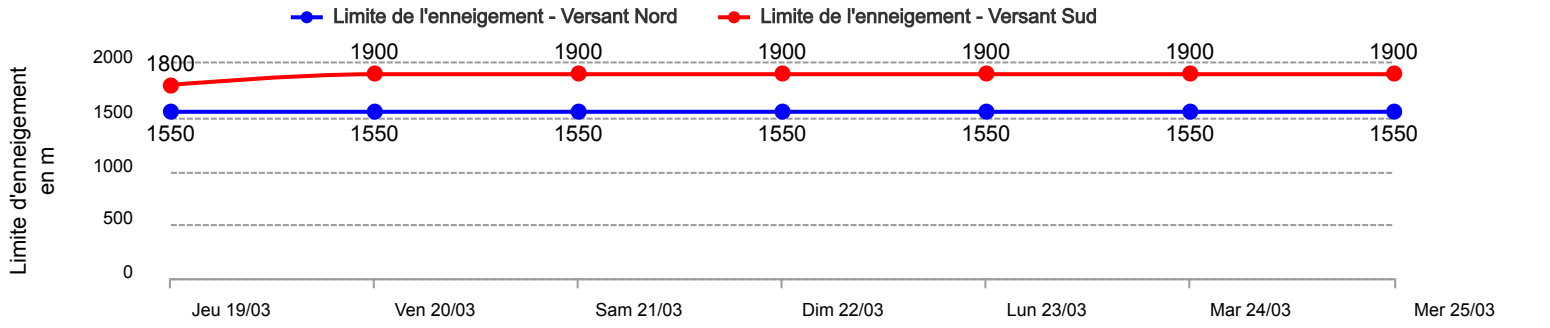

Pour consulter la vigilance en cours, veuillez vous rendre sur le site https://vigilance.meteofrance.fr/fr

Météo-France - 73 avenue de Paris, 94165 Saint-Mandé cedex - Contact : contact@meteo.fr

Bulletin neige & avalanches par téléphone au

0 892 68 10 20 Service 0,35 € / min + prix appel

Rédigé par Météo-France avec la contribution des observateurs du réseau nivo-météorologiques. Partenariat : ANMSM (Maires de Stations de Montagne), DSF (Domaines Skiables de France), ADSP (Directeurs de Pistes et de la Sécurité des Stations de Sports d'Hiver) et autres acteurs de la montagne.