Bulletin d'estimation du risque d'avalanche

(valable en dehors des pistes balisées et ouvertes)

MASSIF : Bauges

Rédigé le mercredi 25 mars 2026 à 16h

Estimation des risques pour le : JEUDI 26 MARS

RETOUR DE L'HIVER

3

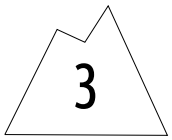

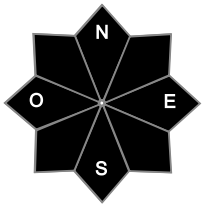

Indice de risque marqué.

Départs spontanés : en neige fraiche

Déclenchements provoqués : nombreuses plaques dans la neige fraîche

Indices de risque : 5 très fort - 4 fort - 3 marqué - 2 limité - 1 faible -- En noir : les pentes les plus dangereuses

Stabilité du manteau neigeux

Situation avalancheuse typique : neige fraîche

Déclenchements provoqués :

Plaques dans la neige fraîche, tous les versants et particulièrement au-dessus de 2000 m. **Facile à déclencher.** La taille des plaques augmente au fil des chutes de neige. Taille 2 (moyenne).

Facteur aggravant : accumulations de neige formées par le fort vent d'ouest puis nord, zones propices aux plaques.

Départs spontanés :

Avalanches de neige fraîche, rares dans la nuit de mercredi à jeudi, **plus nombreuses au fil des chutes de neige** de jeudi. Taille 2 (moyenne).

Qualité de la neige

Enneigement :

Pour la saison, l'enneigement est correct.

Jeudi matin, faible enneigement dès 800 m. Néanmoins, on retrouve un manteau neigeux skiable vers 1200/1300 m en nord et 1500/1600 m en sud.

Formation de corniches dans la nuit et en journée.

Qualité de la neige ce jeudi matin :

Vers 1800/2000 m, 15/20 cm de neige fraîche ventée reposant :

* en sud et en dessous de 2000 m en nord, sur un fond dur (croûte de regel)
* en nord au-dessus de 2000 m, sur 10/15 cm de vielle neige froide ventée

Aperçu météo pour le jeudi 26 mars

Nombreuses averses de neige le matin, plus espacées l'après-midi avec de rares trouées. En soirée, 20/30 cm de neige fraîche au-dessus de 2000 m.

	nuit	matin	après-midi	soir
Pluie-Neige	300 m	400 m	500 m	300 m
Iso 0 °C	500 m	700 m	1 000 m	600 m
Vent 1500 m	↘ 50 km/h	↓ 45 km/h	↓ 40 km/h	↓ 50 km/h
Vent 2000 m	↘ 60 km/h	↓ 60 km/h	↓ 50 km/h	↓ 60 km/h

Épaisseur de neige hors-piste

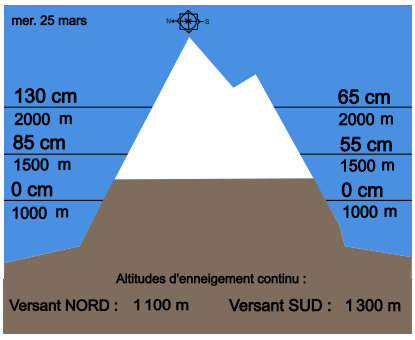

Précipitations à 1800 m

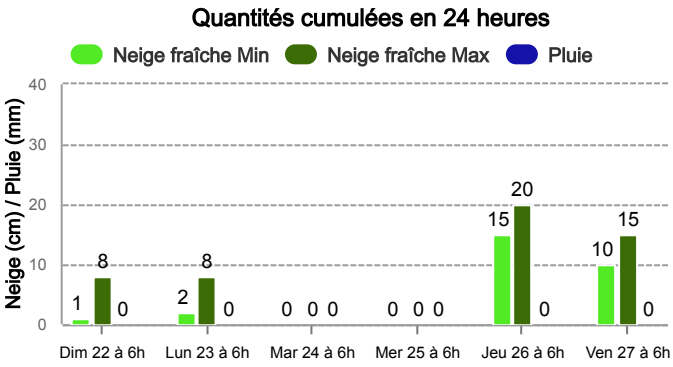

Tendance du vendredi 27 mars

3 **Indice de risque marqué**

Les chutes de neige cessent en fin de nuit de jeudi à vendredi (3/5 cm). Amélioration au fil de la journée de vendredi.

⇒ nombreuses plaques dans la neige fraîche. Encore quelques départs spontanés dans la nuit de jeudi à vendredi.

Pour consulter la vigilance en cours, veuillez vous rendre sur le site https://vigilance.meteofrance.fr/fr

Météo-France - 73 avenue de Paris, 94165 Saint-Mandé cedex - Contact : contact@meteo.fr

Rédigé par Météo-France avec la contribution des observateurs du réseau nivo-météorologiques. Partenariat : ANMSM (Maires de Stations de Montagne), DSF (Domaines Skiables de France), ADSP (Directeurs de Pistes et de la Sécurité des Stations de Sports d'Hiver) et autres acteurs de la montagne.

Bulletin neige & avalanches par téléphone au 0 892 68 10 20 Service 0,35 € / min + prix appel

RÉPUBLIQUE FRANÇAISE
Liberté Égalité Fraternité

METEO FRANCE
À VOS CÔTÉS, DANS UN CLIMAT QUI CHANGE

Bulletin d'estimation du risque d'avalanche

(valable en dehors des pistes balisées et ouvertes)

MASSIF : Bauges

Rédigé le mercredi 25 mars 2026 à 16h

Conditions nivo-météo des 7 derniers jours

	jeu. 19/03				ven. 20/03				sam. 21/03				dim. 22/03				lun. 23/03				mar. 24/03				mer. 25/03			
	03h	09h	15h	21h	03h	09h	15h	21h	03h	09h	15h	21h	03h	09h	15h	21h	03h	09h	15h	21h	03h	09h	15h	21h	03h	09h	15h	21h
Météo																												
Vent (km/h)	40	20	20	20	15	10	5	5	5	10	10	10	20	25	35	10	20	20	25	30	15	10	10	10	25	40	60	60
à 2000m																												
Vent (km/h)	35	15	20	10	5	5	0	0	0	5	5	5	10	15	20	5	10	15	20	25	10	5	5	5	15	30	50	50
à 1500m																												

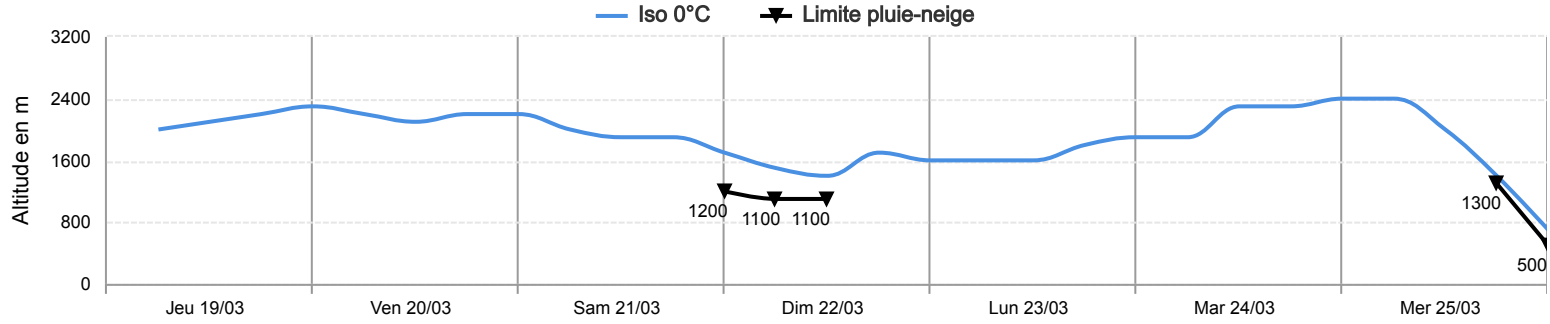

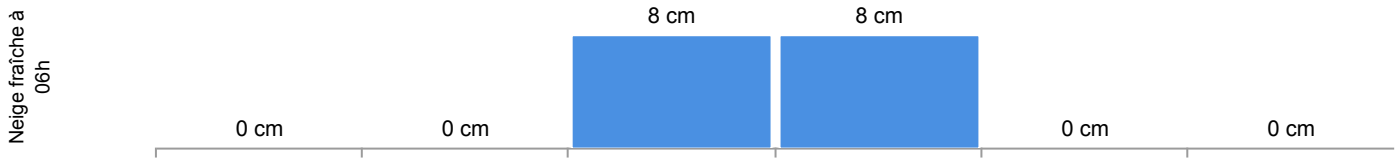

Risque d'avalanche	jeu. 19/03	ven. 20/03	sam. 21/03	dim. 22/03	lun. 23/03	mar. 24/03	mer. 25/03
	2	2	1	2	2	2	2

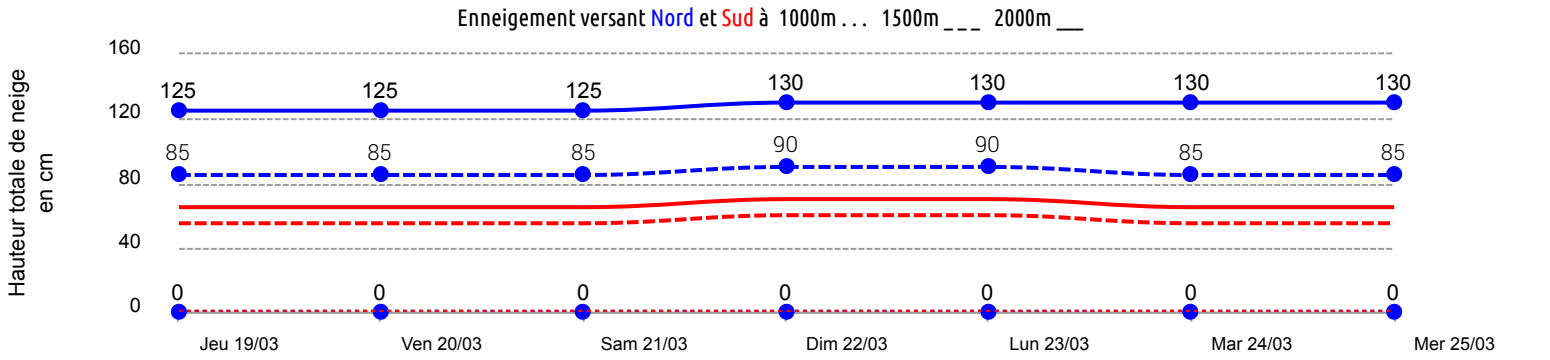

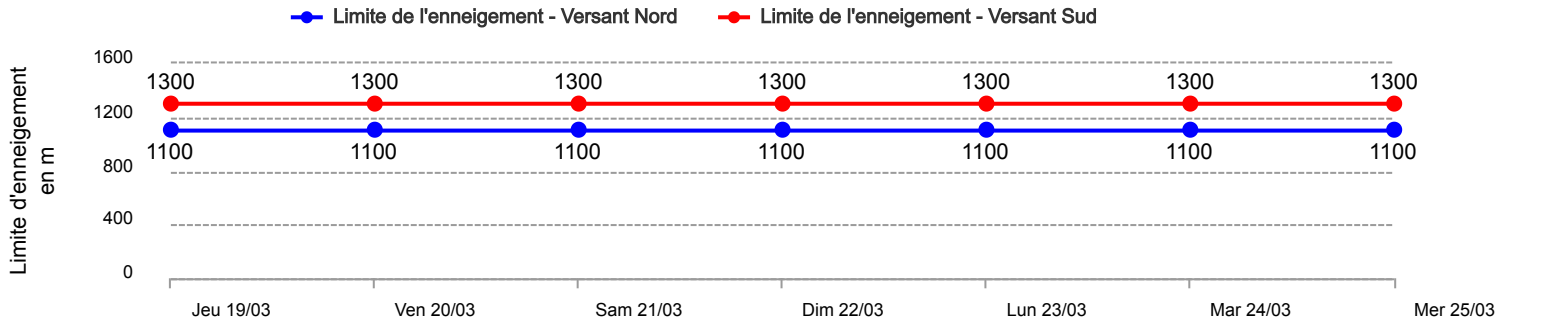

Pour consulter la vigilance en cours, veuillez vous rendre sur le site https://vigilance.meteofrance.fr/fr

Météo-France - 73 avenue de Paris, 94165 Saint-Mandé cedex - Contact : contact@meteo.fr

Rédigé par Météo-France avec la contribution des observateurs du réseau nivo-météorologiques. Partenariat : ANMSM (Maires de Stations de Montagne), DSF (Domaines Skiables de France), ADSP (Directeurs de Pistes et de la Sécurité des Stations de Sports d'Hiver) et autres acteurs de la montagne.

Bulletin neige & avalanches par téléphone au
0 892 68 10 20
Service 0,35 € / min + prix appel