Bulletin d'estimation du risque d'avalanche

(valable en dehors des pistes balisées et ouvertes)

MASSIF : Cerdagne Canigou

Rédigé le mercredi 25 mars 2026 à 16h

Estimation des risques pour le : JEUDI 26 MARS

TRÈS HIVERNAL EN ALTITUDE, QUELQUES PLAQUES À VENT ANCIENNES PRÈS DES SOMMETS.

2

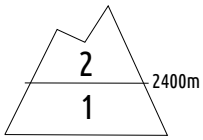

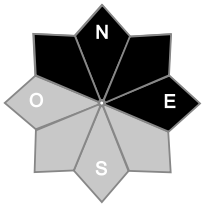

Au-dessus de 2400m indice de risque limité, plus bas indice faible.

Départs spontanés : Rares. Petits départs naturels de poudreuse en couloirs très raides.

Déclenchements provoqués : Anciennes plaques en versants nord sur sous-couches fragiles persistantes.

Indices de risque : 5 très fort - 4 fort - 3 marqué - 2 limité - 1 faible -- En noir : les pentes les plus dangereuses

Stabilité du manteau neigeux

Situation avalancheuse typique : couche fragile persistante — pas de situation prédominante

Déclenchements provoqués :

- Quelques structures de plaques remontant à plus d'une semaine sont possiblement présentes au-delà de 2400/2500 m, reposant sur des couches fragiles persistantes (givres de surface ou neige roulée).

Bien qu'assez ancienne, ces structures sont encore potentiellement bien réactives.

Elles sont localisées dans les pentes sommitales des sommets frontaliers dans un large secteur nord et peuvent être masquées par les petites chutes de neige de la nuit précédente. Elles donnent des avalanches de taille 1 à 2, avec des cassures de 40/50 cm éventuellement possibles.

La quantité de neige mobilisable peut être aggravé par le fort vent de nord-ouest attendu ces prochaines heures.

Observables : neige récente travaillée par le vent, enfoncement des bâtons supérieur à 20/30 cm, fissures devant les skis.

Départs spontanés :

Avec le net refroidissement effectif depuis la nuit précédente, l'activité avalancheuse s'annonce faible. Éventuellement quelques petites avalanches ou coulées mobilisant les 10/15 cm de neige récente accumulés dans des couloirs très raides.

Qualité de la neige

Enneigement :

L'enneigement reste excellent pour la saison, après plusieurs hivers déficitaires.

En altitude, les cumuls sont très conséquents, mais les crêtes et sommets exposés au vent d'ouest à nord-ouest sont parfois complètement déneigés.

On peut encore chausser les skis dans les secteurs ombragés au mieux vers 1700/1800 m.

Qualité de la neige :

- Avec le fort refroidissement, bon regel de l'ancien manteau neigeux perdurant toute la journée dans les secteurs protégés des quelques rayons de soleil. Neige très dure, voire glacée dans les secteurs balayés par le vent, éventuellement saupoudrés par 1 ou 2 centimètres de neige récente vers le Puigmal ou le Cambre.

Aperçu météo pour le jeudi 26 mars

nuit	matin	après-midi	soir

Encore quelques averses de neige en matinée. Du mieux l'après-midi.

Pluie-Neige				
Iso 0 °C	2 000 m	1 700 m	1 900 m	1 600 m
Vent 2000 m	65 km/h	85 km/h	80 km/h	80 km/h
Vent 3000 m	100 km/h	115 km/h	110 km/h	105 km/h

Épaisseur de neige hors-piste

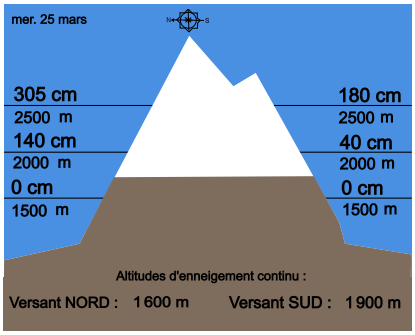

Précipitations à 1800 m

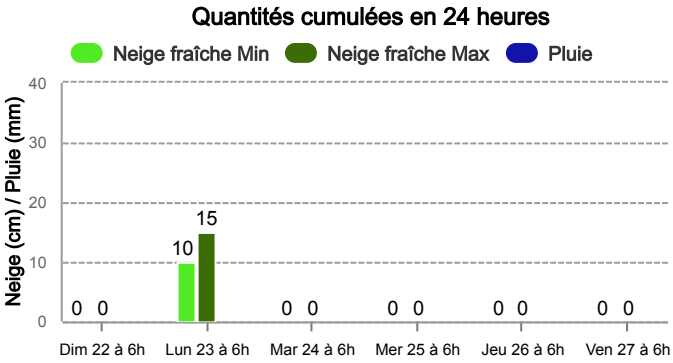

Tendance du vendredi 27 mars

2

Indice de risque limité

Risque stationnaire.

Pour consulter la vigilance en cours, veuillez vous rendre sur le site https://vigilance.meteofrance.fr/fr

Météo-France - 73 avenue de Paris, 94165 Saint-Mandé cedex - Contact : contact@meteo.fr

Rédigé par Météo-France avec la contribution des observateurs du réseau nivo-météorologiques. Partenariat : ANMSM (Maires de Stations de Montagne), DSF (Domaines Skiables de France), ADSP (Directeurs de Pistes et de la Sécurité des Stations de Sports d'Hiver) et autres acteurs de la montagne.

Bulletin neige & avalanches par téléphone au 0 892 68 10 20 Service 0,35 € / min + prix appel

RÉPUBLIQUE FRANÇAISE
Liberté Égalité Fraternité

METEO FRANCE
À VOS CÔTÉS, DANS UN CLIMAT QUI CHANGE

Bulletin d'estimation du risque d'avalanche

(valable en dehors des pistes balisées et ouvertes)

MASSIF : Cerdagne Canigou

Rédigé le mercredi 25 mars 2026 à 16h

Conditions nivo-météo des 7 derniers jours

	jeu. 19/03				ven. 20/03				sam. 21/03				dim. 22/03				lun. 23/03				mar. 24/03				mer. 25/03			
	03h	09h	15h	21h	03h	09h	15h	21h	03h	09h	15h	21h	03h	09h	15h	21h	03h	09h	15h	21h	03h	09h	15h	21h	03h	09h	15h	21h
Météo																												
Vent (km/h)	35	35	30	25	20	20	20	25	15	15	20	20	25	25	35	45	50	50	40	30	25	20	20	20	25	35	40	70
à 3000m	↓	↖	↖	↙	↙	↙	←	↓	↓	↙	↘	↘	↘	→	↓	↓	↓	↓	↓	↓	↘	↘	↑	↘	→	↙	↘	↘
Vent (km/h)	25	25	20	10	10	10	10	10	10	10	15	10	15	15	25	35	35	35	30	20	15	10	10	10	15	20	30	45
à 2000m	↑	↖	↑	↙	↙	↙	←	↓	↓	↙	↘	↘	↙	↘	↓	↓	↓	↓	↘	↘	↘	↙	↗	↘	↘	↓	↘	↘

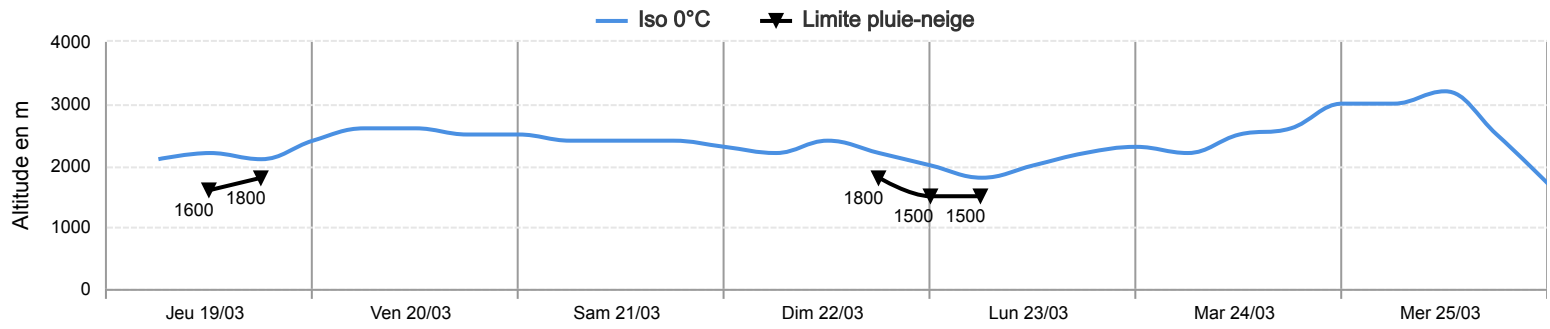

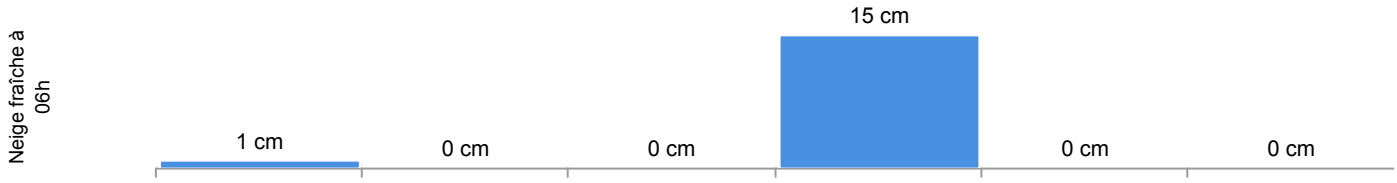

Risque d'avalanche	jeu. 19/03	ven. 20/03	sam. 21/03	dim. 22/03	lun. 23/03	mar. 24/03	mer. 25/03
	2	2	2	2	2	2	2

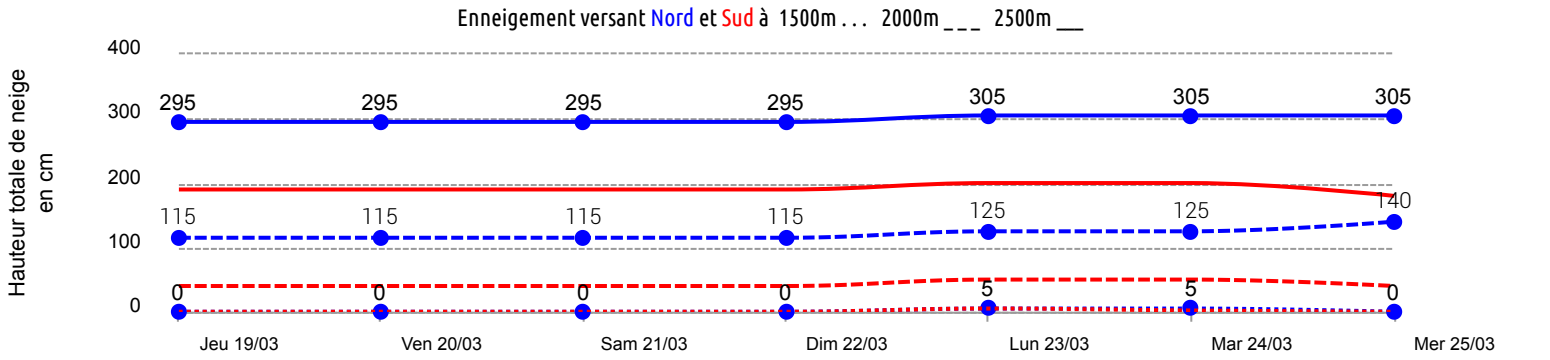

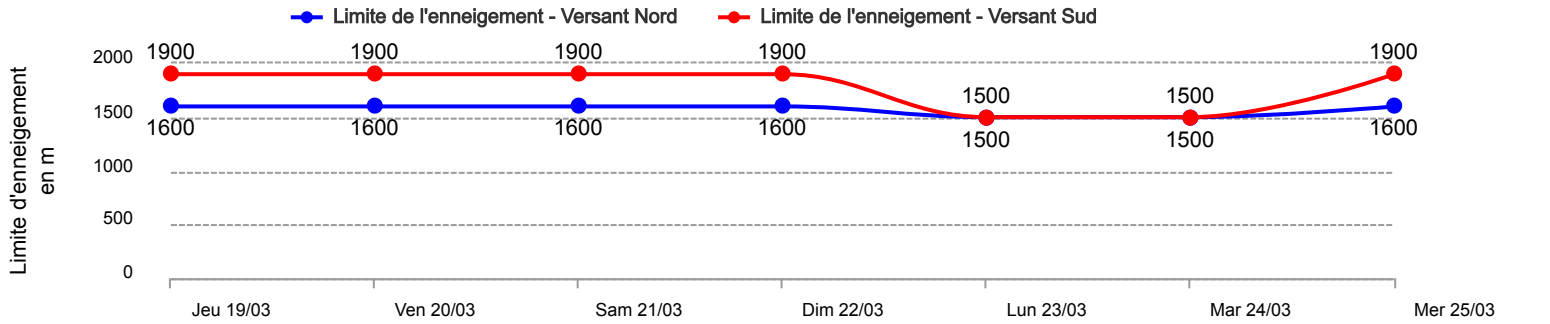

Pour consulter la vigilance en cours, veuillez vous rendre sur le site https://vigilance.meteofrance.fr/fr

Météo-France - 73 avenue de Paris, 94165 Saint-Mandé cedex - Contact : contact@meteo.fr

Rédigé par Météo-France avec la contribution des observateurs du réseau nivo-météorologiques. Partenariat : ANMSM (Maires de Stations de Montagne), DSF (Domaines Skiables de France), ADSP (Directeurs de Pistes et de la Sécurité des Stations de Sports d'Hiver) et autres acteurs de la montagne.

Bulletin neige & avalanches par téléphone au
0 892 68 10 20 Service 0,35 € / min + prix appel