# Bulletin d'estimation du risque d'avalanche
(valable en dehors des pistes balisées et ouvertes)

# MASSIF : Cinto Rotondo

Rédigé le mercredi 25 mars 2026 à 16h

## Estimation des risques pour le : JEUDI 26 MARS

**PERSISTANCE D'INSTABILITÉS EN ALTITUDE DANS LA NEIGE RÉCENTE VENTÉE**

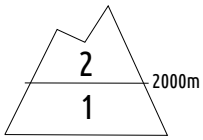


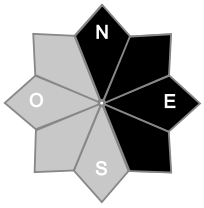


Au-dessus de 2000m indice de risque limité, plus bas indice faible.

**Départs spontanés :** Peu probables

**Déclenchements provoqués :** Plaques à vent difficilement sollicitables, encore présentes en altitude au-dessus de 2000 m

Indices de risque : 5 très fort - 4 fort - 3 marqué - 2 limité - 1 faible -- En noir : les pentes les plus dangereuses

## Stabilité du manteau neigeux

**Situation avalancheuse typique :** neige ventée

**Déclenchements provoqués :** De rares plaques sont encore en place en altitude dans les pentes Nord à Est, au-dessus de 2000 m environ. Certaines instabilités peuvent encore céder au passage d'un skieur dans les pentes raides, parfois cachées sous une fine couche de neige fraîche. Elles peuvent engendrer des avalanches de taille petite à moyenne (taille 1 à 2). En dessous de 2000 m, la neige fraîche repose sur une sous-couche regelée et plus stable.
**Départs spontanés :** Peu probables avec une couche de neige fraîche trop peu importante pour générer des départs spontanés.
**Autres :** Nombreuses surfaces dures et glacées, pouvant être recouvertes de quelques centimètres de neige fraîche.
Présence de corniches parfois volumineuses, dont certaines commencent à se détacher (apparition de fissures).

## Qualité de la neige

**Qualification de l'enneigement :** L'enneigement est excellent pour la saison au-dessus de 1600 m. Sur la Maniccia, à 2400 m d'altitude dans le massif du Rotondo, on relève 3m15 de hauteur de neige totale.
**Limite d'enneigement skiable :** 1500 à 1600 m selon le versant.
**État de la neige** : Une fine couche de neige fraîche recouvre le plus souvent des croûtes épaisses et les surfaces dures. A haute altitude, dans les pentes N à E, la neige reste froide et assez légère, ou bien densifiée ou durcie sur les zones qui ont été exposées au vent. À noter également la présence de corniches parfois volumineuses.

## Aperçu météo pour le jeudi 26 mars

| | nuit | matin | après-midi | soir |
|---|---|---|---|---|
| | | | | |

Averses de neige fortement ventées. Limite pluie-neige basse le matin, remontant progressivement. Vent molissant au fil de la journée.

| | | | | |
|---|---|---|---|---|
| **Pluie-Neige** | 500 m | 800 m | 900 m | 1 000 m |
| **Iso 0 °C** | 1 000 m | 1 200 m | 1 300 m | 1 400 m |
| **Vent 1500 m** | ↗ 95 km/h | → 50 km/h | ↘ 55 km/h | ↓ 55 km/h |
| **Vent 3000 m** | → 115 km/h | → 60 km/h | ↘ 60 km/h | ↓ 65 km/h |

## Épaisseur de neige hors-piste

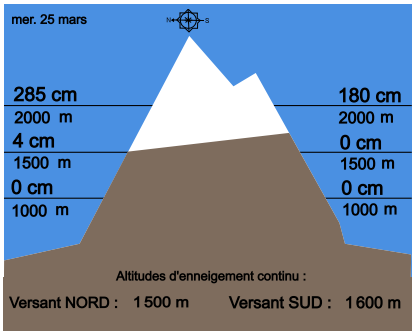


## Précipitations à 1800 m

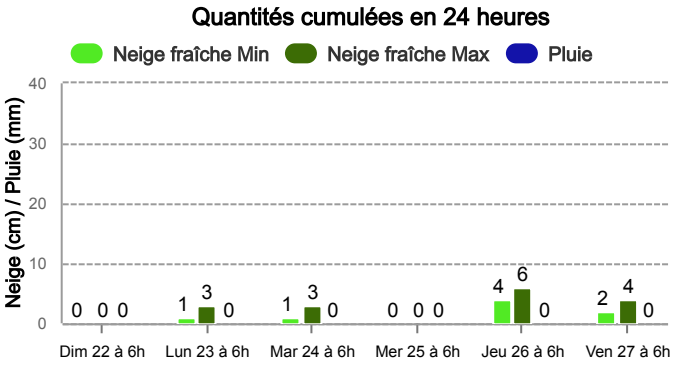


## Tendance du vendredi 27 mars

**Indice de risque limité**

Maintien d'un risque limité.

Pour consulter la vigilance en cours, veuillez vous rendre sur le site https://vigilance.meteofrance.fr/fr

Météo-France - 73 avenue de Paris, 94165 Saint-Mandé cedex - Contact : contact@meteo.fr

Rédigé par Météo-France avec la contribution des observateurs du réseau nivo-météorologiques. Partenariat : ANMSM (Maires de Stations de Montagne), DSF (Domaines Skiables de France), ADSP (Directeurs de Pistes et de la Sécurité des Stations de Sports d'Hiver) et autres acteurs de la montagne.

Bulletin neige & avalanches par téléphone au **0 892 68 10 20** Service 0,35 € / min + prix appel

RÉPUBLIQUE FRANÇAISE
*Liberté Égalité Fraternité*

METEO FRANCE
À VOS CÔTÉS, DANS UN CLIMAT QUI CHANGE

# Bulletin d'estimation du risque d'avalanche

## (valable en dehors des pistes balisées et ouvertes)

# MASSIF : Cinto Rotondo

Rédigé le mercredi 25 mars 2026 à 16h

## Conditions nivo-météo des 7 derniers jours

| | jeu. 19/03 | | | | ven. 20/03 | | | | sam. 21/03 | | | | dim. 22/03 | | | | lun. 23/03 | | | | mar. 24/03 | | | | mer. 25/03 | | | |
|---|---|---|---|---|---|---|---|---|---|---|---|---|---|---|---|---|---|---|---|---|---|---|---|---|---|---|---|---|
| | 03h | 09h | 15h | 21h | 03h | 09h | 15h | 21h | 03h | 09h | 15h | 21h | 03h | 09h | 15h | 21h | 03h | 09h | 15h | 21h | 03h | 09h | 15h | 21h | 03h | 09h | 15h | 21h |
| Météo | | | | | | | | | | | | | | | | | | | | | | | | | | | | |
| Vent (km/h) | 45 | 30 | 50 | 80 | 80 | 80 | 40 | 50 | 50 | 30 | 15 | 20 | 15 | 20 | 15 | 10 | 10 | 15 | 20 | 40 | 30 | 25 | 20 | 20 | 20 | 60 | 80 | 120 |
| à 3000m | | | | | | | | | | | | | | | | | | | | | | | | | | | | |
| Vent (km/h) | 40 | 35 | 20 | 30 | 30 | 30 | 25 | 25 | 25 | 15 | 10 | 10 | 5 | 10 | 5 | 5 | 5 | 10 | 15 | 30 | 5 | 10 | 10 | 10 | 10 | 30 | 65 | 95 |
| à 1500m | | | | | | | | | | | | | | | | | | | | | | | | | | | | |

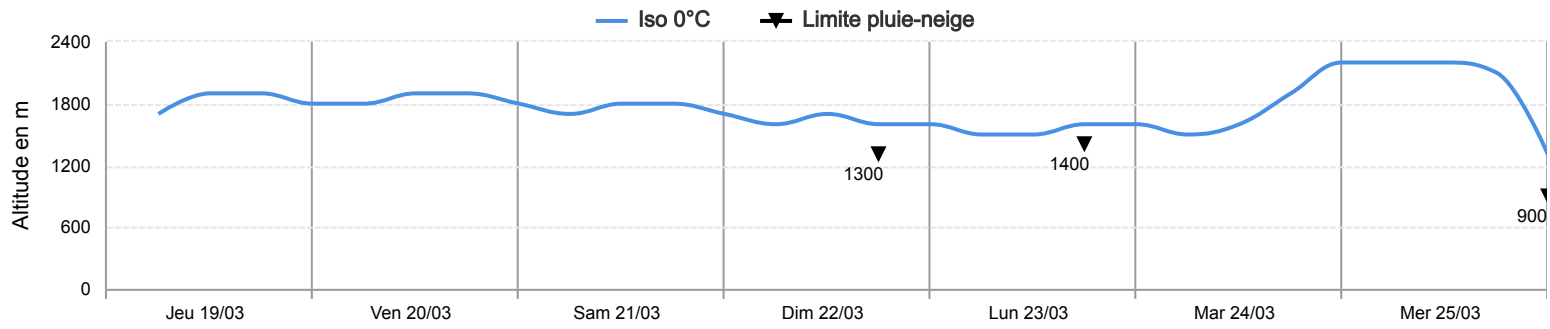


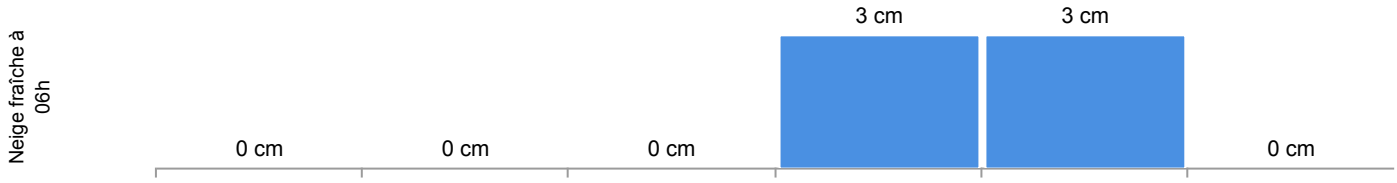


| Risque d'avalanche | jeu. 19/03 | ven. 20/03 | sam. 21/03 | dim. 22/03 | lun. 23/03 | mar. 24/03 | mer. 25/03 |
|---|---|---|---|---|---|---|---|
| | 2 | 2 | 2 | 2 | 2 | 2 | 2 |

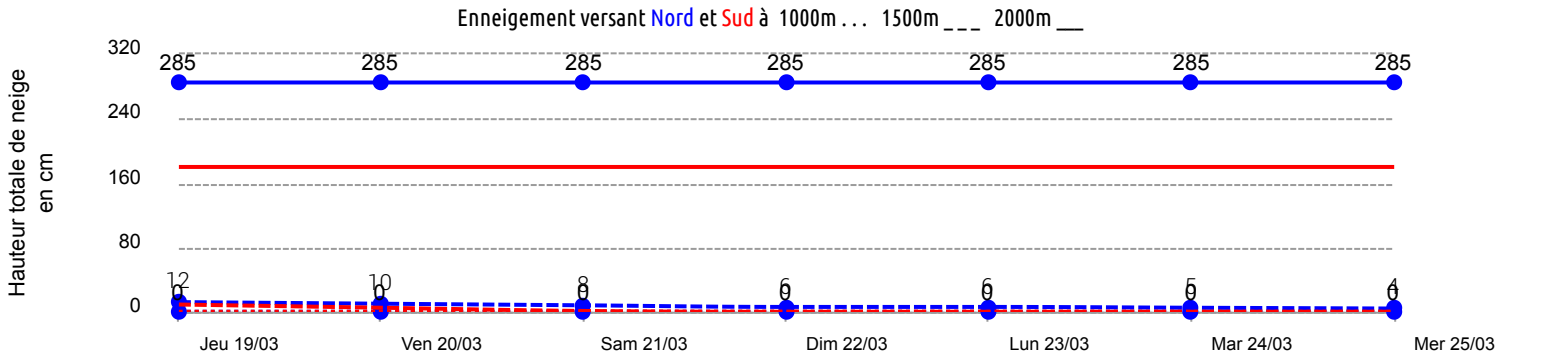


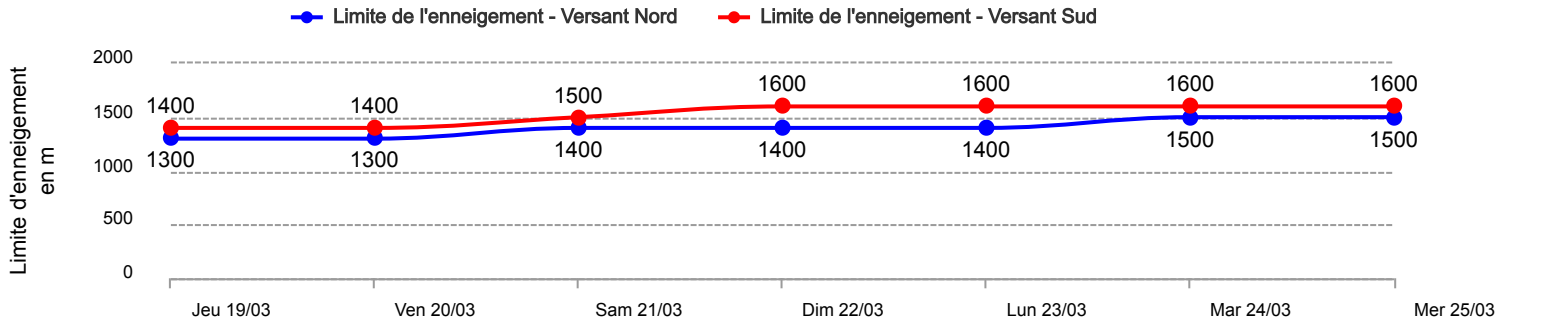


Pour consulter la vigilance en cours, veuillez vous rendre sur le site https://vigilance.meteofrance.fr/fr


Météo-France - 73 avenue de Paris, 94165 Saint-Mandé cedex - Contact : contact@meteo.fr


Bulletin neige & avalanches par téléphone au

0 892 68 10 20 Service 0,35 € / min + prix appel


Rédigé par Météo-France avec la contribution des observateurs du réseau nivo-météorologiques. Partenariat : ANMSM (Maires de Stations de Montagne), DSF (Domaines Skiables de France), ADSP (Directeurs de Pistes et de la Sécurité des Stations de Sports d'Hiver) et autres acteurs de la montagne.