Bulletin d'estimation du risque d'avalanche
(valable en dehors des pistes balisées et ouvertes)

MASSIF : Couserans

Rédigé le mercredi 25 mars 2026 à 16h

Estimation des risques pour le : JEUDI 26 MARS

TRÈS HIVERNAL EN ALTITUDE, QUELQUES PLAQUES À VENT ANCIENNES.

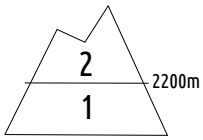

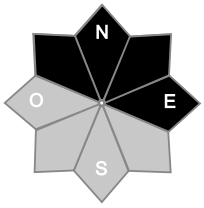

Au-dessus de 2200m indice de risque limité, plus bas indice faible.

Départs spontanés : Rares. Petits départs naturels de poudreuse en couloirs très raides.

Déclenchements provoqués : Anciennes plaques en versants nord sur sous couches fragiles persistantes.

Indices de risque : 5 très fort - 4 fort - 3 marqué - 2 limité - 1 faible -- En noir : les pentes les plus dangereuses

Stabilité du manteau neigeux

Situation avalancheuse typique : couche fragile persistante neige ventée

Déclenchements provoqués :
Quelques structures de plaques remontant à plus d'une semaine sont possiblement présentes, au plus bas vers 2200/2300 m, mais surtout au-delà de 2400/2500 m, reposant sur des couches fragiles persistantes (givres de surface ou neige roulée).
Elles sont localisées dans les pentes sommitales des sommets frontaliers dans un large secteur nord et peuvent être masquées par les petites chutes de neige de la nuit précédente. Elles donnent des avalanches de taille 1 à 2, avec des cassures de 30/40 cm éventuellement possibles.
Observables : neige récente travaillée par le vent, enfoncement des bâtons supérieur à 20/30 cm, fissures devant les skis.

- Le vent associé aux petites chutes de neige de la nuit précédente va également former quelques nouvelles accumulations instables atteignant au maximum 15/20 cm par endroits, déclenchables dans les pentes raides par un skieur. (avalanche de taille 1, pouvant potentiellement entrainer un randonneur sur quelques mètres ou le faire glisser sur l'ancienne neige dure, sans l'ensevelir).

Départs spontanés :
Avec le net refroidissement effectif depuis la nuit précédente, l'activité avalancheuse s'annonce faible. Éventuellement quelques petites avalanches ou coulées mobilisant les 10/15 cm de neige récente accumulés dans des couloirs très raides.

Qualité de la neige

Enneigement :
L'enneigement reste très bon pour la saison, après plusieurs hivers déficitaires.
En altitude, les cumuls sont très conséquents, mais les crêtes et sommets exposés au vent d'ouest à nord-ouest sont parfois complètement déneigés.
On peut encore chausser les skis dans les secteurs ombragés au mieux vers 1500/1600 m.

Qualité de la neige :
Encore un peu de neige dans la nuit de mercredi à jeudi, jusqu'à 5/10 cm de neige légère, pouvant toutefois être facilement balayés par le vent et s'accumuler contre les obstacles.
- Avec le fort refroidissement, bon regel de l'ancien manteau neigeux perdurant toute la journée dans les secteurs protégés des quelques rayons de soleil. Neige très dure, voire glacée dans les secteurs balayés par le vent.

Aperçu météo pour le jeudi 26 mars

	nuit	matin	après-midi	soir

Encore quelques averses de neige en matinée. Du mieux l'après-midi.

	nuit	matin	après-midi	soir
Pluie-Neige	900 m	900 m		
Iso 0 °C	1 300 m	1 300 m	1 700 m	1 200 m
Vent 2000 m	→ 55 km/h	↘ 50 km/h	↘ 50 km/h	↓ 45 km/h
Vent 3000 m	↓ 75 km/h	↓ 75 km/h	↓ 70 km/h	↓ 70 km/h

Épaisseur de neige hors-piste

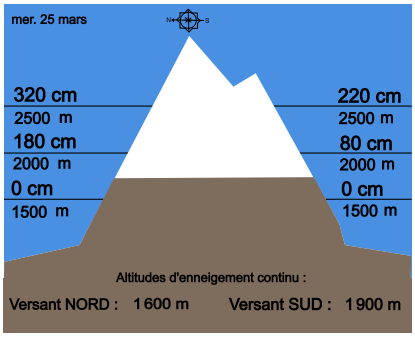

Précipitations à 1800 m

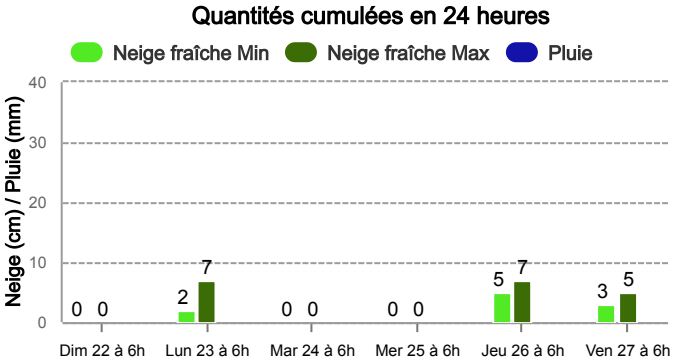

Tendance du vendredi 27 mars

Indice de risque limité

Risque stationnaire.

Pour consulter la vigilance en cours, veuillez vous rendre sur le site https://vigilance.meteofrance.fr/fr

Météo-France - 73 avenue de Paris, 94165 Saint-Mandé cedex - Contact : contact@meteo.fr

Rédigé par Météo-France avec la contribution des observateurs du réseau nivo-météorologiques. Partenariat : ANMSM (Maires de Stations de Montagne), DSF (Domaines Skiables de France), ADSP (Directeurs de Pistes et de la Sécurité des Stations de Sports d'Hiver) et autres acteurs de la montagne.

Bulletin neige & avalanches par téléphone au
0 892 68 10 20 Service 0,35 € / min + prix appel

RÉPUBLIQUE FRANÇAISE
Liberté Égalité Fraternité

METEO FRANCE
À VOS CÔTÉS, DANS UN CLIMAT QUI CHANGE

Bulletin d'estimation du risque d'avalanche

(valable en dehors des pistes balisées et ouvertes)

MASSIF : Couserans

Rédigé le mercredi 25 mars 2026 à 16h

Conditions nivo-météo des 7 derniers jours

	jeu. 19/03				ven. 20/03				sam. 21/03				dim. 22/03				lun. 23/03				mar. 24/03				mer. 25/03			
	03h	09h	15h	21h	03h	09h	15h	21h	03h	09h	15h	21h	03h	09h	15h	21h	03h	09h	15h	21h	03h	09h	15h	21h	03h	09h	15h	21h
Météo																												
Vent (km/h)	40	35	30	20	15	20	20	15	20	15	20	15	20	25	40	50	40	30	30	20	20	15	15	15	25	35	55	75
à 3000m	↑	↑	↑	↑	↙	↙	←	↓	↓	↙	↘	↘	↓	↓	↓	↓	↓	↓	↓	↓	↓	↙	↓	↘	↓	↓	↓	↓
Vent (km/h)	30	25	20	10	10	10	10	15	10	10	15	10	10	15	30	35	30	20	20	10	10	10	10	10	10	20	40	55
à 2000m	↑	↑	↗	↑	↙	↙	←	↓	↓	↙	↘	↘	↗	→	↘	↘	→	↙	↘	↓	↓	↙	↘	↑	↗	→	↘	↘

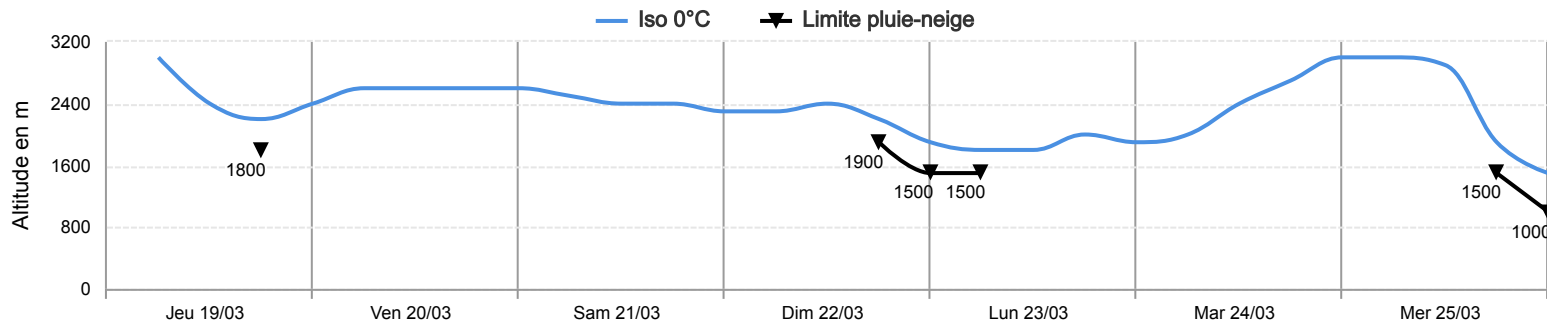

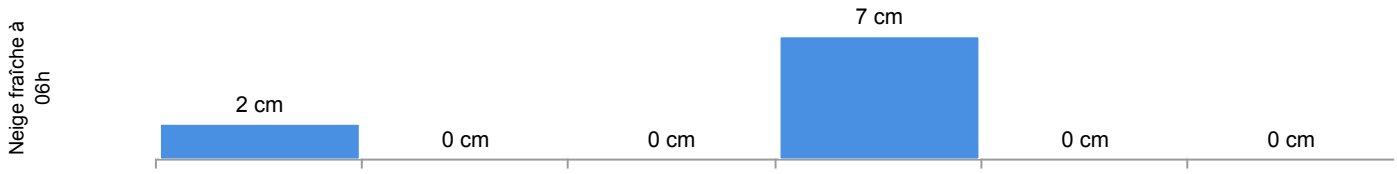

Risque d'avalanche	jeu. 19/03	ven. 20/03	sam. 21/03	dim. 22/03	lun. 23/03	mar. 24/03	mer. 25/03
	2	2	2	2	3	2	2

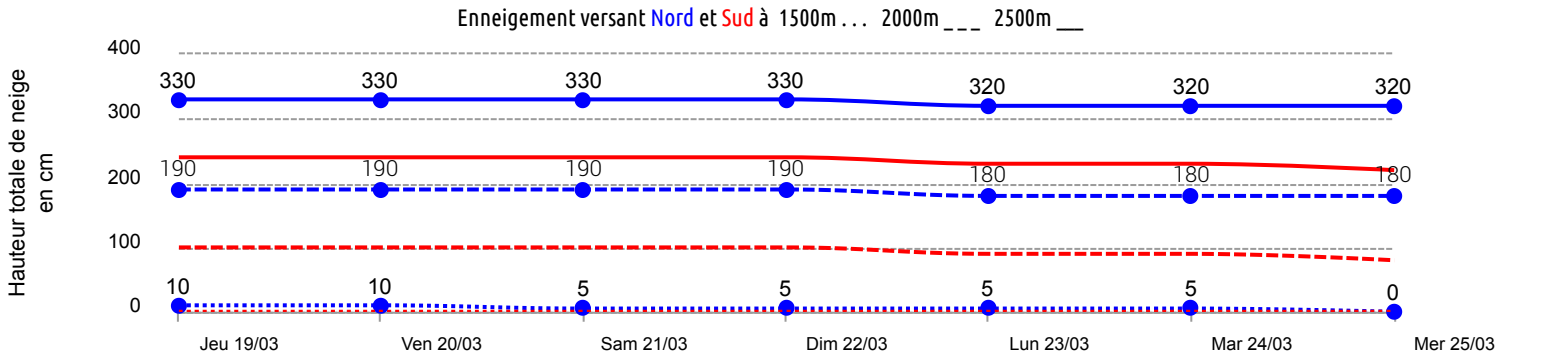

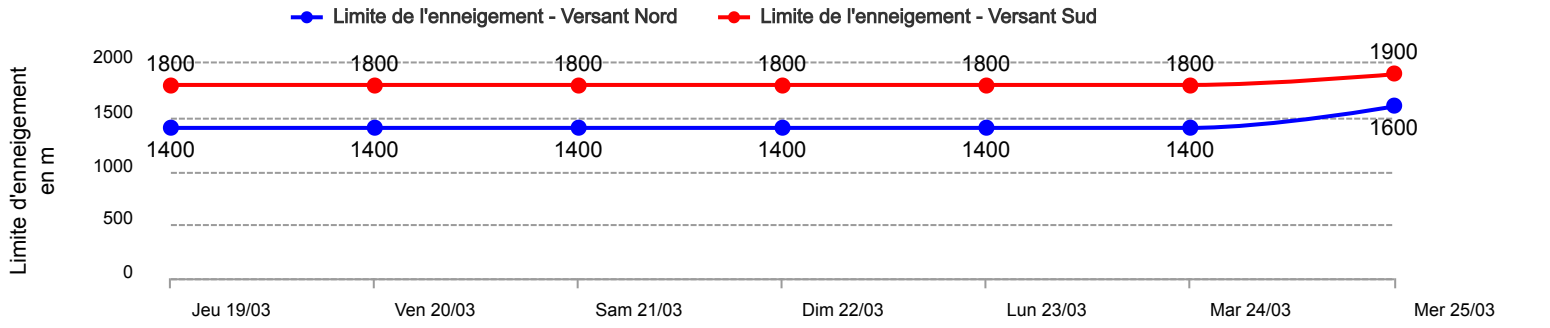

Pour consulter la vigilance en cours, veuillez vous rendre sur le site https://vigilance.meteofrance.fr/fr

Météo-France - 73 avenue de Paris, 94165 Saint-Mandé cedex - Contact : contact@meteo.fr

Rédigé par Météo-France avec la contribution des observateurs du réseau nivo-météorologiques. Partenariat : ANMSM (Maires de Stations de Montagne), DSF (Domaines Skiables de France), ADSP (Directeurs de Pistes et de la Sécurité des Stations de Sports d'Hiver) et autres acteurs de la montagne.

Bulletin neige & avalanches par téléphone au
0 892 68 10 20
Service 0,35 € / min + prix appel